PDAD 2021

PESQUISA DISTRITAL POR AMOSTRA DE DOMICÍLIOS

RELATÓRIO CODEPLAN

PLANO PILOTO
ASA NORTE

codeplan

GOVERNO DO DISTRITO FEDERAL

Ibaneis Rocha Barros Junior

Governador

Paco Britto

Vice-Governador

SECRETARIA DE ESTADO DE FAZENDA, PLANEJAMENTO, ORÇAMENTO E GESTÃO DO DISTRITO FEDERAL – SEFP

José Itamar Feitosa

Secretário

COMPANHIA DE PLANEJAMENTO DO DISTRITO FEDERAL – CODEPLAN

Jeansley Lima

Presidente

Sônia Gontijo Chagas Gonzaga

Diretora Administrativo e Financeiro

Clarissa Jahns Schlabitz

Diretora de Estudos e Pesquisas Socioeconômicas

Daienne Amaral Machado

Diretora de Estudos e Políticas Sociais

Renata Florentino de Faria Santos

Diretora de Estudos Urbanos e Ambientais

Brasília – DF

2022

Atualizado em 09/07/2022

codeplan

COMPANHIA DE PLANEJAMENTO DO DISTRITO FEDERAL

EQUIPE TÉCNICA

DIRETORIA DE ESTUDOS E PESQUISAS SOCIOECONÔMICAS – DIEPS

Clarissa Jahns Schlabitz
Diretora

Thiago Mendes Rosa
Chefe de Gabinete

Simone de Araújo Carvalho
Assistente

GERÊNCIA DE PESQUISAS SOCIOECONÔMICAS – GEREPS

Jusçanio Umbelino de Souza
Gerente de Pesquisas Socioeconômicas

Luiz Rubens Câmara de Araújo
Assistente I

Talia Alves Xavier
Estagiária

Ingrid Stefani Rocha Quirino
Estagiária

Janemercure Oliveira de Souza
Estagiária

NÚCLEO DE PESQUISAS SOCIOECONÔMICAS – NUSOC

José Douglas de Queiroz
Chefe do núcleo

Danilo Camargos
Supervisor

Erivaldo da Fonseca Barbosa
Supervisor

Regina Célia Alves
Supervisora

Alfredo Caetano Valadão Neto
Pesquisador

Ana Lídia de C. Borges Valadão
Pesquisadora

Antônio Humberto F. de Souza
Pesquisador

Antônio Pereira de A. Filho
Pesquisador

Dwahyny Krieger K. de Oliveira
Pesquisador

Eder Tolentino da Silva
Pesquisador

Eline Sousa Lima
Pesquisador

Gean Dores Silveira Araújo
Pesquisador

Gilberto Coelho Borges
Pesquisador

Gilberto Luna dos Santos
Pesquisador

Guiomar Ribeiro de Araújo Silva
Pesquisador

Jacira Roberto dos Santos
Pesquisadora

Josias Laurentino de Sousa
Pesquisador

Lucienny Santos Guimarães
Pesquisadora

Lucimar Batista Pereira
Pesquisadora

Luiz Ricardo Jeanz
Pesquisador

Magda Maria dos Santos
Pesquisadora

Márcia da Silva
Pesquisadora

Marcos Maciel Ribeiro
Pesquisador

Maria de Lourdes de Jesus Silva
Pesquisadora

Paulo Henrique de Paiva
Pesquisador

Rosália Maria Costa Souza
Pesquisadora

Tereza Christina do Amaral
Pesquisadora

Léia Oliveira de Lima
Apoio

Maria Edna P. Medeiros
Apoio

Paulo Rogério Azevedo Andrade
Apoio

Telma Maria de Lima
Apoio

Wallas Amancio Alves
Apoio

GERÊNCIA DE CIÊNCIA DE DADOS, GEOINFORMAÇÃO, DEMOGRAFIA E ESTATÍSTICA – GEGED

Letícia Pacheco dos Passos Claro
Gerente de Ciencia de Dados, Geoinformação, Demografia e Estatística (GEGED) – A partir de abril/2022

Alexandre Silva dos Santos
Gerente da GEDEG (até setembro/2021)

Tais Alves de Oliveira
Assistente I

Elias Mangueira Lopes
Assistente I

Jeferson Lucas Macêdo do Amaral
Assistente I

Lucas Cardoso Cherigath
Assistente I

NÚCLEO DE ESTATÍSTICA – NUEST

Miriam Francisca Silva Chaves Ferreira
Estatística

Frederico Lara de Souza
Estatístico

Alessandra Analu Moreira da Silva
Estatística

Artur Carvalho de Medeiros
Estagiário

Carlo Alesandr Rosano de Almeida
Estagiário

NÚCLEO DE GEOINFORMAÇÃO – NUGEO

Patrícia Pereira Alves da Silva
Assistente I

DIRETORIA DE ESTUDOS E POLÍTICAS SOCIAIS – DIPOS

Daienne Amaral Machado
Diretora

Diego Rodrigues de Loiola
Estagiário

GERÊNCIA DE PESQUISA E ESTUDOS QUANTITATIVOS DE POLÍTICAS SOCIAIS – GEPAQ

Julia Modesto Pinheiro Dias Pereira
Gerente

Francisca de Fátima de Araújo Lucena
Pesquisadora

Acsa Rodrigues Ferreira Guimarães
Pesquisadora

GERÊNCIA DE PESQUISA E ESTUDOS QUALITATIVOS DE POLÍTICAS SOCIAIS – GEAQL

Elisete Rodrigues de Souza
Pesquisadora

NÚCLEO DE ESTUDOS DE POPULAÇÃO – NEP

Mônica Oliveira Marques França
Chefe do núcleo

DIRETORIA DE ESTUDOS URBANOS E AMBIENTAIS – DEURA

Renata Florentino de Faria Santos
Diretora

GERÊNCIA DE ESTUDOS AMBIENTAIS – GEAM

Kassia Castro
Gerente

GERÊNCIA DE ESTUDOS URBANOS, REGIONAIS E METROPOLITANOS – GEURB

Cecília de Faria Sampaio
Gerente

Alda Dutra Duarte Weigand
Assistente

Clara Wanderley Gonçalves
Estagiária

Gleicilene dos Santos Martins
Estagiária

Coleta de dados
VR consultoria

Checagem de dados
Ágora Pesquisa

Editoração Eletrônica
DIEPS

codeplan
COMPANHIA DE PLANEJAMENTO DO DISTRITO FEDERAL

Sumário

APRESENTAÇÃO **1**

1 INTRODUÇÃO **3**

2 METODOLOGIA **5**

2.1 Definição da área pesquisada 6
2.2 A amostra 8
2.3 Caracterização da Unidade de Planejamento Territorial (UPT) Central 12
2.4 Breve histórico e características da RA Plano Piloto 13

3 RESULTADOS – MORADORES **19**

3.1 Caracterização da população urbana 19
3.2 Migração 24
3.3 Saúde 27
3.4 Comunicação 33
3.5 Escolaridade 38
3.6 Trabalho 47
3.7 Rendimento 57

4 RESULTADOS – DOMICÍLIOS **62**

4.1 Características dos domicílios 62
4.2 Infraestrutura domiciliar 65
4.3 Infraestrutura urbana nas proximidades dos domicílios 72
4.4 Serviços domiciliares e inventário de bens duráveis 76
4.5 Localidades predominantes de compras 82
4.6 Animais de estimação 84
4.7 Segurança alimentar 85

5 CONSIDERAÇÕES FINAIS **87**

ANEXOS **88**

Tabelas relacionadas aos moradores 88
Tabelas relacionadas aos domicílios 111

Lista de Figuras

2.1.1 Região de interesse da PDAD 2021 7
2.3.1 Unidades de Planejamento Territorial com destaque para as RA que compõem a UPT Central Adjacente 1 12
2.4.1 Área de cobertura do Plano Piloto na PDAD 2021 18
3.1.1 Distribuição da população por faixas de idade e sexo, Asa Norte, 2021 19
3.1.2 Distribuição da população por arranjos domiciliares, Asa Norte, 2021 20
3.1.3 Distribuição da população por sexo, Asa Norte, 2021 20
3.1.4 Orientação sexual das pessoas com 18 anos ou mais, Asa Norte, 2021 21
3.1.5 Distribuição da população por raça/cor da pele, Asa Norte, 2021 22
3.1.6 Distribuição da população por estado civil (14 anos ou mais), Asa Norte, 2021 23
3.1.7 Pessoas com 18 anos ou mais que possuíam CNH, Asa Norte, 2021 23
3.2.1 Principais estados de nascimento das pessoas que vieram de fora do DF, Asa Norte, 2021 24
3.2.2 Distribuição da motivação do responsável do domicílio a mudar e/ou retornar à capital federal, Asa Norte, 2021 25
3.2.3 Intenção e localidade para constituição de novo domicílio nos próximos 12 meses das pessoas de 14 anos ou mais, Asa Norte, 2021 26
3.3.1 Distribuição da população segundo grau de dificuldade para enxergar, ouvir, caminhar ou subir degraus, limitação nas funções mentais ou dificuldade para pegar pequenos objetos, Asa Norte, 2021 28
3.3.2 Distribuição das pessoas com plano de saúde, por tipo de cobertura, Asa Norte, 2021 29
3.3.3 Último serviço de saúde utilizado, Asa Norte, 2021 30
3.3.4 Motivo do atendimento de saúde, Asa Norte, 2021 31
3.3.5 Localidade de atendimento do último serviço de saúde utilizado, Asa Norte, 2021 32
3.4.1 Posse de celular e tablet para uso pessoal, Asa Norte, 2021 . . . 33

3.4.2 Posse de linha pré-paga e pós-paga para uso pessoal, Asa Norte, 2021 34
3.4.3 Acesso à internet e meios de acesso nos últimos três meses, Asa Norte, 2021 35
3.4.4 Meios de acesso nos últimos três meses, Asa Norte, 2021 36
3.4.5 Motivações do acesso à internet, Asa Norte, 2021 37
3.5.1 População com seis anos ou mais de idade que declararam saber ler e escrever, Asa Norte, 2021 38
3.5.2 Distribuição da frequência escolar da população entre 4 e 24 anos, Asa Norte, 2021 39
3.5.3 Distribuição da modalidade de ensino de todos os estudantes, Asa Norte, 2021 40
3.5.4 Distribuição do turno de estudo de todos os estudantes, Asa Norte, 2021 41
3.5.5 Distribuição da frequência escolar por faixas de idade, Asa Norte, 2021 42
3.5.6 Região Administrativa/Município da unidade de estudo, Asa Norte, 2021 43
3.5.7 Principal meio de transporte da casa até a escola de todos os estudantes, Asa Norte, 2021 44
3.5.8 Tempo de deslocamento da casa até a escola de todos os estudantes, Asa Norte, 2021 45
3.5.9 Escolaridade da população com 25 anos ou mais, Asa Norte, 2021 46
3.6.1 Taxa de participação das pessoas em idade ativa (14 anos ou mais de idade), Asa Norte, 2021 47
3.6.2 População de 18 a 29 anos por situação de trabalho e estudo, Asa Norte, 2021 48
3.6.3 Local onde as pessoas exerciam seu trabalho principal, Asa Norte, 2021 49
3.6.4 Distribuição do setor de atividade da empresa em que as pessoas exerciam seu trabalho principal, Asa Norte, 2021 50
3.6.5 Distribuição da posição na ocupação principal, Asa Norte, 2021 51
3.6.6 Área de atuação e modalidade de contratação dos servidores/empregados públicos, Asa Norte, 2021 52
3.6.7 Empreendedores segundo cadastro de Microempreendedores Individuais (MEI) e Cadastro Nacional de Pessoa Jurídica (CNPJ), Asa Norte, 2021 53

3.6.8 Meios de transporte utilizados para deslocamento até o trabalho principal, Asa Norte, 2021 54
3.6.9 Tempo para deslocamento até o trabalho principal, Asa Norte, 2021 55
3.6.10 Distribuição dos assalariados privados segundo posse de carteira de trabalho assinada (CTPS) e contribuição ao INSS, Asa Norte, 2021 56
3.7.1 Distribuição do rendimento bruto do trabalho principal por faixas de salário mínimo, Asa Norte, 2021 58
3.7.2 Curva de Lorenz do rendimento bruto do trabalho principal, Asa Norte, 2021 59
3.7.3 Distribuição do rendimento domiciliar por faixas de salário mínimo, Asa Norte, 2021 60
3.7.4 Curva de Lorenz do rendimento domiciliar, Asa Norte, 2021 . . 61
4.1.1 Distribuição dos domicílios ocupados segundo a espécie, Asa Norte, 2021 62
4.1.2 Distribuição dos domicílios ocupados segundo o tipo, Asa Norte, 2021 63
4.1.3 Distribuição dos domicílios ocupados e próprios segundo a condição de ocupação, Asa Norte, 2021 64
4.1.4 Distribuição dos domicílios ocupados segundo a regularização do lote, Asa Norte, 2021 64
4.2.1 Distribuição dos domicílios ocupados segundo material predominante nas paredes externas, Asa Norte, 2021 65
4.2.2 Distribuição dos domicílios ocupados segundo material predominante no piso, Asa Norte, 2021 66
4.2.3 Distribuição dos domicílios ocupados segundo material predominante na cobertura (telhado), Asa Norte, 2021 67
4.2.4 Abastecimento de água no domicílio, Asa Norte, 2021 68
4.2.5 Esgotamento sanitário do domicílio, Asa Norte, 2021 69
4.2.6 Abastecimento de energia elétrica no domicílio, Asa Norte, 2021 70
4.2.7 Recolhimento do lixo no domicílio, Asa Norte, 2021 71
4.3.1 Infraestrutura urbana na rua de acesso dos domicílios, Asa Norte, 2021 72
4.3.2 Problemas nas cercanias do domicílio, Asa Norte, 2021 73
4.3.3 Infraestrutura urbana nas cercanias do domicílio, Asa Norte, 2021 74

4.3.4 Segurança nas proximidades do domicílio, Asa Norte, 2021 . . 75
4.4.1 Contratação de serviços pelos domicílios, Asa Norte, 2021 . . . 76
4.4.2 Modalidades de acesso à internet no domicílio, Asa Norte, 2021 77
4.4.3 Posse de veículos no domicílio, Asa Norte, 2021 78
4.4.4 Inventário de bens duráveis dos domicílios, Asa Norte, 2021 . . 79
4.4.5 Inventário de bens duráveis dos domicílios (Continuação), Asa Norte, 2021 80
4.4.6 Utilização de serviços domésticos nos domicílios, Asa Norte, 2021 81
4.5.1 Locais predominantes de compra de artigos de alimentação, higiene e limpeza, eletrodomésticos, material de construção/manutenção e serviços em geral, Asa Norte, 2021 83
4.6.1 Existência de gatos, cachorros, aves, peixes ou outros animais domésticos no domicílio, Asa Norte, 2021 84
4.7.1 Distribuição dos domicílios por situação de segurança alimentar nos últimos 3 meses, Asa Norte, 2021 86

Lista de Tabelas

2.2.1 Amostra da PDAD 2021 por localidade 9
A.1 População por faixa etária e sexo, Asa Norte, 2021 88
A.2 Arranjos domiciliares, Asa Norte, 2021 88
A.3 População por sexo, Asa Norte, 2021 89
A.4 Orientação sexual das pessoas com 18 anos ou mais, Asa Norte, 2021 89
A.5 População com 18 anos ou mais segundo identificação LGBTQIA+, Asa Norte, 2021 89
A.6 Pessoas com 18 anos ou mais que possuíam CNH, Asa Norte, 2021 89
A.7 População por raça/cor da pele, Asa Norte, 2021 90
A.8 Estado civil das pessoas com 14 anos ou mais de idade, Asa Norte, 2021 90
A.9 Pessoas nascidas no DF, Asa Norte, 2021 90
A.10 Estado de nascimento das pessoas que vieram de fora do DF, Asa Norte, 2021 91
A.11 Motivação do chefe do domicílio a mudar e/ou retornar para o DF, Asa Norte, 2021 92
A.12 Intenção e localidade para constituição de novo domicílio das pessoas de 14 anos ou mais, Asa Norte, 2021 92
A.13 Pessoas com dificuldade permanente de enxergar, Asa Norte, 2021 93
A.14 Pessoas com dificuldade permanente de ouvir, Asa Norte, 2021 93
A.15 Pessoas com dificuldade permanente de caminhar ou subir degraus, Asa Norte, 2021 93
A.16 Pessoas com deficiência mental/intelectual permanente, Asa Norte, 2021 94
A.17 Pessoas com dificuldade permanente para pegar pequenos objetos, Asa Norte, 2021 94
A.18 Pessoas com plano de saúde privado, Asa Norte, 2021 94
A.19 Tipo de plano de saúde privado, Asa Norte, 2021 94
A.20 Planos de saúde privado com coparticipação e/ou franquia, Asa Norte, 2021 95
A.21 Último serviço de saúde utilizado, Asa Norte, 2021 95
A.22 Motivo de atendimento de saúde utilizado da última vez, Asa Norte, 2021 96

A.23 Localidade do atendimento do último serviço de saúde utilizado, Asa Norte, 2021 96
A.24 Posse de celular para uso pessoal, Asa Norte, 2021 97
A.25 Posse de tablet para uso pessoal, Asa Norte, 2021 97
A.26 Posse de linha pré-paga uso pessoal, Asa Norte, 2021 97
A.27 Posse de linha pós-paga uso pessoal, Asa Norte, 2021 97
A.28 Acesso à internet nos últimos três meses, Asa Norte, 2021 . . . 98
A.29 Frequência de acesso à internet nos últimos três meses, Asa Norte, 2021 98
A.30 Acesso à internet por meio de microcomputador/laptop, Asa Norte, 2021 98
A.31 Acesso à internet por meio de celular/tablet, Asa Norte, 2021 . . 98
A.32 Acesso à internet por outro meio, Asa Norte, 2021 99
A.33 Acesso à internet por motivo de trabalhar (pessoas com 14 anos ou mais), Asa Norte, 2021 99
A.34 Acesso à internet por motivo de educação/cursos, Asa Norte, 2021 99
A.35 Acesso à internet por motivo de informações/notícias, Asa Norte, 2021 99
A.36 Acesso à internet por motivo de criação/compartilhamento de conteúdo, Asa Norte, 2021 99
A.37 Acesso à internet por motivo de multimídia (lazer e cultura), Asa Norte, 2021 100
A.38 Acesso à internet por motivo de comunicação, Asa Norte, 2021 100
A.39 Acesso à internet por motivo de transações financeiras/comerciais, Asa Norte, 2021 100
A.40 Pessoas com cinco anos ou mais que sabem ler e escrever, Asa Norte, 2021 101
A.41 Frequência escolar da população entre 4 e 24 anos, Asa Norte, 2021 101
A.42 Modalidade de ensino dos estudantes, Asa Norte, 2021 101
A.43 Turno de estudo dos alunos, Asa Norte, 2021 102
A.44 Frequência escolar, por faixa de idade, Asa Norte, , 2021 102
A.45 Região Administrativa/Município da unidade de estudo, Asa Norte, 2021 102
A.46 Principal meio de transporte da casa até a unidade de ensino, Asa Norte, 2021 103

A.47 Tempo de deslocamento utilizado até a unidade de ensino, Asa Norte, 2021 103
A.48 Escolaridade das pessoas com 25 anos ou mais de idade, Asa Norte, 2021 103
A.49 Distribuição da população em idade ativa (PIA - 14 anos ou mais), segundo situação de atividade, Asa Norte, 2021 104
A.50 Distribuição da população economicamente ativa (PEA - 14 anos ou mais), segundo situação de ocupação, Asa Norte, 2021 104
A.51 Distribuição da população economicamente ativa (PEA - 14 anos ou mais), segundo situação de ocupação, Asa Norte, 2021 104
A.52 Pessoas entre 18 e 29 anos por situação de trabalho e estudo, Asa Norte, 2021 104
A.53 Pessoas entre 18 e 29 anos por situação de trabalho, estudo e procura por trabalho nos últimos 30 dias, Asa Norte, 2021 105
A.54 Região Administrativa de exercício do trabalho principal, Asa Norte, 2021 105
A.66 Rendimento bruto do trabalho principal em faixas de salário mínimo, Asa Norte, 2021 105
A.55 Setor de atividade das pessoas ocupadas, Asa Norte, 2021 . . . 107
A.56 Posição na ocupação do trabalho principal, Asa Norte, 2021 . . 107
A.57 Área de atuação dos servidores/empregados públicos, Asa Norte, 2021 107
A.58 Modalidade de contratação dos servidores/empregados públicos, Asa Norte, 2021 108
A.59 Sócios de cooperativas, autônomos, empregadores, donos de negócios familiares e profissionais liberais que eram Microempreendedores Individuais (MEI), Asa Norte, 2021 108
A.60 Sócios de cooperativas, autônomos, empregadores, donos de negócios familiares e profissionais liberais que possuíam CNPJ, Asa Norte, 2021 108
A.61 Meios de transporte para o trabalho principal, Asa Norte, 2021 . 109
A.62 Principal meio de transporte utilizado para o trabalho principal, Asa Norte, 2021 109
A.63 Tempo de deslocamento até o trabalho principal, Asa Norte, 2021109
A.64 Pessoas com carteira de trabalho assinada pelo atual empregador no trabalho principal, Asa Norte, 2021 110

A.65 Pessoas que contribuem com a previdência pública, Asa Norte, 2021 110
A.67 Rendimento bruto domiciliar por faixas de salário mínimo, Asa Norte, 2021 110
A.68 Domicílios ocupados segundo a espécie, Asa Norte, 2021 111
A.69 Domicílios ocupados segundo o tipo, Asa Norte, 2021 111
A.70 Domicílios ocupados segundo a situação de ocupação, Asa Norte, 2021 111
A.71 Domicílios ocupados segundo regularização do lote, Asa Norte, 112
A.72 Material predominante nas paredes externas do domicílio, Asa Norte, 2021 112
A.73 Material predominante no piso do domicílio, Asa Norte, 2021 . . 112
A.74 Material predominante na cobertura (telhado) do domicílio, Asa Norte, 2021 112
A.75 Abastecimento de água no domicílio, Asa Norte, 2021 113
A.76 Esgotamento sanitário do domicílio, Asa Norte, 2021 113
A.77 Abastecimento de energia elétrica no domicílio, Asa Norte, 2021 113
A.78 Recolhimento do lixo no domicílio, Asa Norte, 2021 114
A.79 Infraestrutura urbana na rua de acesso dos domicílios, Asa Norte, 2021 114
A.80 Qualidade da calçada, Asa Norte, 2021 114
A.81 Problemas nas cercanias do domicílio, Asa Norte, 2021 115
A.82 Infraestrutura urbana e equipamentos públicos nas cercanias do domicílio, Asa Norte, 2021 115
A.83 Segurança nas proximidades do domicílio, Asa Norte, 2021 . . . 115
A.84 Contratação de serviços pelos domicílios, Asa Norte, 2021 116
A.85 Acesso à internet no domicílio, Asa Norte, 2021 116
A.86 Tipo de acesso à internet no domicílio, Asa Norte, 2021 116
A.87 Posse de veículos no domicílio, Asa Norte, 2021 116
A.88 Inventário de bens duráveis dos domicílios, Asa Norte, 2021 . . 117
A.89 Utilização de serviços domésticos nos domicílios, Asa Norte, 2021 117
A.90 Frequência mensal da utilização de serviço doméstico do tipo diarista, Asa Norte, 2021 118
A.91 Locais predominantes de compra de artigos de alimentação, higiene e limpeza, Asa Norte, 2021 119
A.92 Locais predominantes de compra de artigos de eletrodomésticos, Asa Norte, 2021 119

A.93 Locais predominantes de compra de material de construção/manutenção, Asa Norte, 2021 120
A.94 Locais predominantes de compra de material de serviços em geral (exceto limpeza doméstica), Asa Norte, 2021 120
A.95 Existência de gatos, cachorros, aves, peixes ou outros animais domésticos no domicílio, Asa Norte, 2021 121
A.96 Distribuição dos domicílios por situação de segurança alimentar nos últimos 3 meses, Asa Norte, 2021 122

APRESENTAÇÃO

A Companhia de Planejamento do Distrito Federal (Codeplan) realiza a Pesquisa Distrital por Amostra de Domicílios – PDAD – a cada dois anos, em conformidade com o decreto nº 39.403, de 26 de outubro de 2018[1]. A PDAD é uma das principais pesquisas da Codeplan, sendo fundamental para o planejamento e o acompanhamento de políticas públicas do Governo do Distrito Federal (GDF), pois é a única a fornecer informações representativas para cada uma das 33 Regiões Administrativas da capital federal.

A última edição da PDAD foi realizada em 2018, tendo sua atualização originalmente programada para 2020. Sua metodologia estabelece visitas presenciais aos domicílios amostrados para realização das entrevistas e coleta das informações. Entretanto, em virtude da pandemia da Covid-19, declarada pela Organização Mundial da Sáude (OMS) em março de 2020[2], uma série de restrições, necessárias ao enfrentamento da crise sanitária, impediram a realização da pesquisa, sendo esta postergada para 2021. O adiamento foi fundamental para que todos os protocolos de combate a pandemia fossem observados, permitindo, desse modo, a realização da coleta com segurança tanto para os pesquisadores quanto para população.

A PDAD 2021, como de costume, investigou aspectos demográficos, de migração, condições sociais e econômicas, situações de trabalho e renda, características do domicílio, condições de infraestrutura urbana, entre outras informações, de modo a oferecer um amplo e circunspecto diagnóstico da situação atual da nossa cidade. Sua periodicidade bianual possibilita um acompanhamento longitudinal de diversos indicadores, proporcionando uma análise das mudanças das condições de vida da população brasiliense. Esta mais recente edição da pesquisa contou com novidades no seu questionário, trazendo investigações inéditas, como identidade de gênero e orientação sexual para maiores de 18 anos, a existência de animais domésticos nos domicílios e questões relacionadas à segurança alimentar.

Outra novidade foi que, com a aprovação da Lei Complementar nº 958, de

[1] Disponível em: <http://www.sinj.df.gov.br/sinj/Norma/263191b1f8e5483180dc52c2cde50b4c/Decreto_39403_29_10_2018.html>

[2] <https://www.euro.who.int/en/health-topics/health-emergencies/coronavirus-covid-19/novel-coronavirus-2019-ncov>

20 de dezembro de 2019[3], o Distrito Federal passou a contar com os limites físicos de todas as suas 33 Regiões Administrativas (RAs), o que faz desta a primeira edição da PDAD a ser realizada com todas as poligonais definidas em Lei. Até a última edição, a legislação vigente à época dividia o território do Distrito Federal em 19 Regiões, enquanto, administrativamente, existiam 31 RAs[4]. Com isso, a PDAD 2021 ganhou, desde o seu planejamento, uma importante atualização.

Apresentaremos os resultados em 44 relatórios, sendo um para o Distrito Federal e os demais para cada uma das 43 localidades. A divulgação ocorrerá por etapas, conforme calendário definido pela Companhia, iniciando-se pelo relatório do Distrito Federal. A medida que os relatórios forem divulgados, eles serão disponibilizados no site da Codeplan (<https://www.codeplan.df.gov.br/pdad>) e, ao final, os microdados e toda a documentação associada à pesquisa serão disponibilizados no mesmo local. Esperamos que a PDAD contribua para o planejamento da nossa cidade e que seja amplamente utilizada pela sociedade brasiliense.

[3] Disponível em: <http://www.sinj.df.gov.br/sinj/Norma/0503ee8e9efd40eca1ffd183d4b50fd0/Lei_Complementar_958_20_12_2019.html>

[4] A Codeplan, para fins de pesquisa, utilizava uma delimitação que, posteriormente, culminou nas delimitações oficiais.

1 INTRODUÇÃO

A Pesquisa Distrital por Amostra de Domicílios (PDAD) 2021 contou com uma amostra de 30.888 domicílios efetivamente entrevistados, localizados majoritariamente em áreas urbanas do Distrito Federal, além de áreas rurais com características de interesse da Codeplan (em geral, áreas urbanizadas e com maior densidade populacional). A coleta dos dados ocorreu entre os dias 5 de maio e 22 de dezembro de 2021, tendo uma duração aproximada de sete meses e meio.

Com a PDAD, é possível traçar o perfil socioeconômico a população-alvo das 33 Regiões Administrativas do Distrito Federal, incluindo condições de moradia e acesso à infraestrutura urbana. Para algumas regiões, como Plano Piloto, Taguatinga, Planaltina, São Sebastião, SCIA/Estrutural, Jardim Botânico e Vicente Pires, informações para recortes territoriais ainda mais específicos estão disponíveis.

O desenvolvimento da PDAD envolve diversas etapas, que podem ser dividas em três categorias: pré-campo, campo e pós-campo. Todas as etapas da PDAD são submetidas ao Conselho Consultivo da PDAD, tendo sua execução companhada pelos conselheiros[5]. As atividades pré-campo envolvem as etapas de planejamento da pesquisa, que se inicia com a atualização dos cadastros de endereçamento dos domicílios, a definição da área de abrangência e o dimensionamento da amostra. Ainda nesta fase, elabora-se o questionário, sendo este amplamente discutido pelas áreas finalísticas da Codeplan e secretarias do GDF, concomitante à confecção do manual da pesquisa. Com o cronograma de campo definido, efetua-se a contratação do serviço de coleta a qual, na edição de 2021, foi realizada pela empresa VR Cosultoria – Gestão Empresarial. No que tange às atividades de campo, realiza-se o pré-teste do questionário e as últimas validações do coletor eletrônico, para, então, executar uma pesquisa piloto. Todas as informações da pesquisa piloto são analisadas, os ajustes necessários são efetuados para, enfim, iniciar a coleta que efetivamente fará parte da pesquisa. Durante a fase de coleta, a Codeplan contratou uma empresa – Ágora Pesquisa – para checar cerca de 25% da amostra coletada, tendo como intenção assegurar a qualidade das informações pesquisadas. Finalmente, na fase pós-coleta, são realizadas as

[5] A portaria que institui o Conselho Consultivo da PDAD está disponível em: <https://www.dodf.df.gov.br/index/visualizar-arquivo/?pasta=2020/06_Junho/DODF%20120%2029-06-2020&arquivo=DODF%20120%2029-06-2020%20INTEGRA.pdf>

últimas analises de consistência e formatação do banco de dados, a expansão da amostra e a elaboração dos relatórios de resultados. Para 2021, a PDAD contabilizou 3.010.881 moradores e 963.812 domicílios no Distrito Federal.

Este relatório, além desta introdução, conta com uma seção de metodologia e uma ampla seção de resultados, dividida em dois conjuntos de informações. O primeiro conjunto abordará as características demográficas da população, de migração, comunicação, saúde, educação, trabalho e rendimento. Já o segundo conjunto abordará as características domiciliares, com informações sobre a infraestrutura dos domicílios e em suas proximidades, os serviços domiciliares e o inventário de bens, os locais predominantes de compras, a existência de animais domésticos e situações de insegurança alimentar. Por fim, a última seção apresentará as considerações finais, enquanto, nos anexos, serão disponibilizadas todas as tabulações.

2 METODOLOGIA

Nesta seção, são apresentados os principais aspectos metodológicos que envolveram a realização da PDAD 2021. Todas as atividades de coordenação geral da pesquisa, planejamento, análise de consistência, expansão dos resultados e elaboração das análises, incluindo este relatório, foram realizadas pela equipe da Codeplan. Já o trabalho de campo foi conduzido por empresas especializadas, contratadas pela Codeplan para esta finalidade.

A unidade elementar de interesse foi o domicílio particular situado em área urbana ou em área rural com características urbanas, além de algumas áreas de interesse da Codeplan. Em cada domicílio visitado, foram coletadas informações de todos os moradores, gerando dois conjuntos de informações: o primeiro relacionado às características dos domicílios; o segundo relacionado aos moradores.

A coleta dos dados foi realizada entre maio e dezembro de 2021, com as entrevistas sendo efetuadas todos os dias da semana, entre 07:00 e 20:00 horas, por meio de coletor eletrônico. Esta atividade de campo foi conduzida pela empresa VR consultoria[6]. Foram realizadas, pelo menos, três tentativas de visitas em dias em horários distintos. Havendo recusa, foram disponibilizadas duas listas de substituições dos domicílios, seguindo esta mesma metodologia de visitas. Visando a garantir a qualidade dos dados, 25% das informações coletadas passaram por um processo de checagem, realizado pela empresa Ágora Pesquisa[7]. Além disso, checagens adicionais de campo foram realizadas pela equipe interna da Codeplan. A data de referência da pesquisa é 1º de julho de 2021.

No restante desta seção, são apresentados os detalhes da definição da área pesquisada e da definição da amostra.

[6] <https://promaxima.com.br/>
[7] <https://www.agorapesquisa.com/>

2.1 Definição da área pesquisada

A PDAD é uma pesquisa amostral que visa a fornecer informações representativas para todas as Regiões Administrativas do Distrito Federal. Na elaboração de planos amostrais para pesquisas domiciliares, a definição dos limites de áreas estudadas torna-se um requisito necessário, pois as inferências realizadas devem ter definidas as áreas de referência. Até a última edição da PDAD, em 2018, tais definições não existiam para todas as regiões presentes na legislação local[8].

Com a aprovação da Lei Complementar nº 958, de 20 de dezembro de 2019[9], atualmente, todas as 33 poligonais estão definidas oficialmente. Em virtude disso, o desenho do plano amostral apresentou algumas modificações daquele observado na PDAD de 2018, contando com alteração em algumas áreas quanto às delimitações das Regiões Administrativas e de algumas localidades de interesse estudadas. Por exemplo, o Jardim Mangueiral, que antes pertencia à RA São Sebastião, passou a pertencer à RA Jardim Botânico. A área de cobertura da PDAD 2021 é apresentada na Figura 2.1.1.

Para o plano amostral da PDAD 2021, foi considerado como universo (sistema de referência) os domicílios do conjunto de setores censitários domiciliares urbano, rural com características urbanas ou de áreas de interesse da Codeplan. Tais domicílios compuseram a lista de localidades definidas como área de cobertura da PDAD 2021, sendo preservados os limites geográficos dos setores censitários, que compreende a menor unidade geográfica para a qual o IBGE publica dados e com a qual ele operacionaliza suas atividades de coleta de dados domiciliares[10].

[8] Quando a PDAD 2018 foi realizada, existiam no DF 31 Regiões Administrativas criadas em Lei, todavia apenas 19 delas apresentavam suas poligonais definidas. Por esta razão, e para fins de pesquisa, a Codeplan definiu uma delimitação provisória, que foi utilizada até então.

[9] Disponível em: <http://www.sinj.df.gov.br/sinj/Norma/0503ee8e9efd40eca1ffd183d4b50fd0/Lei_Complementar_958_20_12_2019.html>

[10] Considerou-se a malha preliminar de 2019 do IBGE.

Figura 2.1.1: Região de interesse da PDAD 2021

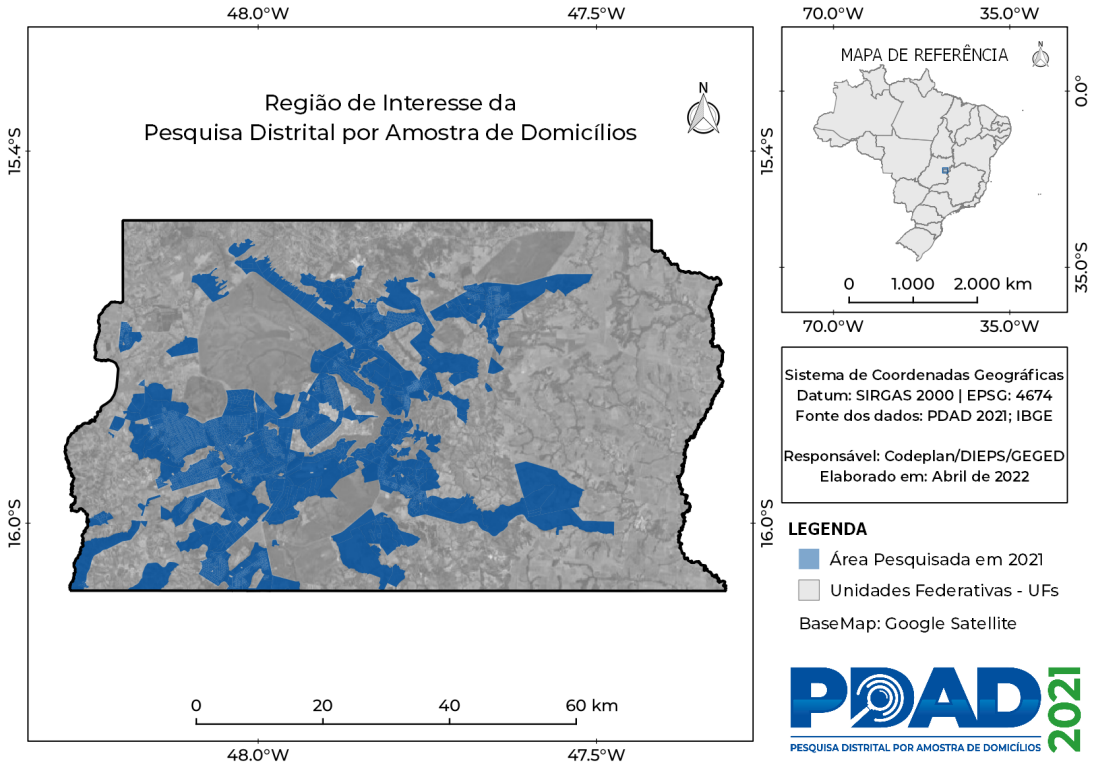

2.2 A amostra

A seleção da amostra seguiu o esquema de amostragem aleatória sistemática para as 33 regiões administrativas do Distrito Federal e as localidades de interesse estabelecidas pela CODEPLAN (totalizando 43).

Para a definição do tamanho das amostras, utilizou-se como parâmetro estatístico a variância da renda domiciliar. Tal parâmetro serviu de balizador na partição da amostra total, de 35.556 domicílios, seguindo o modelo da repartição de Neyman. Quanto maior a variância da renda domiciliar, maior foi a amostra da localidade, sendo utilizado os dados de renda da PDAD 2018.

No intuito de garantir robustez nas amostras, foi definido o menor tamanho amostral (n) de 440 domicílios por localidade, mesmo que a fórmula estatística indicasse uma amostra suficiente menor. Foi prevista uma margem de perda em torno de 16%, de forma que, não ocorrendo 100% da amostra sorteada para uma determinada localidade, os resultados não seriam comprometidos estatisticamente[11].

A base de endereços foi construída utilizando-se o cadastro de programas habitacionais, o cadastro de consumidores de energia elétrica, o cadastro de consumidores de água, cadastros do DF Legal[12] e cadastros de geolocalização elaborados pela Codeplan, todos contendo as variáveis de localização, o que possibilitou agregar, conforme a Região Administrativa, os endereços contidos nos 4.199 setores censitários abrangidos pela pesquisa[13]. Foram utilizadas imagens de satélite para detectar aglomerados subnormais com características urbanas ainda não incluídos nos cadastros disponíveis, para os quais a CODEPLAN providenciou listagens para, assim, dispor de todos os endereços nas 43 localidades abrangidas pela pesquisa. Como exemplo, cita-se a localidade Santa Luzia, situada na RA SCIA-Estrutural. O universo de endereços residenciais urbanos contemplou 899.864 unidades domiciliares aparentemente ocupadas. Foram definidas 43 localidades (ou estratos) de interesse, apresentados na Tabela 2.2.1.

[11] Até o limite desta perda.

[12] Todos os cadastros foram gentilmente compartilhados pela Companhia de Desenvolvimento Habitacional do Distrito Federal – CODHAB, pela então Companhia Energética de Brasília – CEB, pela Companhia de Saneamento Ambiental do Distrito Federal – CAESB e pela Secretaria de Estado De Proteção da Ordem Urbanística do Distrito Federal – DF LEGAL, respectivamente.

[13] Conforme malha censitária parcial do IBGE de 2019.

Tabela 2.2.1: Amostra da PDAD 2021 por localidade

Localidade	Amostra	Localidade	Amostra
Águas Claras	1.808	Plano Piloto - Noroeste	1.387
Arniqueira	630	Recanto das Emas	654
Brazlândia	582	Riacho Fundo	594
Candangolândia	561	Riacho Fundo II	604
Ceilândia	868	S. Sebastião - Consolidado	596
Cruzeiro	616	S. Sebastião - Morro da Cruz	550
Fercal	514	Samambaia	1.059
Gama	778	Santa Maria	696
Guará	1.220	SCIA/Estrutural - Chácara S. Luzia	512
Itapoã	585	SCIA/Estrutural - Consolidado	531
J. Botânico - Consolidado	889	SIA	530
J. Botânico - Jardim Mangueiral	679	Sobradinho	742
Lago Norte	998	Sobradinho II	753
Lago Sul	935	Sol Nasc./Pôr do Sol	600
Núcleo Bandeirante	621	Sudoeste/Octogonal	1.399
Paranoá	578	Taguatinga - Consolidado	1.198
Park Way	853	Taguatinga - S. Prim. ARINE	556
Planaltina - Arapoanga	575	Taguatinga - S. Prim. ARIS	527
Planaltina - Consolidado	710	V. Pires - 26 de Setembro	672
Plano Piloto - Asa Norte	1.936	V. Pires - Consolidado	1.356
Plano Piloto - Asa Sul	1.928	Varjão	510
Plano Piloto - Demais	666		

Fonte: CODEPLAN/DIEPS/GEGED/NUEST

O tamanho da amostra foi determinado a partir da relação:

$$n_i = n\frac{N_i Si}{\sum_{i=1}^{43} N_i S_i} \tag{1}$$

Em que n_i é o tamanho da amostra na localidade; N_i denota o número de domicílios da localidade i e S_i é a raiz quadrada da variância, para todos com i, $(i = 1, 2, 3, ..., 43)$

As estimativas dos totais e proporções foram obtidas a partir dos seguintes estimadores:

$$\hat{Y}_i = N_i \bar{y}_i \tag{2}$$

Em que $\hat{Y}_i$ é o estimador do total da localidade i e $\bar{y}_i$ é a média da amostra da localidade i.

$$\hat{p}_i = \frac{y_i}{n_i} \tag{3}$$

Em que $\hat{p}_i$ é o estimador de uma proporção da localidade i e y_i é o valor para uma característica na amostra da localidade i.

Para o Distrito Federal, os estimadores foram:

$$\bar{Y}_i = \sum_{i=1}^{43} \infty_i \hat{y}_i \tag{4}$$

e

$$\bar{p}_i = \sum_{i=1}^{43} \infty_i \hat{p}_i \tag{5}$$

Em que ∞_i é o peso da RA i obtido pela relação, sendo o inverso da fração amostral:

$$\infty_i = \frac{N_i}{n_i} \tag{6}$$

e

$$N = \sum_{i=1}^{43} N_i \tag{7}$$

Apoiados em resultados de pesquisas desse mesmo porte, com a mesma finalidade, pode-se prever um erro de 3,5%, com 95% de grau de confiança.

A fração amostral resulta da seguinte relação:

$$Fi = \frac{n_i}{N_i} \tag{8}$$

Em que n_i é o tamanho da amostra da localidade i e N_i é o número de domicílios da localidade i.

Para a expansão dos resultados, foram consideradas as projeções populacionais produzidas pela Codeplan, tendo como norte as projeções realizadas pelo Instituto Brasileiro de Geografia e Estatística – IBGE, distribuídas pelas RAs pela equipe da Diretoria de Estudos e Políticas Sociais – DIPOS, da Codeplan[14]. As informações populacionais foram pós-estratificadas por cada uma das 43 localidades territoriais, por sexo e faixas de idade[15], totalizando 1.376 pós-estratos. As informações de domicílios foram expandidas com os dados do Cadastro Nacional de Endereços para Fins Estatísticos – CNEFE, do IBGE[16].

Ao longo do texto, as barras verticais e horizontais nos gráficos denotam o intervalo de confiança das estimativas, calculadas por *bootstrap* segundo metodologia proposta por Rao e Wu (1988)[17], utilizando o pacote *survey*[18] do software R. Além disso, definiu-se um coeficiente de variação máximo de 25% para o reporte das estimativas. As estimativas que apresentaram coeficientes de variação superiores a esse limite foram omitidas do relatório, garantindo, dessa forma, que apenas informações com um parâmetro de qualidade definido fossem divulgadas. Por essa razão, nem sempre as tabelas totalizarão 100% ou os totais populacionais do domínio em análise. Além disso, foram considerados apenas as respostas válidas para as questões, excluíndo-se, portanto, os casos para os quais o morador não sabia fornecer a informação[19].

[14] Como a PDAD 2021 não abrangeu 100% do território, sua população-alvo é ligeiramente inferior à população residente, estimada em 3.091.667, ou seja, uma diferença de 80.786 pessoas. As informações completas sobre as projeções populacionais estão disponíveis em: <https://www.codeplan.df.gov.br/wp-content/uploads/2021/12/Estudo-Projecoes-populacionais-para-as-Regioes-Administrativas-do-Distrito-Federal-2020-2030-Resultados.pdf>

[15] Foram considerados quinquenios de zero até 74 anos e mais de 75 anos.

[16] Para duas localidades, 26 de setembro e Morro da Cruz, o CNEFE não refletia, no nomento da expansão, o volume de domicílios particulares da região. Assim sendo, utilizou-se como estimativa o peso do responsável pelo domicílio.

[17] Rao, J.N.K. and C.F.J. Wu. 1988. Re-Sampling Inference With Complex Survey Data. JASA, March Vol. 83 No.401 pp. 231-241.

[18] Informações sobre o pacote estão disponíveis em: T. Lumley (2020) "Survey: analysis of complex survey samples". R package version 4.0.

[19] Sendo a PDAD uma pesquisa domiciliar, preferencialmente, procura-se entrevistar todos os moradores do domicílio. Entretanto, no momento da entrevista, nem todos os moradores podem estar presentes presentes. Nestes casos, conforme a metodologia adotada pela pesquisa, é possível que um morador forneça informações sobre os demais, o que pode ocasionar situações de não respostas para determinadas questões.

2.3 Caracterização da Unidade de Planejamento Territorial (UPT) Central

A política urbana brasileira é regida pelos artigos artigos 182 e 183 da Constituição Federal de 1988. A regulamentação desses artigos veio em 2001, com a Lei nº 10.257, de 10 de julho de 2001, conhecida como Estatuto da Cidade, que estabelece diretrizes gerais da política urbana. O estatuto estabelece o Plano Diretor como instrumento básico da política de desenvolvimento e expansão urbana[20].

Aqui no DF, o Plano Diretor de Ordenamento Territorial do Distrito Federal instituiu as Unidades de Planejamento Territorial – UPTs[21] (artigo 103 da Lei Complementar 803/2009) para fins de ordenamento e gestão do território do DF. O Distrito Federal foi dividido em 7 (sete) UPTs, as UPTs Norte, Sul, Leste, Oeste, Central, Central Adjacente I e Central Adjacente II (Figura 2.3.1).

Figura 2.3.1: Unidades de Planejamento Territorial com destaque para as RA que compõem a UPT Central Adjacente 1

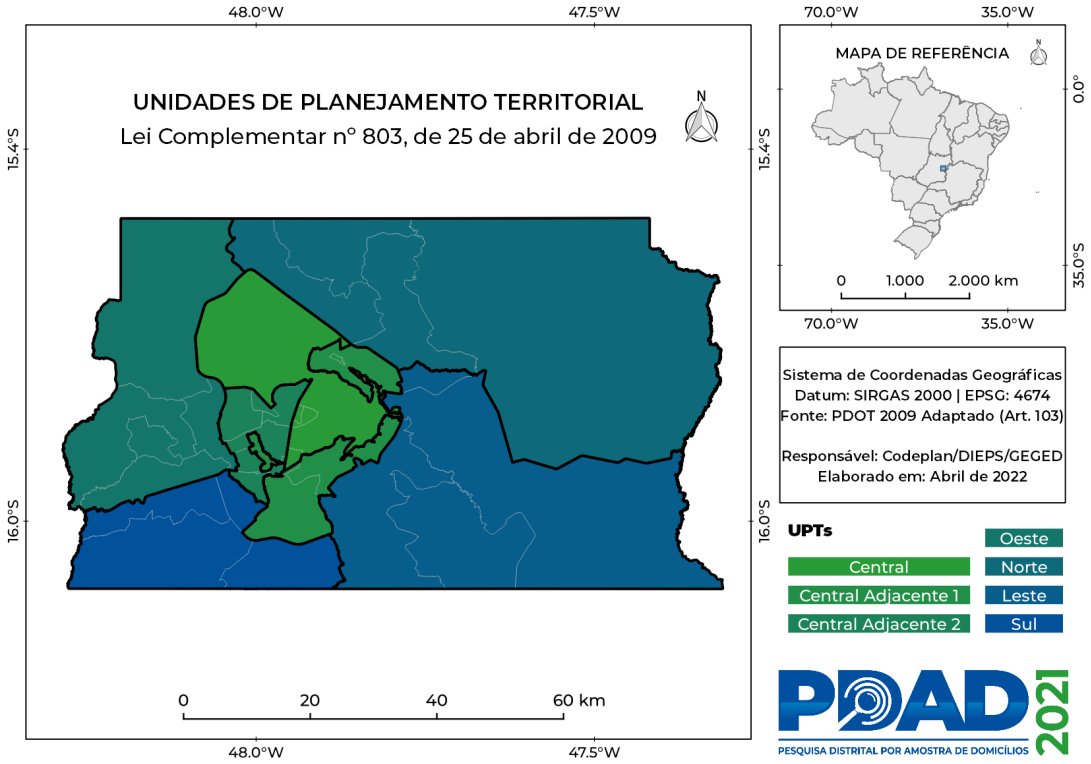

[20] BRASIL. Lei no 10.257 de 10 de julho de 2001. Disponível em: <http://www.planalto.gov.br/ccivil_03/leis/leis_2001/l10257.htm>. Acesso em: 26 abr. 2022.

[21] DISTRITO FEDERAL. Lei Complementar no 803 de 25 de abril de 2009. Disponível em: <http://www.sinj.df.gov.br/sinj/Norma/60298/Lei_Complementar_803_25_04_2009.html>. Acesso em: 26 abr. 2022.

O Estatuto da Cidade estabelece que a revisão do Plano Diretor deve ser realizada a cada 10 anos e, no DF, a Secretaria de Estado de Desenvolvimento Urbano e Habitação – SEDUH iniciou o processo de revisão em 2019, que pode ser acompanhado no Portal do PDOT[22]. Os principais aspectos da UPT Central e do Plano Piloto são:

- A Região Administrativa – RA I – Plano Piloto concentra 68,67% da população da UPT Central, que é formada também pelas RAs Candangolândia, Cruzeiro e Sudoeste/Octogonal. No DF, a população da RA representa 7,47% do total;
- A população total da UPT Central é de 327.413 habitantes, o que representa 10,87% da população do Distrito Federal;
- A densidade demográfica do Plano Piloto na área pesquisada é de 4.299,64 habitantes/km².

2.4 Breve histórico e características da RA Plano Piloto

A Região Administrativa do Plano Piloto – RA I – completa 62 anos no dia 21 de abril de 2022. Com uma área de 43.720,14 hectares, o Plano Piloto recebe a água para seu o abastecimento dos reservatórios do Torto, Santa Maria, Bananal e Lago Paranoá[23].

A construção de Brasília foi marcada por várias iniciativas e ideias que permearam o imaginário daqueles que pretendiam ver erguida, na região Centro-Oeste do país, a sede do governo brasileiro. Foi instituída em 1891, na primeira Constituição da República Brasileira, a "Missão Cruls", como ficou conhecida a Comissão Exploradora do Planalto Central. A Comissão realizou um trabalho de demarcação de terrenos e, entre 1892 e 1894, delimitou uma área de 1.440.000 hectares, conhecida como "Quadrilátero Cruls"[24].

Em setembro de 1956, o presidente eleito Juscelino Kubitschek instituiu a Companhia Urbanizadora da Nova Capital (Novacap), que realizou um concurso público para a escolha do projeto da nova capital. Dentre as 26 propostas

[22] Disponível em: <http://www.pdot.seduh.df.gov.br/>

[23] CAESB. Estações de Tratamento de Água. Disponível em: <https://atlascaesb.maps.arcgis.com/apps/MapJournal/index.html?appid=4d06131962ca482a9d51502c630e195f>. Acesso em: 6 abr. 2022.

[24] ALVES, Lara Moreira. A CONSTRUÇÃO DE BRASÍLIA: UMA CONTRADIÇÃO ENTRE UTOPIA E REALIDADE. p. 5

inscritas, venceu a proposta de número 22, do arquiteto Lúcio Costa, por apresentar uma proposta "clara, direta e fundamentalmente simples" de acordo com a comissão julgadora composta por júri internacional. A implantação da nova capital exigiu a construção dos primeiros canteiros de obras e de vários acampamentos para os trabalhadores e técnicos envolvidos na obra, originalmente de caráter temporário, e muitos desses acampamentos acabaram se tornando a origem de novas cidades permanentes e existentes até os dias atuais[25].

Brasília foi inaugurada em 21 de abril de 1960. A RA I – Brasília, no entanto, só foi formalmente criada em 1964, pela Lei nº 4.545, que dividiu o DF em 8 regiões administrativas. A RA teve seu nome alterado para RA I – Plano Piloto a partir do Decreto nº 11.921/1989, que fixou os limites das então 12 RAs[26]. A capital foi o primeiro conjunto urbano do século XX a ser reconhecido como Patrimônio Mundial pela Organização das Nações Unidas para a Educação, a Ciência e a Cultura (Unesco), em 1987, como Patrimônio Cultural da Humanidade, que busca preservar as características e a articulação das quatro escalas: monumental, residencial, bucólica e gregária, estabelecidas pela Portaria Iphan nº 314, de 8 de outubro de 1992[27].

A escala monumental abarca o Eixo Monumental, que, por sua vez, abriga o centro político-administrativo do País; a escala gregária representada por todos os setores de convergência da população; a escala residencial é composta pelas Superquadras Sul e Norte e a escala bucólica é caracterizada pela arquitetura paisagística de Burle Marx, que permeia as outras três escalas, ou seja, as áreas de uso público destinados aos jardins, praças e parques. Da interação dessas quatro escalas nasceu uma cidade que é predominantemente monumental[28]. A RA I possui o maior patrimônio histórico e cultural do Distrito Federal, a maior parte constituída de projetos do arquiteto Oscar Niemeyer como: Palácio da Alvorada, Palácio do Planalto, Congresso Nacional, Catedral, Memorial JK, dentre outras obras de arquitetos destacados do modernismo brasileiro.

[25] COSTA, Graciete Guerra da. As regiões administrativas do Distrito Federal de 1960 a 2011. 2011.Disponível em: <https://repositorio.unb.br/handle/10482/9987>. Acesso em: 8 abr. 2022.

[26] DISTRITO FEDERAL. Decreto no 11.921 de 25 de outubro de 1989. Disponível em: <http://www.sinj.df.gov.br/sinj/Norma/18119/exec_dec_11921_1989.pdf>. Acesso em: 8 abr. 2022.

[27] IPHAN. Brasília-DF - IPHAN - Instituto do Patrimônio Histórico e Artístico Nacional. Disponível em: <http://portal.iphan.gov.br/pagina/detalhes/31>. Acesso em: 2 maio 2022.

[28] OLIVEIRA, Josildete Pereira de; ANJOS, Francisco Antonio dos; LEITE, Fabiana Calçada de Lamare. O potencial da paisagem urbana como atratividade turística: um estudo sobre a paisagem de Brasília-DF. Interações (Campo Grande), v. 9, n. 2, p. 159–169, 2008.

A RA I é também conhecida por "cidade-parque", não apenas pela definição de projeto urbanístico de Lúcio Costa[29], que incorpora a vegetação e o céu às escalas urbanas, mas também por abrigar em seu território várias Unidades de Conservação. Em nível federal, há o Parque Nacional de Brasília – PNB, conhecido como Água Mineral, criado em 29 de novembro de 1961, que ocupa uma área de 42.355,54 hectares[30], abrange as Regiões Administrativas do Plano Piloto, Sobradinho, Brazlândia e do município goiano de Padre Bernardo. O PNB se destina à preservação de ecossistemas naturais de grande relevância ecológica e beleza cênica, à proteção de recursos hídricos, à realização de pesquisas científicas, ao desenvolvimento de atividades de educação ambiental, de recreação em contato com a natureza, de turismo ecológico e de proteção de espécies de fauna ameaçadas de extinção. O Parque Dona Sarah Kubitschek, mais conhecido por Parque da Cidade, é um dos maiores parques urbanos do mundo, com 4,2 quilômetros quadrados[31]. O projeto de paisagismo do Parque, que alia à paisagem elementos de lazer e recreação, sob autoria dos paisagistas Roberto Burle Marx, Haruyoshi Onu e José Tabacow, foi tombado pelo Decreto nº 33.224 de 2011, juntamente com as edificações existentes na data[32]. O Parque da Cidade é também um dos principais centros de lazer ao ar livre da Capital, especialmente para práticas esportivas e eventos culturais[33]. Entre os Parques Ecológicos e de Usos Múltiplos da RA I, destaca-se o Parque Olhos D'Água, localizado nos espaços que seriam destinados às superquadras 413 e 414 da Asa Norte. No local, encontra-se a Lagoa do Sapo, abastecida por diversas nascentes e córregos[34]. Existem também outros parques distritais ecológicos e de usos múltiplos criados mais recentemente, entre eles: o Parque Ecológico Asa Sul, o Parque

[29] TANURE, J.D. O projeto de paisagismo de Burle Marx e equipe para o "Parque da Cidade" em Brasília. Cap.3, p. 87-98. Disponível em <https://repositorio.unb.br/handle/10482/2067>. Acesso em 29/04/2012.

[30] BRASIL, Instituto Chico Mendes de Conservação da Biodiversidade. Parna Brasília. Disponível em: <https://www.gov.br/icmbio/pt-br/assuntos/biodiversidade/unidade-de-conservacao/unidades-de-biomas/cerrado/lista-de-ucs/parna-de-brasilia> Acesso em 27/04/2012.

[31] IBRAM, Dona Sarah Kubitshek. Disponível em: <https://www.ibram.df.gov.br/dona-sarah-kubitschek/> Acesso em 27/04/2012.

[32] DISTRITO FEDERAL. Decreto no 33.224 de 27 de setembro de 2011. Disponível em: <http://www.tc.df.gov.br/sinj/Norma/69432/exec_dec_33224_2011.html>. Acesso em: 10 maio 2022.

[33] ADMINISTRAÇÃO REGIONAL DO PLANO PILOTO. Plano de Uso e Ocupação do Parque da Cidade. Disponível em: <https://www.seduh.df.gov.br/wp-conteudo/uploads/2019/09/PUOC_Documento-Tecnico.pdf>. Acesso em: 10 maio 2022.

[34] IBRAM, Instituto Brasília Ambiental. Guia de Parques do Distrito Federal. Disponível em: <https://ibram.df.gov.br/wp-content/uploads/2018/03/GUIA-DE-PARQUES.compressed.pdf>. Acesso em: 6 abr. 2022.

da Vila Planalto, o Parque Ecológico Burle Marx e o Parque Ecológico Enseada Norte. Na Categoria de Parques Urbanos, há o Bosque dos Constituintes, o Bosque dos Tribunais e o Bosque das Aves.

A Feira de Artesanato da Torre de TV foi chamada de Feirinha Hippie por décadas. Hoje, ela é conhecida como Feirinha da Torre. Em mais de 50 anos de história, também mudou de lugar. Saiu dos pés da Torre, onde os feirantes montavam barraquinhas com lona azul, para os boxes fixos, pintados de verde, construídos em uma área mais abaixo do monumento projetado por Lúcio Costa. São 600 boxes, 480 ocupados, onde se vende redes, almofadas, esculturas, souvenirs de Brasília, vestuário, flores secas do Cerrado, artesanato, quadros, estofados e móveis[35]. Além dessa feira, o Plano Piloto conta com diversas feiras de produtos hortifruti, a maioria delas com produtos orgânicos, que estão abertas a população em dias e locais variados. Para maiores informações sobre essas feiras, a Empresa de Assistência Técnica e Extensão Rural – EMATER-DF conta com mapa no site[36].

As Regionais de Ensino que atendem os alunos do ensino público médio e fundamental do território são as do Plano Piloto e do Cruzeiro[37]. Além disso, a RA conta com um campus do Instituto Federal de Brasília – IFB, Campus Brasília, que oferta graduação em Licenciatura em Dança, Tecnologia em Eventos, Gestão Pública, Processos Gerenciais e Sistemas para Internet, cursos técnicos em Administração, Comércio, Eventos, Desenvolvimento de Sistemas e Serviços Públicos[38]. A universidade federal de Brasília, UnB Campus Darcy Ribeiro, foi criada em 1962, e oferece graduação e pós-graduação em várias áreas do conhecimento, sendo mais de 61 cursos de graduação e 102 programas de pós graduação[39]. Em 2021, a Universidade de Brasília estava na posição 16° entre as Universidades da América Latina no ranking internacional de universidades *Times Higher Education*[40].

[35] AGÊNCIA BRASÍLIA. Feira da Torre, um mosaico de cada cantinho do Brasil. Agência Brasília. Disponível em: <https://www.agenciabrasilia.df.gov.br/2020/02/27/feira-da-torre-um-mosaico-de-cada-cantinho-do-brasil/>. Acesso em: 6 abr. 2022.

[36] Disponível em: <https://emater.df.gov.br/feiras-organicas/>

[37] SEEDF. Coordenação de Regionais de Ensino. Disponível em: <https://www.educacao.df.gov.br/coordenacoes-regionais-de-ensino/>. Acesso em: 7 abr. 2022.

[38] Cursos - IFB Campus Brasília. Disponível em: <https://www.ifb.edu.br/brasilia/cursos>. Acesso em: 11 abr. 2022.

[39] Universidade de Brasília - Cursos. Disponível em: <https://www.unb.br/graduacao/cursos>. Acesso em: 11 abr. 2022.

[40] TIMES HIGHER EDUCATION (THE). University of Brasília, 2021. Disponível em: <https://www.timeshighereducation.com/world-university-rankings/universidade-de-brasilia-unb>. Acesso em: 10 maio 2022.

Os hospitais da rede pública do Plano Piloto são: Hospital Regional Asa Norte (HRAN), Hospital Universitário de Brasília (HUB), Hospital de Base do Distrito Federal (HBDF), Hospital Materno e Infantil de Brasília (HMIB), Hospital da Criança de Brasília José Alencar (HCB) ,Hospital de Apoio de Brasília (HAB)[41]. Além disso, a RA conta com o Hospital Naval de Brasília, que atende os servidores da Marinha do Brasil e com uma unidade da Rede SARAH de Hospitais de Reabilitação Associação das Pioneiras Sociais, ambos na Asa Sul[42].

Em relação ao transporte público, a empresa que atende a RA é a Viação Piracicabana[43] e as principais vias que acessam a RA são o Eixo Rodoviário de Brasília (DF-002), mais conhecido informalmente por Eixão, o Eixo Monumental, a Estrada Parque Indústria e Abastecimento – EPIA (DF-003), Estrada Parque Indústrias Gráficas – EPIG (DF-011) e a Estrada Parque das Nações – EPNA (DF-004)[44].

O mapa de cobertura da PDAD 2021 para o Plano Piloto é apresentado na Figura 2.4.1.

[41] SES-DF, Hospitais. Disponível em <https://info.saude.df.gov.br/hospitais/> . Acesso em 28/04/2022.

[42] REDE SARAH. Nossa História. Disponível em: <https://www.sarah.br/a-rede-SARAH/nossa-historia/>. Acesso em: 10 maio 2022.

[43] SECRETARIA DE TRANSPORTE E MOBILIDADE. Dados do Sistema de Transporte Público Coletivo do Distrito Federal. Disponível em: <https://semob.df.gov.br/dados-do-sistema-de-transporte-publico-do-df/>. Acesso em: 6 abr. 2022.

[44] DER/DF, Departamento de Estradas de Rodagem do DF. Sistema Rodoviário do Distrito Federal 2021. Disponível em: <https://www.der.df.gov.br/wp-content/uploads/2017/11/SRDF_2021.pdf>.

Figura 2.4.1: Área de cobertura do Plano Piloto na PDAD 2021

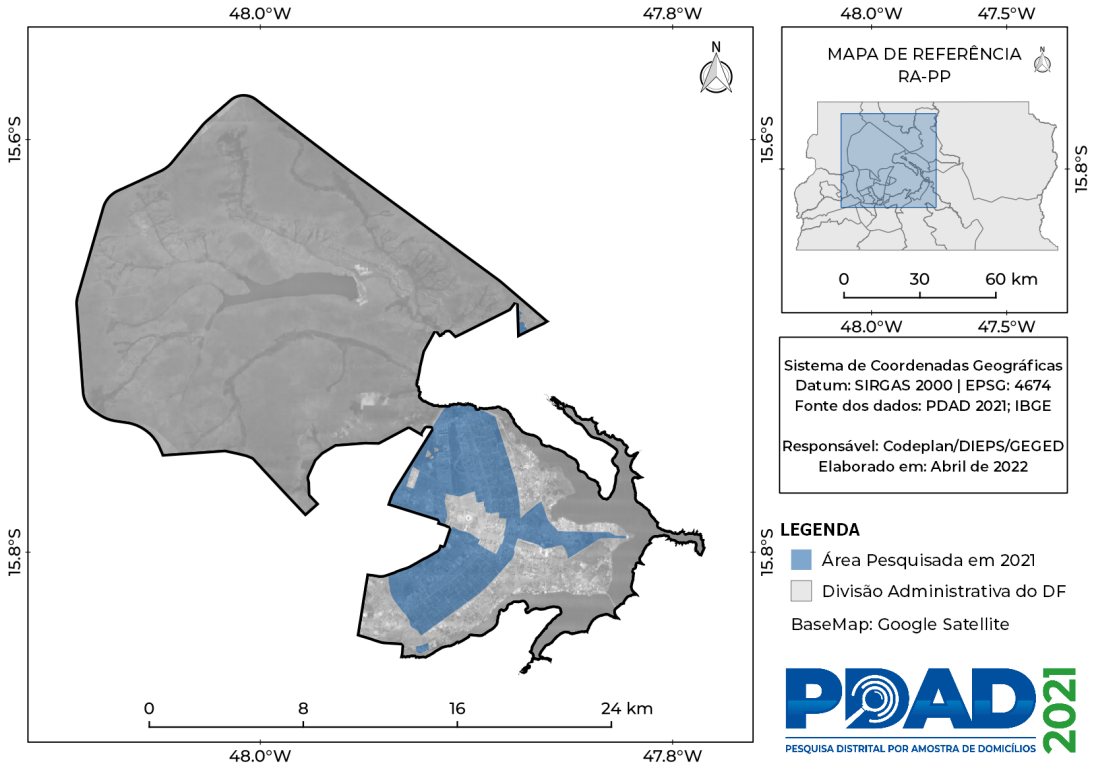

3 RESULTADOS – MORADORES

3.1 Caracterização da população urbana

A PDAD 2021 aponta que a população urbana da localidade Asa Norte era de **118.450** pessoas, sendo 52,9% do sexo de nascimento feminino (Figura 3.1.3 e Tabela A.3). A idade média era de 39,7 anos. A pirâmide etária, apresentada na Figura 3.1.1, traz a distribuição da população por faixas de idade e por sexo (Tabela A.1).

Figura 3.1.1: Distribuição da população por faixas de idade e sexo, Asa Norte, 2021

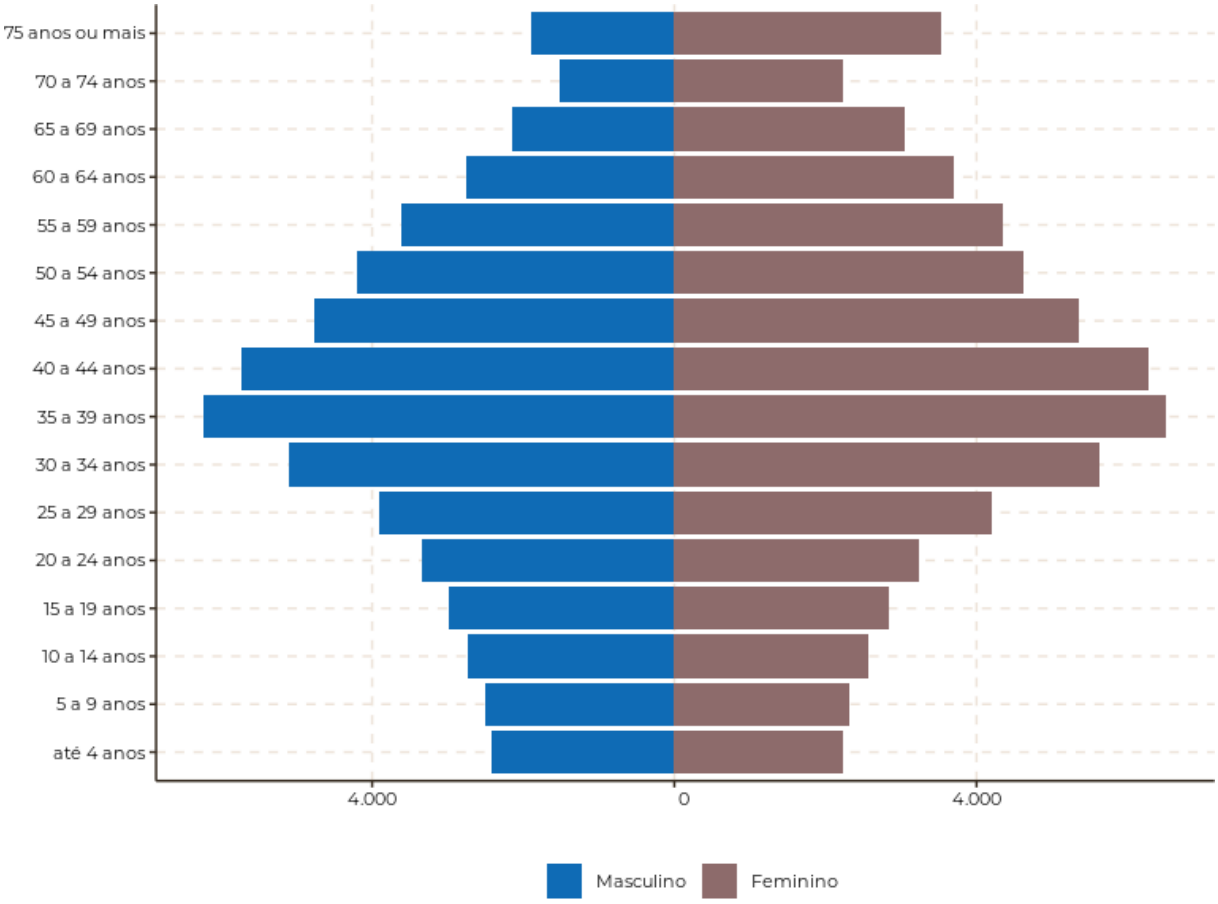

Fonte: CODEPLAN/DIEPS/GEREPS/PDAD 2021

Para entender como as pessoas estão organizadas dentro dos domicílios, foram criados os seguintes arranjos: unipessoal; monoparental feminino; casais sem filhos; casais com um filho; casais com dois filhos; casais com três ou mais filhos; e outros perfis. Para essas classificações, observou-se que o arranjo "casal sem filhos" foi o mais observado, em 31,1% dos domicílios (Figura 3.1.2 e Tabela A.2).

Figura 3.1.2: Distribuição da população por arranjos domiciliares, Asa Norte, 2021

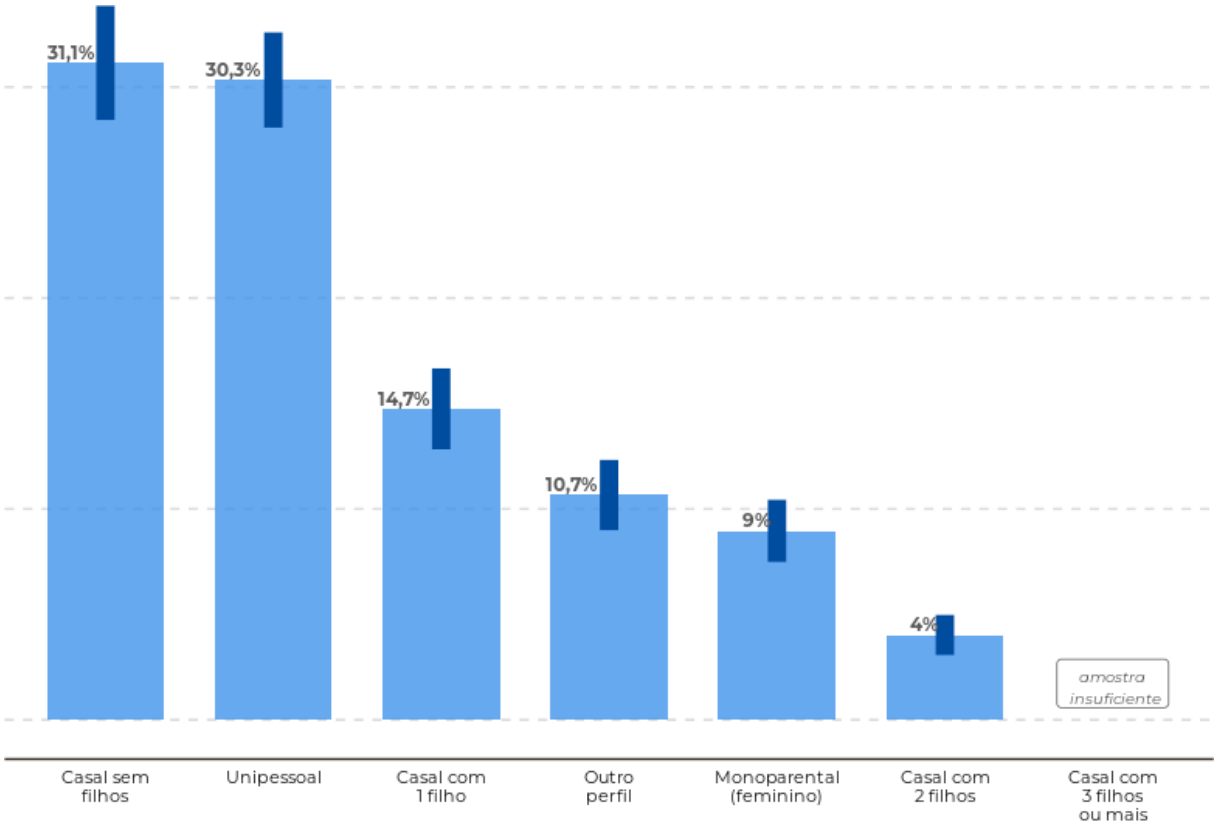

Fonte: CODEPLAN/DIEPS/GEREPS/PDAD 2021

Figura 3.1.3: Distribuição da população por sexo, Asa Norte, 2021

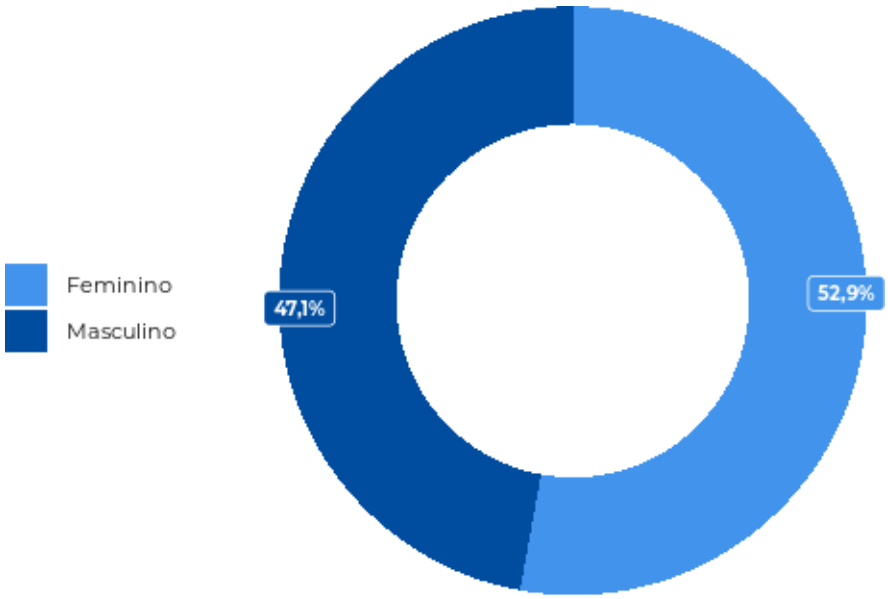

Fonte: CODEPLAN/DIEPS/GEREPS/PDAD 2021

Nesta edição, a PDAD trouxe uma inovação, com perguntas sobre identidade de gênero e sobre orientação sexual dos moradores com 18 anos ou mais de idade[45]. Quando considerado o cruzamento com a questão sobre sexo de nascimento dessas pessoas, no que diz respeito à orientação sexual, 7,5% dos respondentes eram lésbicas, gays, bissexuais ou outros; quanto à identidade de gênero, não houve amostra suficiente para divulgação dos resultados (Figura 3.1.4 e Tabela A.4).

Quando consideradas as pessoas LGBTQIA+[46], ou seja, pessoas transgêneros e/ou lésbicas, gays, bissexuais ou outros, verificou-se uma resposta afirmativa para 7,9% dos respondentes (Figura 3.1.4 e Tabela A.5).

Figura 3.1.4: Orientação sexual das pessoas com 18 anos ou mais, Asa Norte, 2021

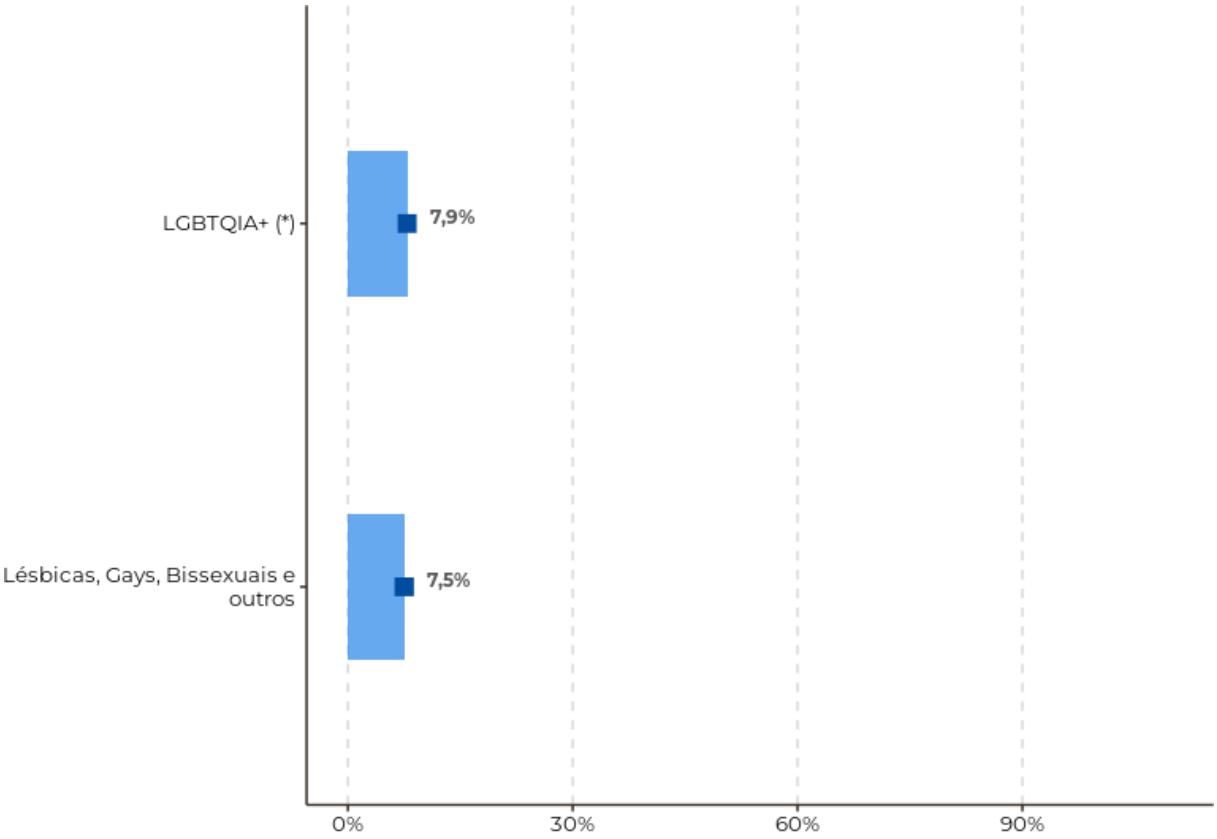

Fonte: CODEPLAN/DIEPS/GEREPS/PDAD 2021
(*) Pessoas que se identificaram como transgêneros e também lésbicas, gays, bissexuais ou outros são consideradas apenas uma vez.

[45] Para mais informações sobre o tema, consulte a Nota Técnica *Gênero e Orientação Sexual no DF – um olhar inclusivo*. Disponível em: <https://www.codeplan.df.gov.br/wp-content/uploads/2018/03/NT-Genero-e-Orientacao-Sexual-no-DF-um-olhar-inclusivo.pdf>

[46] Pessoas que se identificaram como transgêneros e também lésbicas, gays, bissexuais ou outros são consideradas apenas uma vez.

No que diz respeito à raça/cor da pele, verificou-se que a resposta mais comum foi branca, para 58,3% dos moradores (Figura 3.1.5 e Tabela A.7). Sobre o estado civil, 51,4% da população com 14 anos ou mais de idade se declararam casados (Figura 3.1.6 e Tabela A.8).

Por fim, sobre a posse de carteira nacional de habilitação (CNH), 84,9% dos moradores de 18 anos ou mais de idade afirmaram ter o documento (Figura 3.1.7 e Tabela A.6).

Figura 3.1.5: Distribuição da população por raça/cor da pele, Asa Norte, 2021

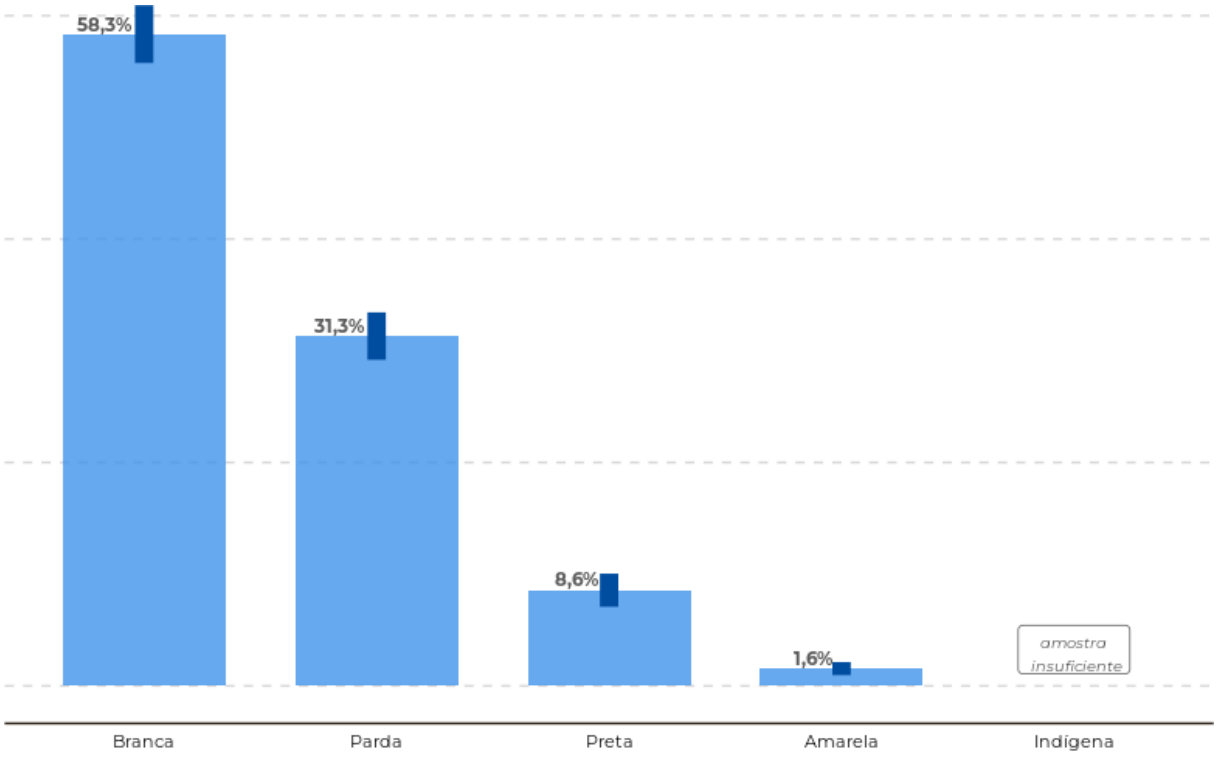

Fonte: CODEPLAN/DIEPS/GEREPS/PDAD 2021

Figura 3.1.6: Distribuição da população por estado civil (14 anos ou mais), Asa Norte, 2021

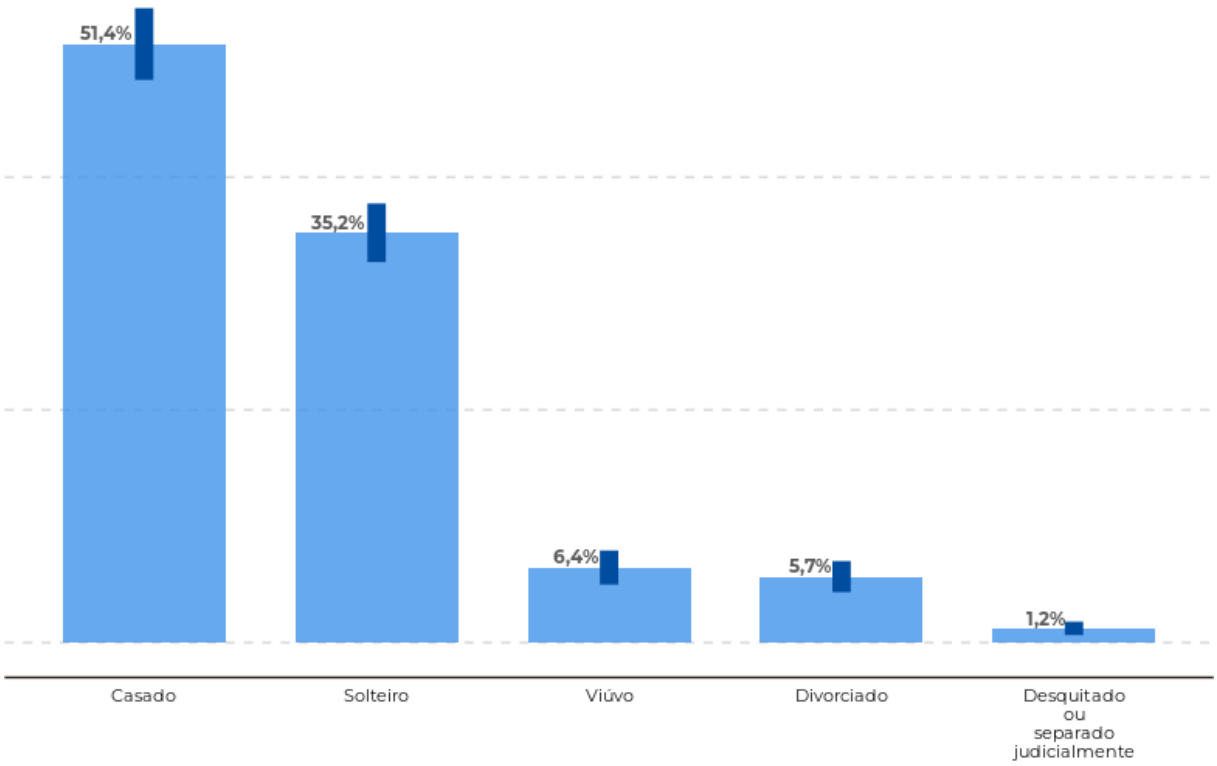

Fonte: CODEPLAN/DIEPS/GEREPS/PDAD 2021

Figura 3.1.7: Pessoas com 18 anos ou mais que possuíam CNH, Asa Norte, 2021

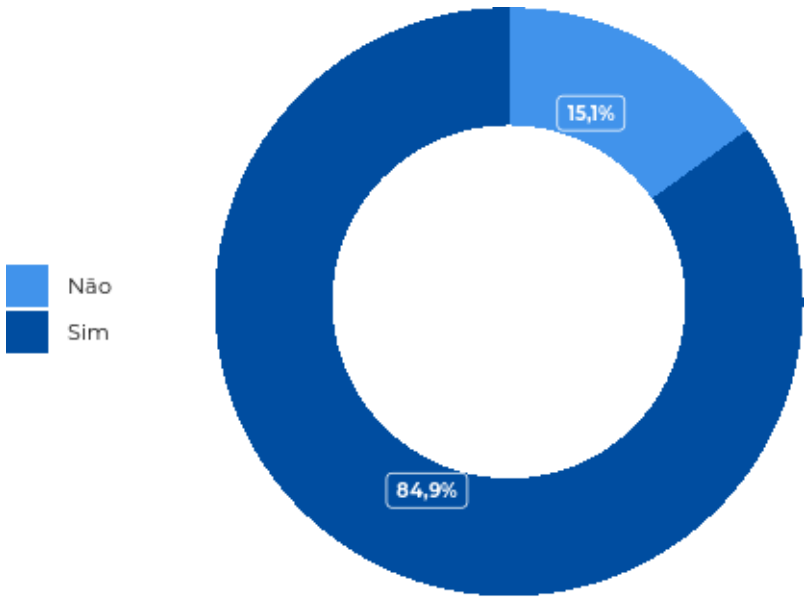

Fonte: CODEPLAN/DIEPS/GEREPS/PDAD 2021

3.2 Migração

Quanto à origem dos moradores, 64,3% informaram ter nascido fora do DF (Tabela A.9)[47]. Para os que não nasceram no DF, o estado mais reportado foi Minas Gerais, segundo 20,4% dos entrevistados (Figura 3.2.1 e Tabela A.10). Para todos os moradores do DF, o tempo médio de moradia na capital federal é de 26,8 anos, enquanto o tempo médio de moradia da RA é de 14,4 anos. Sobre aqueles que vieram para o DF ou que deixaram o território, mas retornaram posteriormente, foi questionada a motivação que os levou a fazer isso. Para 44,3% dos responsáveis dos domicílios, trabalho foi a principal razão da movimentação (Figura 3.2.2 e Tabela A.11).

Figura 3.2.1: Principais estados de nascimento das pessoas que vieram de fora do DF, Asa Norte, 2021

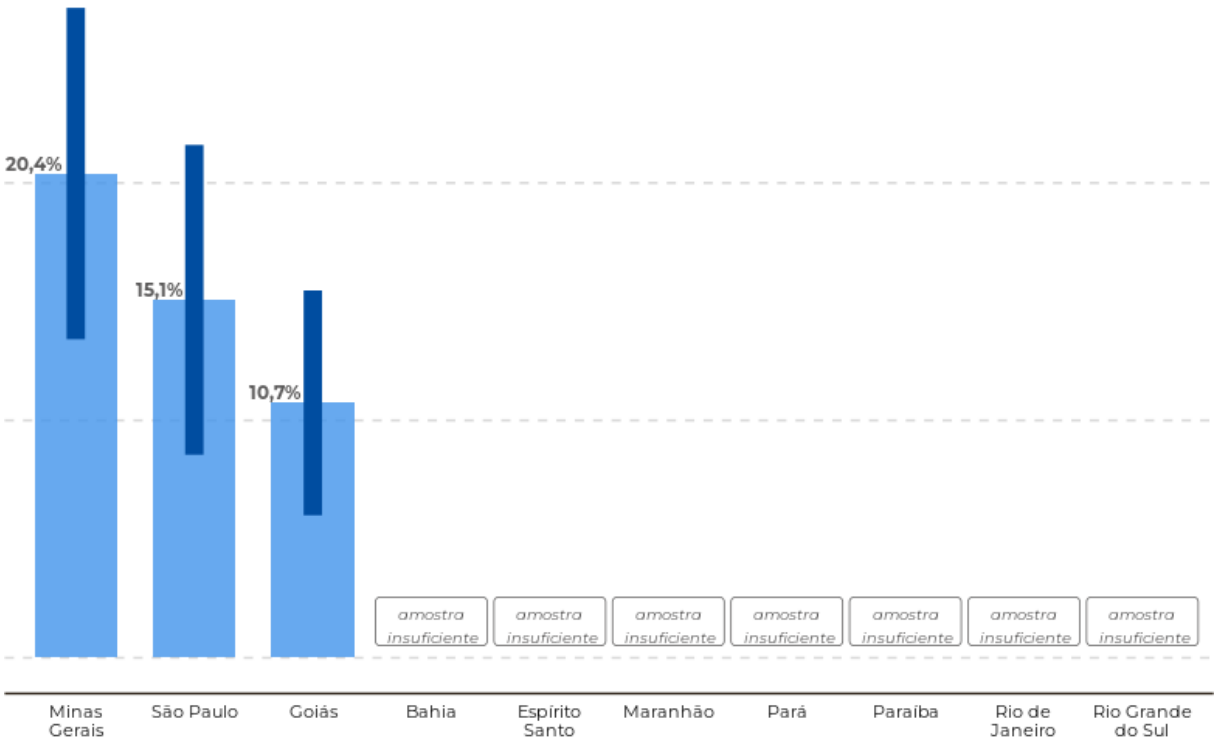

Fonte: CODEPLAN/DIEPS/GEREPS/PDAD 2021
Obs.: São reportadas até o limite das dez maiores categorias.

[47] Devido a problemas na coleta, esta questão apresentou problemas de consistência. Com o intuito de permanecer fornecendo estimativas para esta característica, cerca de 40% dos casos passou por um processo de imputação das respostas. As pessoas que foram imputadas como nascidas fora do DF não tiveram seu local de nascimento imputados.

Figura 3.2.2: Distribuição da motivação do responsável do domicílio a mudar e/ou retornar à capital federal, Asa Norte, 2021

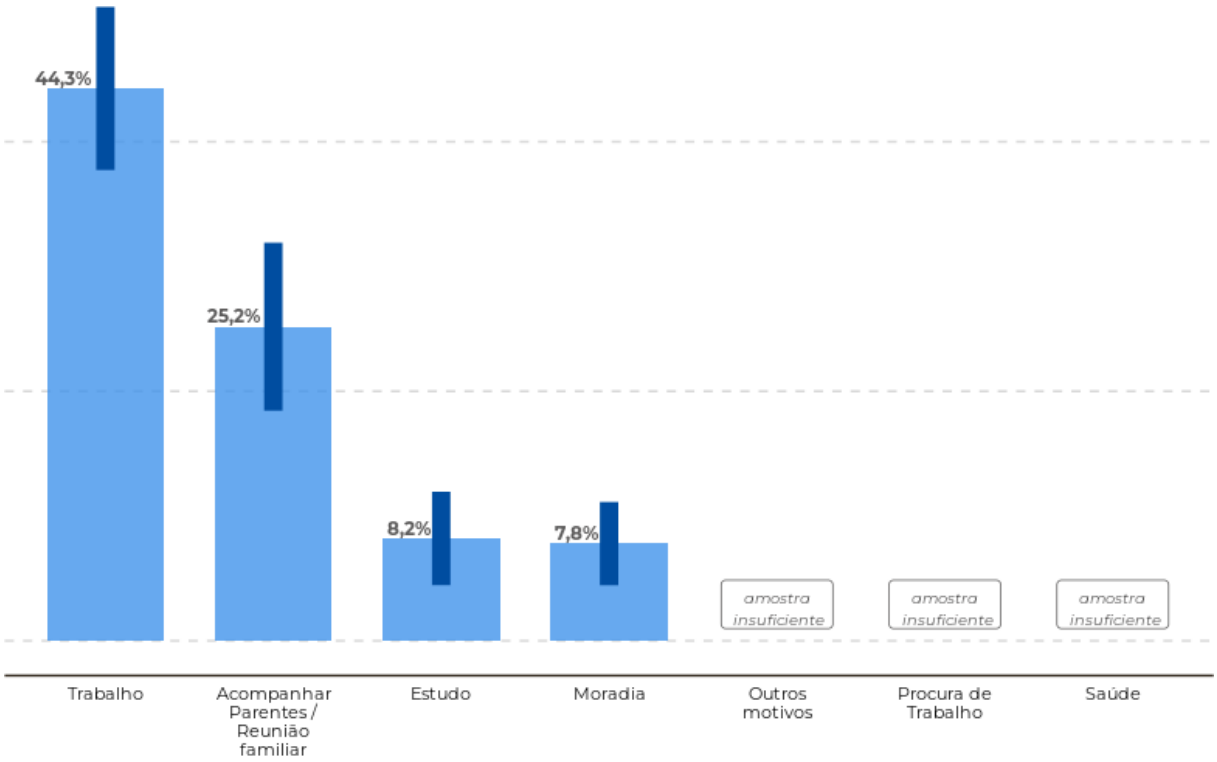

Fonte: CODEPLAN/DIEPS/GEREPS/PDAD 2021

Segundo os moradores com 14 anos ou mais de idade, 4,4% afirmaram ter intenção de constituir um novo domicílio no DF, sendo a RA Plano Piloto a mais reportada (71,3%) (Figura 3.2.3 e Tabela A.12).

Figura 3.2.3: Intenção e localidade para constituição de novo domicílio nos próximos 12 meses das pessoas de 14 anos ou mais, Asa Norte, 2021

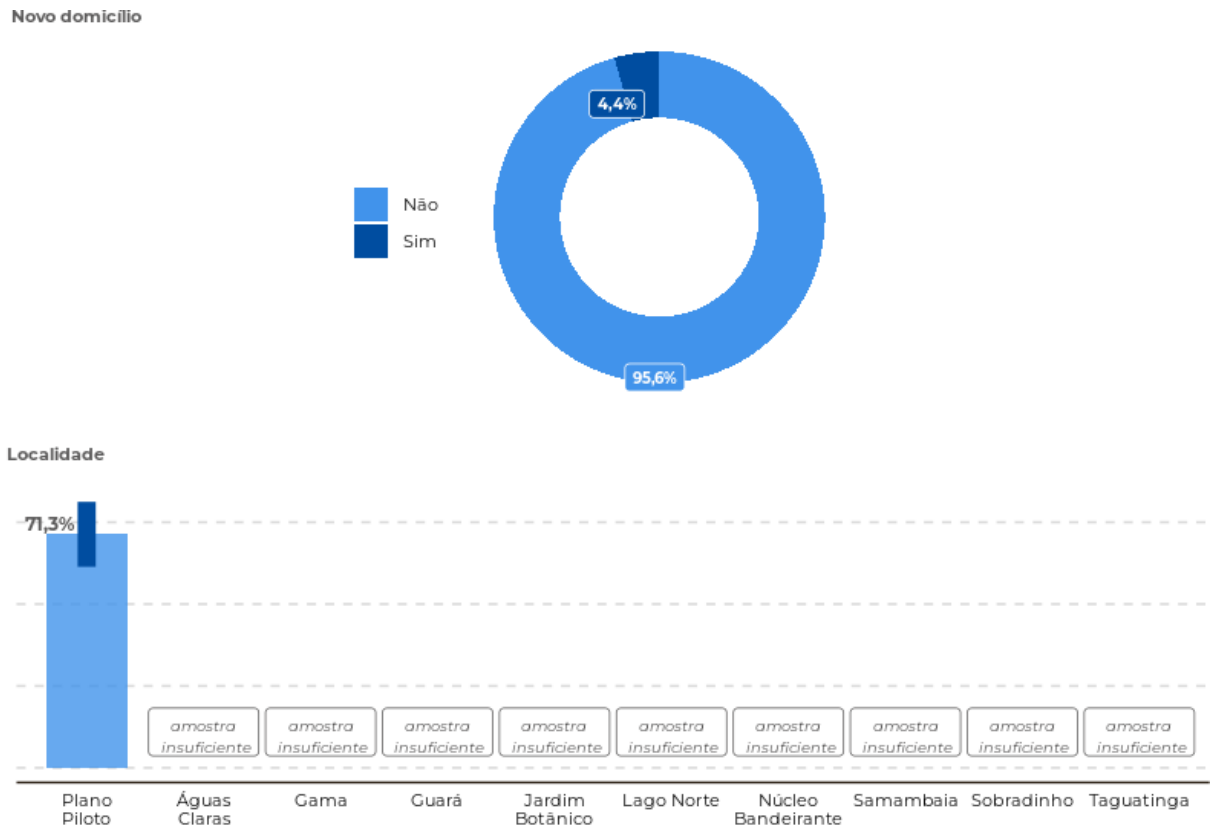

Fonte: CODEPLAN/DIEPS/GEREPS/PDAD 2021

3.3 Saúde

A PDAD 2021 levantou informações sobre pessoas com deficiência. No que diz respeito à visão, 86,5% declararam que "não têm dificuldade" para enxergar (Figura 3.3.1 e Tabela A.13). Quanto à audição, 96% declararam que "não têm dificuldade" para escutar (Figura 3.3.1 e Tabela A.14). Já para a locomoção, 97,8% informaram que "não têm dificuldade" para caminhar ou subir degraus (Figura 3.3.1 e Tabela A.15). Por fim, 98,7% reportaram que não têm dificuldade decorrente de limitações nas funções mentais, enquanto 98,9% não têm dificuldade para pegar pequenos objetos (Figura 3.3.1 e Tabelas A.16 e A.17).

Sobre a cobertura de plano de saúde privado, verificou-se que 60,4% declararam ter este serviço, dos quais 80,6% eram individual/familiar e 42,3% tinham coparticipação/franquia (Figura 3.3.2 e Tabela A.18).

No que diz respeito ao atendimento de saúde, 41,6% dos moradores informaram ter utilizado posto de saúde/unidade básica de saúde na última ocasião de necessidade (Figura 3.3.3 e Tabela A.21).

O principal motivo para o atendimento foi vacinação, segundo 50,5% (Figura 3.3.4 e Tabela A.22), e a localidade de atendimento predominante, entre estes, foi Plano Piloto (98,7%) (Figura 3.3.5 e Tabela A.23).

Figura 3.3.1: Distribuição da população segundo grau de dificuldade para enxergar, ouvir, caminhar ou subir degraus, limitação nas funções mentais ou dificuldade para pegar pequenos objetos, Asa Norte, 2021

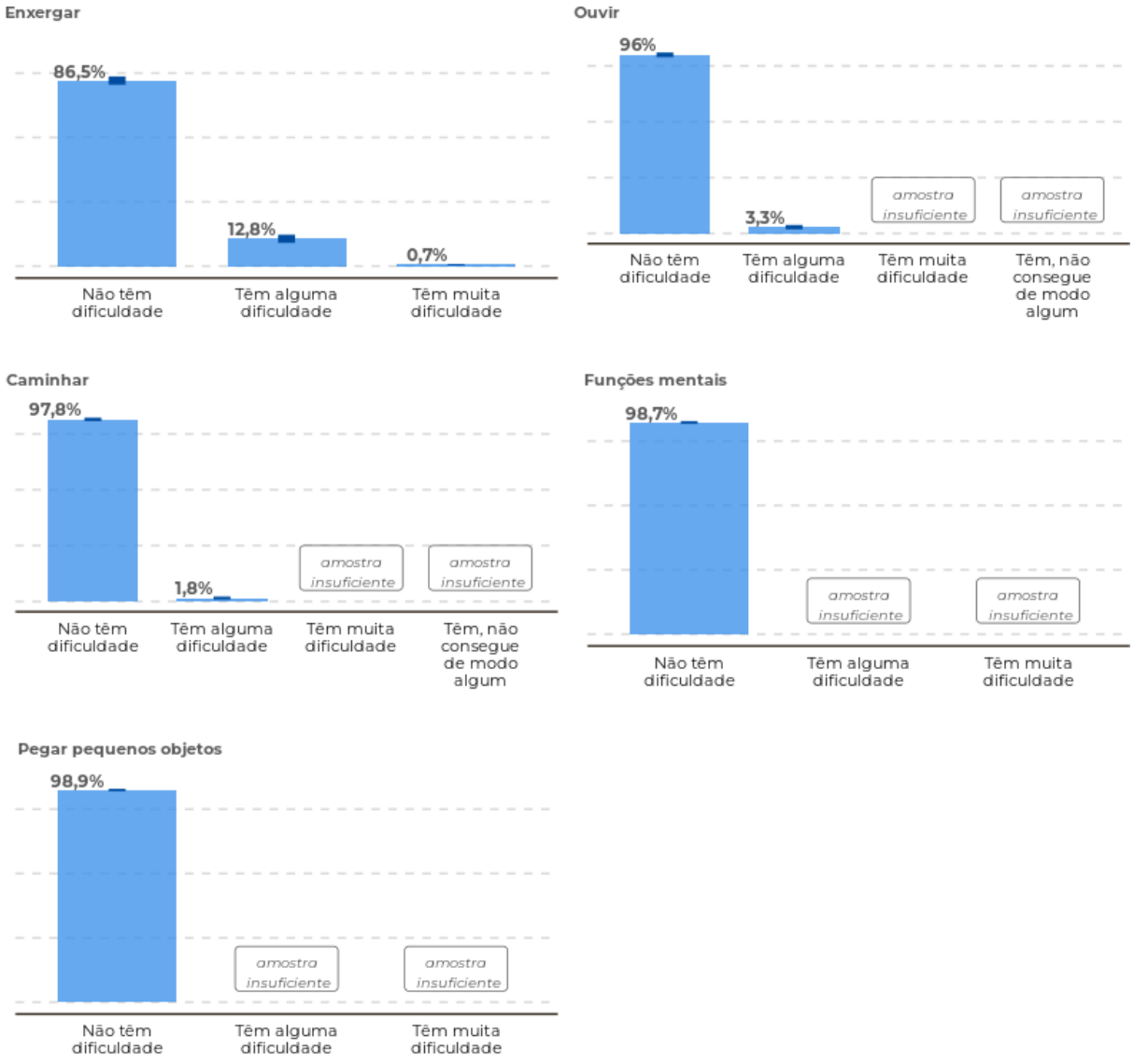

Fonte: CODEPLAN/DIEPS/GEREPS/PDAD 2021

Figura 3.3.2: Distribuição das pessoas com plano de saúde, por tipo de cobertura, Asa Norte, 2021

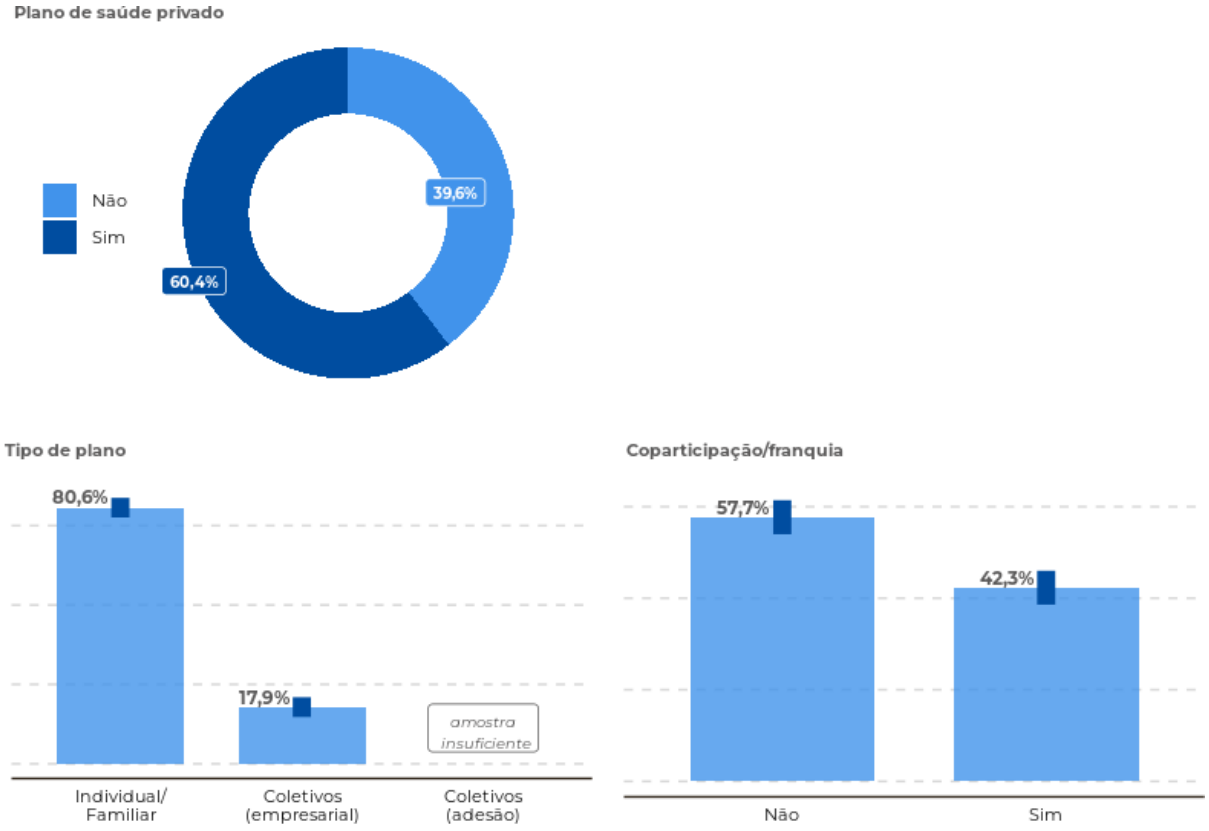

Fonte: CODEPLAN/DIEPS/GEREPS/PDAD 2021

Figura 3.3.3: Último serviço de saúde utilizado, Asa Norte, 2021

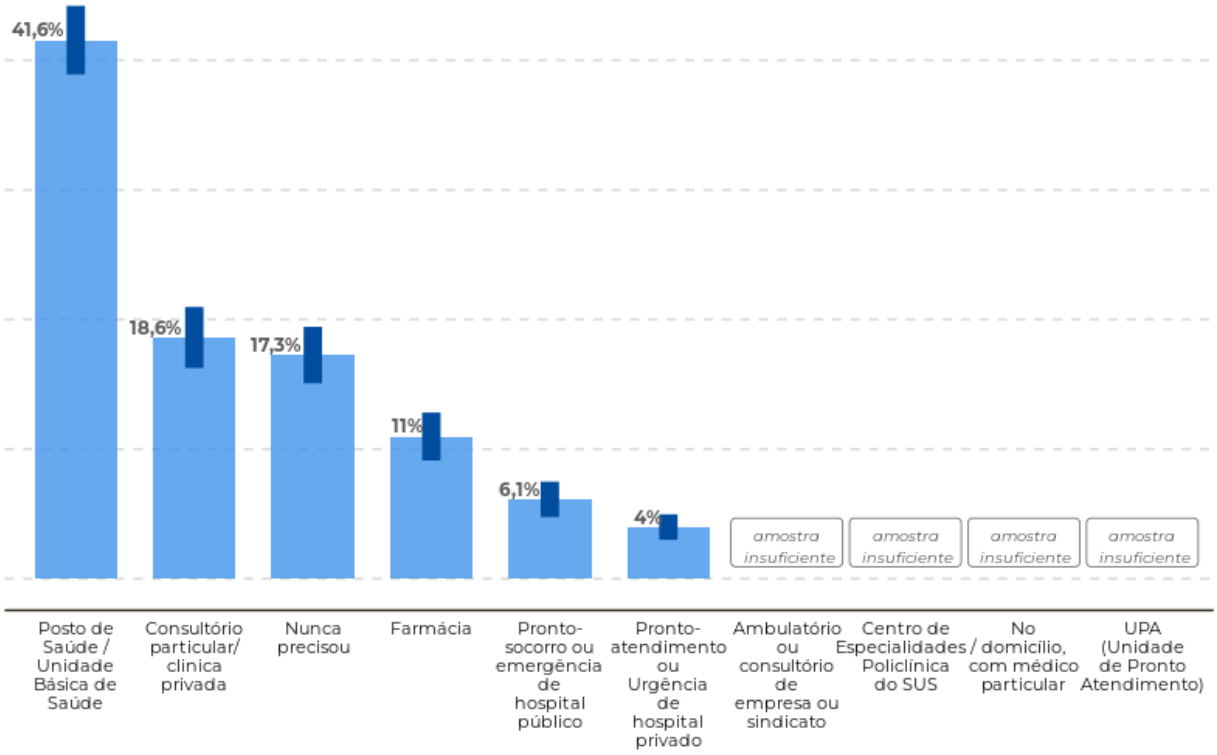

Fonte: CODEPLAN/DIEPS/GEREPS/PDAD 2021
Obs.: São reportadas até o limite das dez maiores categorias

Figura 3.3.4: Motivo do atendimento de saúde, Asa Norte, 2021

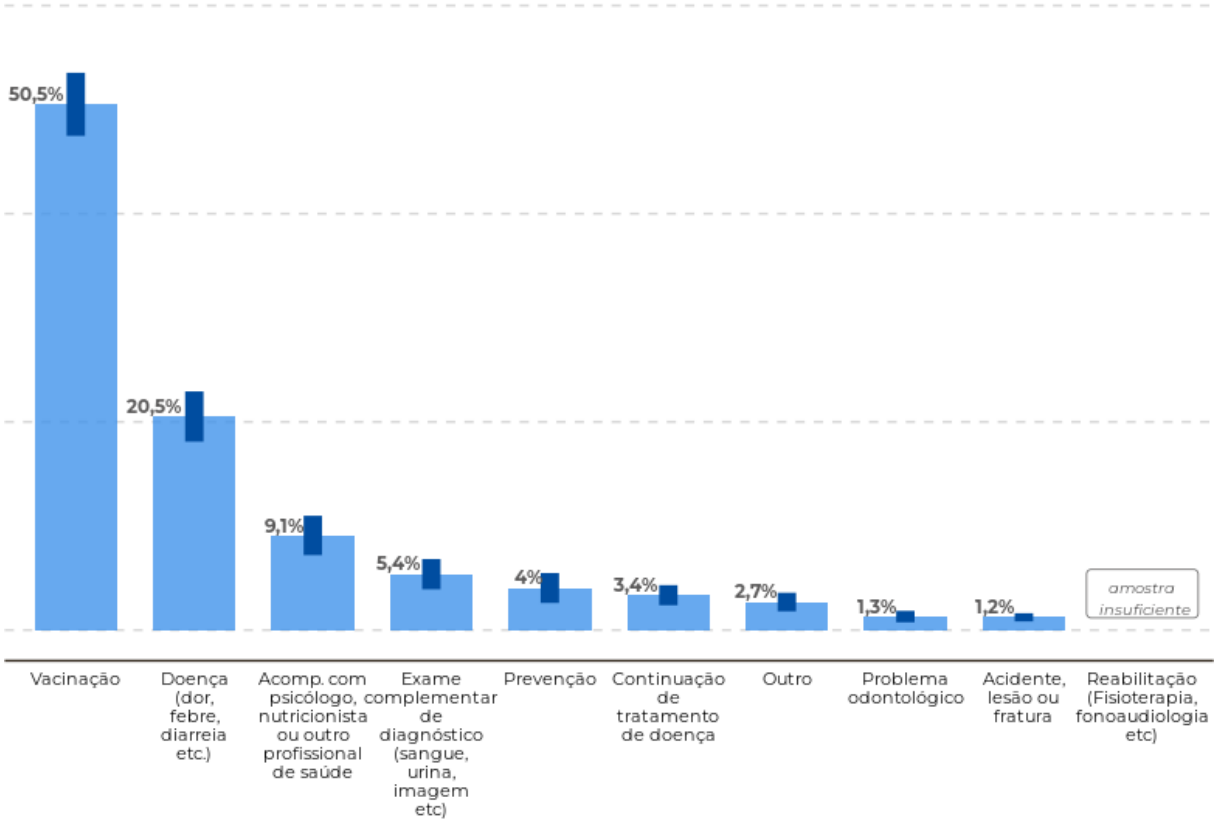

Fonte: CODEPLAN/DIEPS/GEREPS/PDAD 2021
Obs.: São reportadas até o limite das dez maiores categorias.

Figura 3.3.5: Localidade de atendimento do último serviço de saúde utilizado, Asa Norte, 2021



Fonte: CODEPLAN/DIEPS/GEREPS/PDAD 2021
Obs.: São reportadas até o limite das dez maiores categorias.

3.4 Comunicação

Sobre o acesso à comunicação, 92,4% dos entrevistados declararam possuir ao menos um celular para uso pessoal, enquanto 12,5% declararam possuir ao menos um tablet (Figura 3.4.1 e Tabelas A.24 e A.25). Quanto ao tipo de linha, 55,9% afirmaram utilizar pré-paga e 39,4% pós-paga[48] (Figura 3.4.2 e Tabelas A.26 e A.27).

Figura 3.4.1: Posse de celular e tablet para uso pessoal, Asa Norte, 2021

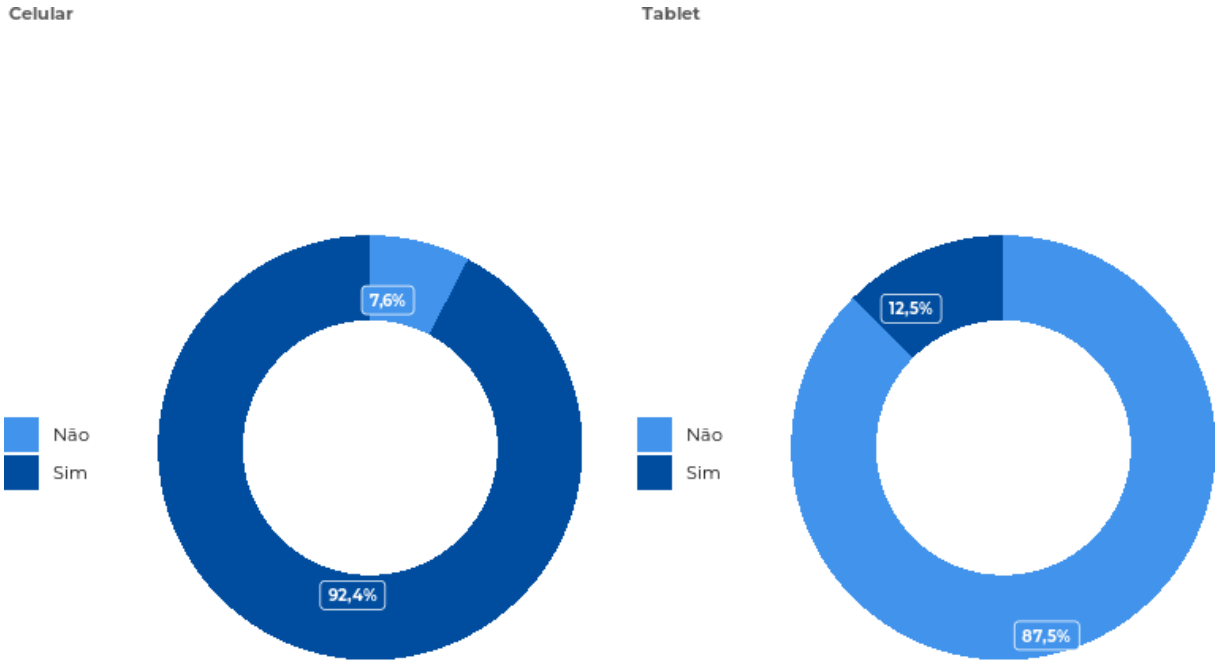

Fonte: CODEPLAN/DIEPS/GEREPS/PDAD 2021

Perguntados se acessaram à internet nos últimos três meses, 91,3% dos entrevistados responderam afirmativamente, dos quais 93,6% acessaram todos os dias. Sobre os meios de acesso, 89,3% se conectaram por meio de microcomputador, 99,6% por meio de celular ou tablet e 88% por outros meios (como televisão, videogame ou outro equipamento eletrônico)[49] (Figuras 3.4.3 e 3.4.4 e Tabelas A.28, A.30, A.31 e A.32).

[48] Um morador poderia ter, simultaneamente, tanto linha pré-paga quanta pós-paga.
[49] O mesmo morador pode ter acessado a internet por mais de um meio.

Figura 3.4.2: Posse de linha pré-paga e pós-paga para uso pessoal, Asa Norte, 2021

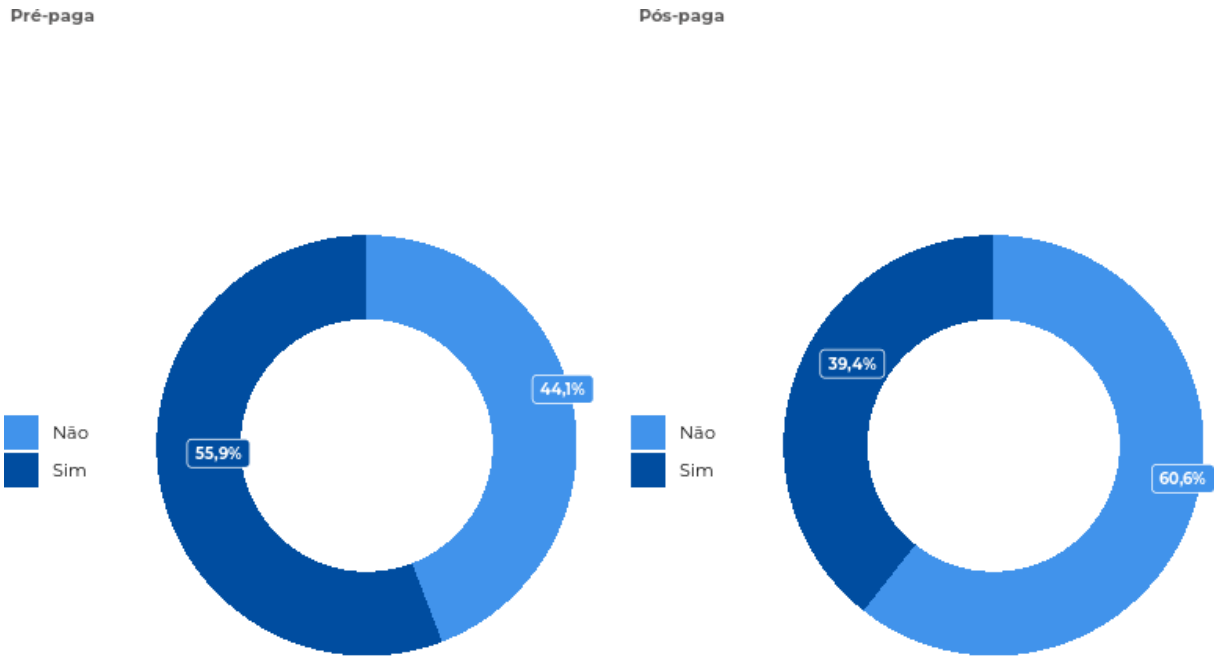

Fonte: CODEPLAN/DIEPS/GEREPS/PDAD 2021

Figura 3.4.3: Acesso à internet e meios de acesso nos últimos três meses, Asa Norte, 2021

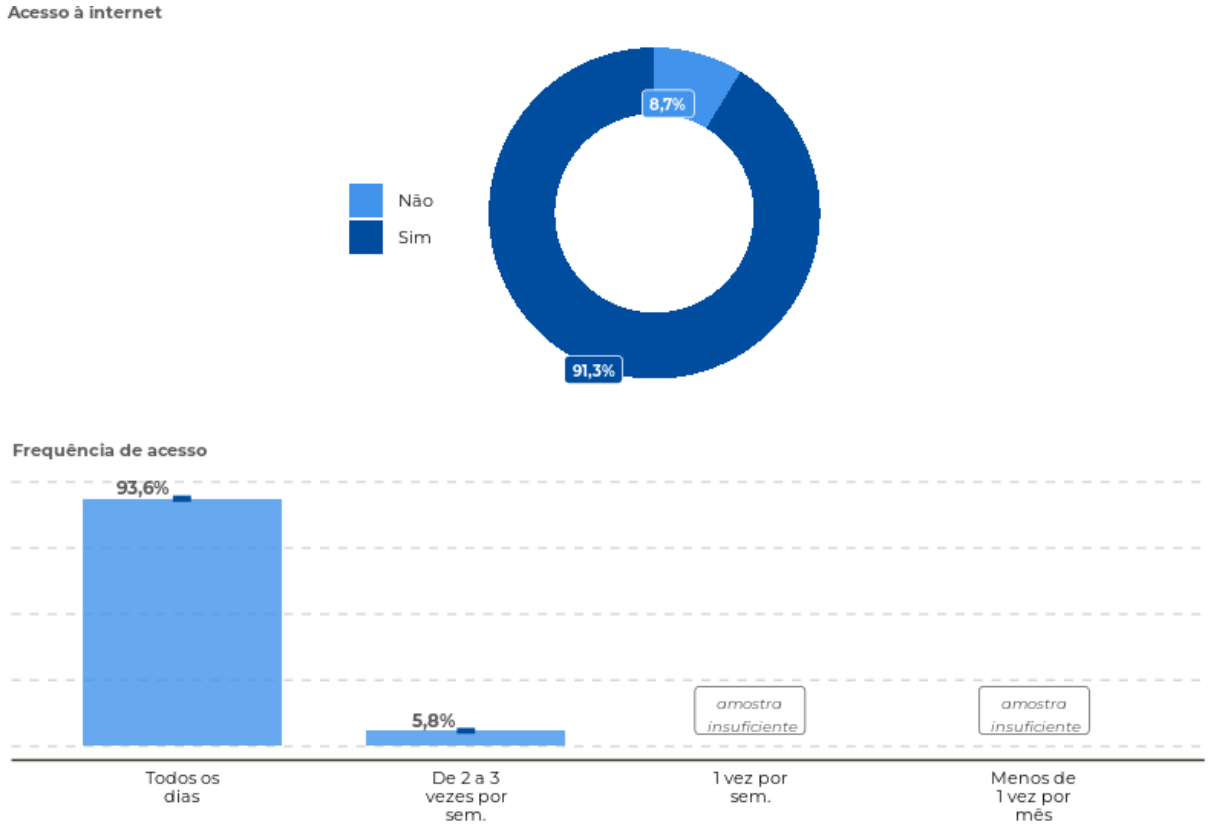

Fonte: CODEPLAN/DIEPS/GEREPS/PDAD 2021

Figura 3.4.4: Meios de acesso nos últimos três meses, Asa Norte, 2021

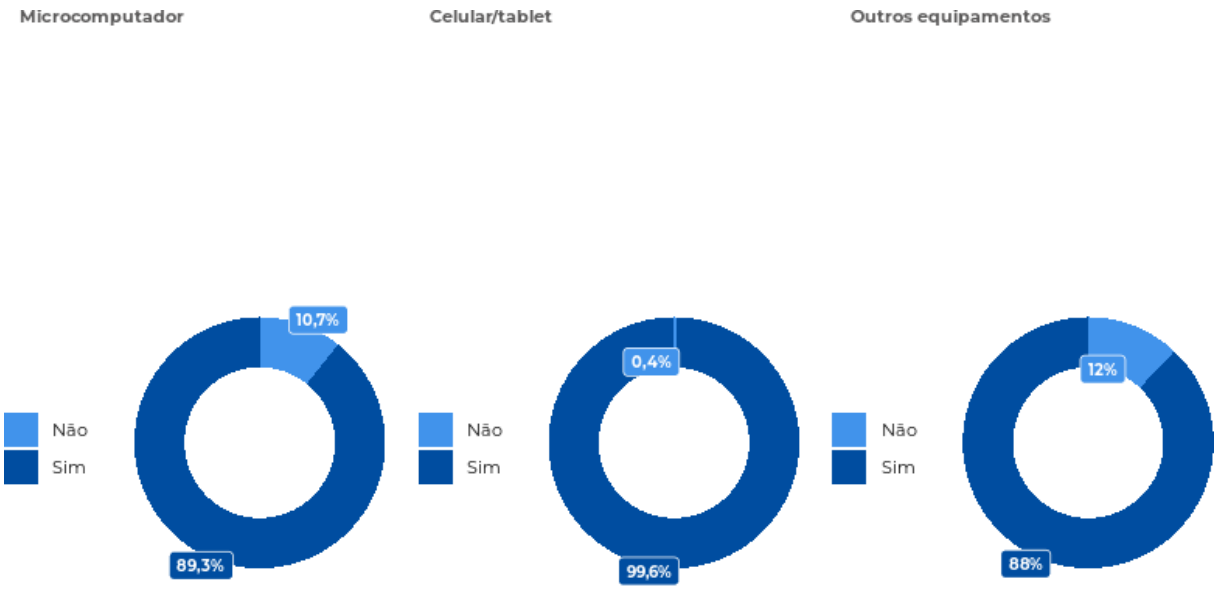

Fonte: CODEPLAN/DIEPS/GEREPS/PDAD 2021

Foram perguntados, ainda, os motivos de acesso à internet, tendo-se as seguintes respostas: 95,5% para comunicação; 94,2% para multimídia, lazer e cultura; 93,7% informações e notícias; 65% criação e compartilhamento de conteúdo; 81,8% para transações financeiras ou comerciais; 68,2% para educação ou cursos; e 63,6% para trabalho (Figura 3.4.5 e Tabelas A.33 até A.39).

Figura 3.4.5: Motivações do acesso à internet, Asa Norte, 2021

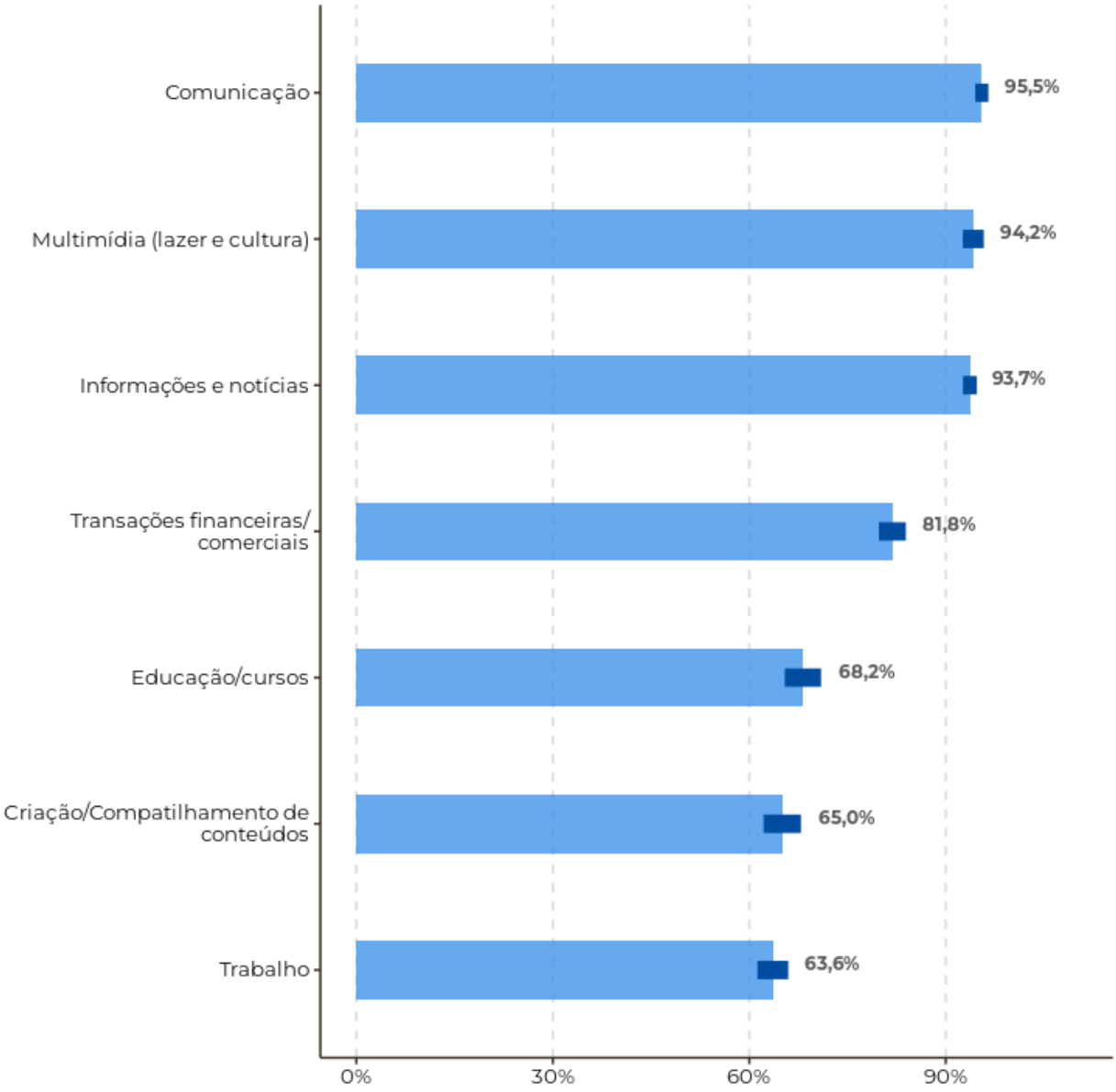

Fonte: CODEPLAN/DIEPS/GEREPS/PDAD 2021

3.5 Escolaridade

Sobre a escolaridade, 99,2% dos moradores com seis anos ou mais de idade declararam saber ler e escrever (Figura 3.5.1 e Tabela A.40)[50]. Para as pessoas entre 4 e 24 anos, 41,2% reportaram frequentar escola particular (Figura 3.5.2 e Tabela A.41). Considerando-se os estudantes de todas as idades, a modalidade predominante era presencial, para 63,4% dos respondentes (Figura 3.5.3 e Tabela A.42), e o turno predominante era matutino (57,4%) (Figura 3.5.4 e Tabela A.43). A frequência escolar, por faixa de idades[51], é apresentada na Figura 3.5.5.

Figura 3.5.1: População com seis anos ou mais de idade que declararam saber ler e escrever, Asa Norte, 2021

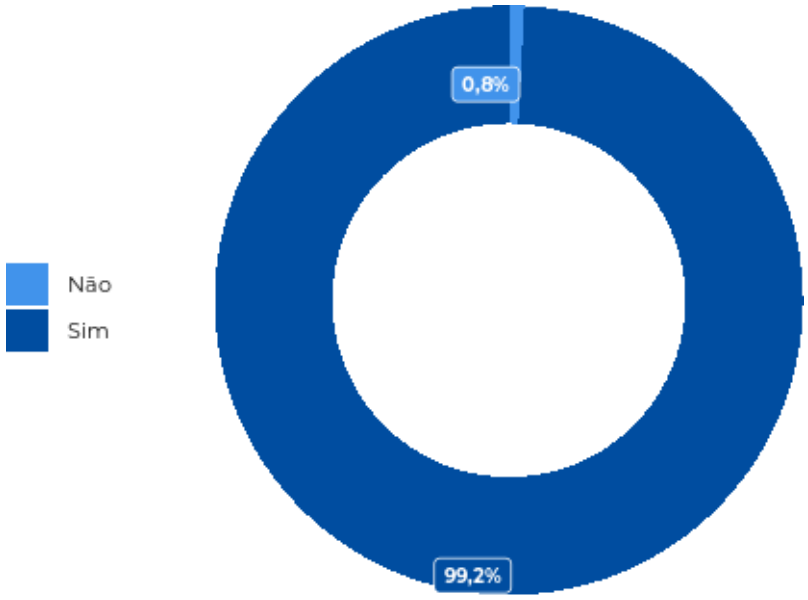

Fonte: CODEPLAN/DIEPS/GEREPS/PDAD 2021

Entre aqueles que frequentavam alguma unidade de ensino, 98,8% estudavam na RA Plano Piloto (Figura 3.5.6 e Tabela A.45). O principal meio de transporte declarado foi automóvel, para 50,3% dos respondentes (Figura 3.5.7 e Tabela A.46). O tempo gasto mais reportado foi até 15 minutos para 56,9% dos estudantes (Figura 3.5.8 e Tabela A.47).

[50] O reporte deste resultado desconsidera quem não sabia responder à questão.

[51] A frequência escolar é obrigatória para crianças a partir de 4 anos completos em 31/03 de cada ano. Como data de nascimento completa não foi captada para todas as crianças, não foi possível fazer o corte para as crianças de 4 anos. Dessa forma, as informações para essas faixas-etárias precisam ser analisadas com cautela.

Figura 3.5.2: Distribuição da frequência escolar da população entre 4 e 24 anos, Asa Norte, 2021

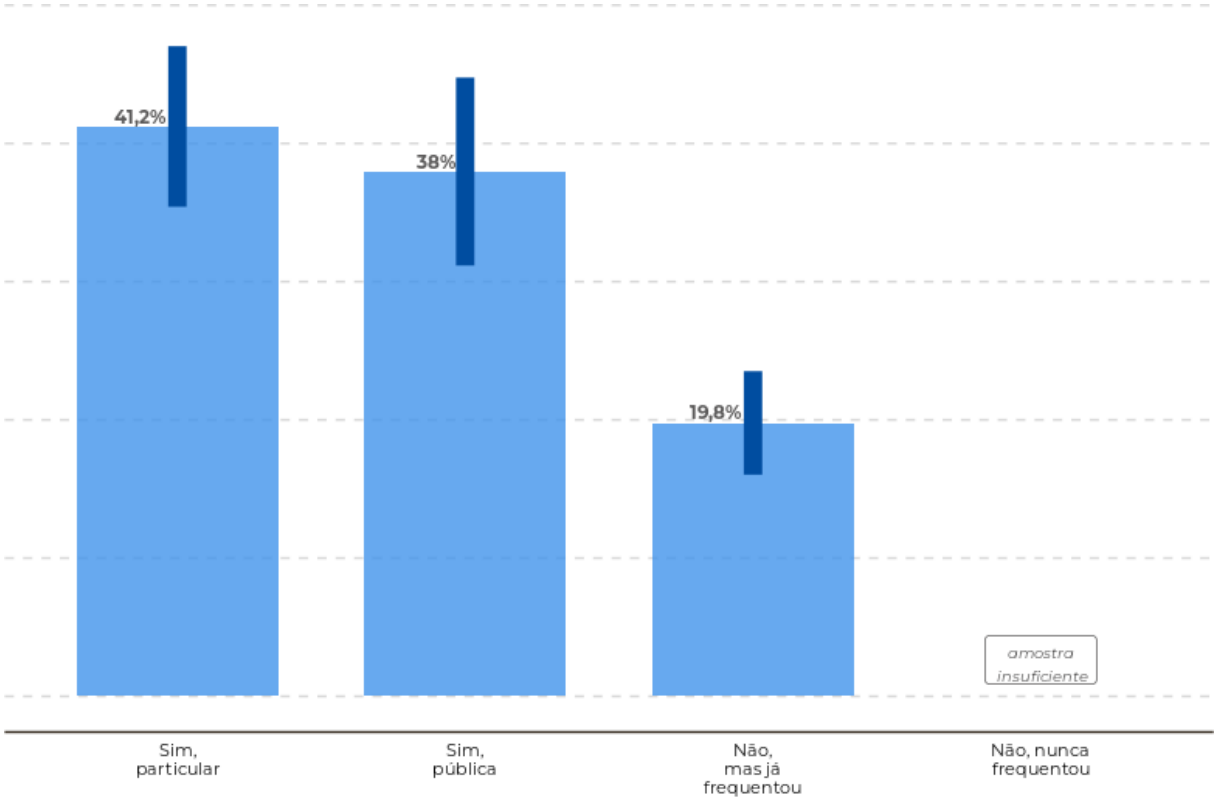

Fonte: CODEPLAN/DIEPS/GEREPS/PDAD 2021

Figura 3.5.3: Distribuição da modalidade de ensino de todos os estudantes, Asa Norte, 2021

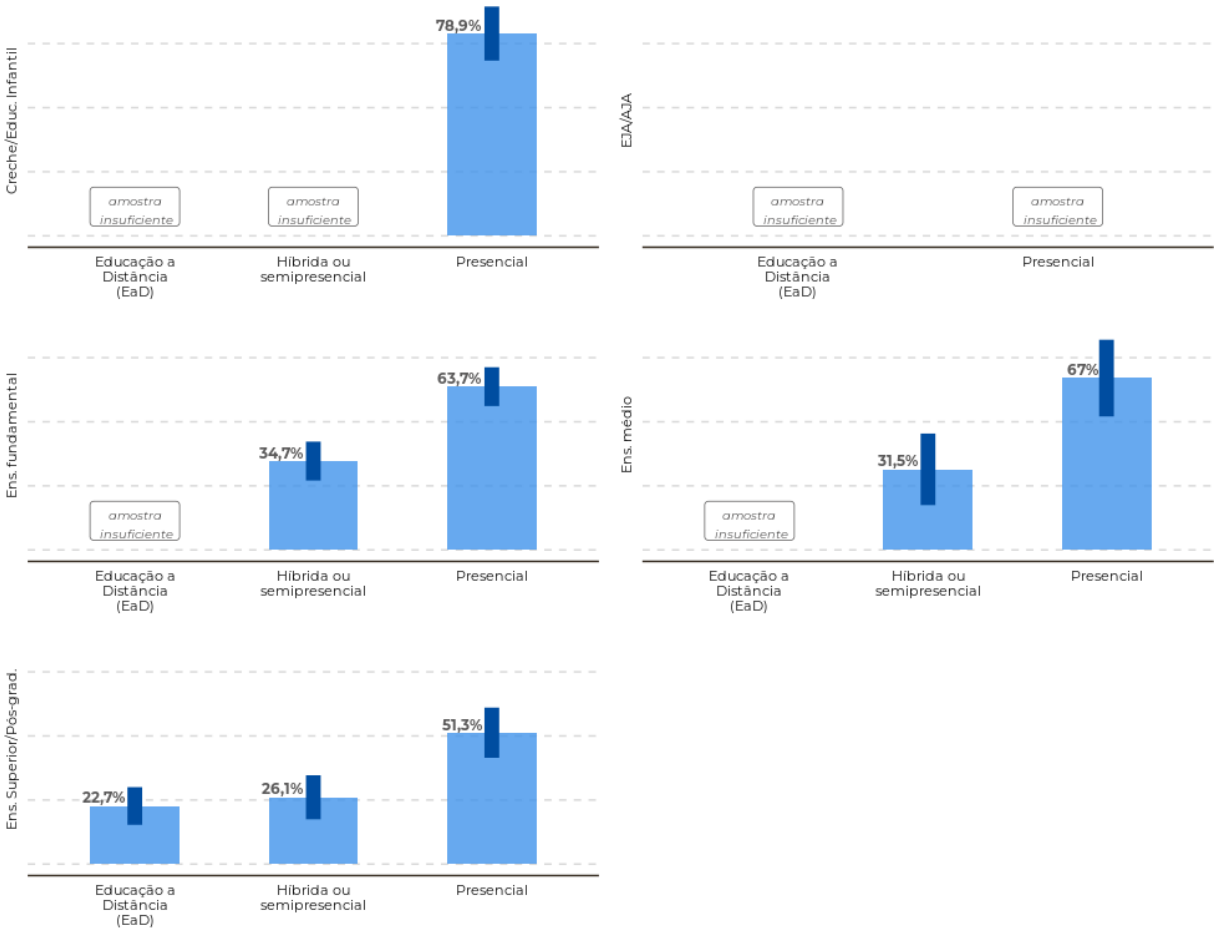

Fonte: CODEPLAN/DIEPS/GEREPS/PDAD 2021

Figura 3.5.4: Distribuição do turno de estudo de todos os estudantes, Asa Norte, 2021

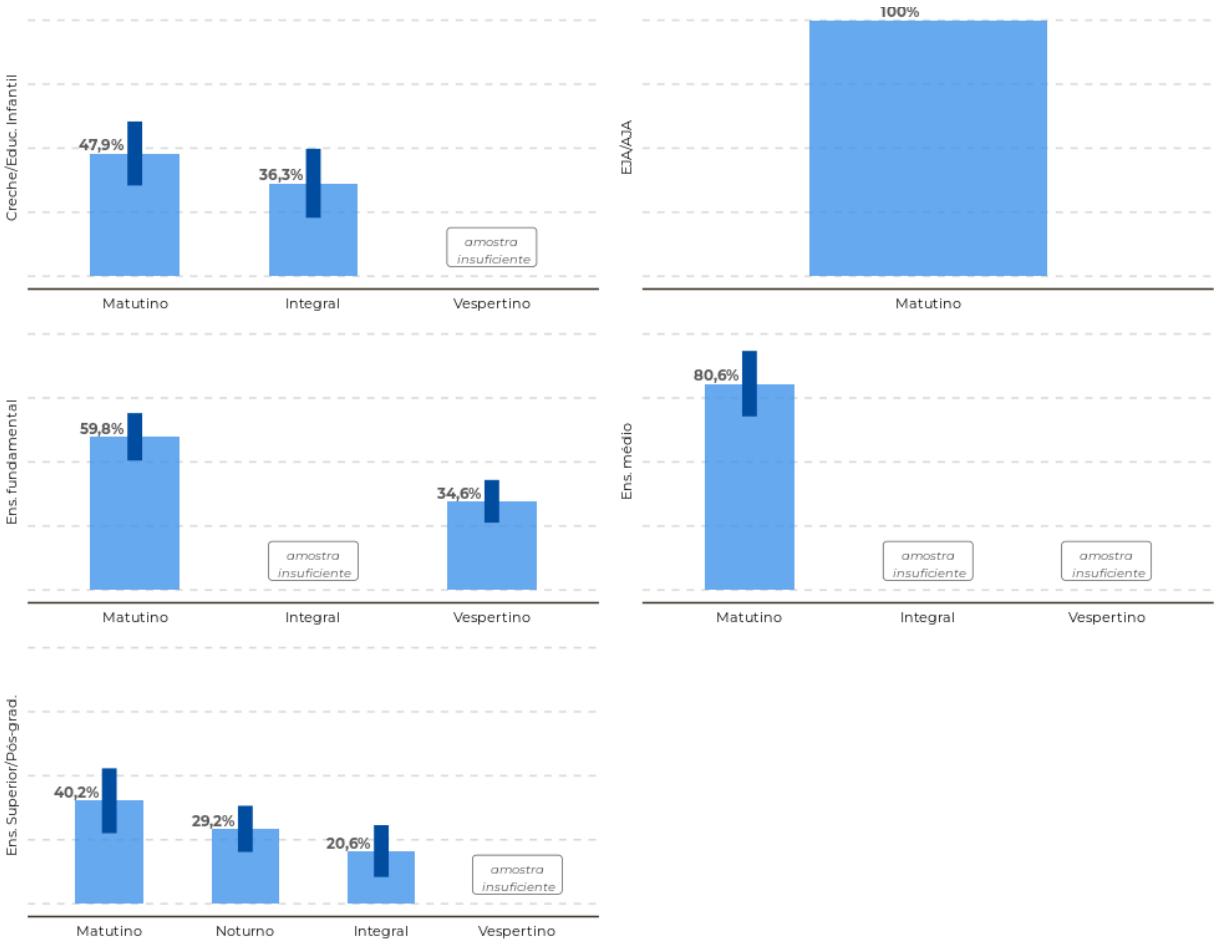

Fonte: CODEPLAN/DIEPS/GEREPS/PDAD 2021

Figura 3.5.5: Distribuição da frequência escolar por faixas de idade, Asa Norte, 2021

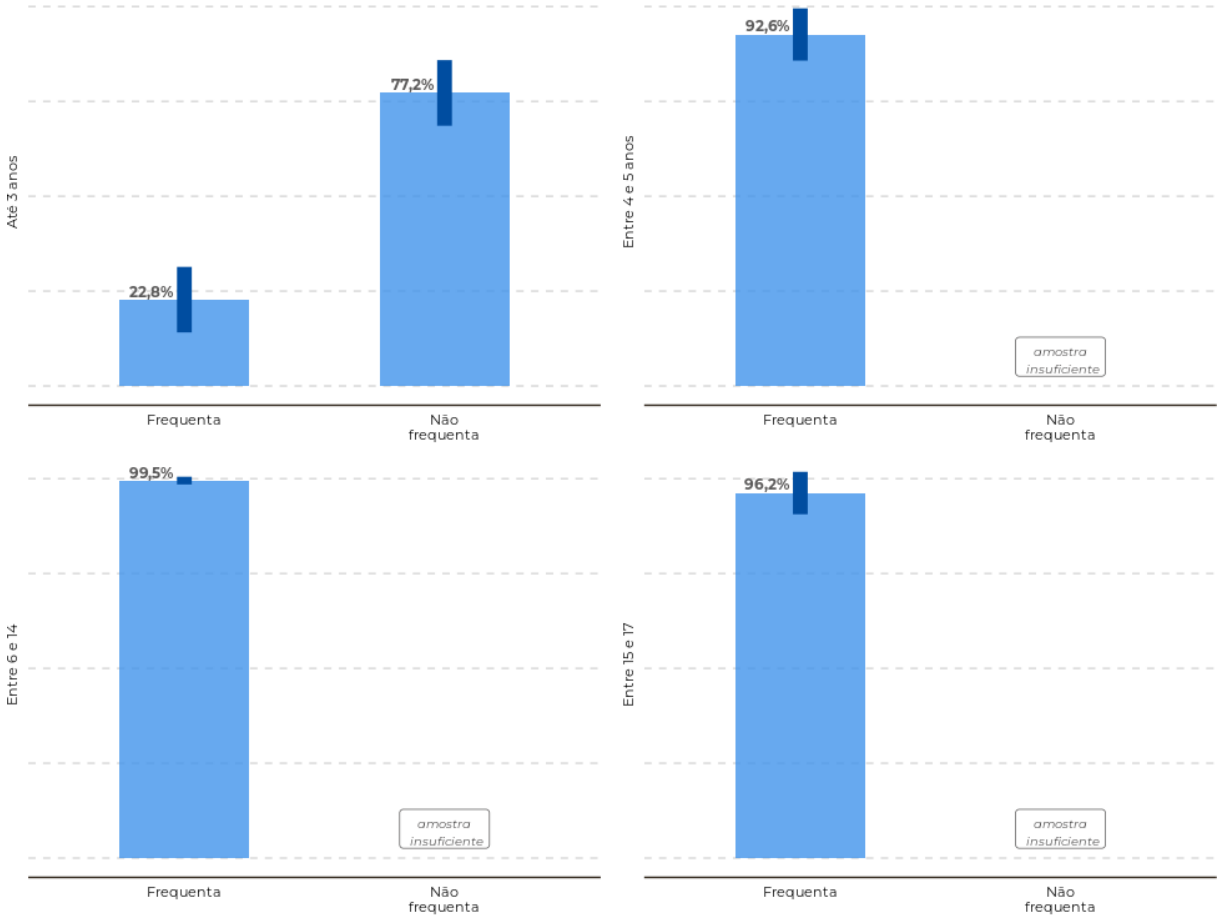

Fonte: CODEPLAN/DIEPS/GEREPS/PDAD 2021

Figura 3.5.6: Região Administrativa/Município da unidade de estudo, Asa Norte, 2021

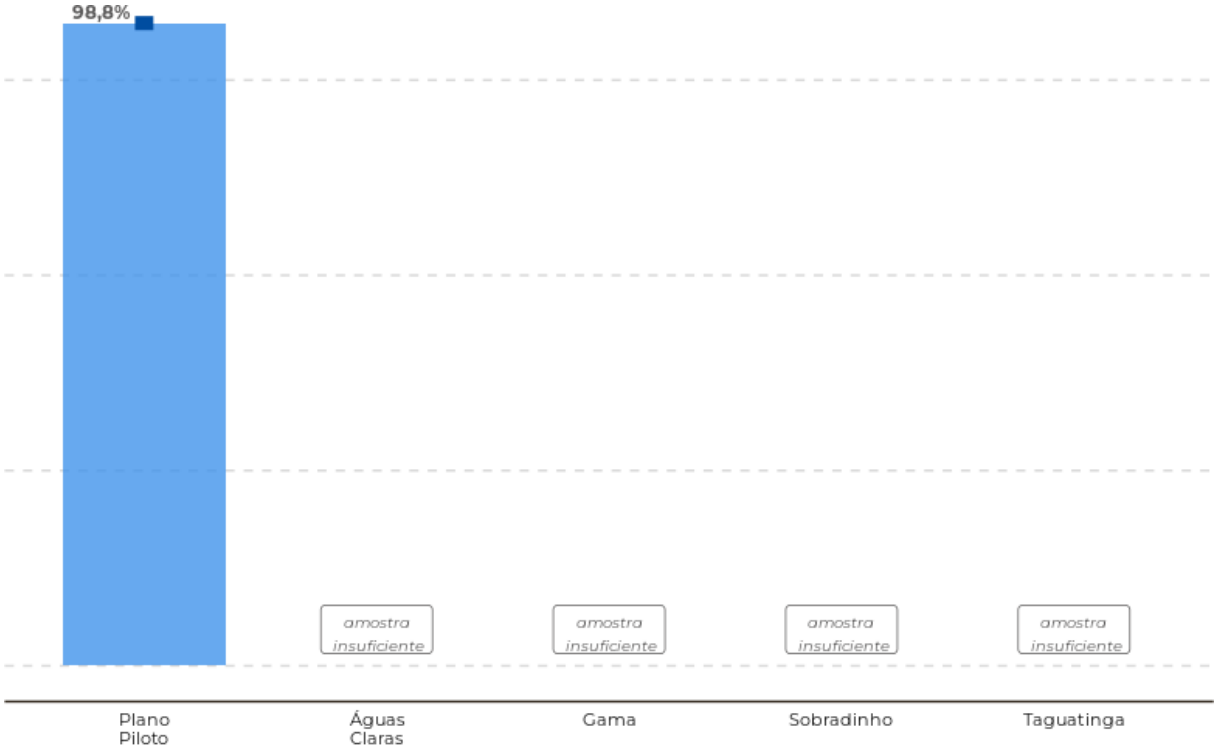

Fonte: CODEPLAN/DIEPS/GEREPS/PDAD 2021
Obs.: São reportadas até o limite das dez maiores categorias.

Figura 3.5.7: Principal meio de transporte da casa até a escola de todos os estudantes, Asa Norte, 2021

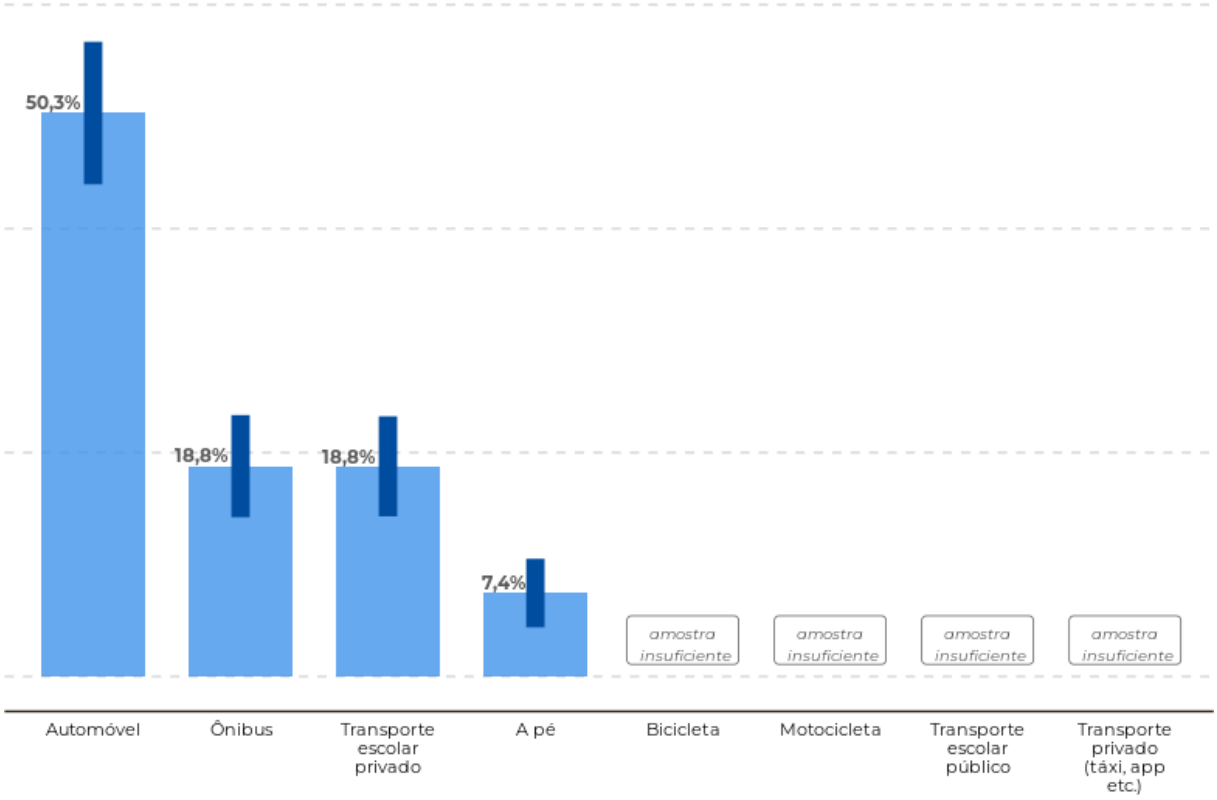

Fonte: CODEPLAN/DIEPS/GEREPS/PDAD 2021

Figura 3.5.8: Tempo de deslocamento da casa até a escola de todos os estudantes, Asa Norte, 2021

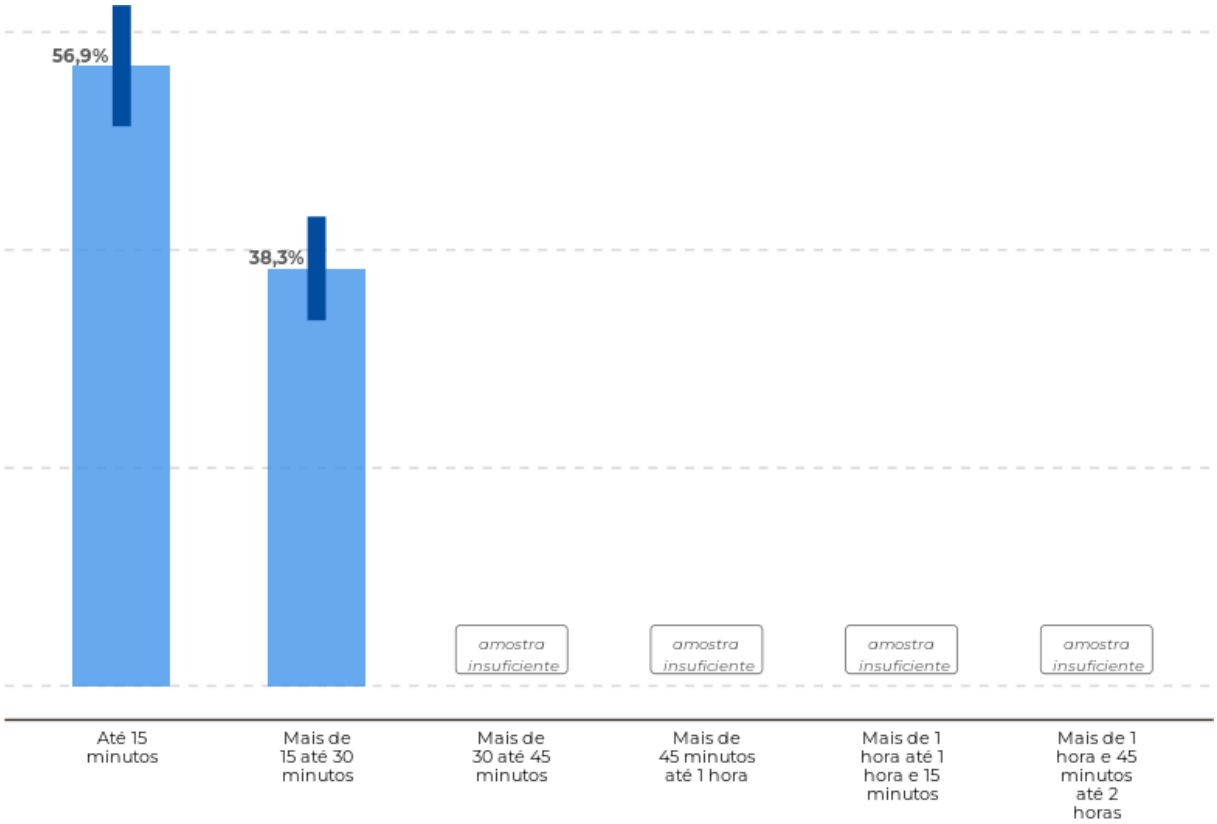

Fonte: CODEPLAN/DIEPS/GEREPS/PDAD 2021

Por fim, no que diz respeito à escolaridade das pessoas com 25 anos ou mais, 73,9% declararam ter o ensino superior completo (Figura 3.5.9 e Tabela A.48).

Figura 3.5.9: Escolaridade da população com 25 anos ou mais, Asa Norte, 2021

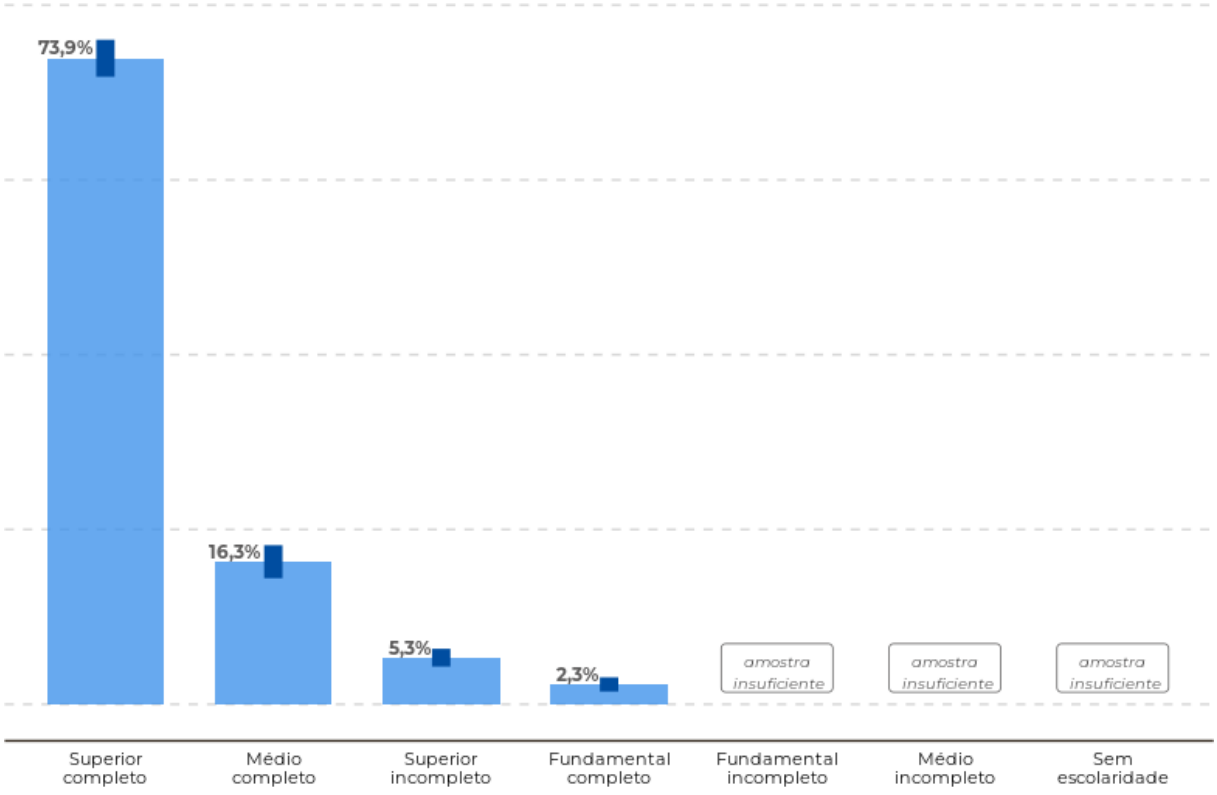

Fonte: CODEPLAN/DIEPS/GEREPS/PDAD 2021

3.6 Trabalho

Considerando as pessoas com 14 anos ou mais, também conhecida como população em idade ativa (PIA), 57% estavam economicamente ativas, isto é, ocupadas ou desocupadas[52] (59.609 pessoas, Figura 3.6.1). Tendo como referência o período dos últimos 30 dias[53], a população desocupada compreendeu 3,4% dessa mesma faixa etária (1998 pessoas) (Figura 3.6.1).

Figura 3.6.1: Taxa de participação das pessoas em idade ativa (14 anos ou mais de idade), Asa Norte, 2021

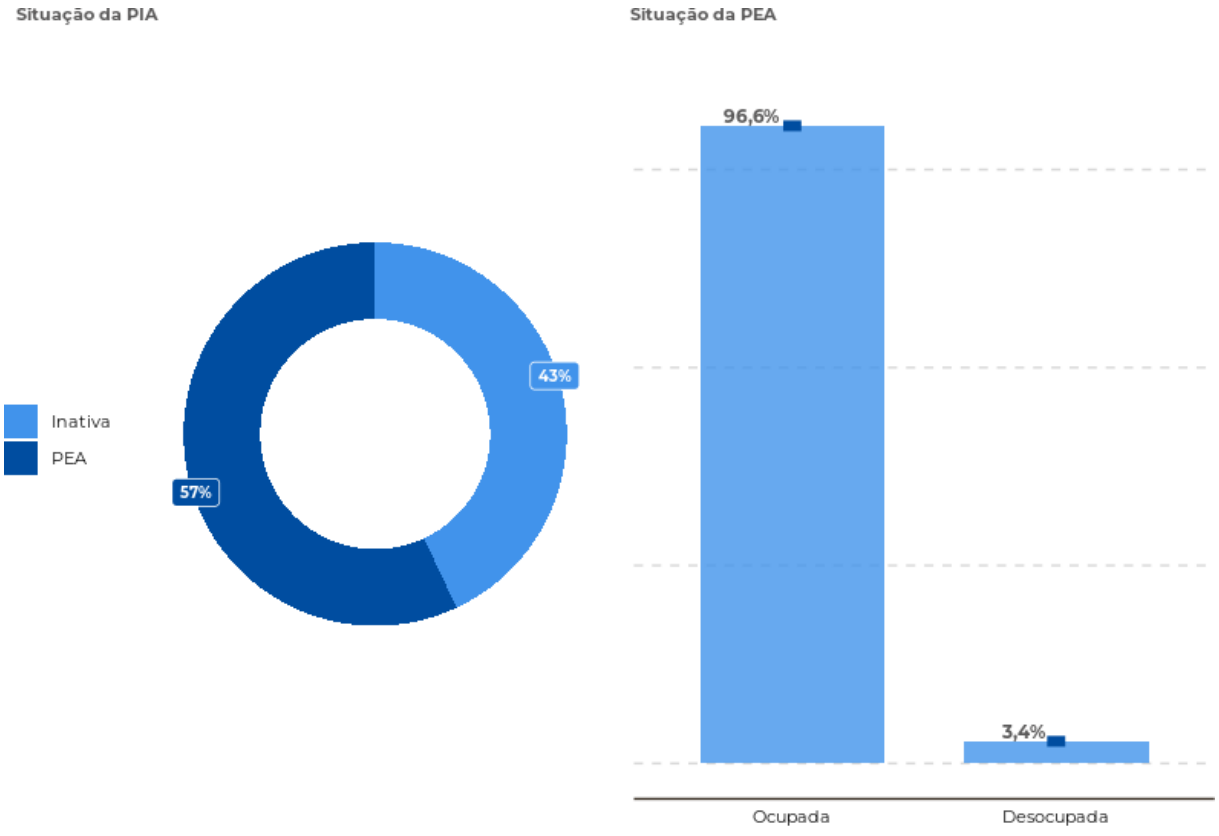

Fonte: CODEPLAN/DIEPS/GEREPS/PDAD 2021

Uma questão relevante para o mercado de trabalho diz respeito à parcela da população que não estuda, nem trabalha, os chamados "nem-nem". Para a população entre 18 e 29 anos, 22,9% se encontravam nesta situação (3.820 jovens). Considerando-se entre os nem-nem apenas aqueles jovens

[52] São classificadas como desocupadas as pessoas que não tinham trabalho, mas procuraram por uma ocupação no período considerado.
[53] A partir da data da entrevista.

que procuraram trabalho, tinha-se 2,7% (458 jovens)[54] (Figura 3.6.2 e Tabela A.52).

Figura 3.6.2: População de 18 a 29 anos por situação de trabalho e estudo, Asa Norte, 2021

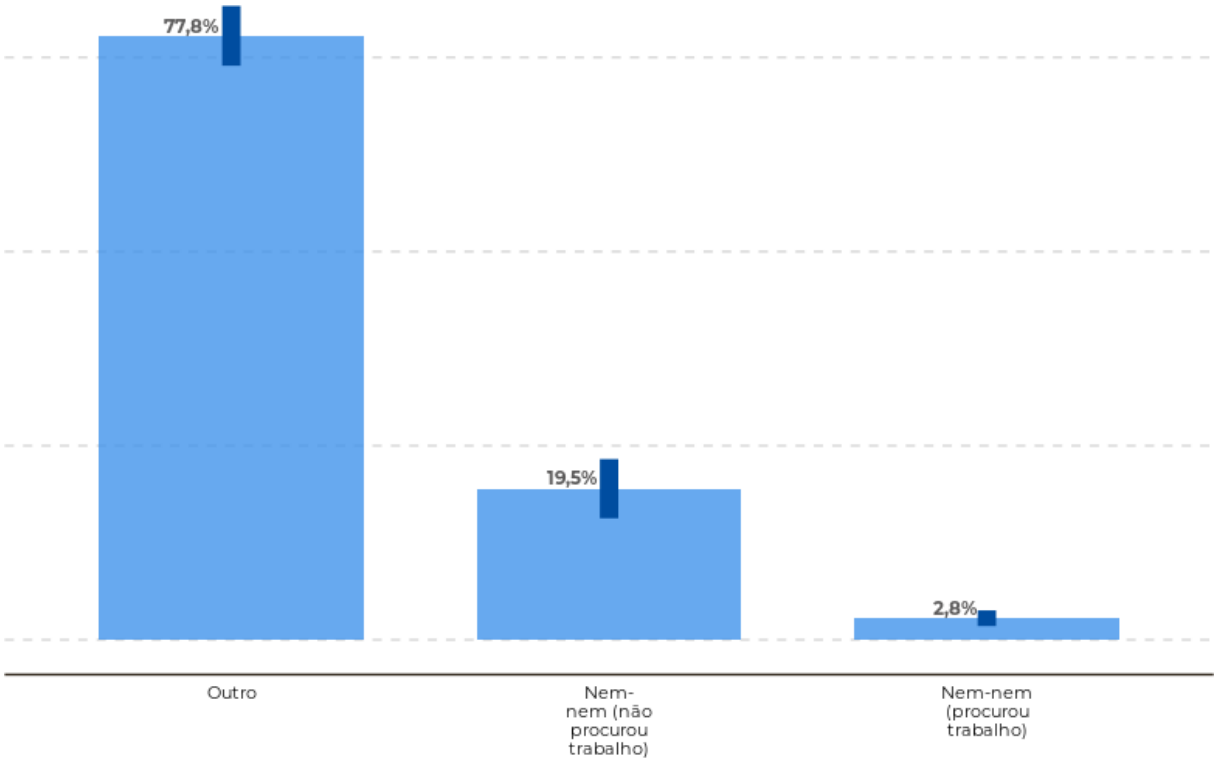

Fonte: CODEPLAN/DIEPS/GEREPS/PDAD 2021

Para os ocupados, foi questionada a atividade da empresa em que estes exerciam o seu trabalho principal, sendo o setor de Outros Serviços o mais informado, segundo 52,4% dos respondentes (Figura 3.6.4 e Tabela A.55). A Região Administrativa onde a maioria dos respondentes declarou exercer seu trabalho principal foi Plano Piloto (95,7%, Tabela A.54 e Figura 3.6.3). Finalmente, a posição na ocupação mais comum foi empregado no setor privado (exceto doméstico), para 49,3% dos entrevistados (Figura 3.6.5 e Tabela A.56). Em média, os trabalhadores estavam há 10,2 anos na ocupação principal, e trabalhavam 39,2 horas por semana.

Sobre os trabalhadores do setor público, a principal área de atuação era federal (78,4%) e era estatutário (67,5%) (Figura 3.6.6 e Tabelas A.57 e A.58).

[54] Para alguns respondentes não foi possível determinar a procura por trabalho devido à ausência de resposta positiva ou negativa para esta pergunta.

Figura 3.6.3: Local onde as pessoas exerciam seu trabalho principal, Asa Norte, 2021

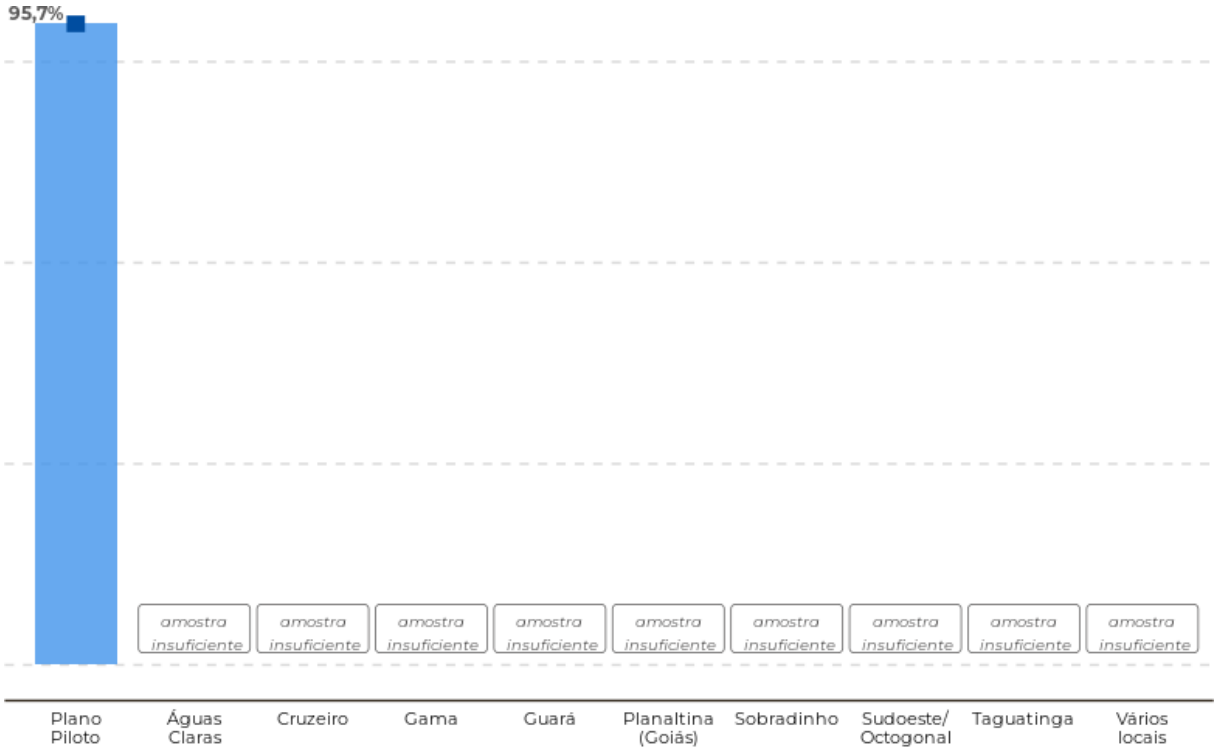

Fonte: CODEPLAN/DIEPS/GEREPS/PDAD 2021
Obs.: São reportadas até o limite das dez maiores categorias.

Figura 3.6.4: Distribuição do setor de atividade da empresa em que as pessoas exerciam seu trabalho principal, Asa Norte, 2021

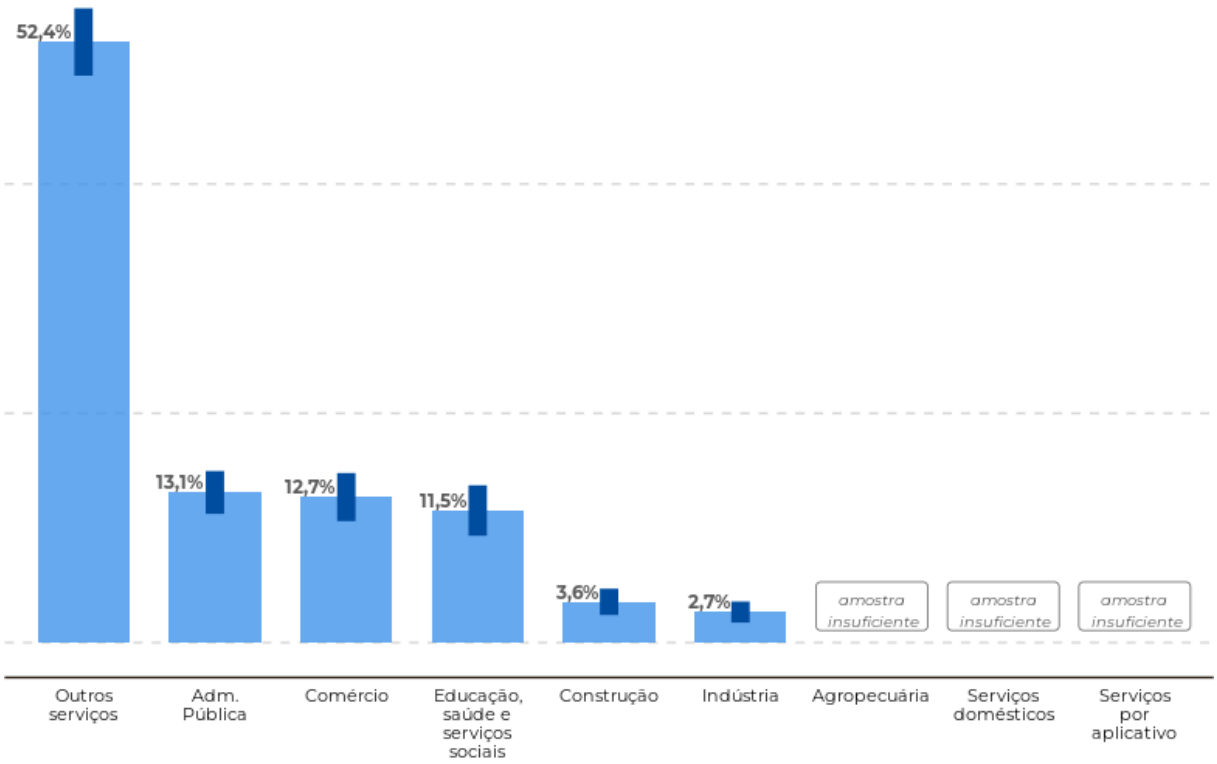

Fonte: CODEPLAN/DIEPS/GEREPS/PDAD 2021

Figura 3.6.5: Distribuição da posição na ocupação principal, Asa Norte, 2021

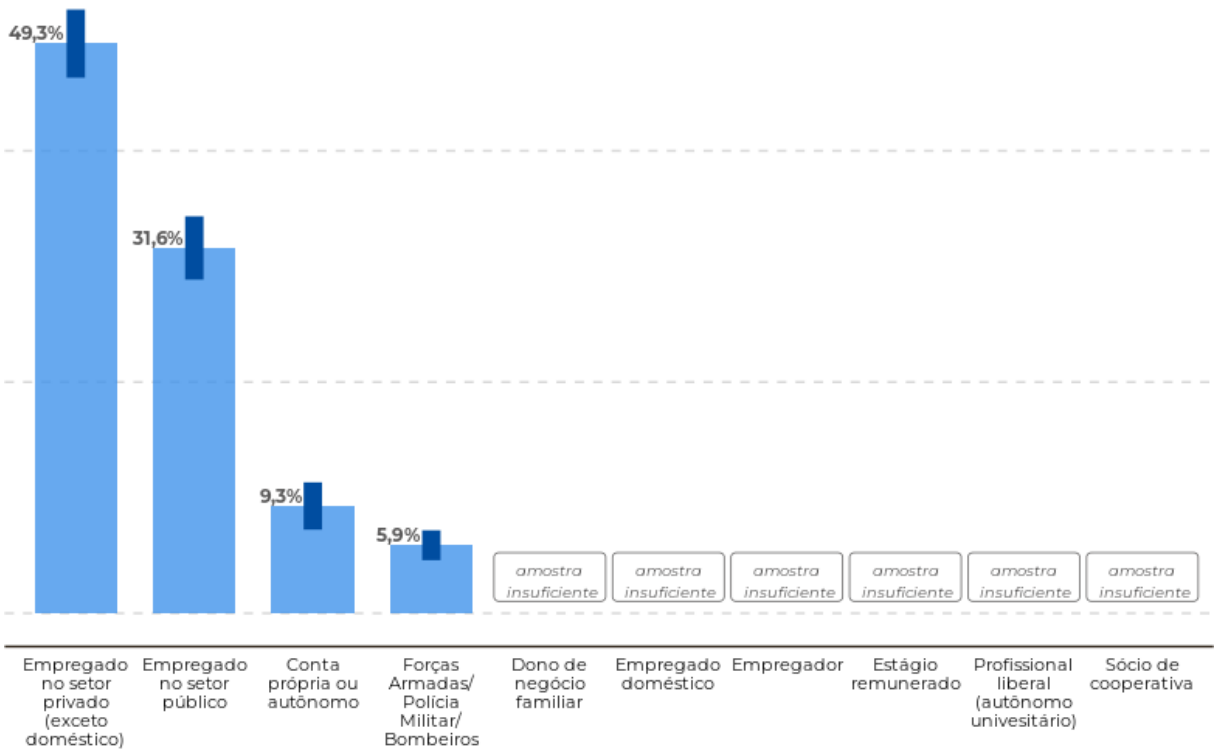

Fonte: CODEPLAN/DIEPS/GEREPS/PDAD 2021
Obs.: São reportadas até o limite das dez maiores categorias.

Figura 3.6.6: Área de atuação e modalidade de contratação dos servidores/empregados públicos, Asa Norte, 2021

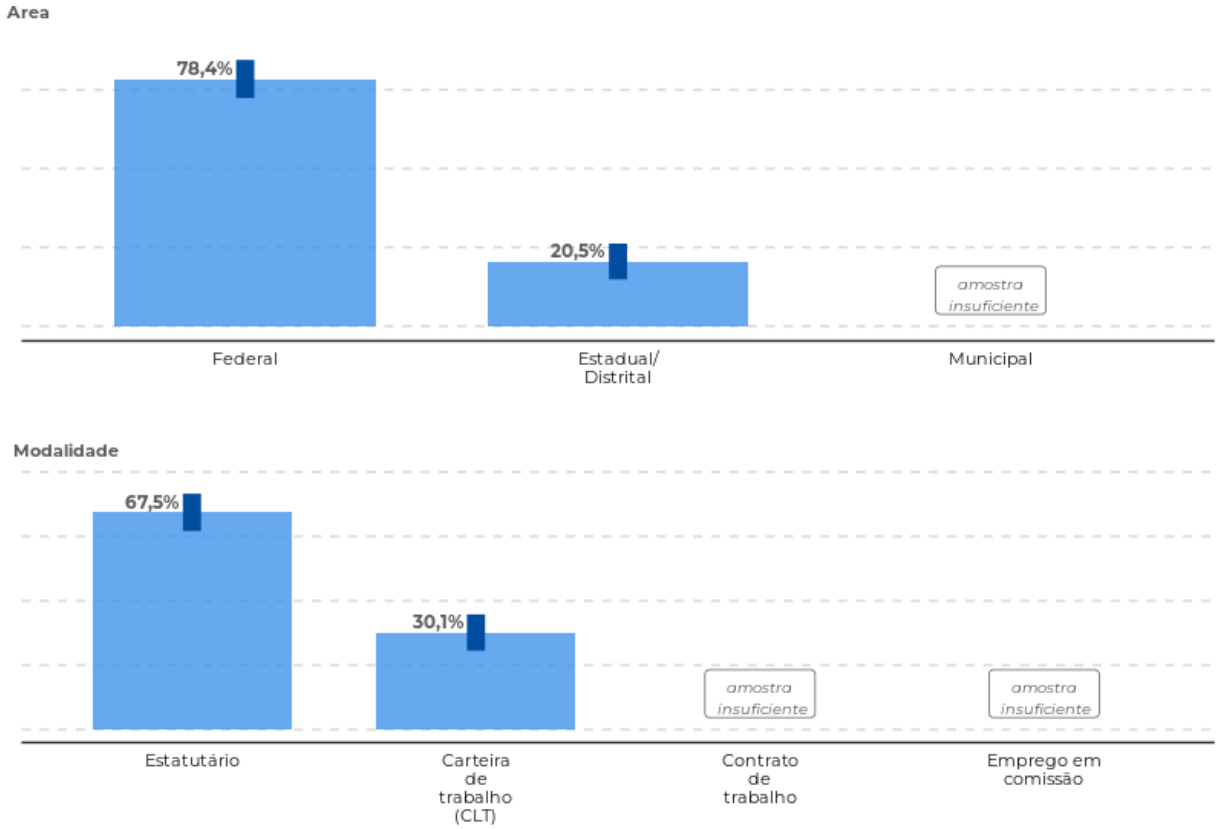

Fonte: CODEPLAN/DIEPS/GEREPS/PDAD 2021

Sobre os empreendedores (sócios de cooperativas, autônomos, empregadores, donos de negócios familiares e profissionais liberais), 46,1% eram microempreendedores individuais (MEI) e 70,6% possuíam Cadastro Nacional de Pessoa Jurídica (CNPJ) (Figura 3.6.7 e Tabelas A.59 e A.60).

Figura 3.6.7: Empreendedores segundo cadastro de Microempreendedores Individuais (MEI) e Cadastro Nacional de Pessoa Jurídica (CNPJ), Asa Norte, 2021

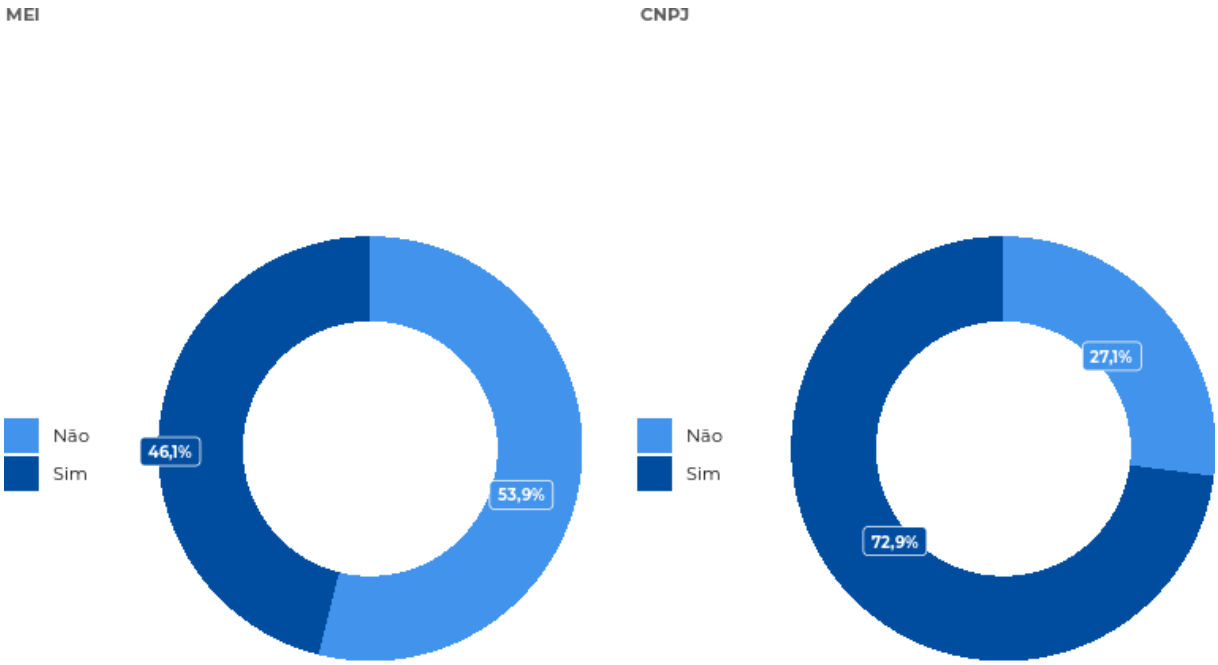

Fonte: CODEPLAN/DIEPS/GEREPS/PDAD 2021

No que tange ao deslocamento para o trabalho, 22,2% responderam utilizar ônibus, 80,4% informaram utilizar automóvel, 9,8% relataram utilizar transporte privado (empresa de aplicativo, táxi, fornecido pela empresa etc.), 2,8% disseram utilizar motocicleta e 5,2% caminhavam até a localidade laboral (Figura 3.6.8 e Tabela A.61). Dentre estes, o principal meio de transporte reportado foi automóvel, segundo 74% dos entrevistados. Sobre a duração deste trajeto, até 15 minutos foi o tempo de deslocamento mais reportado (56,8% dos respondentes, Figura 3.6.9 e Tabela A.63).

Sobre a formalização dos assalariados privados, 94,7% informaram ter

Figura 3.6.8: Meios de transporte utilizados para deslocamento até o trabalho principal, Asa Norte, 2021

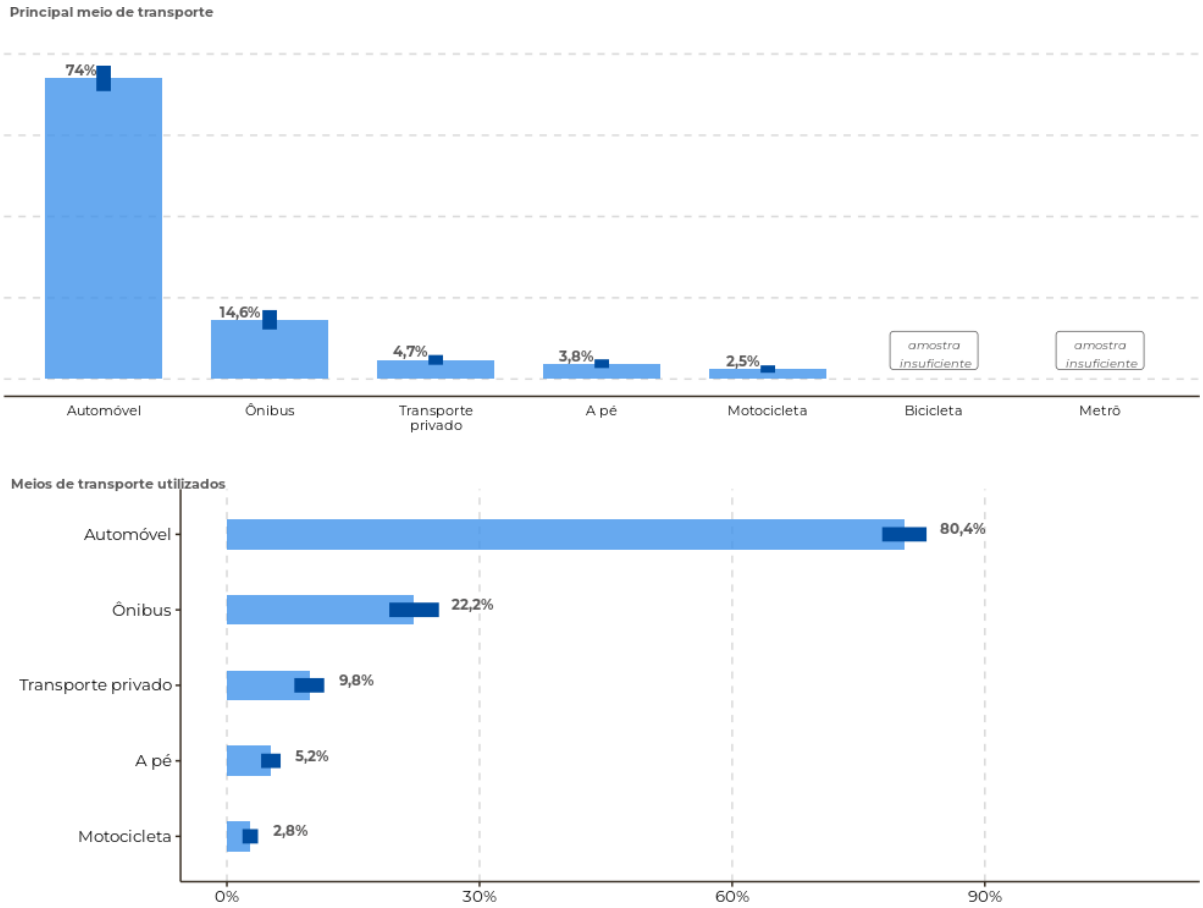

Fonte: CODEPLAN/DIEPS/GEREPS/PDAD 2021

Figura 3.6.9: Tempo para deslocamento até o trabalho principal, Asa Norte, 2021

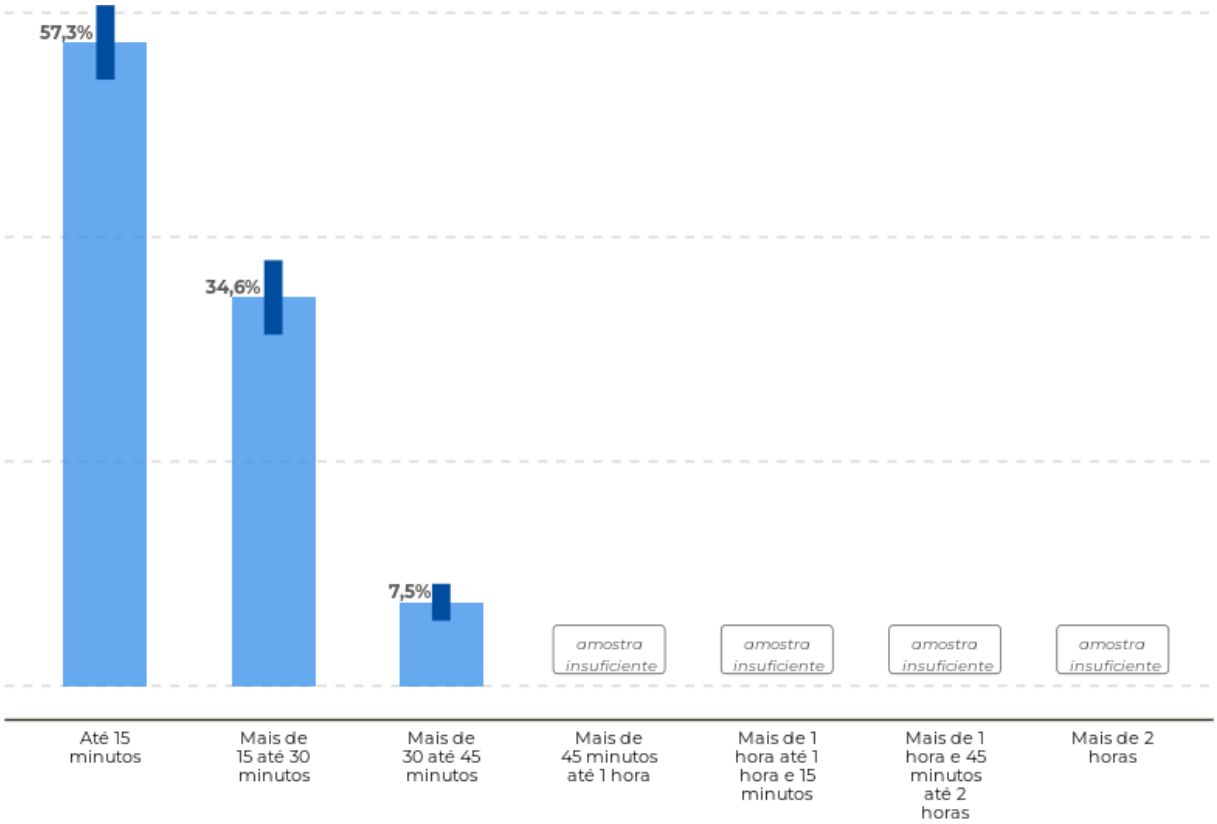

Fonte: CODEPLAN/DIEPS/GEREPS/PDAD 2021

carteira de trabalho assinada pelo atual empregador[55]. Sobre a cobertura da previdência social pública (INSS), 98,1% dos assalariados privados declararam fazer contribuição[56] (Figura 3.6.10 e Tabelas A.64 e A.65).

Figura 3.6.10: Distribuição dos assalariados privados segundo posse de carteira de trabalho assinada (CTPS) e contribuição ao INSS, Asa Norte, 2021

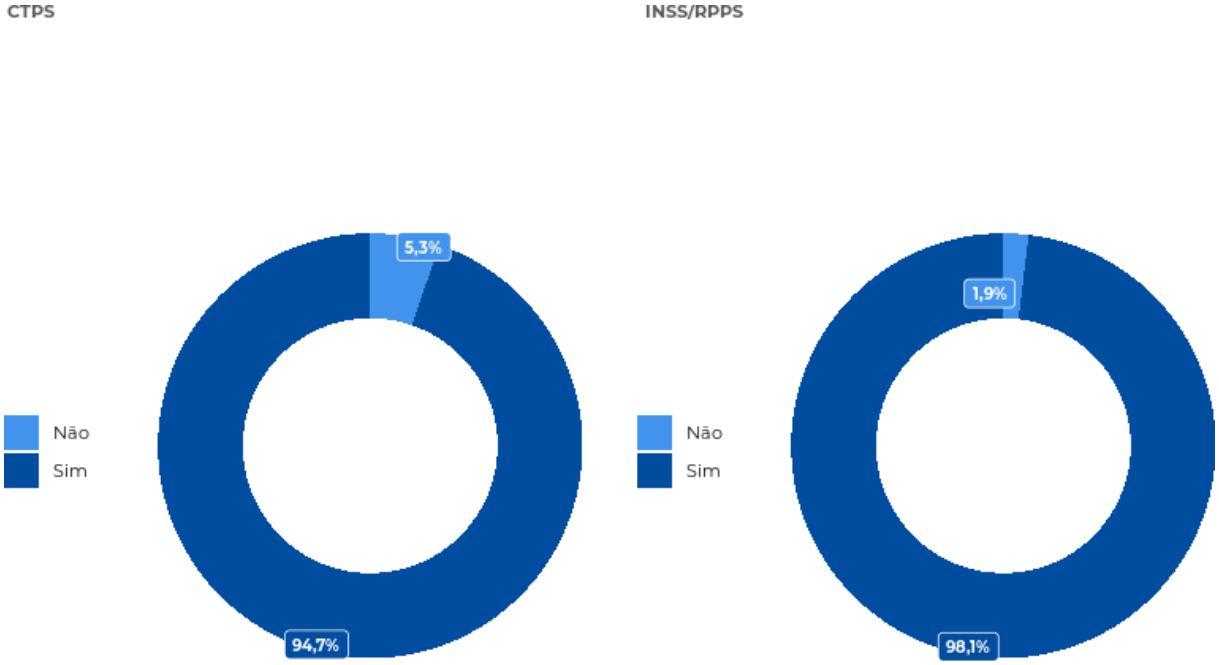

Fonte: CODEPLAN/DIEPS/GEREPS/PDAD 2021

[55] Para este resultado foram desconsideradas as pessoas que não souberam responder e aquelas que disseram não ter carteira assinada por serem funcionários públicos.

[56] Para este resultado foram considerados os empregados no setor privado, trabalhadores domésticos, religiosos remunerados e aprendizes.

3.7 Rendimento

No que diz respeito à remuneração de trabalho principal, o valor[57] médio observado foi de R$ 7.964,86. No que tange à desigualdade, o coeficiente de Gini[58] para esta remuneração foi de 0,41. De modo a ampliar a análise da distribuição desta renda, a Figura 3.7.2 apresenta a curva de Lorenz, que descreve a relação entre a proporção da renda e de pessoas de maneira cumulativa[59].

Já a renda domiciliar[60] estimada foi de R$ 11.012,60, que resulta em um valor médio por pessoa de R$ 5.985,20. Quanto à desigualdade, o índice de Gini da renda domiciliar foi de 0,44, enquanto para a renda por pessoa foi de 0,43 (a Figura 3.7.4 apresenta a curva de Lorenz desta renda).

A Figura 3.7.1 apresenta a distribuição do rendimento bruto do trabalho principal por faixas de salário mínimo (considerando o valor de 2021, de R$ 1.100,00), enquanto a Figura 3.7.3 apresenta a renda domiciliar para estas mesmas faixas. Essas informações estão também nas Tabelas A.60 e A.67, respectivamente.

[57] Todos valores monetários foram corrigidos pelo Índice Nacional de Preços ao Consumidor Amplo – IPCA, de Brasília, calculado pelo IBGE, tendo como referência o mês de julho de 2021.

[58] O coeficiente de Gini é uma medida de desigualdade que varia entre 0 e 1, em que o valor nulo indica igualdade total e o valor unitário indica desigualdade total.

[59] Em caso de uma distribuição perfeitamente igualitária, a "curva" de Lorenz seria coincidente com a linha de 45°. Assim, quanto maior a convexidade da curva, maior a desigualdade.

[60] A renda domiciliar foi calculada da seguinte maneira: caso algum membro do domicílio se recusasse a informar o valor de algum rendimento questionado (trabalho, aposentadoria, pensões, benefícios sociais ou outros rendimentos), todo o domicílio foi desconsiderado para o cálculo da renda domiciliar. Isso foi feito pois, havendo a recusa da informação por parte de um morador, sabe-se que existe um rendimento no domicílio mas sem ser possível determinar o seu valor, o que afetaria o cômputo do rendimento domiciliar total. Adicionalmente, caso o entrevistado não soubesse informar o rendimento do trabalho, o domicílio também foi excluído do cálculo. Como a renda do trabalho é a fonte de rendimento mais comum dos domicílios, a falta desta informação poderia subestimar muito os valores médios estimados. Adicionalmente, foram desconsiderados os rendimentos iguais a zero.

Figura 3.7.1: Distribuição do rendimento bruto do trabalho principal por faixas de salário mínimo, Asa Norte, 2021

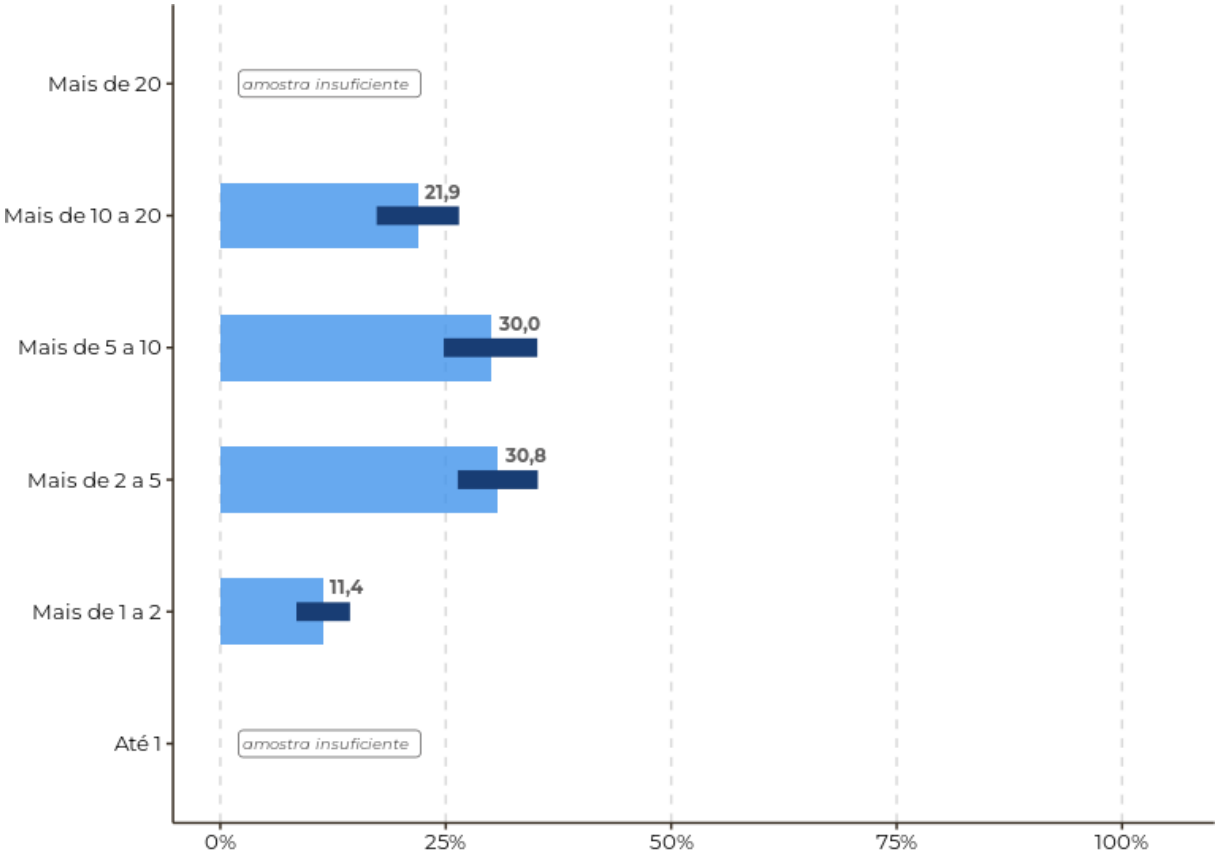

Fonte: CODEPLAN/DIEPS/GEREPS/PDAD 2021
Obs.: Valor do salário mínimo em 2021 era R$ 1.100,00. Valores atualizados pelo IPCA/Brasília.

Figura 3.7.2: Curva de Lorenz do rendimento bruto do trabalho principal, Asa Norte, 2021

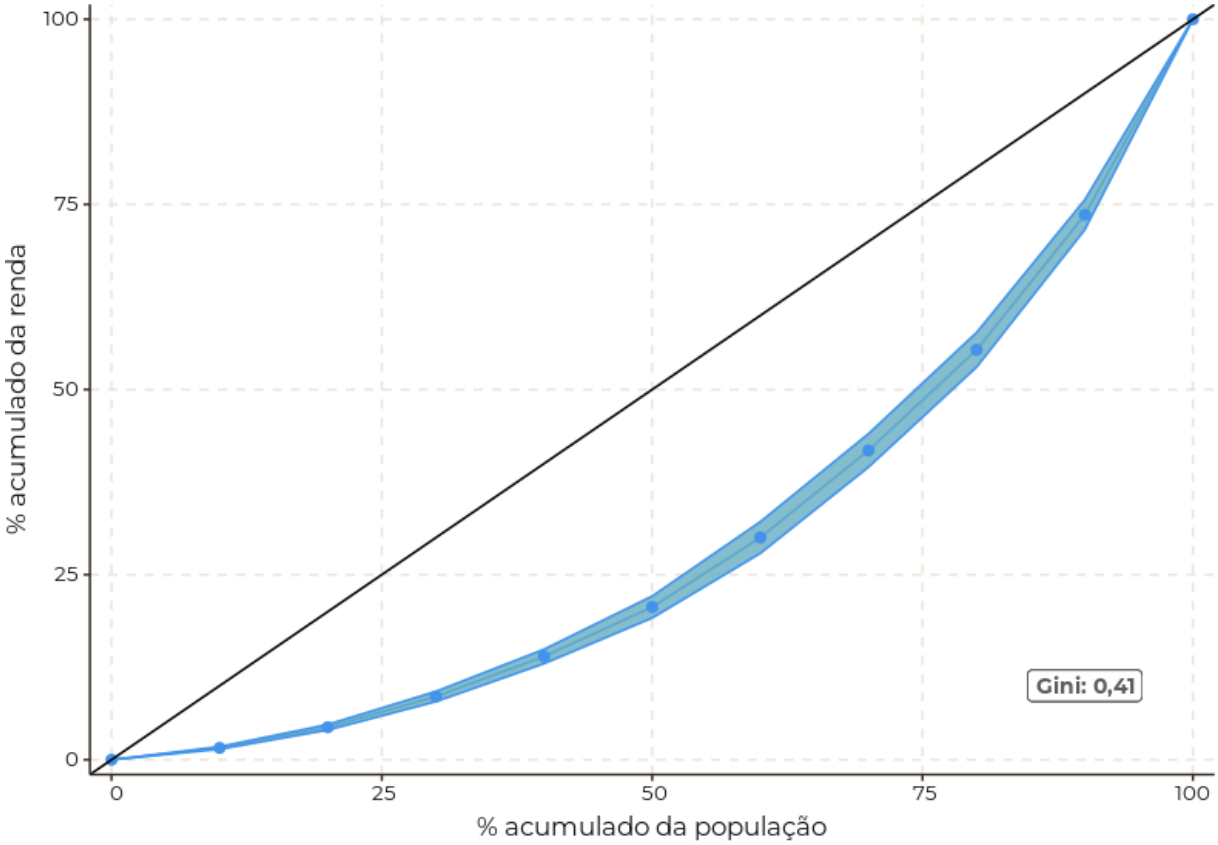

Fonte: CODEPLAN/DIEPS/GEREPS/PDAD 2021
Obs.1: Valores atualizados pelo IPCA/Brasília, R$ de julho de 2021.
Obs.2: Intervalo de confiança na área sombreada.

Figura 3.7.3: Distribuição do rendimento domiciliar por faixas de salário mínimo, Asa Norte, 2021

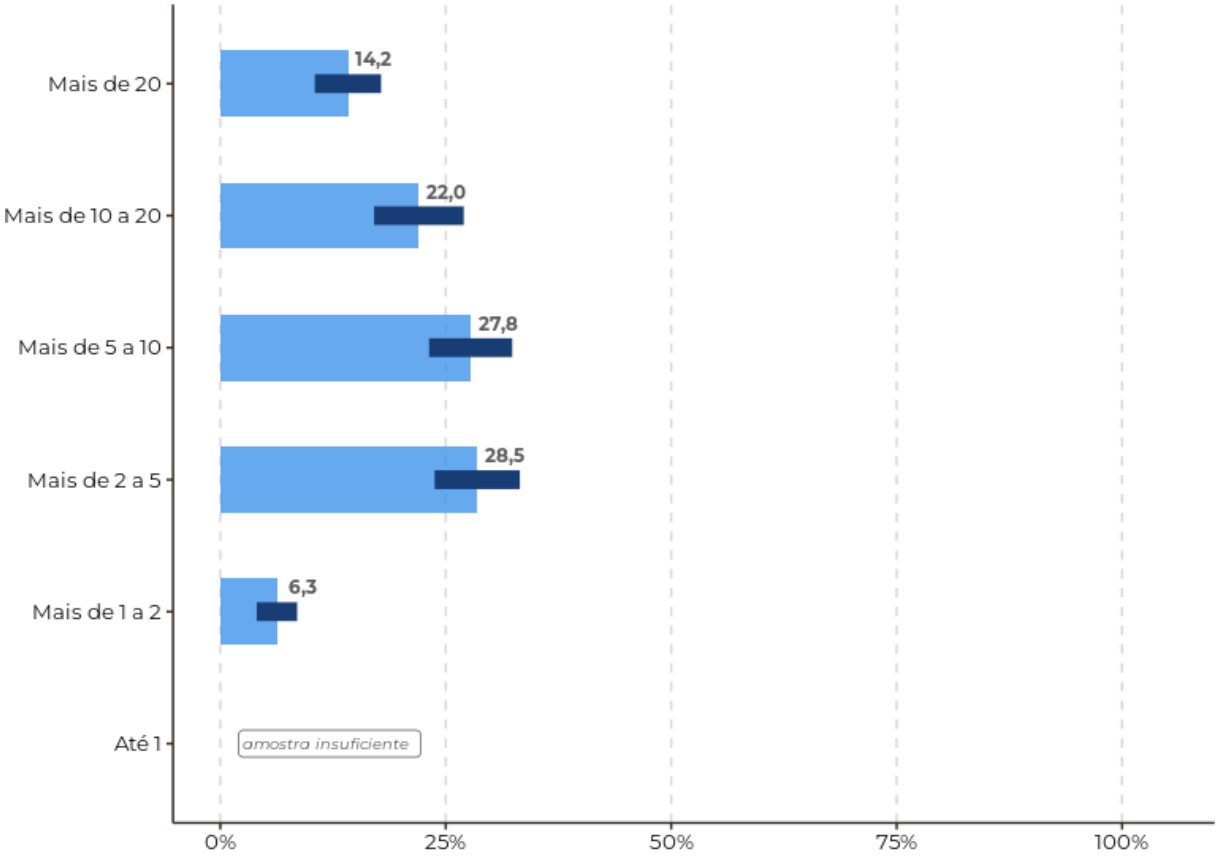

Fonte: CODEPLAN/DIEPS/GEREPS/PDAD 2021
Obs.: Valor do salário mínimo em 2021 era R$ 1.100,00. Valores atualizados pelo IPCA/Brasília.

Figura 3.7.4: Curva de Lorenz do rendimento domiciliar, Asa Norte, 2021

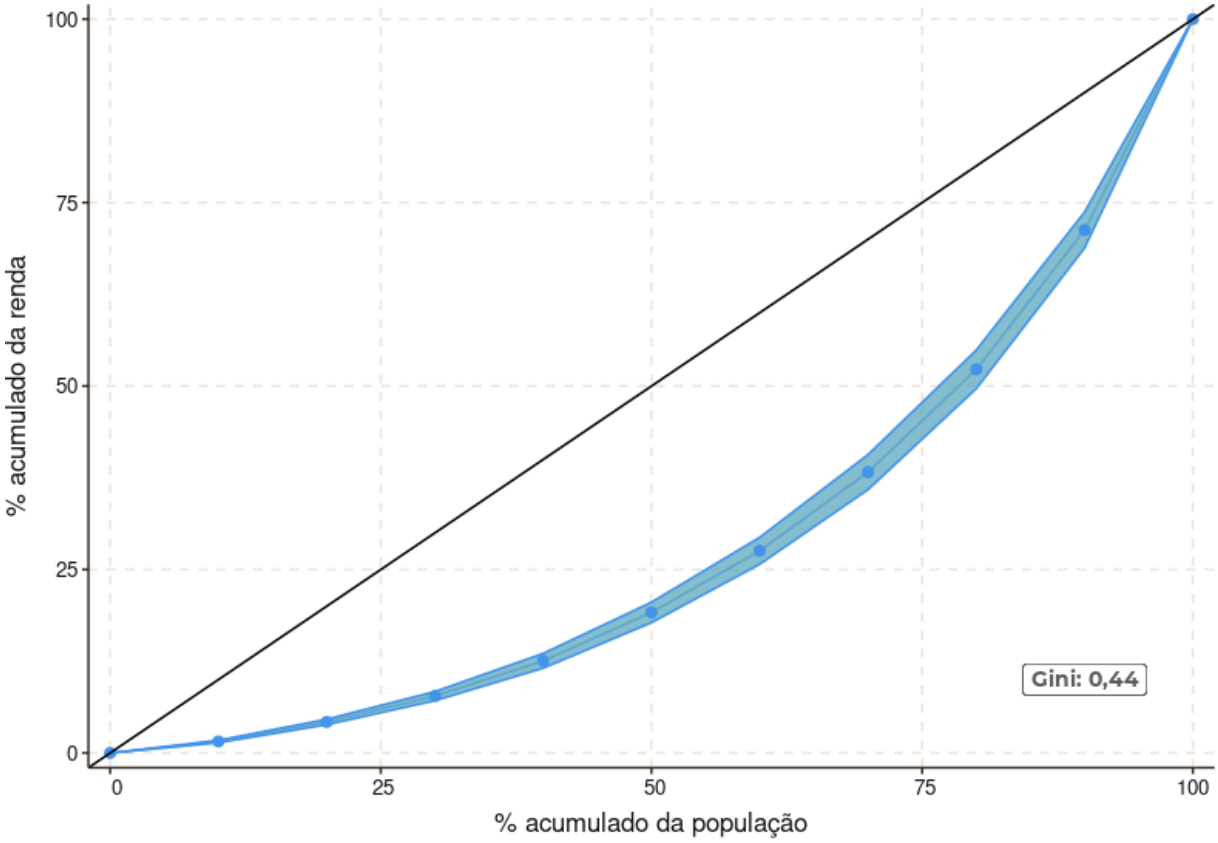

Fonte: CODEPLAN/DIEPS/GEREPS/PDAD 2021
Obs.1: Valores atualizados pelo IPCA/Brasília, R$ de julho de 2021.
Obs.2: Intervalo de confiança na área sombreada.

4 RESULTADOS – DOMICÍLIOS

4.1 Características dos domicílios

A unidade de observação utilizada nesta pesquisa foi o domicílio particular, tendo-se um número estimado de **48.413** unidades ocupadas, com uma média de 2,45 moradores por domicílio. A condição permanente foi observada em 90,2% dos domicílios (Figura 4.1.1 e Tabela A.68).

Figura 4.1.1: Distribuição dos domicílios ocupados segundo a espécie, Asa Norte, 2021

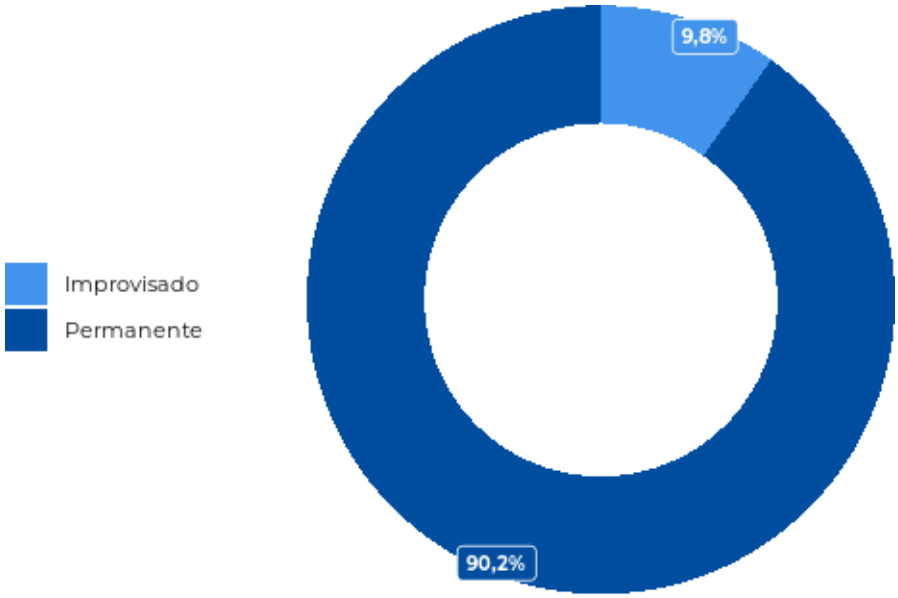

Fonte: CODEPLAN/DIEPS/GEREPS/PDAD 2021

No que diz respeito ao tipo, 93,8% dos domicílios eram apartamentos (Figura 4.1.2 e Tabela A.69), enquanto a condição de ocupação mais comum era próprio, já pago, para 51,1% (Figura 4.1.3 e Tabela A.70). Por fim, 98,1% dos domicílios próprios possuíam escritura definitiva registrada em cartório, segundo informação dos moradores (Figura 4.1.4 e Tabela A.71).

Figura 4.1.2: Distribuição dos domicílios ocupados segundo o tipo, Asa Norte, 2021

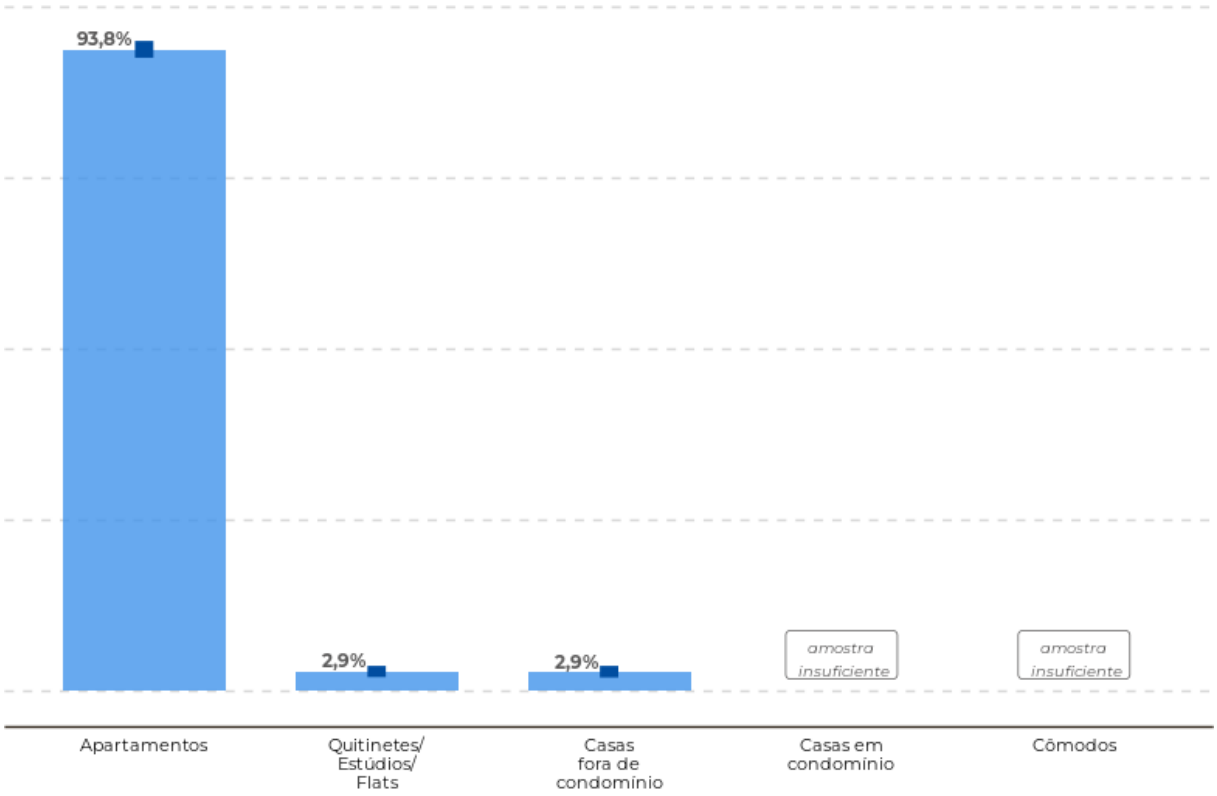

Fonte: CODEPLAN/DIEPS/GEREPS/PDAD 2021

Figura 4.1.3: Distribuição dos domicílios ocupados e próprios segundo a condição de ocupação, Asa Norte, 2021

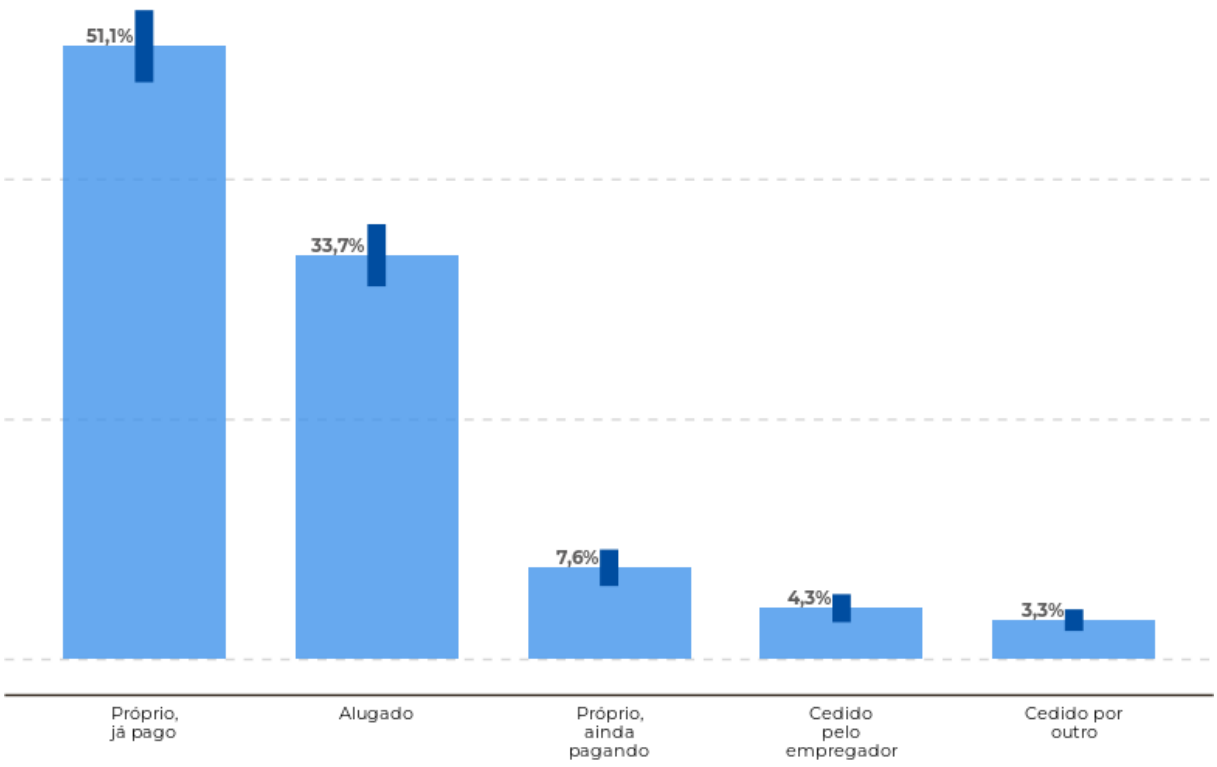

Fonte: CODEPLAN/DIEPS/GEREPS/PDAD 2021

Figura 4.1.4: Distribuição dos domicílios ocupados segundo a regularização do lote, Asa Norte, 2021

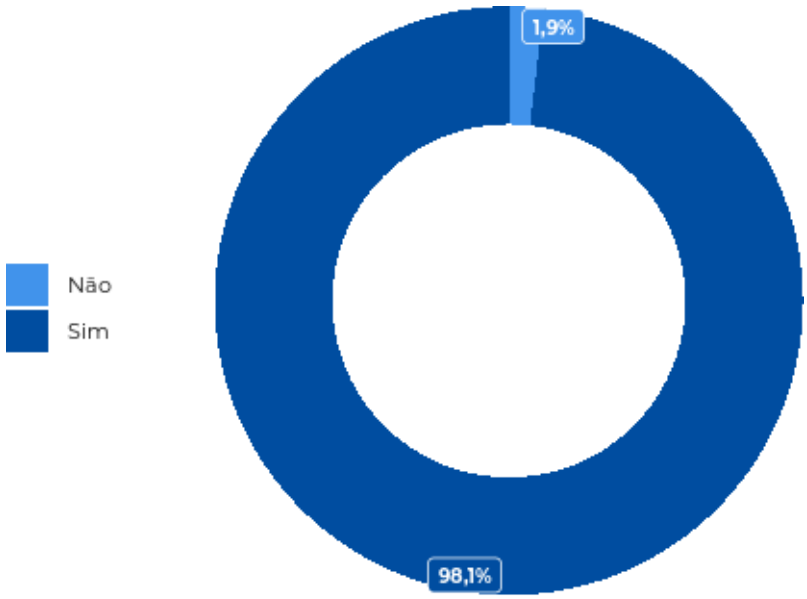

Fonte: CODEPLAN/DIEPS/GEREPS/PDAD 2021

4.2 Infraestrutura domiciliar

Passando para a infraestrutura domiciliar, verificou-se que 96,5% das residências apresentavam parede externa de alvenaria com revestimento (Figura 4.2.1 e Tabela A.72), 95,3% tinham o material do piso de "cerâmica / procelanato / madeira" (Figura 4.2.2 e Tabela A.73), enquanto o telhado era de só laje em 94,2% dos domicílios (Figura 4.2.3 e Tabela A.74).

Figura 4.2.1: Distribuição dos domicílios ocupados segundo material predominante nas paredes externas, Asa Norte, 2021

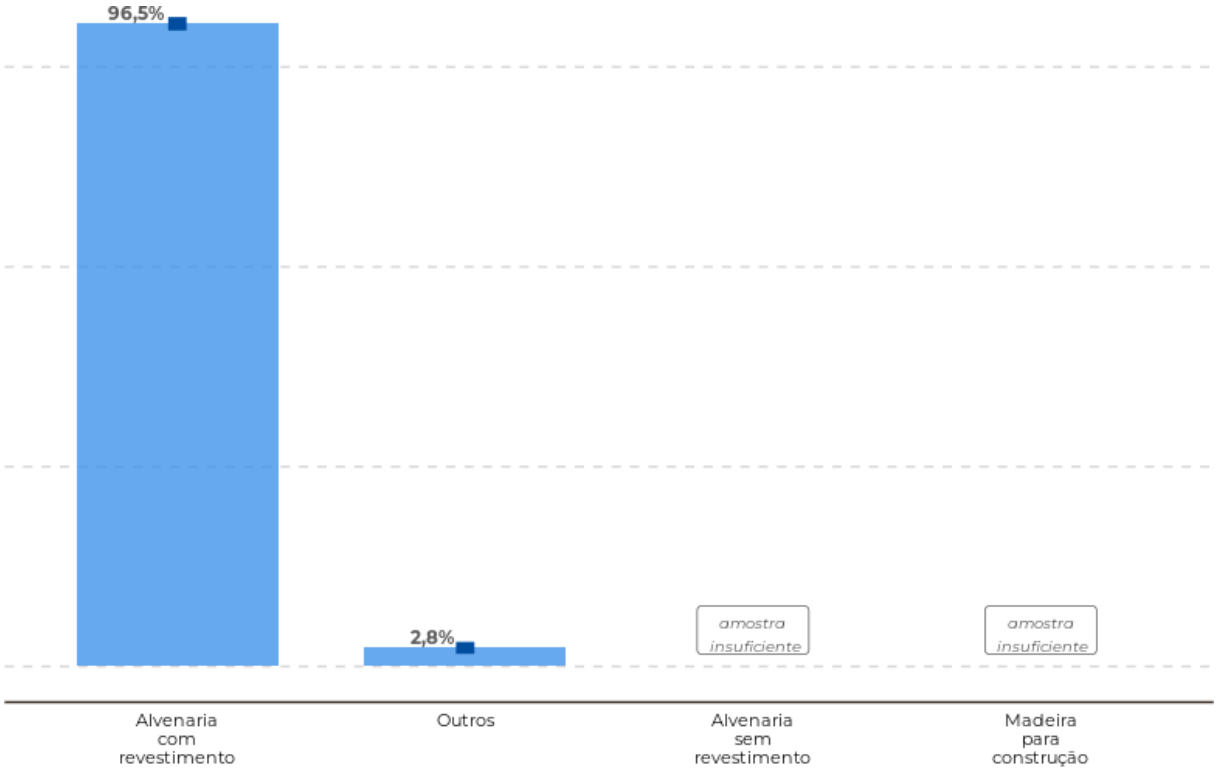

Fonte: CODEPLAN/DIEPS/GEREPS/PDAD 2021

Nos aspectos ligados ao tamanho e à composição dos domicílios, observou-se um número médio de 6,4 cômodos, dos quais 2,1 estavam servindo como dormitório e 1,7 eram banheiros.

Quanto ao abastecimento de água, 99,9% dos domicílios tinham acesso à rede geral da Companhia de Saneamento Ambiental do Distrito Federal (CAESB) (Figura 4.2.4 e Tabela A.75). Sobre a posse de caixa d'água, 97,8% afirmaram ter este item.

No que diz respeito ao esgotamento sanitário, verificou-se que 99,9% dos domicílios com ligação à rede geral da CAESB (Figura 4.2.5 e Tabela A.76).

Figura 4.2.2: Distribuição dos domicílios ocupados segundo material predominante no piso, Asa Norte, 2021

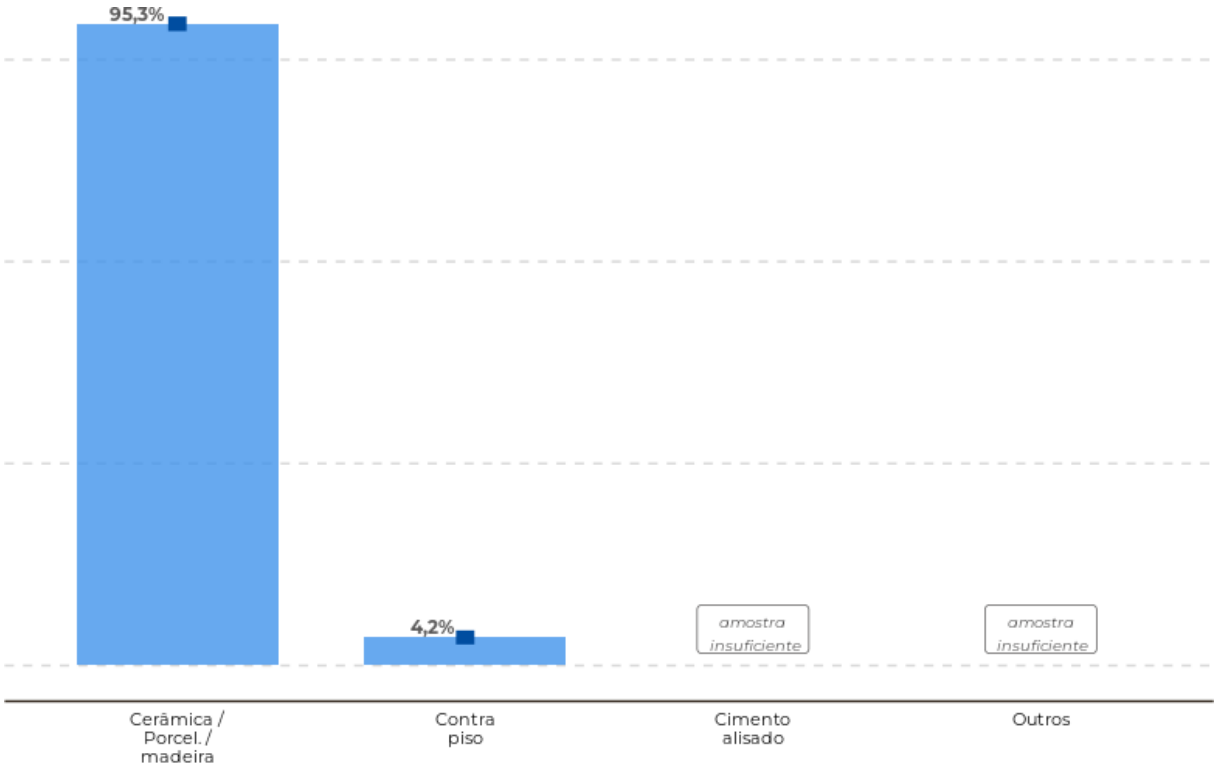

Fonte: CODEPLAN/DIEPS/GEREPS/PDAD 2021

Figura 4.2.3: Distribuição dos domicílios ocupados segundo material predominante na cobertura (telhado), Asa Norte, 2021

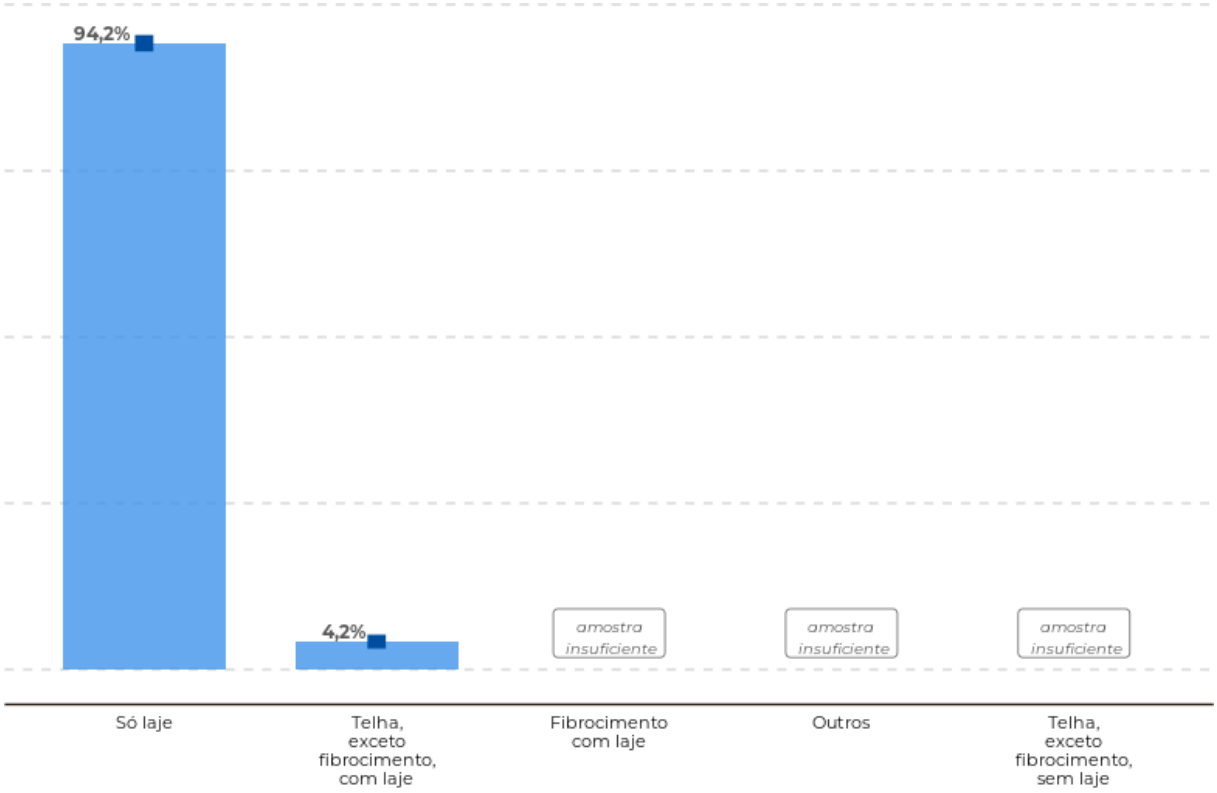

Fonte: CODEPLAN/DIEPS/GEREPS/PDAD 2021

Figura 4.2.4: Abastecimento de água no domicílio, Asa Norte, 2021

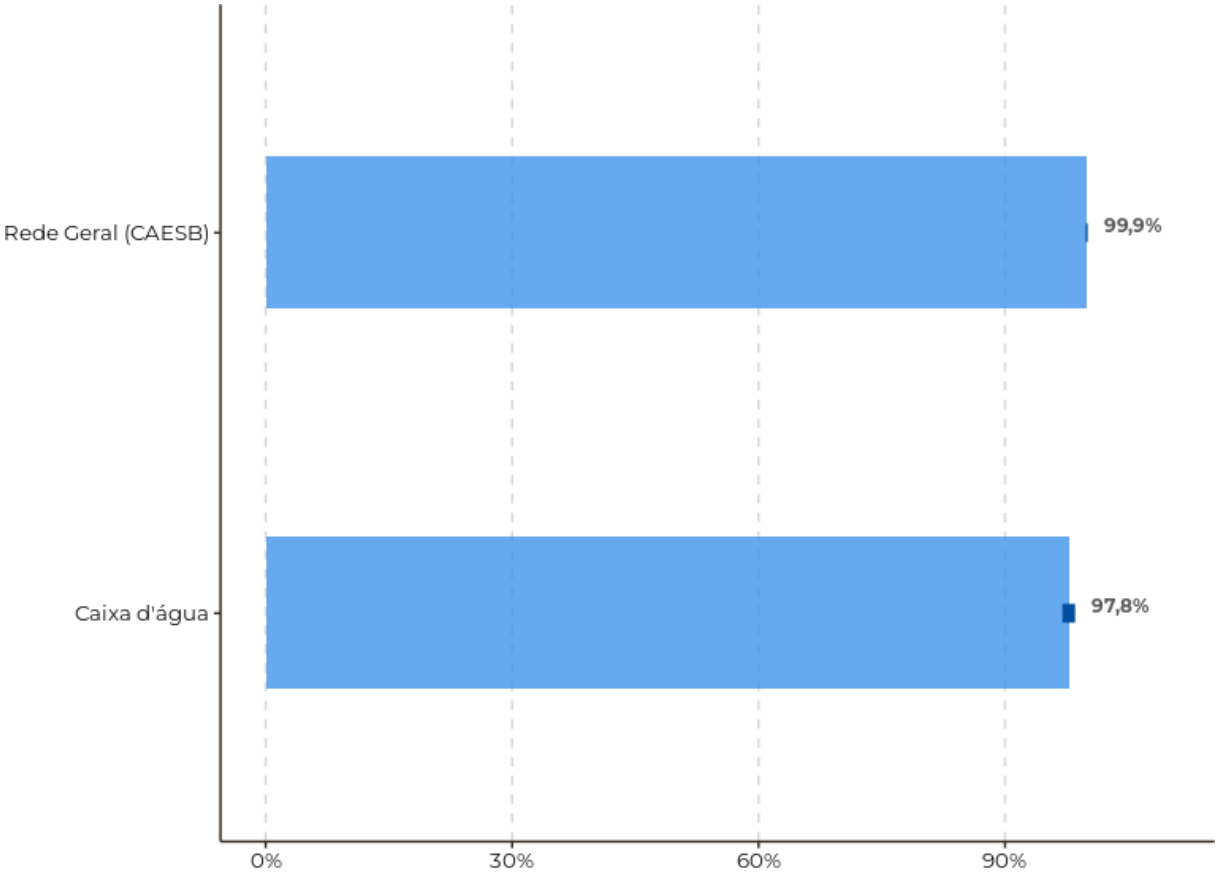

Fonte: CODEPLAN/DIEPS/GEREPS/PDAD 2021

Figura 4.2.5: Esgotamento sanitário do domicílio, Asa Norte, 2021

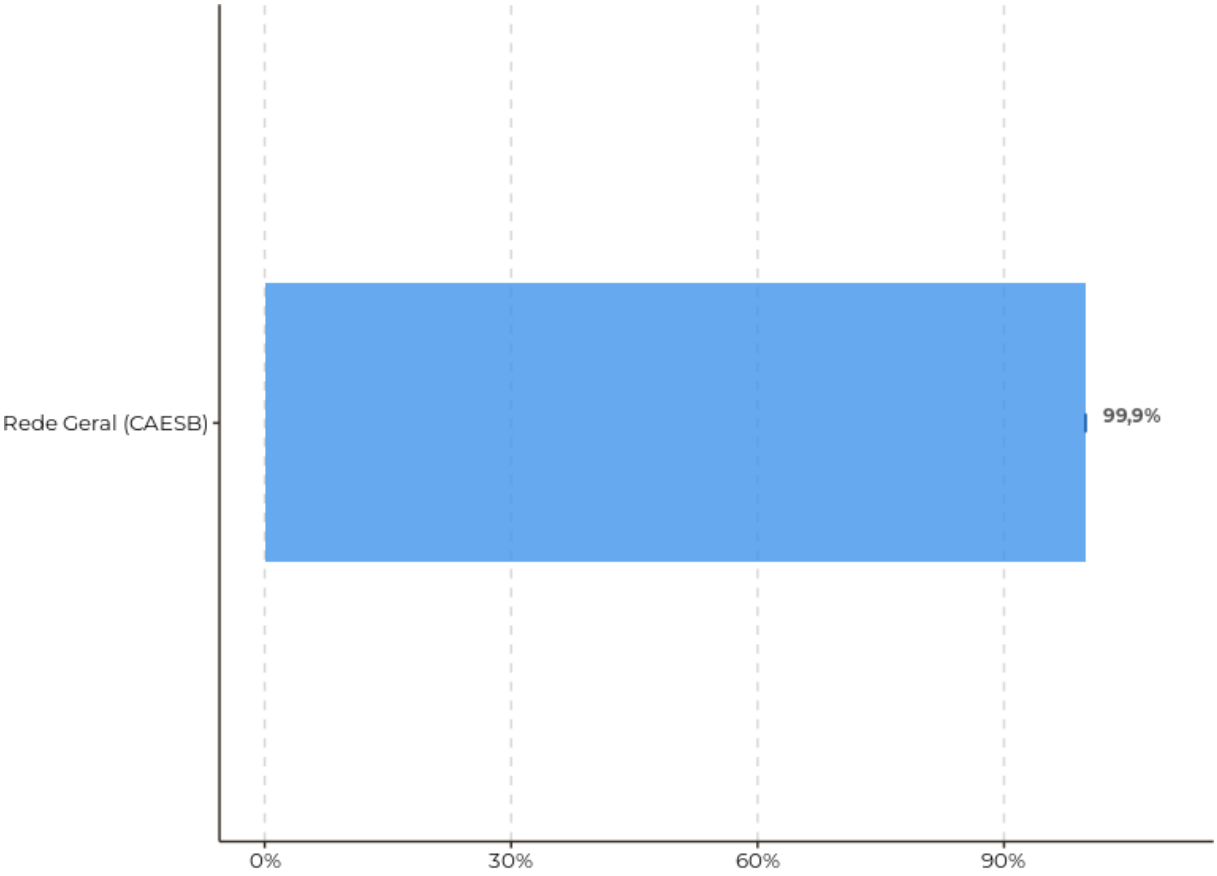

Fonte: CODEPLAN/DIEPS/GEREPS/PDAD 2021

Sobre o abastecimento de energia elétrica, 100% declararam possuir abastecimento da rede geral da Companhia Energética de Brasília (CEB/Neoenergia)[61] (Figura 4.2.6 e Tabela A.77).

Figura 4.2.6: Abastecimento de energia elétrica no domicílio, Asa Norte, 2021

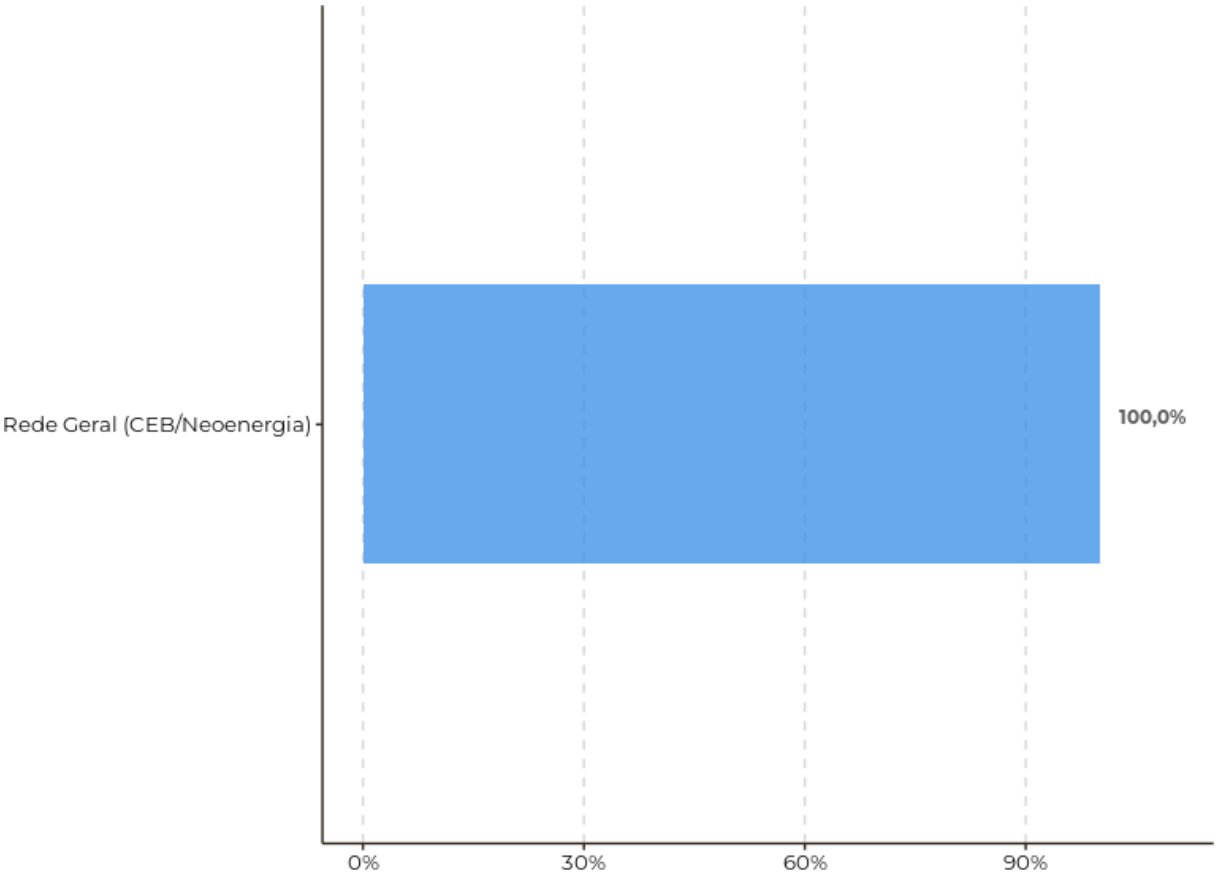

Fonte: CODEPLAN/DIEPS/GEREPS/PDAD 2021

No que diz respeito ao recolhimento de lixo, 96,4% afirmaram ter coleta direta[62], sendo 85,7% seletiva e 96,2% não seletiva, 92,1% tinham coleta indireta. Além disso, 80% faziam a separação do lixo no domicílio, entre orgânico e reciclável (Figura 4.2.7 e Tabela A.78).

[61] Em março de 2021 o grupo Neoenergia assumiu as operações da CEB, mudando o seu nome para Neoenergia Distribuição Brasília em 21 de abril do mesmo ano.
[62] Um domicílio pode ter tanto coleta direta seletiva quanto coleta direta não-seletiva.

Figura 4.2.7: Recolhimento do lixo no domicílio, Asa Norte, 2021

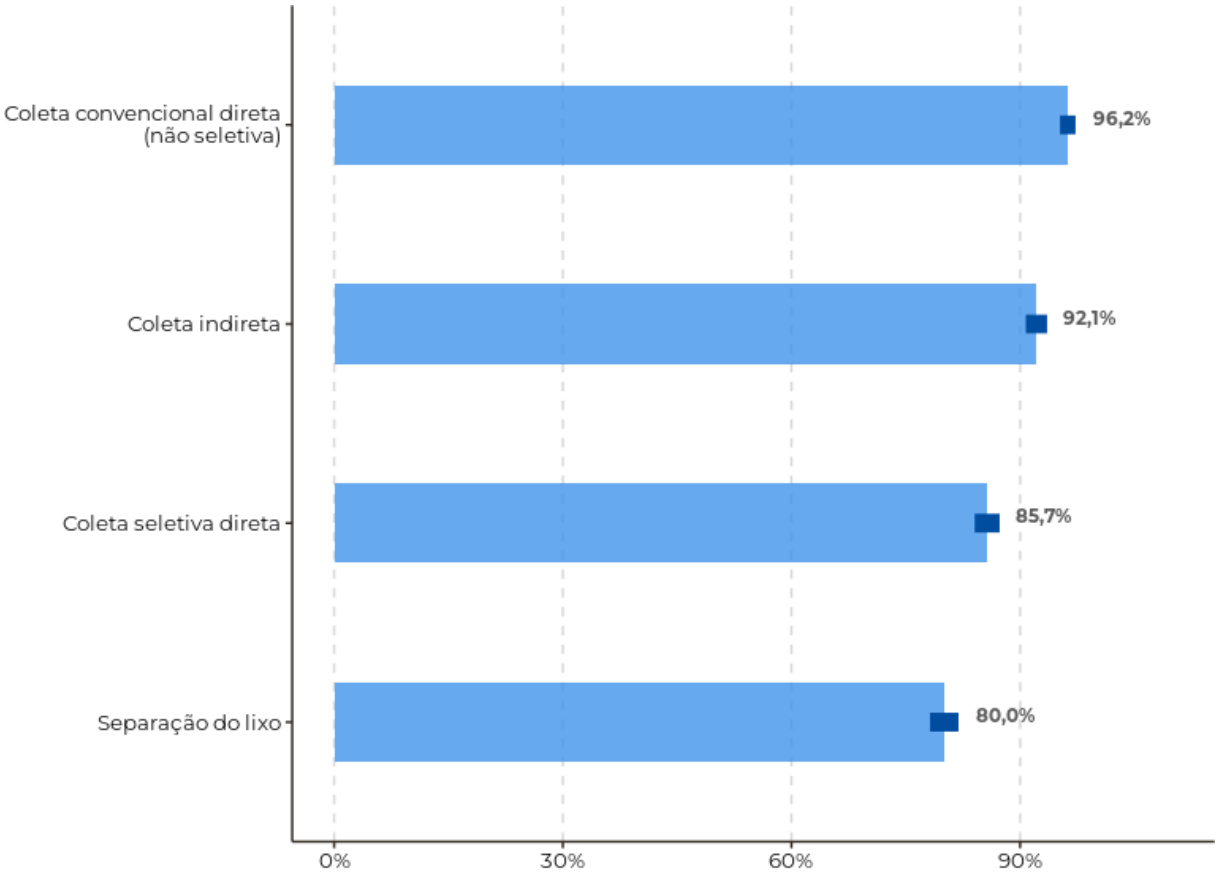

Fonte: CODEPLAN/DIEPS/GEREPS/PDAD 2021

4.3 Infraestrutura urbana nas proximidades dos domicílios

Passando para as questões referentes à infraestrutura urbana existente nas proximidades dos domicílios, verificou-se que a rua de acesso principal ao domicílio era asfaltada em 99,7% das unidades, 99,3% afirmaram ter calçada, das quais 86,9% tinham meio fio, sendo avaliadas como "boa", segundo 63,7% dos respondentes. Para 98,8% dos entrevistados havia iluminação na rua principal de acesso ao domicílio, enquanto 98,6% responderam que havia drenagem da água da chuva (boca de lobo) (Figura 4.3.1 e Tabela A.79).

Figura 4.3.1: Infraestrutura urbana na rua de acesso dos domicílios, Asa Norte, 2021

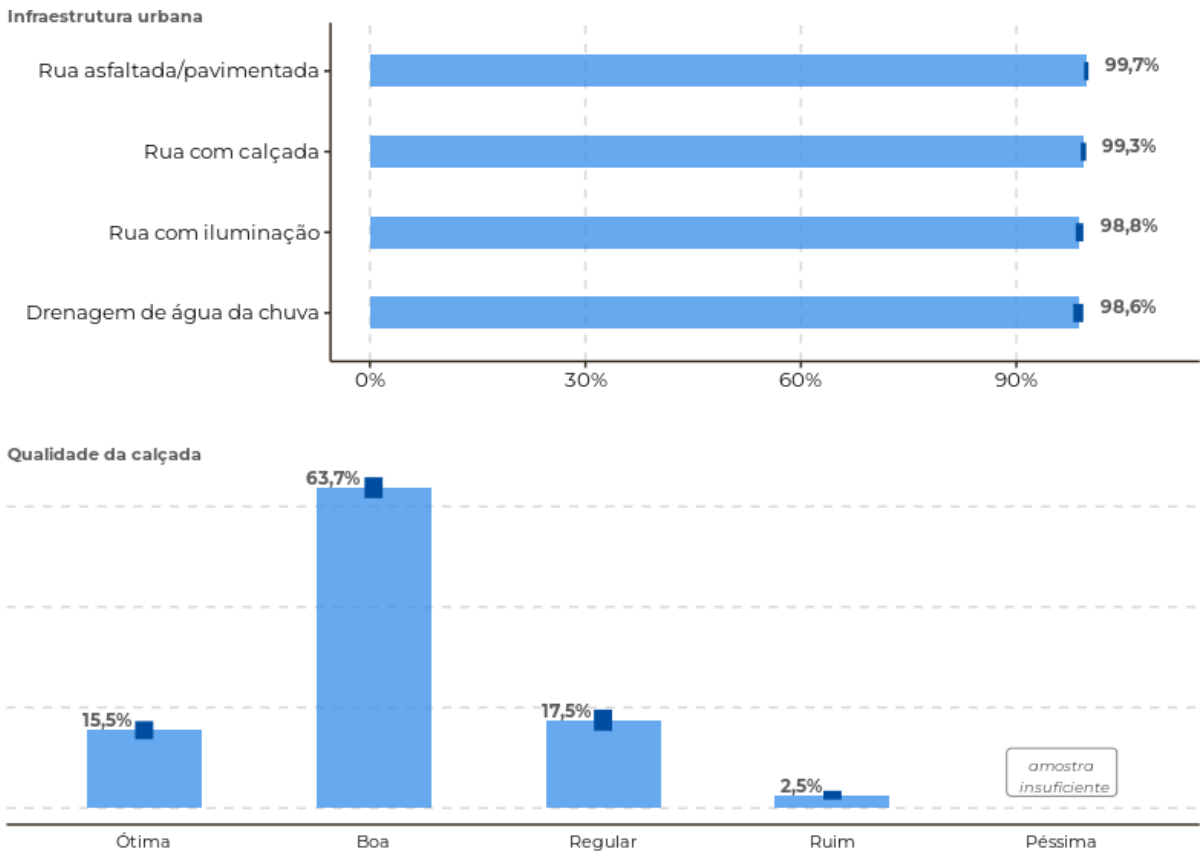

Fonte: CODEPLAN/DIEPS/GEREPS/PDAD 2021

Sobre problemas nas proximidades dos domicílios, 5,6% responderam que havia áreas com erosão, 1,5% responderam que havia áreas com inclinação acentuada (como morros) que poderiam apresentar riscos aos moradores, 3,6% responderam que havia entulho, 10,6% informaram que as ruas ficavam alagadas em ocasiões de chuva e 15,5% disseram que ruas próximas eram esburacadas (Figura 4.3.2 e Tabela A.81).

Figura 4.3.2: Problemas nas cercanias do domicílio, Asa Norte, 2021

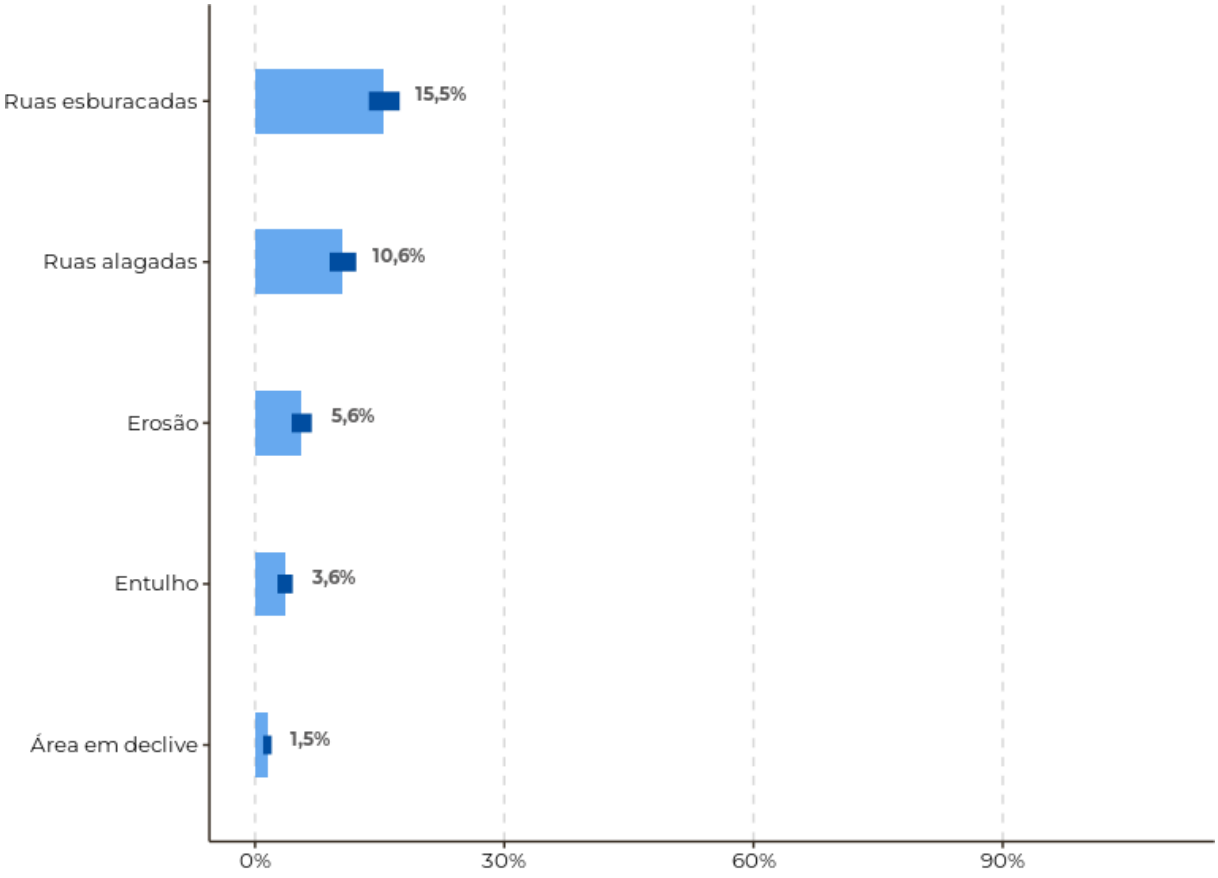

Fonte: CODEPLAN/DIEPS/GEREPS/PDAD 2021

Sobre infraestrutura pública nas proximidades dos domicílios, 99,4% responderam que havia ruas arborizadas, 93,3% responderam que havia jardins e parques, 97% responderam que existia praça, 81,8% informaram a existência de espaços culturais públicos, 93,7% informaram existiam academias comunitárias (também conhecidos como PEC – Ponto de Encontro Comunitário), 94,5% relataram a existência de quadras esportivas, 96,2% afirmaram haver ciclovia/ciclofaixa, 98,7% relataram existir travessia sinalizada para pedestres (como faixas de pedestre, passarela, passagem subterrânea ou semáforo) e 98,6% disseram existir ponto de ônibus (Figura 4.3.3 e Tabela A.82).

Figura 4.3.3: Infraestrutura urbana nas cercanias do domicílio, Asa Norte, 2021

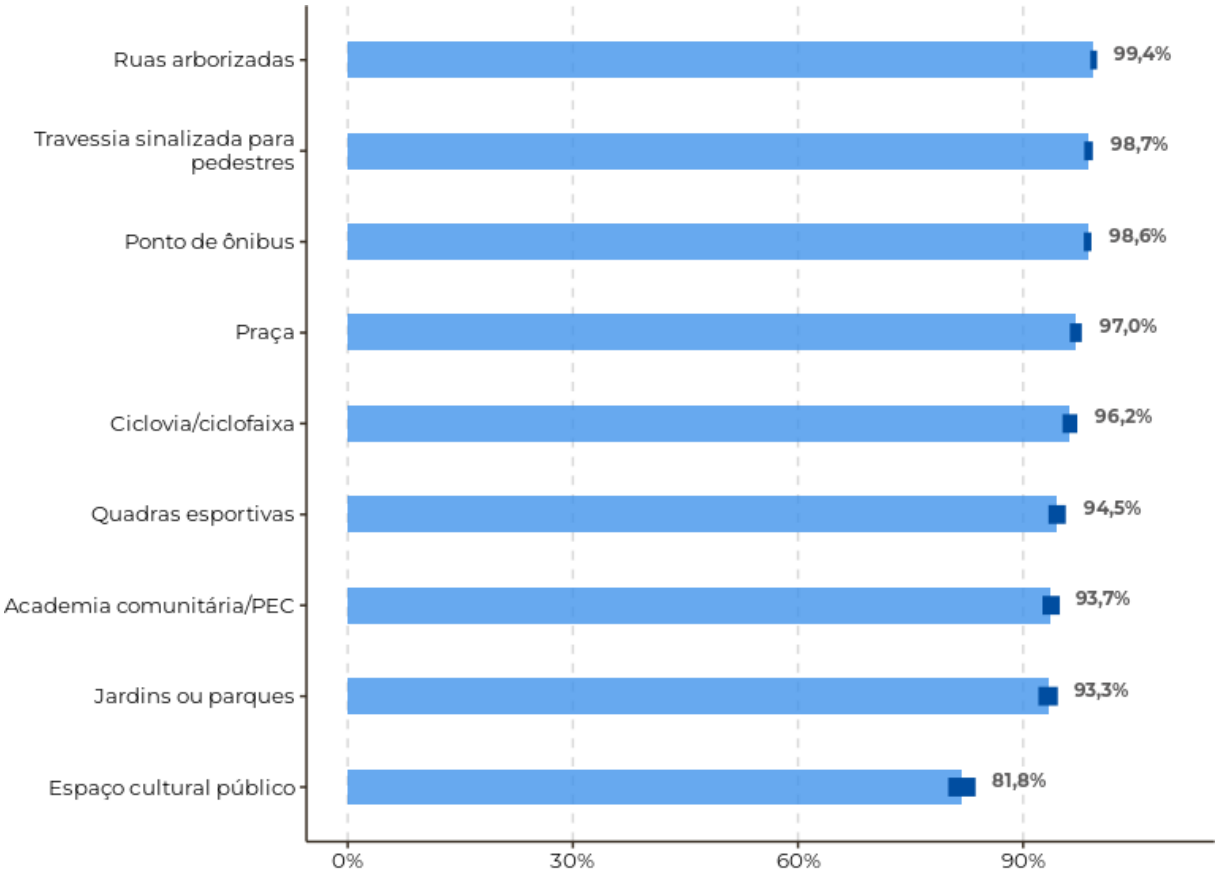

Fonte: CODEPLAN/DIEPS/GEREPS/PDAD 2021

No que tange às questões de segurança, 93,3% afirmaram haver policiamento militar regular, em 33,2% dos domicílios havia equipamento ou dispositivo de segurança particular e em 55,9% havia tais serviços compartilhados com mais domicílios (como portarias, sistemas de segurança de condomínio, servidos de ronda etc.) (Figura 4.3.4 e Tabela A.83).

Figura 4.3.4: Segurança nas proximidades do domicílio, Asa Norte, 2021

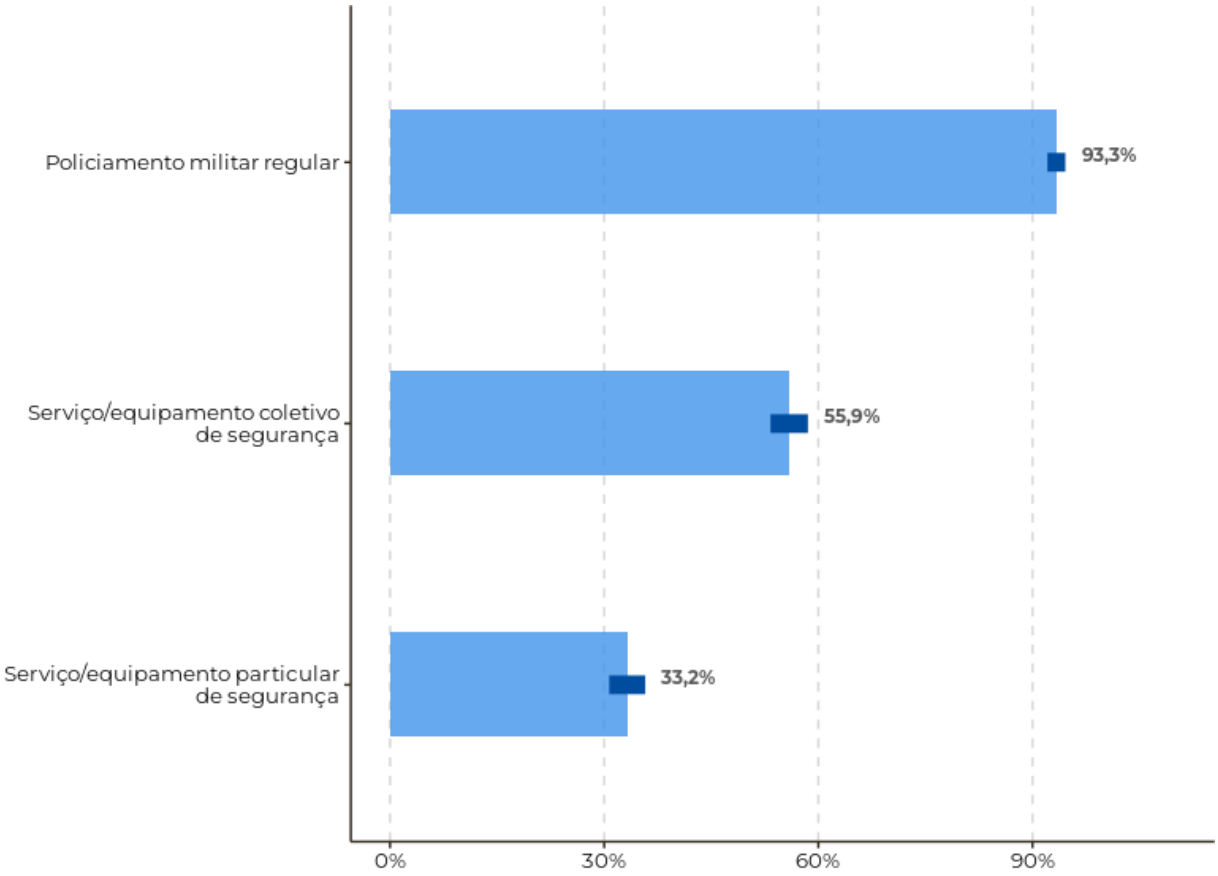

Fonte: CODEPLAN/DIEPS/GEREPS/PDAD 2021

4.4 Serviços domiciliares e inventário de bens duráveis

Uma importante característica que permite avaliar a capacidade de consumo das unidades domiciliares é a contratação de serviços domiciliares e a posse de bens duráveis. Assim sendo, este bloco é dedicado a investigar essas questões. Em 89% havia assinatura serviços on-line, como filmes, músicas, notícias, cursos, esportes etc., enquanto em 64,6% dos domicílios havia serviço de TV por assinatura, e 12,3% assinavam revistas ou jornais impressos (Figura 4.4.1 e Tabela A.84).

Figura 4.4.1: Contratação de serviços pelos domicílios, Asa Norte, 2021

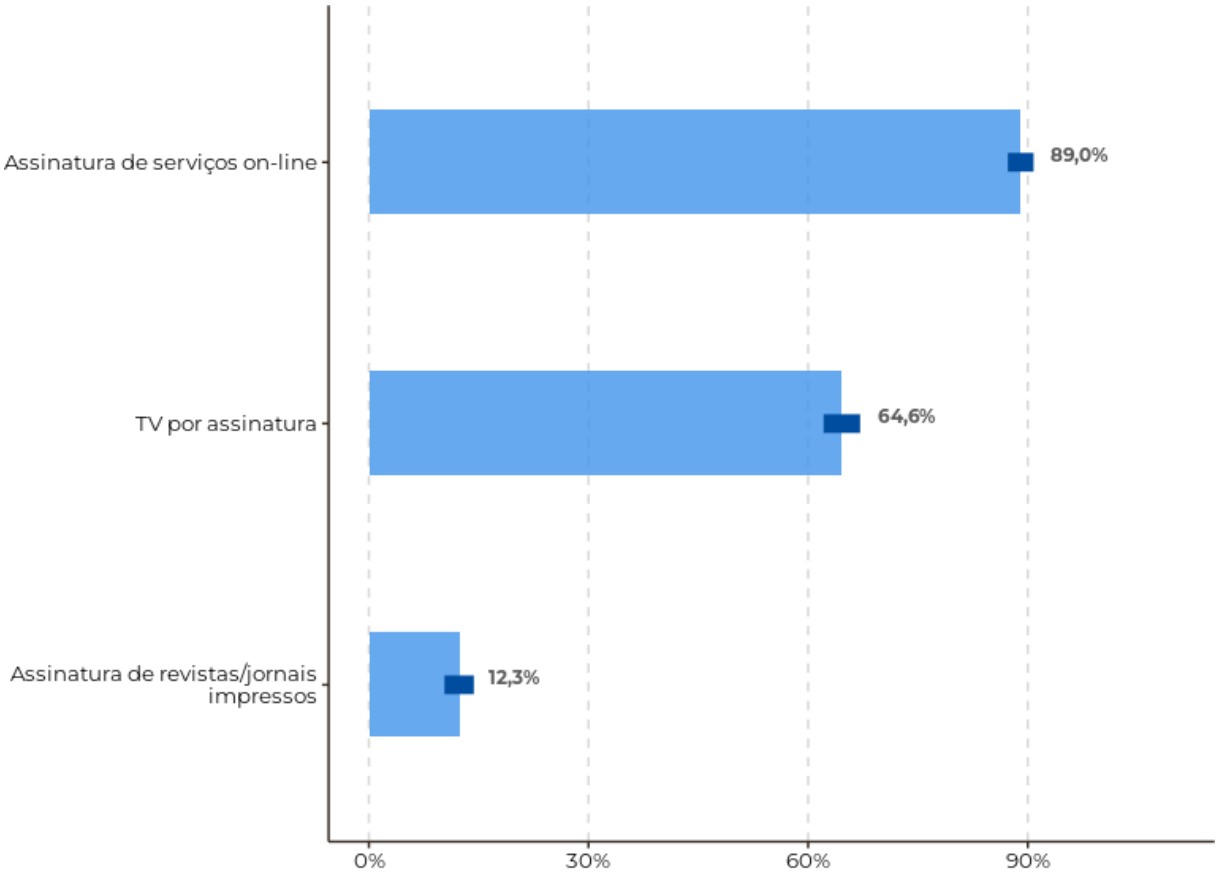

Fonte: CODEPLAN/DIEPS/GEREPS/PDAD 2021

Sobre internet, 99,9% possuíam acesso[63], sendo que 97,4% do acesso era realizado por meio próprio (Figura 4.4.2 e Tabela A.85).

No que diz respeito à posse de veículos, 85,3% dos entrevistados declararam possuir automóvel, 9,1% informaram ter motocicleta e 28,8% disseram possuir bicicleta (Figura 4.4.3 e Tabela A.87).

[63] Pelo menos um morador do domicílio tinha acesso à internet, seja esta fixa ou móvel.

Figura 4.4.2: Modalidades de acesso à internet no domicílio, Asa Norte, 2021

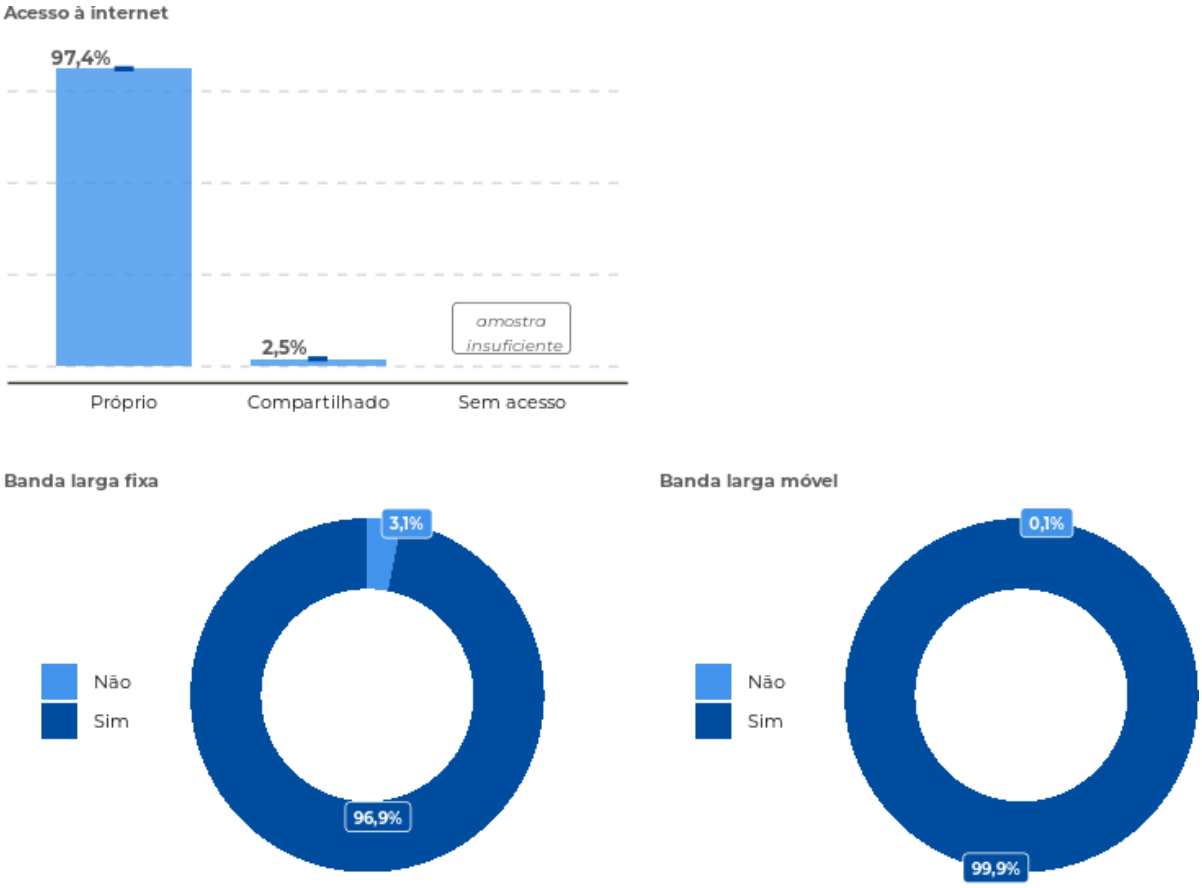

Fonte: CODEPLAN/DIEPS/GEREPS/PDAD 2021

Figura 4.4.3: Posse de veículos no domicílio, Asa Norte, 2021

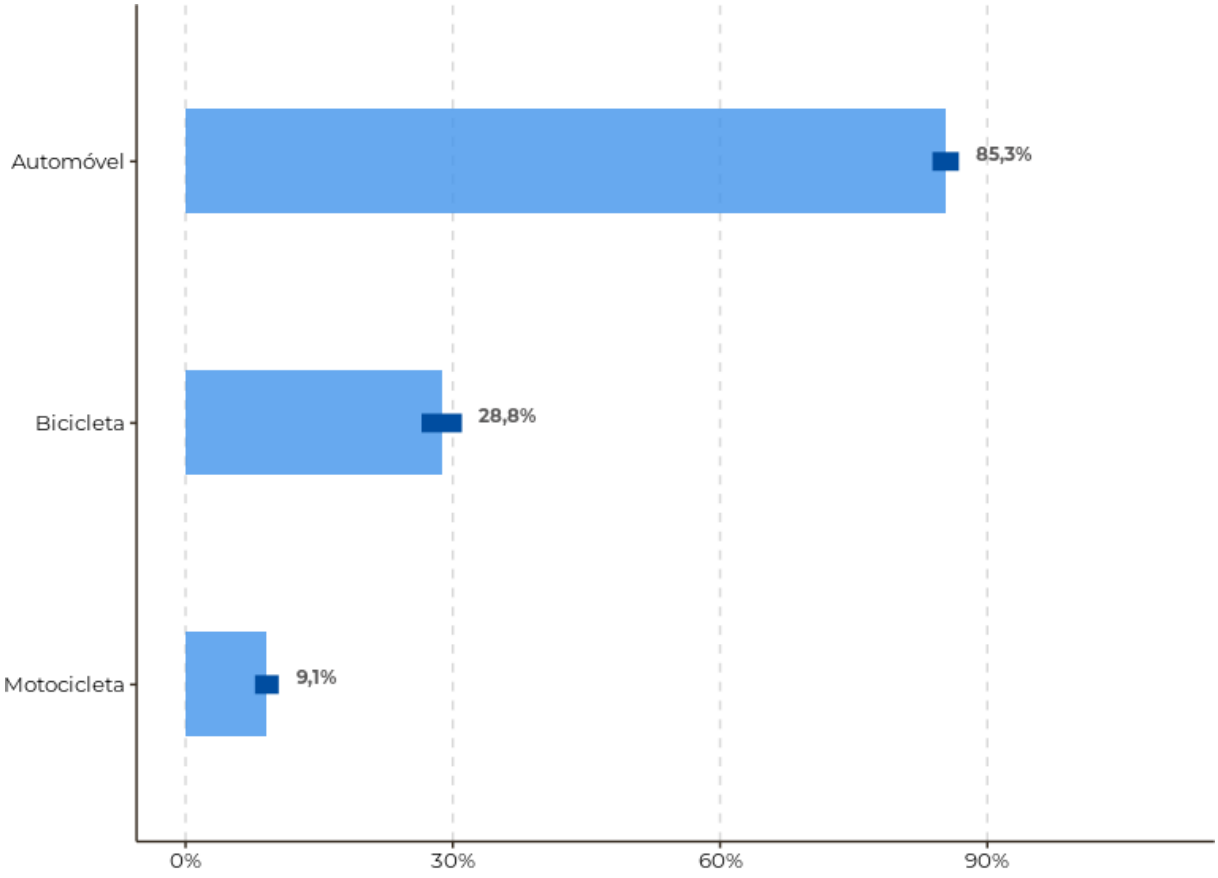

Fonte: CODEPLAN/DIEPS/GEREPS/PDAD 2021

Sobre a posse de eletrodomésticos, observou-se que 99,7% dos domicílios tinham pelo menos um fogão, 92% tinham micro-ondas, 34% tinham geladeira de uma porta, 66,3% tinham geladeira de duas ou mais portas, 17,3% tinham freezer, 66,5% tinham máquina de lavar roupas, 30,7% tinham máquina de lavar e secar roupas, 15,2% tinham secadora de roupa, 12,7% máquina de lavar louça, 2,1% tinham televisores tubo, 98,3% televisores tela fina/plana, 8,6% tinham reprodutores de DVD e/ou Blu-ray, 37,1% tinham microcomputadores de mesa, 82,5% tinham notebook/laptop, 62,3% tinham ar condicionado, 54,4% tinham circuladores de ar e/ou ventiladores e 46,5% tinham telefone fixo (Figura 4.4.4, Figura 4.4.5 e Tabela A.88).

Figura 4.4.4: Inventário de bens duráveis dos domicílios, Asa Norte, 2021

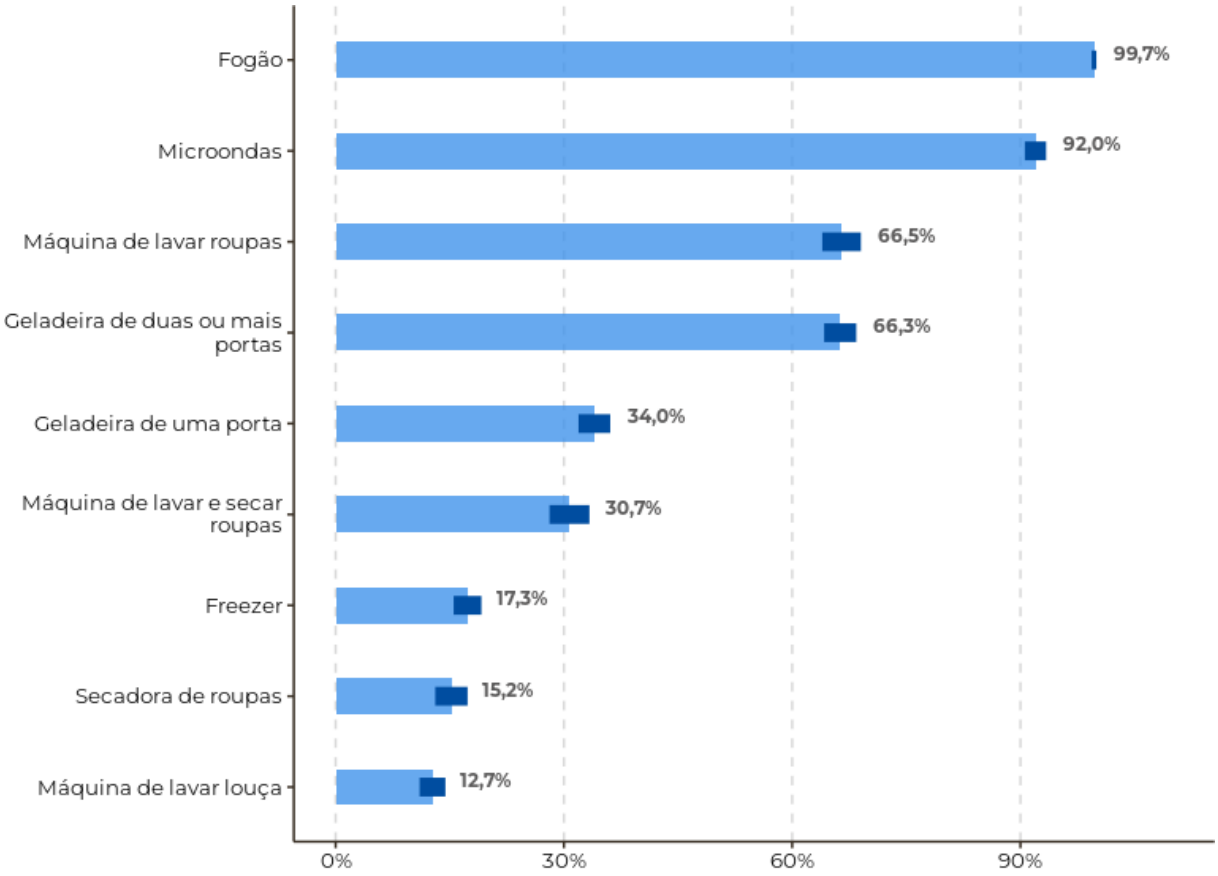

Fonte: CODEPLAN/DIEPS/GEREPS/PDAD 2021

Questionou-se, ainda, a utilização de serviços domésticos. Em 51,7% os respondentes declararam não haver a contratação de empregados domésticos, sejam mensalistas ou diaristas (Figura 4.4.6 e Tabela A.89).

Figura 4.4.5: Inventário de bens duráveis dos domicílios (Continuação), Asa Norte, 2021

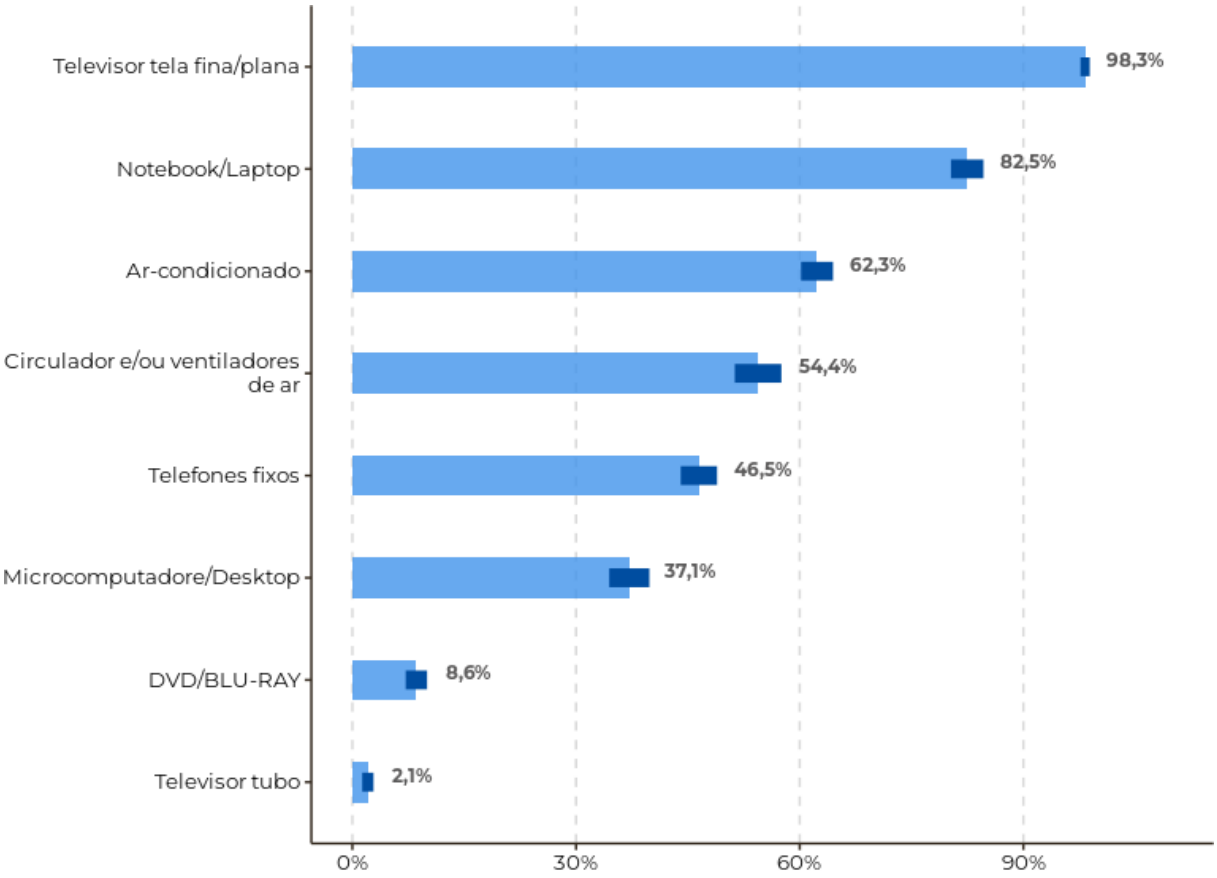

Fonte: CODEPLAN/DIEPS/GEREPS/PDAD 2021

Figura 4.4.6: Utilização de serviços domésticos nos domicílios, Asa Norte, 2021

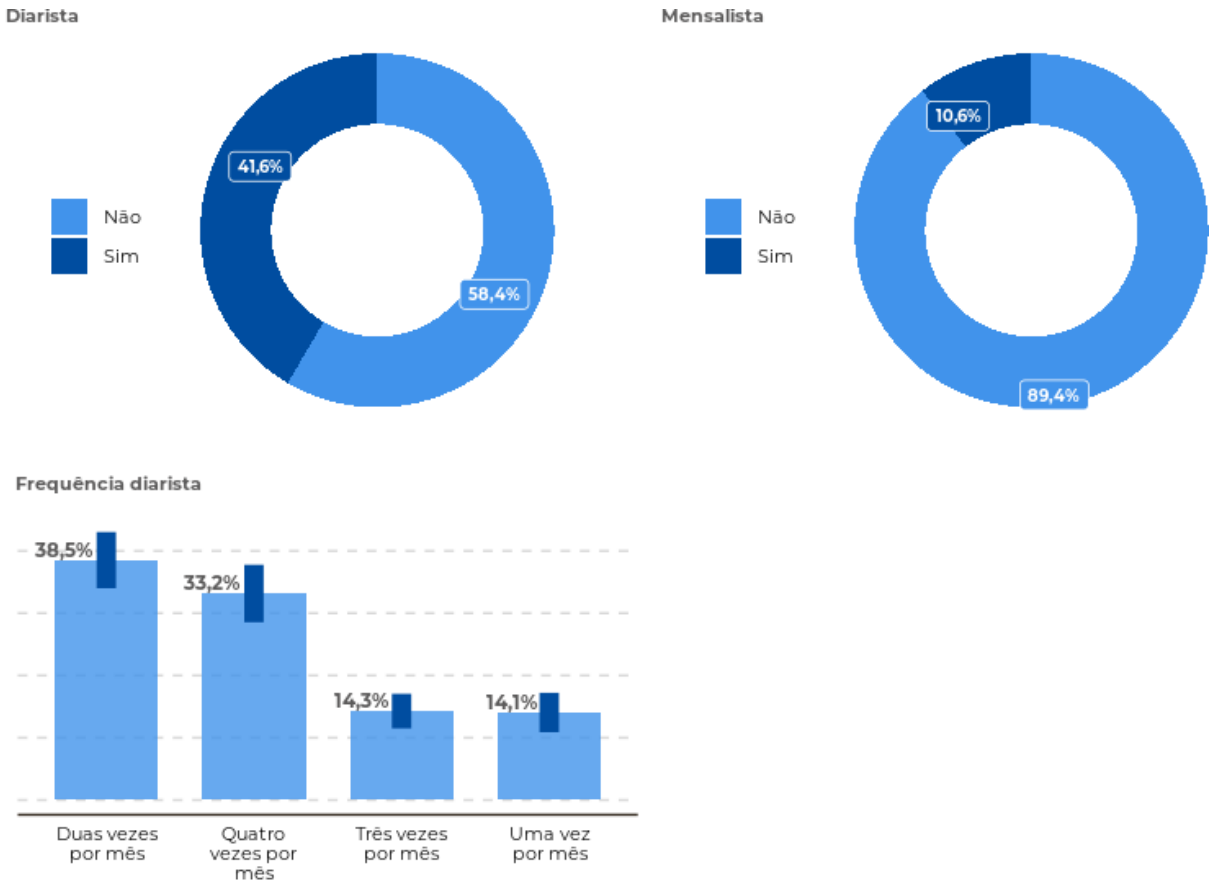

Fonte: CODEPLAN/DIEPS/GEREPS/PDAD 2021

4.5 Localidades predominantes de compras

Nesta edição, a PDAD perguntou quais eram as localidades predominantes de compra de alguns itens de consumo domiciliar[64]. Para alimentação, higiene e limpeza, tendo como referência o último mês a partir da data da entrevista, 98,7% dos respondentes indicaram a RA Plano Piloto como a principal localidade. Agora, sempre considerando como referência os últimos doze meses, o principal local de compra de eletrodomésticos foi Plano Piloto (94,3%), de materiais de construção ou manutenção foi Plano Piloto (98,7%) e de serviços em geral (exceto limpeza doméstica) foi Plano Piloto (99%).

[64] Foram desconsiderados os domicílios que não efetuaram compras dos itens questionados no período de referência.

Figura 4.5.1: Locais predominantes de compra de artigos de alimentação, higiene e limpeza, eletrodomésticos, material de construção/manutenção e serviços em geral, Asa Norte, 2021

Fonte: CODEPLAN/DIEPS/GEREPS/PDAD 2021
Obs.: São reportadas até o limite das dez maiores categorias.

4.6 Animais de estimação

Outra novidade da PDAD 2021 diz respeito à existência de animais de estimação nos domicílios. Segundo os entrevistados, em 26,5% havia pelo menos um animal de estimação; em 8,2% havia gato; em 18,3% havia cachorro; em 1,4% havia peixe; em 1,2% havia algum outro animal (Figura 4.6.1 e Tabela A.95).

Figura 4.6.1: Existência de gatos, cachorros, aves, peixes ou outros animais domésticos no domicílio, Asa Norte, 2021

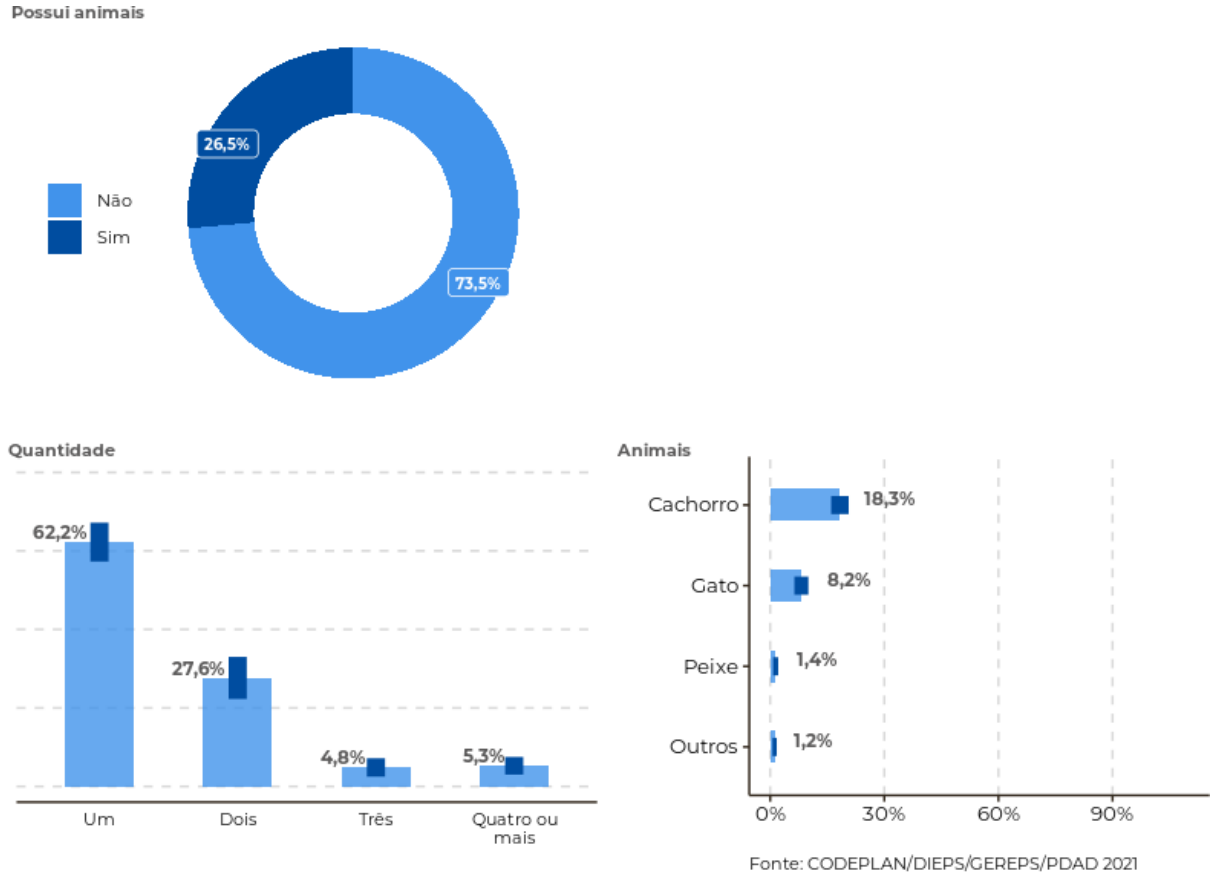

Fonte: CODEPLAN/DIEPS/GEREPS/PDAD 2021

4.7 Segurança alimentar

Para finalizar este capítulo de domicílios, a PDAD 2021 investigou domicílios em situação de insegurança alimentar[65].

A insegurança alimentar foi obtida a partir da aplicação da Escala Brasileira de Insegurança Alimentar (EBIA), uma escala psicométrica que avalia de maneira direta a dimensão de acesso aos alimentos na população, por meio da percepção e experiência com a fome[66]. Trata-se de um indicador originário do indicador Cornell, desenvolvido pela Universidade de Cornell[67].

A EBIA mede diretamente a percepção e vivência de insegurança alimentar e fome no nível domiciliar, captando a dificuldade de acesso familiar aos alimentos e a experiência de vida com a insegurança alimentar e a fome vivenciada nos domicílios[68]. Fornece estimativas da prevalência de insegurança alimentar em diferentes níveis de severidade e sua obtenção está baseada em perguntas sobre comportamentos adotados frente à insuficiência alimentar e a incerteza em relação ao acesso ao alimento.

A insegurança alimentar se divide em três escalas[69]:

- **Insegurança Alimentar leve:** Preocupação ou incerteza quanto acesso aos alimentos no futuro; qualidade inadequada dos alimentos resultante de estratégias que visam não comprometer a quantidade de alimentos;
- **Insegurança Alimentar Moderada:** Redução quantitativa de alimentos entre os adultos e/ou ruptura nos padrões de alimentação resultante da falta de alimentos entre os adultos;

[65] Instituto Brasileiro de Geografia e Estatística (IBGE). Pesquisa Nacional por Amostra de Domicílios – Segurança Alimentar. Rio de Janeiro: IBGE, Diretoria de Pesquisa, Coordenação de Trabalho e Renda; 2006. Disponível em: <http://www.planalto.gov.br/consea/static/documentos/Eventos/IIIConferencia/PNADSegurancaAlimentar2004%20VERS%C3O%20FINAL.pdf>

[66] KEPPLE AW, SEGALL-CORRÊA AM. Conceituando e medindo segurança alimentar e nutricional. Ciência & Saúde Coletiva, 16(1):187-199, 2011.

[67] RADIMER KL, OLSON CM, GREENE JC, CAMPBELL CC, HABICHT J-P. Understanding hunger and developing indicators to assess it in women and children. J Nutr Educ 1992; 24(Suppl.):36-45.

[68] KEPPLE AW, SEGALL-CORRÊA AM. Conceituando e medindo segurança alimentar e nutricional. Ciência & Saúde Coletiva, 16(1):187-199, 2011.

[69] IBGE. Pesquisa de Orçamentos Familiares: 2017-2018. Análise da segurança alimentar no Brasil, 2020

- **Insegurança alimentar grave:** Redução quantitativa de alimentos também entre as crianças, ou seja, ruptura nos padrões de alimentação resultante da falta de alimentos entre todos os moradores, incluindo as crianças. Nessa situação, a fome passa a ser uma experiência vivida no domicílio.

Os resultados apontam que 2,1% estavam nesta situação nos três meses anteriores à data da entrevista, seja esta leve, moderada ou grave (Figura 4.7.1 e Tabela A.96).

Figura 4.7.1: Distribuição dos domicílios por situação de segurança alimentar nos últimos 3 meses, Asa Norte, 2021

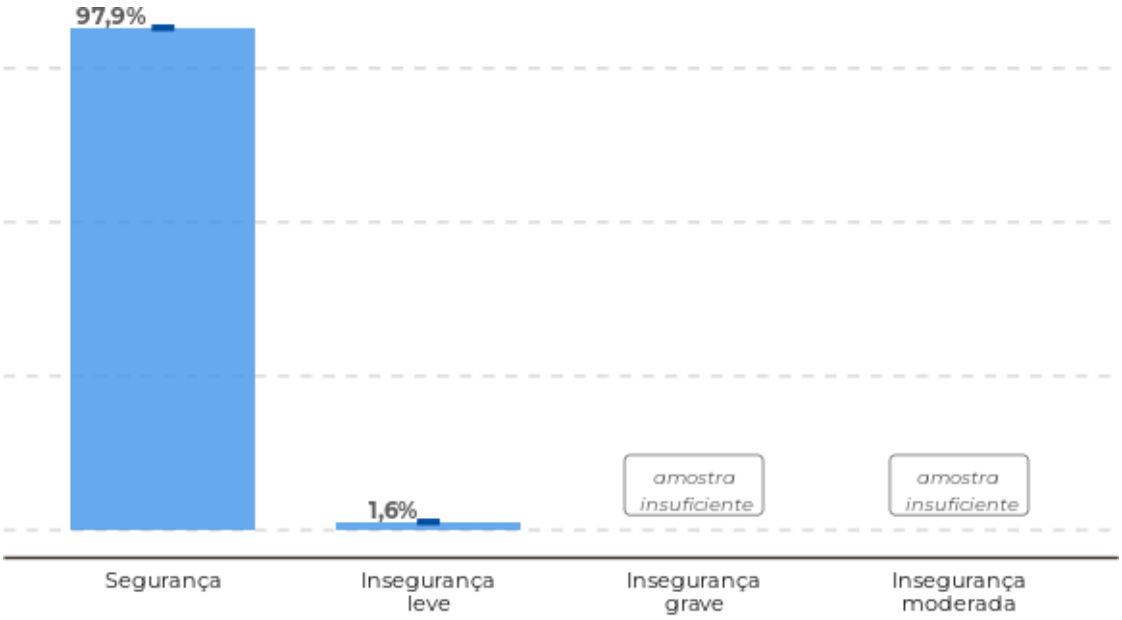

Fonte: CODEPLAN/DIEPS/GEREPS/PDAD 2021

5 CONSIDERAÇÕES FINAIS

Este relatório teve por objetivo apresentar os principais resultados da PDAD 2021. Apesar de ser um relatório amplo, abrangendo a grande maioria das questões investigadas pelo levantamento, ele não foi exaustivo. A riqueza das informações coletadas pela PDAD permite que diversas análises sejam realizadas, sobre os mais variados assuntos, os quais, por limitação de espaço e por objetividade, não puderam ser completamente explorados neste relatório.

Análises mais aprofundadas sobre os diversos temas da PDAD são comumente conduzidas pela própria Codeplan, em estudos específicos, divulgados no site da Companhia. A divulgação da PDAD 2021 permite que tais estudos sejam atualizados, além de possibilitar a realização de novas investigações, uma vez que novos temas foram adicionados nesta edição, como as investigações de identidade de gênero, orientação sexual e insegurança alimentar.

Além disso, a Codeplan disponibiliza os microdados de suas pesquisas em seu site para que a sociedade possa utilizar as informações coletadas da maneira mais ampla possível. Diversas perguntas podem ter suas respostas extraídas deste levantamento, o que faz da PDAD a principal fonte de dados para retratar os aspectos socioeconômicos do Distrito Federal e de suas Regiões Administrativas. Espera-se que essa nova edição da PDAD contribua com o entendimento do nosso território, com a produção de novos conhecimentos que, por seu turno, resultem em ações que melhorem a qualidade de vida da população.

ANEXOS

Tabelas relacionadas aos moradores

Características gerais e de migração

Tabela A.1: População por faixa etária e sexo, Asa Norte, 2021

	Feminino		Masculino	
Resposta	Total	%	Total	%
Total	62.633	52,9	55.817	47,1
até 4 anos	2.233	48,0	2.421	52,0
5 a 9 anos	2.308	48,1	2.494	51,9
10 a 14 anos	2.570	48,5	2.729	51,5
15 a 19 anos	2.830	48,6	2.988	51,4
20 a 24 anos	3.233	49,2	3.337	50,8
25 a 29 anos	4.192	51,8	3.898	48,2
30 a 34 anos	5.629	52,4	5.111	47,6
35 a 39 anos	6.513	51,1	6.223	48,9
40 a 44 anos	6.283	52,3	5.728	47,7
45 a 49 anos	5.349	52,9	4.764	47,1
50 a 54 anos	4.627	52,4	4.198	47,6
55 a 59 anos	4.356	54,6	3.619	45,4
60 a 64 anos	3.695	57,3	2.757	42,7
65 a 69 anos	3.050	58,7	2.145	41,3
70 a 74 anos	2.240	59,6	1.516	40,4
75 anos ou mais	3.525	65,1	1.889	34,9

Fonte: CODEPLAN/DIEPS/GEREPS/PDAD 2021

Tabela A.2: Arranjos domiciliares, Asa Norte, 2021

Resposta	Total	%
Total	48.413	100,0
Casal sem filhos	15.079	31,1
Unipessoal	14.687	30,3
Casal com 1 filho	7.139	14,7
Outro perfil	5.160	10,7
Monoparental (feminino)	4.337	9,0
Casal com 2 filhos	1.947	4,0
Casal com 3 filhos ou mais	(***)	(***)

Fonte: CODEPLAN/DIEPS/GEREPS/PDAD 2021

(***): Estimativa não divulgada por insuficiência de amostra

Tabela A.3: População por sexo, Asa Norte, 2021

Resposta	Total	%
Total	118.450	100,0
Feminino	62.633	52,9
Masculino	55.817	47,1

Fonte: CODEPLAN/DIEPS/GEREPS/PDAD 2021

Tabela A.4: Orientação sexual das pessoas com 18 anos ou mais, Asa Norte, 2021

Resposta	Total	%
Total	96.189	100,0
Heterossexual	88.949	92,5
Lésbicas, Gays, Bissexuais e outros	7.240	7,5

Fonte: CODEPLAN/DIEPS/GEREPS/PDAD 2021

Tabela A.5: População com 18 anos ou mais segundo identificação LGBTQIA+, Asa Norte, 2021

Resposta	Total	%
Total	99.904	100,0
Não LGBTQIA+	91.995	92,1
LGBTQIA+	7.909	7,9

Fonte: CODEPLAN/DIEPS/GEREPS/PDAD 2021

Tabela A.6: Pessoas com 18 anos ou mais que possuíam CNH, Asa Norte, 2021

Resposta	Total	%
Total	99.453	100,0
Sim	84.481	84,9
Não	14.972	15,1

Fonte: CODEPLAN/DIEPS/GEREPS/PDAD 2021

Tabela A.7: População por raça/cor da pele, Asa Norte, 2021

Resposta	Total	%
Total	118.450	100,0
Branca	69.105	58,3
Parda	37.099	31,3
Preta	10.149	8,6
Amarela	1.837	1,6
Indígena	(***)	(***)

Fonte: CODEPLAN/DIEPS/GEREPS/PDAD 2021
(***): Estimativa não divulgada por insuficiência de amostra

Tabela A.8: Estado civil das pessoas com 14 anos ou mais de idade, Asa Norte, 2021

Resposta	Total	%
Total	103.866	100,0
Casado	53.436	51,4
Solteiro	36.582	35,2
Viúvo	6.695	6,4
Divorciado	5.888	5,7
Desquitado ou separado judicialmente	1.265	1,2

Fonte: CODEPLAN/DIEPS/GEREPS/PDAD 2021

Tabela A.9: Pessoas nascidas no DF, Asa Norte, 2021

Resposta	Total	%
Total	118.450	100,0
Outro estado	76.206	64,3
DF	42.244	35,7

Fonte: CODEPLAN/DIEPS/GEREPS/PDAD 2021

Tabela A.10: Estado de nascimento das pessoas que vieram de fora do DF, Asa Norte, 2021

Resposta	Total	%
Total	17.314	100,0
Minas Gerais	3.532	20,4
Goiás	1.859	10,7
Acre	(***)	(***)
Alagoas	(***)	(***)
Amapá	(***)	(***)
Amazonas	(***)	(***)
Bahia	(***)	(***)
Ceará	(***)	(***)
Espírito Santo	(***)	(***)
Maranhão	(***)	(***)
Mato Grosso	(***)	(***)
Mato Grosso do Sul	(***)	(***)
Pará	(***)	(***)
Paraíba	(***)	(***)
Paraná	(***)	(***)
Pernambuco	(***)	(***)
Piauí	(***)	(***)
Rio de Janeiro	(***)	(***)
Rio Grande do Norte	(***)	(***)
Rio Grande do Sul	(***)	(***)
Rondônia	(***)	(***)
Roraima	(***)	(***)
Santa Catarina	(***)	(***)
São Paulo	(***)	(***)
Sergipe	(***)	(***)
Tocantins	(***)	(***)

Fonte: CODEPLAN/DIEPS/GEREPS/PDAD 2021
(***): Estimativa não divulgada por insuficiência de amostra

Tabela A.11: Motivação do chefe do domicílio a mudar e/ou retornar para o DF, Asa Norte, 2021

Resposta	Total	%
Total	5.951	100,0
Trabalho	2.635	44,3
Acompanhar Parentes / Reunião familiar	1.498	25,2
Estudo	488	8,2
Moradia	463	7,8
Outros motivos	(***)	(***)
Procura de Trabalho	(***)	(***)
Saúde	(***)	(***)

Fonte: CODEPLAN/DIEPS/GEREPS/PDAD 2021
(***): Estimativa não divulgada por insuficiência de amostra

Tabela A.12: Intenção e localidade para constituição de novo domicílio das pessoas de 14 anos ou mais, Asa Norte, 2021

Resposta	Total	%
Total	4.313	100,0
Plano Piloto	3.075	71,3
Águas Claras	(***)	(***)
Ceilândia	(***)	(***)
Gama	(***)	(***)
Guará	(***)	(***)
Jardim Botânico	(***)	(***)
Lago Norte	(***)	(***)
Núcleo Bandeirante	(***)	(***)
Riacho Fundo	(***)	(***)
Riacho Fundo II	(***)	(***)
Samambaia	(***)	(***)
Sobradinho	(***)	(***)
Taguatinga	(***)	(***)

Fonte: CODEPLAN/DIEPS/GEREPS/PDAD 2021
(***): Estimativa não divulgada por insuficiência de amostra

Saúde

Tabela A.13: Pessoas com dificuldade permanente de enxergar, Asa Norte, 2021

Resposta	Total	%
Total	116.741	100,0
Não têm dificuldade	100.997	86,5
Têm alguma dificuldade	14.902	12,8
Têm muita dificuldade	841	0,7

Fonte: CODEPLAN/DIEPS/GEREPS/PDAD 2021

Tabela A.14: Pessoas com dificuldade permanente de ouvir, Asa Norte, 2021

Resposta	Total	%
Total	116.741	100,0
Não têm dificuldade	112.013	96,0
Têm alguma dificuldade	3.905	3,3
Têm muita dificuldade	(***)	(***)
Têm, não consegue de modo algum	(***)	(***)

Fonte: CODEPLAN/DIEPS/GEREPS/PDAD 2021
(***): Estimativa não divulgada por insuficiência de amostra

Tabela A.15: Pessoas com dificuldade permanente de caminhar ou subir degraus, Asa Norte, 2021

Resposta	Total	%
Total	116.741	100,0
Não têm dificuldade	114.176	97,8
Têm alguma dificuldade	2.139	1,8
Têm muita dificuldade	(***)	(***)
Têm, não consegue de modo algum	(***)	(***)

Fonte: CODEPLAN/DIEPS/GEREPS/PDAD 2021
(***): Estimativa não divulgada por insuficiência de amostra

Tabela A.16: Pessoas com deficiência mental/intelectual permanente, Asa Norte, 2021

Resposta	Total	%
Total	116.741	100,0
Não têm dificuldade	115.257	98,7
Têm alguma dificuldade	(***)	(***)
Têm muita dificuldade	(***)	(***)

Fonte: CODEPLAN/DIEPS/GEREPS/PDAD 2021
(***): Estimativa não divulgada por insuficiência de amostra

Tabela A.17: Pessoas com dificuldade permanente para pegar pequenos objetos, Asa Norte, 2021

Resposta	Total	%
Total	116.741	100,0
Não têm dificuldade	115.505	98,9
Têm alguma dificuldade	(***)	(***)
Têm muita dificuldade	(***)	(***)

Fonte: CODEPLAN/DIEPS/GEREPS/PDAD 2021
(***): Estimativa não divulgada por insuficiência de amostra

Tabela A.18: Pessoas com plano de saúde privado, Asa Norte, 2021

Resposta	Total	%
Total	113.665	100,0
Sim	68.645	60,4
Não	45.019	39,6

Fonte: CODEPLAN/DIEPS/GEREPS/PDAD 2021

Tabela A.19: Tipo de plano de saúde privado, Asa Norte, 2021

Resposta	Total	%
Total	67.582	100,0
Individual/Familiar	54.494	80,6
Coletivos (empresarial)	12.070	17,9
Coletivos (adesão)	(***)	(***)

Fonte: CODEPLAN/DIEPS/GEREPS/PDAD 2021
(***): Estimativa não divulgada por insuficiência de amostra

Tabela A.20: Planos de saúde privado com coparticipação e/ou franquia, Asa Norte, 2021

Resposta	Total	%
Total	63.800	100,0
Não	36.810	57,7
Sim	26.990	42,3

Fonte: CODEPLAN/DIEPS/GEREPS/PDAD 2021

Tabela A.21: Último serviço de saúde utilizado, Asa Norte, 2021

Resposta	Total	%
Total	117.832	100,0
Posto de Saúde / Unidade Básica de Saúde	48.965	41,6
Consultório particular/ clinica privada	21.934	18,6
Nunca precisou	20.333	17,3
Farmácia	12.930	11,0
Pronto-socorro ou emergência de hospital público	7.221	6,1
Pronto-atendimento ou Urgência de hospital privado	4.693	4,0
Ambulatório de hospital público	(***)	(***)
Ambulatório ou consultório de empresa ou sindicato	(***)	(***)
Centro de Especialidades / Policlínica do SUS	(***)	(***)
No domicílio, com médico particular	(***)	(***)
No domicílio, com profissional da equipe de saúde da família	(***)	(***)
Outro serviço	(***)	(***)
UPA (Unidade de Pronto Atendimento)	(***)	(***)

Fonte: CODEPLAN/DIEPS/GEREPS/PDAD 2021

(***): Estimativa não divulgada por insuficiência de amostra

Tabela A.22: Motivo de atendimento de saúde utilizado da última vez, Asa Norte, 2021

Resposta	Total	%
Total	97.219	100,0
Vacinação	49.105	50,5
Doença (dor, febre, diarreia etc.)	19.950	20,5
Acomp. com psicólogo, nutricionista ou outro profissional de saúde	8.840	9,1
Exame complementar de diagnóstico (sangue, urina, imagem etc)	5.222	5,4
Prevenção	3.926	4,0
Continuação de tratamento de doença	3.257	3,4
Outro	2.619	2,7
Problema odontológico	1.261	1,3
Acidente, lesão ou fratura	1.196	1,2
Parto	(***)	(***)
Pré-natal	(***)	(***)
Reabilitação (Fisioterapia, fonoaudiologia etc)	(***)	(***)
Solicitação de atestado de saúde	(***)	(***)

Fonte: CODEPLAN/DIEPS/GEREPS/PDAD 2021

(***): Estimativa não divulgada por insuficiência de amostra

Tabela A.23: Localidade do atendimento do último serviço de saúde utilizado, Asa Norte, 2021

Resposta	Total	%
Total	97.437	100,0
Plano Piloto	96.136	98,7
Águas Claras	(***)	(***)
Fora do Distrito Federal	(***)	(***)
Gama	(***)	(***)
Lago Norte	(***)	(***)
Lago Sul	(***)	(***)
Núcleo Bandeirante	(***)	(***)
Samambaia	(***)	(***)
Sobradinho	(***)	(***)
Taguatinga	(***)	(***)

Fonte: CODEPLAN/DIEPS/GEREPS/PDAD 2021

(***): Estimativa não divulgada por insuficiência de amostra

Comunicação e informação

Tabela A.24: Posse de celular para uso pessoal, Asa Norte, 2021

Resposta	Total	%
Total	118.387	100,0
Sim	109.362	92,4
Não	9.025	7,6

Fonte: CODEPLAN/DIEPS/GEREPS/PDAD 2021

Tabela A.25: Posse de tablet para uso pessoal, Asa Norte, 2021

Resposta	Total	%
Total	118.370	100,0
Não	103.549	87,5
Sim	14.822	12,5

Fonte: CODEPLAN/DIEPS/GEREPS/PDAD 2021

Tabela A.26: Posse de linha pré-paga uso pessoal, Asa Norte, 2021

Resposta	Total	%
Total	118.177	100,0
Sim	66.006	55,9
Não	52.171	44,1

Fonte: CODEPLAN/DIEPS/GEREPS/PDAD 2021

Tabela A.27: Posse de linha pós-paga uso pessoal, Asa Norte, 2021

Resposta	Total	%
Total	118.102	100,0
Não	71.599	60,6
Sim	46.504	39,4

Fonte: CODEPLAN/DIEPS/GEREPS/PDAD 2021

Tabela A.28: Acesso à internet nos últimos três meses, Asa Norte, 2021

Resposta	Total	%
Total	117.834	100,0
Sim	107.562	91,3
Não	10.272	8,7

Fonte: CODEPLAN/DIEPS/GEREPS/PDAD 2021

Tabela A.29: Frequência de acesso à internet nos últimos três meses, Asa Norte, 2021

Resposta	Total	%
Total	106.898	100,0
Todos os dias	100.109	93,6
De 2 a 3 vezes por sem.	6.242	5,8
1 vez por sem.	(***)	(***)
Menos de 1 vez por mês	(***)	(***)

Fonte: CODEPLAN/DIEPS/GEREPS/PDAD 2021
(***): Estimativa não divulgada por insuficiência de amostra

Tabela A.30: Acesso à internet por meio de microcomputador/laptop, Asa Norte, 2021

Resposta	Total	%
Total	107.412	100,0
Sim	95.901	89,3
Não	11.511	10,7

Fonte: CODEPLAN/DIEPS/GEREPS/PDAD 2021

Tabela A.31: Acesso à internet por meio de celular/tablet, Asa Norte, 2021

Resposta	Total	%
Total	107.562	100,0
Sim	107.118	99,6
Não	(***)	(***)

Fonte: CODEPLAN/DIEPS/GEREPS/PDAD 2021
(***): Estimativa não divulgada por insuficiência de amostra

Tabela A.32: Acesso à internet por outro meio, Asa Norte, 2021

Resposta	Total	%
Total	107.053	100
Sim	94.178	88
Não	12.875	12

Fonte: CODEPLAN/DIEPS/GEREPS/PDAD 2021

Tabela A.33: Acesso à internet por motivo de trabalhar (pessoas com 14 anos ou mais), Asa Norte, 2021

Resposta	Total	%
Total	102.480	100,0
Sim	65.172	63,6
Não	37.308	36,4

Fonte: CODEPLAN/DIEPS/GEREPS/PDAD 2021

Tabela A.34: Acesso à internet por motivo de educação/cursos, Asa Norte, 2021

Resposta	Total	%
Total	107.248	100,0
Sim	73.129	68,2
Não	34.118	31,8

Fonte: CODEPLAN/DIEPS/GEREPS/PDAD 2021

Tabela A.35: Acesso à internet por motivo de informações/notícias, Asa Norte, 2021

Resposta	Total	%
Total	107.206	100,0
Sim	100.435	93,7
Não	6.771	6,3

Fonte: CODEPLAN/DIEPS/GEREPS/PDAD 2021

Tabela A.36: Acesso à internet por motivo de criação/compartilhamento de conteúdo, Asa Norte, 2021

Resposta	Total	%
Total	106.976	100
Sim	69.568	65
Não	37.407	35

Fonte: CODEPLAN/DIEPS/GEREPS/PDAD 2021

Tabela A.37: Acesso à internet por motivo de multimídia (lazer e cultura), Asa Norte, 2021

Resposta	Total	%
Total	107.063	100,0
Sim	100.860	94,2
Não	6.203	5,8

Fonte: CODEPLAN/DIEPS/GEREPS/PDAD 2021

Tabela A.38: Acesso à internet por motivo de comunicação, Asa Norte, 2021

Resposta	Total	%
Total	107.404	100,0
Sim	102.577	95,5
Não	4.827	4,5

Fonte: CODEPLAN/DIEPS/GEREPS/PDAD 2021

Tabela A.39: Acesso à internet por motivo de transações financeiras/comerciais, Asa Norte, 2021

Resposta	Total	%
Total	107.163	100,0
Sim	87.708	81,8
Não	19.455	18,2

Fonte: CODEPLAN/DIEPS/GEREPS/PDAD 2021

Educação

Tabela A.40: Pessoas com cinco anos ou mais que sabem ler e escrever, Asa Norte, 2021

Resposta	Total	%
Total	113.475	100,0
Sim	111.813	98,5
Não	1.662	1,5

Fonte: CODEPLAN/DIEPS/GEREPS/PDAD 2021

Tabela A.41: Frequência escolar da população entre 4 e 24 anos, Asa Norte, 2021

Resposta	Total	%
Total	23.515	100,0
Sim, particular	9.694	41,2
Sim, pública	8.928	38,0
Não, mas já frequentou	4.650	19,8
Não, nunca frequentou	(***)	(***)

Fonte: CODEPLAN/DIEPS/GEREPS/PDAD 2021
(***): Estimativa não divulgada por insuficiência de amostra

Tabela A.42: Modalidade de ensino dos estudantes, Asa Norte, 2021

	Educação a Distância (EaD)		Híbrida ou semipresencial		Presencial	
Resposta	Total	%	Total	%	Total	%
Creche/Educ. Infantil	(***)	(***)	(***)	(***)	2.823	78,9
EJA/AJA	(***)	(***)	(***)	(***)	(***)	(***)
Ens. fundamental	(***)	(***)	2.942	34,7	5.409	63,7
Ens. médio	(***)	(***)	(***)	(***)	2.409	67,0
Ens. Superior/Pós-grad.	1.296	22,7	1.488	26,1	2.927	51,3

Fonte: CODEPLAN/DIEPS/GEREPS/PDAD 2021
(***): Estimativa não divulgada por insuficiência de amostra

Tabela A.43: Turno de estudo dos alunos, Asa Norte, 2021

	Integral		Matutino		Noturno		Vespertino	
Resposta	Total	%	Total	%	Total	%	Total	%
Creche/Educ. Infantil	1.270	36,3	1.677	47,9	(***)	(***)	(***)	(***)
EJA/AJA	(***)	(***)	(***)	(***)	(***)	(***)	(***)	(***)
Ens. fundamental	(***)	(***)	5.029	59,8	(***)	(***)	2.911	34,6
Ens. médio	(***)	(***)	2.852	80,6	(***)	(***)	(***)	(***)
Ens. Superior/Pós-grad.	(***)	(***)	1.728	40,2	1.256	29,2	(***)	(***)

Fonte: CODEPLAN/DIEPS/GEREPS/PDAD 2021
(***): Estimativa não divulgada por insuficiência de amostra

Tabela A.44: Frequência escolar, por faixa de idade, Asa Norte, , 2021

	Frequenta		Não frequenta	
Resposta	Total	%	Total	%
Até 3 anos	826	22,8	2.803	77,2
Entre 4 e 5 anos	2.179	92,6	(***)	(***)
Entre 6 e 14	8.731	99,5	(***)	(***)
Entre 15 e 17	3.648	96,2	(***)	(***)

Fonte: CODEPLAN/DIEPS/GEREPS/PDAD 2021
(***): Estimativa não divulgada por insuficiência de amostra

Tabela A.45: Região Administrativa/Município da unidade de estudo, Asa Norte, 2021

Resposta	Total	%
Total	21.220	100,0
Plano Piloto	20.956	98,8
Águas Claras	(***)	(***)
Gama	(***)	(***)
Sobradinho	(***)	(***)
Taguatinga	(***)	(***)

Fonte: CODEPLAN/DIEPS/GEREPS/PDAD 2021
(***): Estimativa não divulgada por insuficiência de amostra

Tabela A.46: Principal meio de transporte da casa até a unidade de ensino, Asa Norte, 2021

Resposta	Total	%
Total	21.602	100,0
Automóvel	10.870	50,3
Ônibus	4.057	18,8
Transporte escolar privado	4.055	18,8
A pé	1.608	7,4
Bicicleta	(***)	(***)
Motocicleta	(***)	(***)
Transporte escolar público	(***)	(***)
Transporte privado (táxi, app etc.)	(***)	(***)

Fonte: CODEPLAN/DIEPS/GEREPS/PDAD 2021

(***): Estimativa não divulgada por insuficiência de amostra

Tabela A.47: Tempo de deslocamento utilizado até a unidade de ensino, Asa Norte, 2021

Resposta	Total	%
Total	22.136	100,0
Até 15 minutos	12.277	55,5
Mais de 15 até 30 minutos	8.265	37,3
Mais de 30 até 45 minutos	961	4,3
Mais de 1 hora até 1 hora e 15 minutos	(***)	(***)
Mais de 1 hora e 45 minutos até 2 horas	(***)	(***)
Mais de 45 minutos até 1 hora	(***)	(***)
Não sabe	(***)	(***)

Fonte: CODEPLAN/DIEPS/GEREPS/PDAD 2021

(***): Estimativa não divulgada por insuficiência de amostra

Tabela A.48: Escolaridade das pessoas com 25 anos ou mais de idade, Asa Norte, 2021

Resposta	Total	%
Total	88.689	100,0
Superior completo	65.558	73,9
Médio completo	14.467	16,3
Superior incompleto	4.726	5,3
Fundamental completo	2.014	2,3
Sem escolaridade	(***)	(***)
Fundamental incompleto	(***)	(***)
Médio incompleto	(***)	(***)

Fonte: CODEPLAN/DIEPS/GEREPS/PDAD 2021

(***): Estimativa não divulgada por insuficiência de amostra

Trabalho e rendimento

Tabela A.49: Distribuição da população em idade ativa (PIA - 14 anos ou mais), segundo situação de atividade, Asa Norte, 2021

Resposta	Total	%
Total	104.615	100
PEA	59.609	57
Inativa	45.006	43

Fonte: CODEPLAN/DIEPS/GEREPS/PDAD 2021

Tabela A.50: Distribuição da população economicamente ativa (PEA - 14 anos ou mais), segundo situação de ocupação, Asa Norte, 2021

Resposta	Total	%
Total	59.506	100,0
Ocupada	57.507	96,6
Desocupada	1.998	3,4

Fonte: CODEPLAN/DIEPS/GEREPS/PDAD 2021

Tabela A.51: Distribuição da população economicamente ativa (PEA - 14 anos ou mais), segundo situação de ocupação, Asa Norte, 2021

Resposta	Total	%
Total	59.506	100,0
Ocupada	57.507	96,6
Desocupada	1.998	3,4

Fonte: CODEPLAN/DIEPS/GEREPS/PDAD 2021
Obs.: Exclusive pessoas sem classificação de ocupação.

Tabela A.52: Pessoas entre 18 e 29 anos por situação de trabalho e estudo, Asa Norte, 2021

Resposta	Total	%
Total	16.687	100,0
Outro	12.868	77,1
Nem-nem	3.820	22,9

Fonte: CODEPLAN/DIEPS/GEREPS/PDAD 2021

Tabela A.53: Pessoas entre 18 e 29 anos por situação de trabalho, estudo e procura por trabalho nos últimos 30 dias, Asa Norte, 2021

Resposta	Total	%
Total	16.545	100,0
Outro	12.868	77,8
Nem-nem (não procurou trabalho)	3.219	19,5
Nem-nem (procurou trabalho)	458	2,8

Fonte: CODEPLAN/DIEPS/GEREPS/PDAD 2021

Tabela A.54: Região Administrativa de exercício do trabalho principal, Asa Norte, 2021

Resposta	Total	%
Total	55.981	100,0
Plano Piloto	53.557	95,7
Águas Claras	(***)	(***)
Brazlândia	(***)	(***)
Cruzeiro	(***)	(***)
Formosa (Goiás)	(***)	(***)
Gama	(***)	(***)
Guará	(***)	(***)
Jardim Botânico	(***)	(***)
Lago Norte	(***)	(***)
Lago Sul	(***)	(***)
Luziânia (Goiás)	(***)	(***)
Outros locais	(***)	(***)
Paranoá	(***)	(***)
Planaltina (Goiás)	(***)	(***)
SIA	(***)	(***)
Sobradinho	(***)	(***)
Sobradinho II	(***)	(***)
Sudoeste/ Octogonal	(***)	(***)
Taguatinga	(***)	(***)
Vários locais	(***)	(***)

Fonte: CODEPLAN/DIEPS/GEREPS/PDAD 2021
(***): Estimativa não divulgada por insuficiência de amostra

Tabela A.66: Rendimento bruto do trabalho principal em faixas de salário mínimo, Asa Norte, 2021

Faixas	Total	%
Até 1	(***)	(***)
Mais de 1 até 2	2.463	11,2
Mais de 2 até 5	6.644	30,3
Mais de 5 até 10	6.470	29,5

Mais de 10 até 20	4.729	21,5
Mais de 20	(***)	(***)

Fonte: CODEPLAN/DIEPS/GEREPS/PDAD 2021
(***): Estimativa não divulgada por insuficiência de amostra
Obs.1: Salários mínimos em R$ de Jul/2021, pelo IPCA/Brasília
Obs.2: Salário mínimo de R$ 1.100,00.

Tabela A.55: Setor de atividade das pessoas ocupadas, Asa Norte, 2021

Resposta	Total	%
Total	52.414	100,0
Outros serviços	27.461	52,4
Adm. Pública	6.865	13,1
Comércio	6.654	12,7
Educação, saúde e serviços sociais	6.038	11,5
Construção	1.862	3,6
Indústria	1.397	2,7
Agropecuária	(***)	(***)
Serviços domésticos	(***)	(***)
Serviços por aplicativo	(***)	(***)

Fonte: CODEPLAN/DIEPS/GEREPS/PDAD 2021
(***): Estimativa não divulgada por insuficiência de amostra

Tabela A.56: Posição na ocupação do trabalho principal, Asa Norte, 2021

Resposta	Total	%
Total	49.295	100,0
Empregado no setor privado (exceto doméstico)	24.291	49,3
Empregado no setor público	15.579	31,6
Conta própria ou autônomo	4.577	9,3
Forças Armadas/ Polícia Militar/ Bombeiros	2.903	5,9
Dono de negócio familiar	(***)	(***)
Empregado doméstico	(***)	(***)
Empregador	(***)	(***)
Estágio remunerado	(***)	(***)
Profissional liberal (autônomo univesitário)	(***)	(***)
Sócio de cooperativa	(***)	(***)

Fonte: CODEPLAN/DIEPS/GEREPS/PDAD 2021
(***): Estimativa não divulgada por insuficiência de amostra

Tabela A.57: Área de atuação dos servidores/empregados públicos, Asa Norte, 2021

Resposta	Total	%
Total	18.347	100,0
Federal	14.387	78,4
Estadual/Distrital	3.768	20,5
Municipal	(***)	(***)

Fonte: CODEPLAN/DIEPS/GEREPS/PDAD 2021
(***): Estimativa não divulgada por insuficiência de amostra

Tabela A.58: Modalidade de contratação dos servidores/empregados públicos, Asa Norte, 2021

Resposta	Total	%
Total	18.244	100,0
Estatutário	12.308	67,5
Carteira de trabalho (CLT)	5.498	30,1
Contrato de trabalho	(***)	(***)
Emprego em comissão	(***)	(***)

Fonte: CODEPLAN/DIEPS/GEREPS/PDAD 2021
(***): Estimativa não divulgada por insuficiência de amostra

Tabela A.59: Sócios de cooperativas, autônomos, empregadores, donos de negócios familiares e profissionais liberais que eram Microempreendedores Individuais (MEI), Asa Norte, 2021

Resposta	Total	%
Total	5.037	100,0
Não	2.716	53,9
Sim	2.322	46,1

Fonte: CODEPLAN/DIEPS/GEREPS/PDAD 2021

Tabela A.60: Sócios de cooperativas, autônomos, empregadores, donos de negócios familiares e profissionais liberais que possuíam CNPJ, Asa Norte, 2021

Resposta	Total	%
Total	5.464	100,0
Sim	3.985	72,9
Não	1.478	27,1

Fonte: CODEPLAN/DIEPS/GEREPS/PDAD 2021

Tabela A.61: Meios de transporte para o trabalho principal, Asa Norte, 2021

	Total		%	
Variável	Sim	Não	Sim	Não
Ônibus	12.674	44.323	22,2	77,8
Automóvel	45.850	11.147	80,4	19,6
Transporte privado	5.574	51.383	9,8	90,2
Metrô	811	56.186	1,4	98,6
Motocicleta	1.582	55.415	2,8	97,2
Bicicleta	(***)	56.659	(***)	99,4
A pé	2.977	54.019	5,2	94,8

Fonte: CODEPLAN/DIEPS/GEREPS/PDAD 2021
(***): Estimativa não divulgada por insuficiência de amostra

Tabela A.62: Principal meio de transporte utilizado para o trabalho principal, Asa Norte, 2021

Resposta	Total	%
Total	56.997	100,0
Automóvel	42.173	74,0
Ônibus	8.315	14,6
Transporte privado	2.688	4,7
A pé	2.161	3,8
Motocicleta	1.406	2,5
Bicicleta	(***)	(***)
Metrô	(***)	(***)

Fonte: CODEPLAN/DIEPS/GEREPS/PDAD 2021
(***): Estimativa não divulgada por insuficiência de amostra

Tabela A.63: Tempo de deslocamento até o trabalho principal, Asa Norte, 2021

Resposta	Total	%
Total	56.997	100,0
Até 15 minutos	32.387	56,8
Mais de 15 até 30 minutos	19.552	34,3
Mais de 30 até 45 minutos	4.211	7,4
Mais de 1 hora até 1 hora e 15 minutos	(***)	(***)
Mais de 1 hora e 45 minutos até 2 horas	(***)	(***)
Mais de 2 horas	(***)	(***)
Mais de 45 minutos até 1 hora	(***)	(***)
Não sabe	(***)	(***)

Fonte: CODEPLAN/DIEPS/GEREPS/PDAD 2021
(***): Estimativa não divulgada por insuficiência de amostra

Tabela A.64: Pessoas com carteira de trabalho assinada pelo atual empregador no trabalho principal, Asa Norte, 2021

Resposta	Total	%
Total	30.595	100,0
Sim	28.028	91,6
Não	2.566	8,4

Fonte: CODEPLAN/DIEPS/GEREPS/PDAD 2021

Tabela A.65: Pessoas que contribuem com a previdência pública, Asa Norte, 2021

Resposta	Total	%
Total	100.675	100,0
Sim	63.113	62,7
Não	37.562	37,3

Fonte: CODEPLAN/DIEPS/GEREPS/PDAD 2021

Tabela A.67: Rendimento bruto domiciliar por faixas de salário mínimo, Asa Norte, 2021

Faixas	N	%
Até 1	(***)	(***)
Mais de 1 até 2	849	6,3
Mais de 2 até 5	3.856	28,5
Mais de 5 até 10	3.757	27,8
Mais de 10 até 20	2.980	22,0
Mais de 20	1.915	14,2

Fonte: CODEPLAN/DIEPS/GEREPS/PDAD 2021

Obs.1: Salários mínimos em R$ de Jul/2021, pelo IPCA/Brasília

Obs.2: Salário mínimo de R$ 1.100,00.

Tabelas relacionadas aos domicílios

Características do domicílio particular

Tabela A.68: Domicílios ocupados segundo a espécie, Asa Norte, 2021

Resposta	Total	%
Total	48.413	100,0
Permanente	43.650	90,2
Improvisado	4.763	9,8

Fonte: CODEPLAN/DIEPS/GEREPS/PDAD 2021

Tabela A.69: Domicílios ocupados segundo o tipo, Asa Norte, 2021

Resposta	Total	%
Total	48.413	100,0
Apartamentos	45.432	93,8
Quitinetes/Estúdios/Flats	1.398	2,9
Casas fora de condomínio	1.382	2,9
Casas em condomínio	(***)	(***)
Cômodos	(***)	(***)

Fonte: CODEPLAN/DIEPS/GEREPS/PDAD 2021
(***): Estimativa não divulgada por insuficiência de amostra

Tabela A.70: Domicílios ocupados segundo a situação de ocupação, Asa Norte, 2021

Resposta	Total	%
Total	48.349	100,0
Próprio, já pago	24.713	51,1
Alugado	16.289	33,7
Próprio, ainda pagando	3.696	7,6
Cedido pelo empregador	2.066	4,3
Cedido por outro	1.585	3,3

Fonte: CODEPLAN/DIEPS/GEREPS/PDAD 2021

Tabela A.71: Domicílios ocupados segundo regularização do lote, Asa Norte,

Resposta	Total	%
Total	26.605	100,0
Sim	26.100	98,1
Não	505	1,9

Fonte: CODEPLAN/DIEPS/GEREPS/PDAD 2021

Tabela A.72: Material predominante nas paredes externas do domicílio, Asa Norte, 2021

Resposta	Total	%
Total	48.413	100,0
Alvenaria com revestimento	46.706	96,5
Outros	1.353	2,8
Alvenaria sem revestimento	(***)	(***)
Madeira para construção	(***)	(***)

Fonte: CODEPLAN/DIEPS/GEREPS/PDAD 2021
(***): Estimativa não divulgada por insuficiência de amostra

Tabela A.73: Material predominante no piso do domicílio, Asa Norte, 2021

Resposta	Total	%
Total	48.413	100,0
Cerâmica / Porcel. / madeira	46.149	95,3
Contra piso	2.019	4,2
Cimento alisado	(***)	(***)
Outros	(***)	(***)

Fonte: CODEPLAN/DIEPS/GEREPS/PDAD 2021
(***): Estimativa não divulgada por insuficiência de amostra

Tabela A.74: Material predominante na cobertura (telhado) do domicílio, Asa Norte, 2021

Resposta	Total	%
Total	48.413	100,0
Só laje	45.593	94,2
Telha, exceto fibrocimento, com laje	2.032	4,2
Fibrocimento com laje	(***)	(***)
Outros	(***)	(***)
Telha, exceto fibrocimento, sem laje	(***)	(***)

Fonte: CODEPLAN/DIEPS/GEREPS/PDAD 2021
(***): Estimativa não divulgada por insuficiência de amostra

Tabela A.75: Abastecimento de água no domicílio, Asa Norte, 2021

	Total		%	
Variável	Sim	Não	Sim	Não
Rede Geral (CAESB)	48.381	(***)	99,9	(***)
Poço/Cisterna	(***)	48.284	(***)	99,9
Poço artesiano	(***)	48.284	(***)	99,9
Captação de água da chuva	(***)	48.316	(***)	99,9
Gambiarra/gato	(***)	48.284	(***)	99,9
Caixa d'água	45.307	1.038	97,8	2,2

Fonte: CODEPLAN/DIEPS/GEREPS/PDAD 2021
(***): Estimativa não divulgada por insuficiência de amostra

Tabela A.76: Esgotamento sanitário do domicílio, Asa Norte, 2021

	Total		%	
Variável	Sim	Não	Sim	Não
Rede Geral (CAESB)	48.381	(***)	99,9	(***)
Fossa séptica	(***)	48.349	(***)	99,9
Fossa rudimentar	(***)	48.413	(***)	100,0
Esgotamento a céu aberto	(***)	48.413	(***)	100,0

Fonte: CODEPLAN/DIEPS/GEREPS/PDAD 2021
(***): Estimativa não divulgada por insuficiência de amostra

Tabela A.77: Abastecimento de energia elétrica no domicílio, Asa Norte, 2021

	Total		%	
Variável	Sim	Não	Sim	Não
Rede Geral (CAESB)	48.413	(***)	100	(***)
Próprio (gerador a combustível)	(***)	47.543	(***)	99,9
Próprio (gerador solar)	(***)	46.129	(***)	99,9
Outras fontes renováveis	(***)	47.543	(***)	100,0
Gambiarra/gato	(***)	48.316	(***)	100,0

Fonte: CODEPLAN/DIEPS/GEREPS/PDAD 2021
(***): Estimativa não divulgada por insuficiência de amostra

Tabela A.78: Recolhimento do lixo no domicílio, Asa Norte, 2021

	Total		%	
Variável	Sim	Não	Sim	Não
Coleta seletiva direta	41.002	6.856	85,7	14,3
Coleta convencional direta (não seletiva)	46.466	1.811	96,2	3,8
Coleta indireta	44.549	3.800	92,1	7,9
Jogado em local impróprio	(***)	48.180	(***)	99,6
Outro (enterrado ou queimado)	(***)	48.084	(***)	99,5
Separação do lixo	38.700	9.648	80,0	20,0

Fonte: CODEPLAN/DIEPS/GEREPS/PDAD 2021
(***): Estimativa não divulgada por insuficiência de amostra

Tabela A.79: Infraestrutura urbana na rua de acesso dos domicílios, Asa Norte, 2021

	Total		%	
Variável	Sim	Não	Sim	Não
Rua asfaltada/pavimentada	48.220	(***)	99,7	(***)
Rua com calçada	48.032	(***)	99,3	(***)
Rua com iluminação	47.831	582	98,8	1,2
Drenagem de água da chuva	46.570	(***)	98,6	(***)

Fonte: CODEPLAN/DIEPS/GEREPS/PDAD 2021
(***): Estimativa não divulgada por insuficiência de amostra

Tabela A.80: Qualidade da calçada, Asa Norte, 2021

Resposta	Total	%
Total	48.032	100,0
Boa	30.618	63,7
Regular	8.395	17,5
Ótima	7.431	15,5
Ruim	1.221	2,5
Péssima	(***)	(***)

Fonte: CODEPLAN/DIEPS/GEREPS/PDAD 2021
(***): Estimativa não divulgada por insuficiência de amostra

Tabela A.81: Problemas nas cercanias do domicílio, Asa Norte, 2021

	Total		%	
Variável	Sim	Não	Sim	Não
Erosão	2.616	43.994	5,6	94,4
Área em declive	708	47.254	1,5	98,5
Entulho	1.734	46.293	3,6	96,4
Esgoto a céu aberto	(***)	47.697	(***)	99,1
Ruas Alagadas	5.068	42.862	10,6	89,4
Ruas esburacadas	7.466	40.560	15,5	84,5

Fonte: CODEPLAN/DIEPS/GEREPS/PDAD 2021
(***): Estimativa não divulgada por insuficiência de amostra

Tabela A.82: Infraestrutura urbana e equipamentos públicos nas cercanias do domicílio, Asa Norte, 2021

	Total		%	
Variável	Sim	Não	Sim	Não
Ruas arborizadas	46.491	(***)	99,4	(***)
Jardins ou parques	44.972	3.215	93,3	6,7
Praça	46.784	1.436	97,0	3,0
Espaço cultural	38.893	8.628	81,8	18,2
Academia comunitária/PEC	44.713	2.991	93,7	6,3
Quadras esportivas	45.308	2.622	94,5	5,5
Ciclovia/ciclofaixa	46.184	1.810	96,2	3,8
Travessia sinalizada para pedestres	47.663	621	98,7	1,3
Ponto de ônibus	47.572	680	98,6	1,4

Fonte: CODEPLAN/DIEPS/GEREPS/PDAD 2021

Tabela A.83: Segurança nas proximidades do domicílio, Asa Norte, 2021

	Total		%	
Variável	Sim	Não	Sim	Não
Policiamento militar regular	44.374	3.162	93,3	6,7
Serviço/equipamento particular de segurança	16.066	32.283	33,2	66,8
Serviço/equipamento coletivo de segurança	27.017	21.299	55,9	44,1

Fonte: CODEPLAN/DIEPS/GEREPS/PDAD 2021

Serviços domiciliares inventário de bens duráveis

Tabela A.84: Contratação de serviços pelos domicílios, Asa Norte, 2021

	Total		%	
Variável	Sim	Não	Sim	Não
TV por assinatura	31.233	17.116	64,6	35,4
Assinatura de revistas/jornais impressos	5.962	42.386	12,3	87,7
Assinatura de serviços on-line	42.866	5.282	89,0	11,0

Fonte: CODEPLAN/DIEPS/GEREPS/PDAD 2021

Tabela A.85: Acesso à internet no domicílio, Asa Norte, 2021

Resposta	Total	%
Total	48.413	100,0
Próprio	47.140	97,4
Compartilhado	1.209	2,5
Sem acesso	(***)	(***)

Fonte: CODEPLAN/DIEPS/GEREPS/PDAD 2021
(***): Estimativa não divulgada por insuficiência de amostra

Tabela A.86: Tipo de acesso à internet no domicílio, Asa Norte, 2021

	Total		%	
Variável	Sim	Não	Sim	Não
Banda larga fixa	46.838	1.511	96,9	3,1
Banda larga móvel	48.316	(***)	99,9	(***)

Fonte: CODEPLAN/DIEPS/GEREPS/PDAD 2021
(***): Estimativa não divulgada por insuficiência de amostra

Tabela A.87: Posse de veículos no domicílio, Asa Norte, 2021

	Total		%	
Variável	Sim	Não	Sim	Não
Automóvel	41.225	7.091	85,3	14,7
Motocicleta	4.409	43.907	9,1	90,9
Bicicleta	13.873	34.371	28,8	71,2

Fonte: CODEPLAN/DIEPS/GEREPS/PDAD 2021

Tabela A.88: Inventário de bens duráveis dos domicílios, Asa Norte, 2021

	Total		%	
Variável	Sim	Não	Sim	Não
Fogão	48.252	(***)	99,7	(***)
Microondas	44.527	3.886	92,0	8,0
Geladeira de uma porta	16.461	31.952	34,0	66,0
Geladeira de duas ou mais portas	32.103	16.310	66,3	33,7
Freezer	8.392	40.021	17,3	82,7
Máquina de lavar roupas	32.188	16.225	66,5	33,5
Máquina de lavar e secar roupas	14.877	33.536	30,7	69,3
Secadora de roupas	7.366	41.047	15,2	84,8
Máquina de lavar louça	6.163	42.250	12,7	87,3
Televisor tubo	1.006	47.407	2,1	97,9
Televisor tela fina/plana	47.581	832	98,3	1,7
DVD/BLU-RAY	4.156	44.257	8,6	91,4
Microcomputadore/Desktop	17.983	30.430	37,1	62,9
Notebook/Laptop	39.924	8.489	82,5	17,5
Ar-condicionado	30.172	18.241	62,3	37,7
Circulador e/ou ventiladores de ar	26.345	22.068	54,4	45,6
Telefones fixos	22.501	25.912	46,5	53,5
Placas de aquecedor solar	(***)	47.930	(***)	99,0

Fonte: CODEPLAN/DIEPS/GEREPS/PDAD 2021

(***): Estimativa não divulgada por insuficiência de amostra

Tabela A.89: Utilização de serviços domésticos nos domicílios, Asa Norte, 2021

	Total		%	
Variável	Sim	Não	Sim	Não
Mensalista	5.113	43.236	10,6	89,4
Diarista	20.040	28.179	41,6	58,4

Fonte: CODEPLAN/DIEPS/GEREPS/PDAD 2021

Tabela A.90: Frequência mensal da utilização de serviço doméstico do tipo diarista, Asa Norte, 2021

Resposta	Total	%
Total	17.786	100,0
Duas vezes por mês	6.850	38,5
Quatro vezes por mês	5.898	33,2
Três vezes por mês	2.539	14,3
Uma vez por mês	2.499	14,1

Fonte: CODEPLAN/DIEPS/GEREPS/PDAD 2021

Localidades predominantes de compras

Tabela A.91: Locais predominantes de compra de artigos de alimentação, higiene e limpeza, Asa Norte, 2021

Resposta	Total	%
Total	48.381	100,0
Plano Piloto	47.762	98,7
Águas Claras	(***)	(***)
Gama	(***)	(***)
Pela internet	(***)	(***)
Planaltina	(***)	(***)
Recanto das Emas	(***)	(***)
Scia e Estrutural	(***)	(***)
SIA	(***)	(***)
Sobradinho	(***)	(***)
Taguatinga	(***)	(***)

Fonte: CODEPLAN/DIEPS/GEREPS/PDAD 2021
(***): Estimativa não divulgada por insuficiência de amostra

Tabela A.92: Locais predominantes de compra de artigos de eletrodomésticos, Asa Norte, 2021

Resposta	Total	%
Total	48.284	100,0
Plano Piloto	43.780	90,7
Pela internet	2.231	4,6
Não comprou	1.840	3,8
Gama	(***)	(***)
Planaltina	(***)	(***)
SIA	(***)	(***)
Sobradinho	(***)	(***)
Taguatinga	(***)	(***)

Fonte: CODEPLAN/DIEPS/GEREPS/PDAD 2021
(***): Estimativa não divulgada por insuficiência de amostra

Tabela A.93: Locais predominantes de compra de material de construção/manutenção, Asa Norte, 2021

Resposta	Total	%
Total	48.155	100,0
Plano Piloto	41.611	86,4
Não comprou	6.007	12,5
Gama	(***)	(***)
Outros locais	(***)	(***)
Pela internet	(***)	(***)
Planaltina	(***)	(***)
Scia e Estrutural	(***)	(***)
SIA	(***)	(***)
Sobradinho	(***)	(***)
Taguatinga	(***)	(***)

Fonte: CODEPLAN/DIEPS/GEREPS/PDAD 2021
(***): Estimativa não divulgada por insuficiência de amostra

Tabela A.94: Locais predominantes de compra de material de serviços em geral (exceto limpeza doméstica), Asa Norte, 2021

Resposta	Total	%
Total	48.373	100,0
Plano Piloto	46.548	96,2
Não comprou	1.367	2,8
Gama	(***)	(***)
Outros locais	(***)	(***)
Pela internet	(***)	(***)
Planaltina	(***)	(***)
SIA	(***)	(***)
Sobradinho	(***)	(***)
Taguatinga	(***)	(***)

Fonte: CODEPLAN/DIEPS/GEREPS/PDAD 2021
(***): Estimativa não divulgada por insuficiência de amostra

Animais de estimação

Tabela A.95: Existência de gatos, cachorros, aves, peixes ou outros animais domésticos no domicílio, Asa Norte, 2021

	Total		%	
Variável	Sim	Não	Sim	Não
Gato	3.968	44.445	8,2	91,8
Cachorro	8.875	39.538	18,3	81,7
Ave	(***)	47.980	(***)	99,1
Peixe	691	47.722	1,4	98,6
Outro	562	47.851	1,2	98,8

Fonte: CODEPLAN/DIEPS/GEREPS/PDAD 2021
(***): Estimativa não divulgada por insuficiência de amostra

Segurança alimentar

Tabela A.96: Distribuição dos domicílios por situação de segurança alimentar nos últimos 3 meses, Asa Norte, 2021

Resposta	Total	%
Total	47.898	100,0
Segurança	46.877	97,9
Insegurança leve	748	1,6
Insegurança moderada	(***)	(***)
Insegurança grave	(***)	(***)

Fonte: CODEPLAN/DIEPS/GEREPS/PDAD 2021
(***): Estimativa não divulgada por insuficiência de amostra

Companhia de Planejamento do Distrito Federal – Codeplan
Setor de Administração Municipal
SAM, Bloco H, Setores Complementares
Ed. Sede Codeplan

CEP: 70620-080 - Brasília-DF
Fone: (0xx61) 3342-2222
<www.codeplan.df.gov.br>
codeplan@codeplan.df.gov.br

codeplan
COMPANHIA DE PLANEJAMENTO DO DISTRITO FEDERAL