PDAD 2021

PESQUISA DISTRITAL POR AMOSTRA DE DOMICÍLIOS

RELATÓRIO CODEPLAN

LAGO SUL

codeplan

GOVERNO DO DISTRITO FEDERAL

Ibaneis Rocha Barros Junior

Governador

Paco Britto

Vice-Governador

SECRETARIA DE ESTADO DE FAZENDA, PLANEJAMENTO, ORÇAMENTO E GESTÃO DO DISTRITO FEDERAL – SEFP

José Itamar Feitosa

Secretário

COMPANHIA DE PLANEJAMENTO DO DISTRITO FEDERAL – CODEPLAN

Jeansley Lima

Presidente

Sônia Gontijo Chagas Gonzaga

Diretora Administrativo e Financeiro

Clarissa Jahns Schlabitz

Diretora de Estudos e Pesquisas Socioeconômicas

Daienne Amaral Machado

Diretora de Estudos e Políticas Sociais

Renata Florentino de Faria Santos

Diretora de Estudos Urbanos e Ambientais

Brasília – DF

2022

Atualizado em 09/07/2022

codeplan

COMPANHIA DE PLANEJAMENTO DO DISTRITO FEDERAL

EQUIPE TÉCNICA

DIRETORIA DE ESTUDOS E PESQUISAS SOCIOECONÔMICAS – DIEPS

Clarissa Jahns Schlabitz
Diretora

Thiago Mendes Rosa
Chefe de Gabinete

Simone de Araújo Carvalho
Assistente

GERÊNCIA DE PESQUISAS SOCIOECONÔMICAS – GEREPS

Jusçanio Umbelino de Souza
Gerente de Pesquisas Socioeconômicas

Luiz Rubens Câmara de Araújo
Assistente I

Talia Alves Xavier
Estagiária

Ingrid Stefani Rocha Quirino
Estagiária

Janemercure Oliveira de Souza
Estagiária

NÚCLEO DE PESQUISAS SOCIOECONÔMICAS – NUSOC

José Douglas de Queiroz
Chefe do núcleo

Danilo Camargos
Supervisor

Erivaldo da Fonseca Barbosa
Supervisor

Regina Célia Alves
Supervisora

Alfredo Caetano Valadão Neto
Pesquisador

Ana Lídia de C. Borges Valadão
Pesquisadora

Antônio Humberto F. de Souza
Pesquisador

Antônio Pereira de A. Filho
Pesquisador

Dwahyny Krieger K. de Oliveira
Pesquisador

Eder Tolentino da Silva
Pesquisador

Eline Sousa Lima
Pesquisador

Gean Dores Silveira Araújo
Pesquisador

Gilberto Coelho Borges
Pesquisador

Gilberto Luna dos Santos
Pesquisador

Guiomar Ribeiro de Araújo Silva
Pesquisador

Jacira Roberto dos Santos
Pesquisadora

Josias Laurentino de Sousa
Pesquisador

Lucienny Santos Guimarães
Pesquisadora

Lucimar Batista Pereira
Pesquisadora

Luiz Ricardo Jeanz
Pesquisador

Magda Maria dos Santos
Pesquisadora

Márcia da Silva
Pesquisadora

Marcos Maciel Ribeiro
Pesquisador

Maria de Lourdes de Jesus Silva
Pesquisadora

Paulo Henrique de Paiva
Pesquisador

Rosália Maria Costa Souza
Pesquisadora

Tereza Christina do Amaral
Pesquisadora

Léia Oliveira de Lima
Apoio

Maria Edna P. Medeiros
Apoio

Paulo Rogério Azevedo Andrade
Apoio

Telma Maria de Lima
Apoio

Wallas Amancio Alves
Apoio

GERÊNCIA DE CIÊNCIA DE DADOS, GEOINFORMAÇÃO, DEMOGRAFIA E ESTATÍSTICA – GEGED

Letícia Pacheco dos Passos Claro
Gerente de Ciencia de Dados, Geoinformação, Demografia e Estatística (GEGED) – A partir de abril/2022

Alexandre Silva dos Santos
Gerente da GEDEG (até setembro/2021)

Tais Alves de Oliveira
Assistente I

Elias Mangueira Lopes
Assistente I

Jeferson Lucas Macêdo do Amaral
Assistente I

Lucas Cardoso Cherigath
Assistente I

NÚCLEO DE ESTATÍSTICA – NUEST

Miriam Francisca Silva Chaves Ferreira
Estatística

Frederico Lara de Souza
Estatístico

Alessandra Analu Moreira da Silva
Estatística

Artur Carvalho de Medeiros
Estagiário

Carlo Alesandr Rosano de Almeida
Estagiário

NÚCLEO DE GEOINFORMAÇÃO – NUGEO

Patrícia Pereira Alves da Silva
Assistente I

DIRETORIA DE ESTUDOS E POLÍTICAS SOCIAIS – DIPOS

Daienne Amaral Machado
Diretora

Diego Rodrigues de Loiola
Estagiário

GERÊNCIA DE PESQUISA E ESTUDOS QUANTITATIVOS DE POLÍTICAS SOCIAIS – GEPAQ

Julia Modesto Pinheiro Dias Pereira
Gerente

Francisca de Fátima de Araújo Lucena
Pesquisadora

Acsa Rodrigues Ferreira Guimarães
Pesquisadora

GERÊNCIA DE PESQUISA E ESTUDOS QUALITATIVOS DE POLÍTICAS SOCIAIS – GEAQL

Elisete Rodrigues de Souza
Pesquisadora

NÚCLEO DE ESTUDOS DE POPULAÇÃO – NEP

Mônica Oliveira Marques França
Chefe do núcleo

DIRETORIA DE ESTUDOS URBANOS E AMBIENTAIS – DEURA

Renata Florentino de Faria Santos
Diretora

GERÊNCIA DE ESTUDOS AMBIENTAIS – GEAM

Kassia Castro
Gerente

GERÊNCIA DE ESTUDOS URBANOS, REGIONAIS E METROPOLITANOS – GEURB

Cecília de Faria Sampaio
Gerente

Alda Dutra Duarte Weigand
Assistente

Clara Wanderley Gonçalves
Estagiária

Gleicilene dos Santos Martins
Estagiária

Coleta de dados
VR consultoria

Checagem de dados
Ágora Pesquisa

Editoração Eletrônica
DIEPS

codeplan
COMPANHIA DE PLANEJAMENTO DO DISTRITO FEDERAL

Sumário

APRESENTAÇÃO **1**

1 INTRODUÇÃO **3**

2 METODOLOGIA **5**

2.1 Definição da área pesquisada 6
2.2 A amostra 8
2.3 Caracterização da Unidade de Planejamento Territorial (UPT) Central Adjacente 1 12
2.4 Breve histórico e características da RA Lago Sul 13

3 RESULTADOS – MORADORES **16**

3.1 Caracterização da população urbana 16
3.2 Migração 22
3.3 Saúde 25
3.4 Comunicação 31
3.5 Escolaridade 36
3.6 Trabalho 45
3.7 Rendimento 55

4 RESULTADOS – DOMICÍLIOS **60**

4.1 Características dos domicílios 60
4.2 Infraestrutura domiciliar 63
4.3 Infraestrutura urbana nas proximidades dos domicílios 70
4.4 Serviços domiciliares e inventário de bens duráveis 74
4.5 Localidades predominantes de compras 80
4.6 Animais de estimação 82
4.7 Segurança alimentar 83

5 CONSIDERAÇÕES FINAIS **85**

ANEXOS **86**

Tabelas relacionadas aos moradores 86
Tabelas relacionadas aos domicílios 110

Lista de Figuras

2.1.1 Região de interesse da PDAD 2021 7
2.3.1 Unidades de Planejamento Territorial com destaque para as RA que compõem a UPT Central Adjacente 1 12
2.4.1 Área de cobertura do Lago Sul na PDAD 2021 15
3.1.1 Distribuição da população por faixas de idade e sexo, Lago Sul, 2021 16
3.1.2 Distribuição da população por arranjos domiciliares, Lago Sul, 2021 17
3.1.3 Distribuição da população por sexo, Lago Sul, 2021 17
3.1.4 Identidade de gênero e orientação sexual das pessoas com 18 anos ou mais, Lago Sul, 2021 19
3.1.5 Distribuição da população por raça/cor da pele, Lago Sul, 2021 20
3.1.6 Distribuição da população por estado civil (14 anos ou mais), Lago Sul, 2021 21
3.1.7 Pessoas com 18 anos ou mais que possuíam CNH, Lago Sul, 2021 21
3.2.1 Principais estados de nascimento das pessoas que vieram de fora do DF, Lago Sul, 2021 22
3.2.2 Distribuição da motivação do responsável do domicílio a mudar e/ou retornar à capital federal, Lago Sul, 2021 23
3.2.3 Intenção e localidade para constituição de novo domicílio nos próximos 12 meses das pessoas de 14 anos ou mais, Lago Sul, 2021 24
3.3.1 Distribuição da população segundo grau de dificuldade para enxergar, ouvir, caminhar ou subir degraus, limitação nas funções mentais ou dificuldade para pegar pequenos objetos, Lago Sul, 2021 26
3.3.2 Distribuição das pessoas com plano de saúde, por tipo de cobertura, Lago Sul, 2021 27
3.3.3 Último serviço de saúde utilizado, Lago Sul, 2021 28
3.3.4 Motivo do atendimento de saúde, Lago Sul, 2021 29
3.3.5 Localidade de atendimento do último serviço de saúde utilizado, Lago Sul, 2021 30
3.4.1 Posse de celular e tablet para uso pessoal, Lago Sul, 2021 . . . 31
3.4.2 Posse de linha pré-paga e pós-paga para uso pessoal, Lago Sul, 2021 32

3.4.3 Acesso à internet e meios de acesso nos últimos três meses, Lago Sul, 2021 33
3.4.4 Meios de acesso nos últimos três meses, Lago Sul, 2021 34
3.4.5 Motivações do acesso à internet, Lago Sul, 2021 35
3.5.1 População com seis anos ou mais de idade que declararam saber ler e escrever, Lago Sul, 2021 36
3.5.2 Distribuição da frequência escolar da população entre 4 e 24 anos, Lago Sul, 2021 37
3.5.3 Distribuição da modalidade de ensino de todos os estudantes, Lago Sul, 2021 38
3.5.4 Distribuição do turno de estudo de todos os estudantes, Lago Sul, 2021 39
3.5.5 Distribuição da frequência escolar por faixas de idade, Lago Sul, 2021 40
3.5.6 Região Administrativa/Município da unidade de estudo, Lago Sul, 2021 41
3.5.7 Principal meio de transporte da casa até a escola de todos os estudantes, Lago Sul, 2021 42
3.5.8 Tempo de deslocamento da casa até a escola de todos os estudantes, Lago Sul, 2021 43
3.5.9 Escolaridade da população com 25 anos ou mais, Lago Sul, 2021 44
3.6.1 Taxa de participação das pessoas em idade ativa (14 anos ou mais de idade), Lago Sul, 2021 45
3.6.2 População de 18 a 29 anos por situação de trabalho e estudo, Lago Sul, 2021 46
3.6.3 Local onde as pessoas exerciam seu trabalho principal, Lago Sul, 2021 47
3.6.4 Distribuição do setor de atividade da empresa em que as pessoas exerciam seu trabalho principal, Lago Sul, 2021 48
3.6.5 Distribuição da posição na ocupação principal, Lago Sul, 2021 . 49
3.6.6 Área de atuação e modalidade de contratação dos servidores/empregados públicos, Lago Sul, 2021 50
3.6.7 Empreendedores segundo cadastro de Microempreendedores Individuais (MEI) e Cadastro Nacional de Pessoa Jurídica (CNPJ), Lago Sul, 2021 51
3.6.8 Meios de transporte utilizados para deslocamento até o trabalho principal, Lago Sul, 2021 52

3.6.9 Tempo para deslocamento até o trabalho principal, Lago Sul, 2021 53
3.6.10 Distribuição dos assalariados privados segundo posse de carteira de trabalho assinada (CTPS) e contribuição ao INSS, Lago Sul, 2021 54
3.7.1 Distribuição do rendimento bruto do trabalho principal por faixas de salário mínimo, Lago Sul, 2021 56
3.7.2 Curva de Lorenz do rendimento bruto do trabalho principal, Lago Sul, 2021 57
3.7.3 Distribuição do rendimento domiciliar por faixas de salário mínimo, Lago Sul, 2021 58
3.7.4 Curva de Lorenz do rendimento domiciliar, Lago Sul, 2021 . . . 59
4.1.1 Distribuição dos domicílios ocupados segundo a espécie, Lago Sul, 2021 60
4.1.2 Distribuição dos domicílios ocupados segundo o tipo, Lago Sul, 2021 61
4.1.3 Distribuição dos domicílios ocupados e próprios segundo a condição de ocupação, Lago Sul, 2021 62
4.1.4 Distribuição dos domicílios ocupados segundo a regularização do lote, Lago Sul, 2021 62
4.2.1 Distribuição dos domicílios ocupados segundo material predominante nas paredes externas, Lago Sul, 2021 63
4.2.2 Distribuição dos domicílios ocupados segundo material predominante no piso, Lago Sul, 2021 64
4.2.3 Distribuição dos domicílios ocupados segundo material predominante na cobertura (telhado), Lago Sul, 2021 65
4.2.4 Abastecimento de água no domicílio, Lago Sul, 2021 66
4.2.5 Esgotamento sanitário do domicílio, Lago Sul, 2021 67
4.2.6 Abastecimento de energia elétrica no domicílio, Lago Sul, 2021 68
4.2.7 Recolhimento do lixo no domicílio, Lago Sul, 2021 69
4.3.1 Infraestrutura urbana na rua de acesso dos domicílios, Lago Sul, 2021 70
4.3.2 Problemas nas cercanias do domicílio, Lago Sul, 2021 71
4.3.3 Infraestrutura urbana nas cercanias do domicílio, Lago Sul, 2021 72
4.3.4 Segurança nas proximidades do domicílio, Lago Sul, 2021 . . . 73
4.4.1 Contratação de serviços pelos domicílios, Lago Sul, 2021 74
4.4.2 Modalidades de acesso à internet no domicílio, Lago Sul, 2021 75

4.4.3 Posse de veículos no domicílio, Lago Sul, 2021 76
4.4.4 Inventário de bens duráveis dos domicílios, Lago Sul, 2021 . . . 77
4.4.5 Inventário de bens duráveis dos domicílios (Continuação), Lago Sul, 2021 78
4.4.6 Utilização de serviços domésticos nos domicílios, Lago Sul, 2021 79
4.5.1 Locais predominantes de compra de artigos de alimentação, higiene e limpeza, eletrodomésticos, material de construção/manutenção e serviços em geral, Lago Sul, 2021 81
4.6.1 Existência de gatos, cachorros, aves, peixes ou outros animais domésticos no domicílio, Lago Sul, 2021 82
4.7.1 Distribuição dos domicílios por situação de segurança alimentar nos últimos 3 meses, Lago Sul, 2021 84

Lista de Tabelas

2.2.1 Amostra da PDAD 2021 por localidade 9
A.1 População por faixa etária e sexo, Lago Sul, 2021 86
A.2 Arranjos domiciliares, Lago Sul, 2021 86
A.3 População por sexo, Lago Sul, 2021 87
A.4 Identidade de gênero das pessoas com 18 anos ou mais, Lago Sul, 2021 87
A.5 Orientação sexual das pessoas com 18 anos ou mais, Lago Sul, 2021 87
A.6 População com 18 anos ou mais segundo identificação LGBTQIA+, Lago Sul, 2021 87
A.7 Pessoas com 18 anos ou mais que possuíam CNH, Lago Sul, 2021 87
A.8 População por raça/cor da pele, Lago Sul, 2021 88
A.9 Estado civil das pessoas com 14 anos ou mais de idade, Lago Sul, 2021 88
A.10 Pessoas nascidas no DF, Lago Sul, 2021 88
A.11 Estado de nascimento das pessoas que vieram de fora do DF, Lago Sul, 2021 89
A.12 Motivação do chefe do domicílio a mudar e/ou retornar para o DF, Lago Sul, 2021 90
A.13 Intenção e localidade para constituição de novo domicílio das pessoas de 14 anos ou mais, Lago Sul, 2021 90
A.14 Pessoas com dificuldade permanente de enxergar, Lago Sul, 2021 91
A.15 Pessoas com dificuldade permanente de ouvir, Lago Sul, 2021 . 91
A.16 Pessoas com dificuldade permanente de caminhar ou subir degraus, Lago Sul, 2021 91
A.17 Pessoas com deficiência mental/intelectual permanente, Lago Sul, 2021 92
A.18 Pessoas com dificuldade permanente para pegar pequenos objetos, Lago Sul, 2021 92
A.19 Pessoas com plano de saúde privado, Lago Sul, 2021 92
A.20 Tipo de plano de saúde privado, Lago Sul, 2021 92
A.21 Planos de saúde privado com coparticipação e/ou franquia, Lago Sul, 2021 93
A.22 Último serviço de saúde utilizado, Lago Sul, 2021 93

A.23 Motivo de atendimento de saúde utilizado da última vez, Lago Sul, 2021 94
A.24 Localidade do atendimento do último serviço de saúde utilizado, Lago Sul, 2021 95
A.25 Posse de celular para uso pessoal, Lago Sul, 2021 96
A.26 Posse de tablet para uso pessoal, Lago Sul, 2021 96
A.27 Posse de linha pré-paga uso pessoal, Lago Sul, 2021 96
A.28 Posse de linha pós-paga uso pessoal, Lago Sul, 2021 96
A.29 Acesso à internet nos últimos três meses, Lago Sul, 2021 97
A.30 Frequência de acesso à internet nos últimos três meses, Lago Sul, 2021 97
A.31 Acesso à internet por meio de microcomputador/laptop, Lago Sul, 2021 97
A.32 Acesso à internet por meio de celular/tablet, Lago Sul, 2021 . . 97
A.33 Acesso à internet por outro meio, Lago Sul, 2021 98
A.34 Acesso à internet por motivo de trabalhar (pessoas com 14 anos ou mais), Lago Sul, 2021 98
A.35 Acesso à internet por motivo de educação/cursos, Lago Sul, 2021 98
A.36 Acesso à internet por motivo de informações/notícias, Lago Sul, 2021 98
A.37 Acesso à internet por motivo de criação/compartilhamento de conteúdo, Lago Sul, 2021 98
A.38 Acesso à internet por motivo de multimídia (lazer e cultura), Lago Sul, 2021 99
A.39 Acesso à internet por motivo de comunicação, Lago Sul, 2021 . 99
A.40 Acesso à internet por motivo de transações financeiras/comerciais, Lago Sul, 2021 99
A.41 Pessoas com cinco anos ou mais que sabem ler e escrever, Lago Sul, 2021 100
A.42 Frequência escolar da população entre 4 e 24 anos, Lago Sul, 2021 100
A.43 Modalidade de ensino dos estudantes, Lago Sul, 2021 100
A.44 Turno de estudo dos alunos, Lago Sul, 2021 101
A.45 Frequência escolar, por faixa de idade, Lago Sul, , 2021 101
A.46 Região Administrativa/Município da unidade de estudo, Lago Sul, 2021 101
A.47 Principal meio de transporte da casa até a unidade de ensino, Lago Sul, 2021 102

A.48 Tempo de deslocamento utilizado até a unidade de ensino, Lago Sul, 2021 102
A.49 Escolaridade das pessoas com 25 anos ou mais de idade, Lago Sul, 2021 102
A.50 Distribuição da população em idade ativa (PIA - 14 anos ou mais), segundo situação de atividade, Lago Sul, 2021 103
A.51 Distribuição da população economicamente ativa (PEA - 14 anos ou mais), segundo situação de ocupação, Lago Sul, 2021 . 103
A.52 Distribuição da população economicamente ativa (PEA - 14 anos ou mais), segundo situação de ocupação, Lago Sul, 2021 . 103
A.53 Pessoas entre 18 e 29 anos por situação de trabalho e estudo, Lago Sul, 2021 103
A.54 Pessoas entre 18 e 29 anos por situação de trabalho, estudo e procura por trabalho nos últimos 30 dias, Lago Sul, 2021 104
A.67 Rendimento bruto do trabalho principal em faixas de salário mínimo, Lago Sul, 2021 104
A.55 Região Administrativa de exercício do trabalho principal, Lago Sul, 2021 105
A.56 Setor de atividade das pessoas ocupadas, Lago Sul, 2021 106
A.57 Posição na ocupação do trabalho principal, Lago Sul, 2021 . . . 106
A.58 Área de atuação dos servidores/empregados públicos, Lago Sul, 2021 106
A.59 Modalidade de contratação dos servidores/empregados públicos, Lago Sul, 2021 107
A.60 Sócios de cooperativas, autônomos, empregadores, donos de negócios familiares e profissionais liberais que eram Microempreendedores Individuais (MEI), Lago Sul, 2021 107
A.61 Sócios de cooperativas, autônomos, empregadores, donos de negócios familiares e profissionais liberais que possuíam CNPJ, Lago Sul, 2021 107
A.62 Meios de transporte para o trabalho principal, Lago Sul, 2021 . . 108
A.63 Principal meio de transporte utilizado para o trabalho principal, Lago Sul, 2021 108
A.64 Tempo de deslocamento até o trabalho principal, Lago Sul, 2021108
A.65 Pessoas com carteira de trabalho assinada pelo atual empregador no trabalho principal, Lago Sul, 2021 109

A.66 Pessoas que contribuem com a previdência pública, Lago Sul, 2021 109
A.68 Rendimento bruto domiciliar por faixas de salário mínimo, Lago Sul, 2021 109
A.69 Domicílios ocupados segundo a espécie, Lago Sul, 2021 110
A.70 Domicílios ocupados segundo o tipo, Lago Sul, 2021 110
A.71 Domicílios ocupados segundo a situação de ocupação, Lago Sul, 2021 110
A.72 Domicílios ocupados segundo regularização do lote, Lago Sul, 111
A.73 Material predominante nas paredes externas do domicílio, Lago Sul, 2021 111
A.74 Material predominante no piso do domicílio, Lago Sul, 2021 . . 111
A.75 Material predominante na cobertura (telhado) do domicílio, Lago Sul, 2021 111
A.76 Abastecimento de água no domicílio, Lago Sul, 2021 112
A.77 Esgotamento sanitário do domicílio, Lago Sul, 2021 112
A.78 Abastecimento de energia elétrica no domicílio, Lago Sul, 2021 112
A.79 Recolhimento do lixo no domicílio, Lago Sul, 2021 113
A.80 Infraestrutura urbana na rua de acesso dos domicílios, Lago Sul, 2021 113
A.81 Qualidade da calçada, Lago Sul, 2021 113
A.82 Problemas nas cercanias do domicílio, Lago Sul, 2021 114
A.83 Infraestrutura urbana e equipamentos públicos nas cercanias do domicílio, Lago Sul, 2021 114
A.84 Segurança nas proximidades do domicílio, Lago Sul, 2021 . . . 114
A.85 Contratação de serviços pelos domicílios, Lago Sul, 2021 115
A.86 Acesso à internet no domicílio, Lago Sul, 2021 115
A.87 Tipo de acesso à internet no domicílio, Lago Sul, 2021 115
A.88 Posse de veículos no domicílio, Lago Sul, 2021 115
A.89 Inventário de bens duráveis dos domicílios, Lago Sul, 2021 . . . 116
A.90 Utilização de serviços domésticos nos domicílios, Lago Sul, 2021 116
A.91 Frequência mensal da utilização de serviço doméstico do tipo diarista, Lago Sul, 2021 117
A.92 Locais predominantes de compra de artigos de alimentação, higiene e limpeza, Lago Sul, 2021 118
A.93 Locais predominantes de compra de artigos de eletrodomésticos, Lago Sul, 2021 119

A.94 Locais predominantes de compra de material de construção/manutenção, Lago Sul, 2021 119
A.95 Locais predominantes de compra de material de serviços em geral (exceto limpeza doméstica), Lago Sul, 2021 120
A.96 Existência de gatos, cachorros, aves, peixes ou outros animais domésticos no domicílio, Lago Sul, 2021 121
A.97 Distribuição dos domicílios por situação de segurança alimentar nos últimos 3 meses, Lago Sul, 2021 122

APRESENTAÇÃO

A Companhia de Planejamento do Distrito Federal (Codeplan) realiza a Pesquisa Distrital por Amostra de Domicílios – PDAD – a cada dois anos, em conformidade com o decreto nº 39.403, de 26 de outubro de 2018[1]. A PDAD é uma das principais pesquisas da Codeplan, sendo fundamental para o planejamento e o acompanhamento de políticas públicas do Governo do Distrito Federal (GDF), pois é a única a fornecer informações representativas para cada uma das 33 Regiões Administrativas da capital federal.

A última edição da PDAD foi realizada em 2018, tendo sua atualização originalmente programada para 2020. Sua metodologia estabelece visitas presenciais aos domicílios amostrados para realização das entrevistas e coleta das informações. Entretanto, em virtude da pandemia da Covid-19, declarada pela Organização Mundial da Sáude (OMS) em março de 2020[2], uma série de restrições, necessárias ao enfrentamento da crise sanitária, impediram a realização da pesquisa, sendo esta postergada para 2021. O adiamento foi fundamental para que todos os protocolos de combate a pandemia fossem observados, permitindo, desse modo, a realização da coleta com segurança tanto para os pesquisadores quanto para população.

A PDAD 2021, como de costume, investigou aspectos demográficos, de migração, condições sociais e econômicas, situações de trabalho e renda, características do domicílio, condições de infraestrutura urbana, entre outras informações, de modo a oferecer um amplo e circunspecto diagnóstico da situação atual da nossa cidade. Sua periodicidade bianual possibilita um acompanhamento longitudinal de diversos indicadores, proporcionando uma análise das mudanças das condições de vida da população brasiliense. Esta mais recente edição da pesquisa contou com novidades no seu questionário, trazendo investigações inéditas, como identidade de gênero e orientação sexual para maiores de 18 anos, a existência de animais domésticos nos domicílios e questões relacionadas à segurança alimentar.

Outra novidade foi que, com a aprovação da Lei Complementar nº 958, de

[1] Disponível em: <http://www.sinj.df.gov.br/sinj/Norma/263191b1f8e5483180dc52c2cde50b4c/Decreto_39403_29_10_2018.html>

[2] <https://www.euro.who.int/en/health-topics/health-emergencies/coronavirus-covid-19/novel-coronavirus-2019-ncov>

20 de dezembro de 2019[3], o Distrito Federal passou a contar com os limites físicos de todas as suas 33 Regiões Administrativas (RAs), o que faz desta a primeira edição da PDAD a ser realizada com todas as poligonais definidas em Lei. Até a última edição, a legislação vigente à época dividia o território do Distrito Federal em 19 Regiões, enquanto, administrativamente, existiam 31 RAs[4]. Com isso, a PDAD 2021 ganhou, desde o seu planejamento, uma importante atualização.

Apresentaremos os resultados em 44 relatórios, sendo um para o Distrito Federal e os demais para cada uma das 43 localidades. A divulgação ocorrerá por etapas, conforme calendário definido pela Companhia, iniciando-se pelo relatório do Distrito Federal. A medida que os relatórios forem divulgados, eles serão disponibilizados no site da Codeplan (<https://www.codeplan.df.gov.br/pdad>) e, ao final, os microdados e toda a documentação associada à pesquisa serão disponibilizados no mesmo local. Esperamos que a PDAD contribua para o planejamento da nossa cidade e que seja amplamente utilizada pela sociedade brasiliense.

[3] Disponível em: <http://www.sinj.df.gov.br/sinj/Norma/0503ee8e9efd40eca1ffd183d4b50fd0/Lei_Complementar_958_20_12_2019.html>

[4] A Codeplan, para fins de pesquisa, utilizava uma delimitação que, posteriormente, culminou nas delimitações oficiais.

1 INTRODUÇÃO

A Pesquisa Distrital por Amostra de Domicílios (PDAD) 2021 contou com uma amostra de 30.888 domicílios efetivamente entrevistados, localizados majoritariamente em áreas urbanas do Distrito Federal, além de áreas rurais com características de interesse da Codeplan (em geral, áreas urbanizadas e com maior densidade populacional). A coleta dos dados ocorreu entre os dias 5 de maio e 22 de dezembro de 2021, tendo uma duração aproximada de sete meses e meio.

Com a PDAD, é possível traçar o perfil socioeconômico a população-alvo das 33 Regiões Administrativas do Distrito Federal, incluindo condições de moradia e acesso à infraestrutura urbana. Para algumas regiões, como Plano Piloto, Taguatinga, Planaltina, São Sebastião, SCIA/Estrutural, Jardim Botânico e Vicente Pires, informações para recortes territoriais ainda mais específicos estão disponíveis.

O desenvolvimento da PDAD envolve diversas etapas, que podem ser dividas em três categorias: pré-campo, campo e pós-campo. Todas as etapas da PDAD são submetidas ao Conselho Consultivo da PDAD, tendo sua execução companhada pelos conselheiros[5]. As atividades pré-campo envolvem as etapas de planejamento da pesquisa, que se inicia com a atualização dos cadastros de endereçamento dos domicílios, a definição da área de abrangência e o dimensionamento da amostra. Ainda nesta fase, elabora-se o questionário, sendo este amplamente discutido pelas áreas finalísticas da Codeplan e secretarias do GDF, concomitante à confecção do manual da pesquisa. Com o cronograma de campo definido, efetua-se a contratação do serviço de coleta a qual, na edição de 2021, foi realizada pela empresa VR Cosultoria – Gestão Empresarial. No que tange às atividades de campo, realiza-se o pré-teste do questionário e as últimas validações do coletor eletrônico, para, então, executar uma pesquisa piloto. Todas as informações da pesquisa piloto são analisadas, os ajustes necessários são efetuados para, enfim, iniciar a coleta que efetivamente fará parte da pesquisa. Durante a fase de coleta, a Codeplan contratou uma empresa – Ágora Pesquisa – para checar cerca de 25% da amostra coletada, tendo como intenção assegurar a qualidade das informações pesquisadas. Finalmente, na fase pós-coleta, são realizadas as

[5] A portaria que institui o Conselho Consultivo da PDAD está disponível em: <https://www.dodf.df.gov.br/index/visualizar-arquivo/?pasta=2020/06_Junho/DODF%20120%2029-06-2020&arquivo=DODF%20120%2029-06-2020%20INTEGRA.pdf>

últimas analises de consistência e formatação do banco de dados, a expansão da amostra e a elaboração dos relatórios de resultados. Para 2021, a PDAD contabilizou 3.010.881 moradores e 963.812 domicílios no Distrito Federal.

Este relatório, além desta introdução, conta com uma seção de metodologia e uma ampla seção de resultados, dividida em dois conjuntos de informações. O primeiro conjunto abordará as características demográficas da população, de migração, comunicação, saúde, educação, trabalho e rendimento. Já o segundo conjunto abordará as características domiciliares, com informações sobre a infraestrutura dos domicílios e em suas proximidades, os serviços domiciliares e o inventário de bens, os locais predominantes de compras, a existência de animais domésticos e situações de insegurança alimentar. Por fim, a última seção apresentará as considerações finais, enquanto, nos anexos, serão disponibilizadas todas as tabulações.

2 METODOLOGIA

Nesta seção, são apresentados os principais aspectos metodológicos que envolveram a realização da PDAD 2021. Todas as atividades de coordenação geral da pesquisa, planejamento, análise de consistência, expansão dos resultados e elaboração das análises, incluindo este relatório, foram realizadas pela equipe da Codeplan. Já o trabalho de campo foi conduzido por empresas especializadas, contratadas pela Codeplan para esta finalidade.

A unidade elementar de interesse foi o domicílio particular situado em área urbana ou em área rural com características urbanas, além de algumas áreas de interesse da Codeplan. Em cada domicílio visitado, foram coletadas informações de todos os moradores, gerando dois conjuntos de informações: o primeiro relacionado às características dos domicílios; o segundo relacionado aos moradores.

A coleta dos dados foi realizada entre maio e dezembro de 2021, com as entrevistas sendo efetuadas todos os dias da semana, entre 07:00 e 20:00 horas, por meio de coletor eletrônico. Esta atividade de campo foi conduzida pela empresa VR consultoria[6]. Foram realizadas, pelo menos, três tentativas de visitas em dias em horários distintos. Havendo recusa, foram disponibilizadas duas listas de substituições dos domicílios, seguindo esta mesma metodologia de visitas. Visando a garantir a qualidade dos dados, 25% das informações coletadas passaram por um processo de checagem, realizado pela empresa Ágora Pesquisa[7]. Além disso, checagens adicionais de campo foram realizadas pela equipe interna da Codeplan. A data de referência da pesquisa é 1º de julho de 2021.

No restante desta seção, são apresentados os detalhes da definição da área pesquisada e da definição da amostra.

[6] <https://promaxima.com.br/>
[7] <https://www.agorapesquisa.com/>

2.1 Definição da área pesquisada

A PDAD é uma pesquisa amostral que visa a fornecer informações representativas para todas as Regiões Administrativas do Distrito Federal. Na elaboração de planos amostrais para pesquisas domiciliares, a definição dos limites de áreas estudadas torna-se um requisito necessário, pois as inferências realizadas devem ter definidas as áreas de referência. Até a última edição da PDAD, em 2018, tais definições não existiam para todas as regiões presentes na legislação local[8].

Com a aprovação da Lei Complementar nº 958, de 20 de dezembro de 2019[9], atualmente, todas as 33 poligonais estão definidas oficialmente. Em virtude disso, o desenho do plano amostral apresentou algumas modificações daquele observado na PDAD de 2018, contando com alteração em algumas áreas quanto às delimitações das Regiões Administrativas e de algumas localidades de interesse estudadas. Por exemplo, o Jardim Mangueiral, que antes pertencia à RA São Sebastião, passou a pertencer à RA Jardim Botânico. A área de cobertura da PDAD 2021 é apresentada na Figura 2.1.1.

Para o plano amostral da PDAD 2021, foi considerado como universo (sistema de referência) os domicílios do conjunto de setores censitários domiciliares urbano, rural com características urbanas ou de áreas de interesse da Codeplan. Tais domicílios compuseram a lista de localidades definidas como área de cobertura da PDAD 2021, sendo preservados os limites geográficos dos setores censitários, que compreende a menor unidade geográfica para a qual o IBGE publica dados e com a qual ele operacionaliza suas atividades de coleta de dados domiciliares[10].

[8] Quando a PDAD 2018 foi realizada, existiam no DF 31 Regiões Administrativas criadas em Lei, todavia apenas 19 delas apresentavam suas poligonais definidas. Por esta razão, e para fins de pesquisa, a Codeplan definiu uma delimitação provisória, que foi utilizada até então.

[9] Disponível em: <http://www.sinj.df.gov.br/sinj/Norma/0503ee8e9efd40eca1ffd183d4b50fd0/Lei_Complementar_958_20_12_2019.html>

[10] Considerou-se a malha preliminar de 2019 do IBGE.

Figura 2.1.1: Região de interesse da PDAD 2021

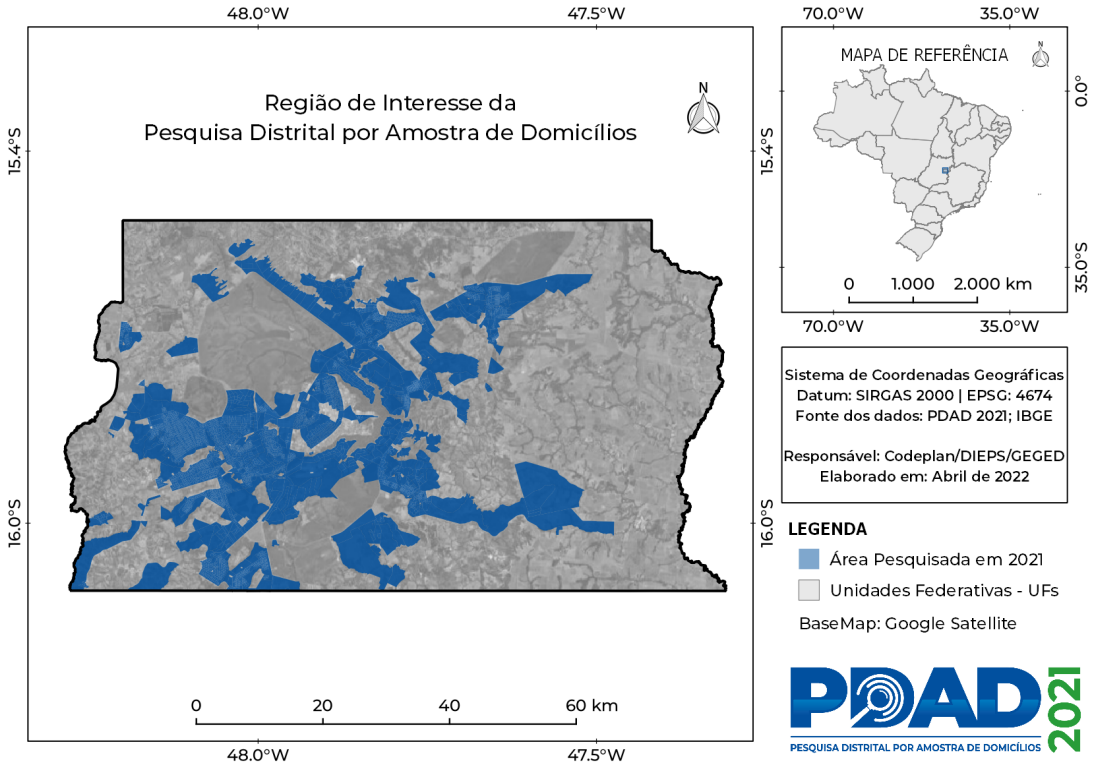

2.2 A amostra

A seleção da amostra seguiu o esquema de amostragem aleatória sistemática para as 33 regiões administrativas do Distrito Federal e as localidades de interesse estabelecidas pela CODEPLAN (totalizando 43).

Para a definição do tamanho das amostras, utilizou-se como parâmetro estatístico a variância da renda domiciliar. Tal parâmetro serviu de balizador na partição da amostra total, de 35.556 domicílios, seguindo o modelo da repartição de Neyman. Quanto maior a variância da renda domiciliar, maior foi a amostra da localidade, sendo utilizado os dados de renda da PDAD 2018.

No intuito de garantir robustez nas amostras, foi definido o menor tamanho amostral (n) de 440 domicílios por localidade, mesmo que a fórmula estatística indicasse uma amostra suficiente menor. Foi prevista uma margem de perda em torno de 16%, de forma que, não ocorrendo 100% da amostra sorteada para uma determinada localidade, os resultados não seriam comprometidos estatisticamente[11].

A base de endereços foi construída utilizando-se o cadastro de programas habitacionais, o cadastro de consumidores de energia elétrica, o cadastro de consumidores de água, cadastros do DF Legal[12] e cadastros de geolocalização elaborados pela Codeplan, todos contendo as variáveis de localização, o que possibilitou agregar, conforme a Região Administrativa, os endereços contidos nos 4.199 setores censitários abrangidos pela pesquisa[13]. Foram utilizadas imagens de satélite para detectar aglomerados subnormais com características urbanas ainda não incluídos nos cadastros disponíveis, para os quais a CODEPLAN providenciou listagens para, assim, dispor de todos os endereços nas 43 localidades abrangidas pela pesquisa. Como exemplo, cita-se a localidade Santa Luzia, situada na RA SCIA-Estrutural. O universo de endereços residenciais urbanos contemplou 899.864 unidades domiciliares aparentemente ocupadas. Foram definidas 43 localidades (ou estratos) de interesse, apresentados na Tabela 2.2.1.

[11] Até o limite desta perda.

[12] Todos os cadastros foram gentilmente compartilhados pela Companhia de Desenvolvimento Habitacional do Distrito Federal – CODHAB, pela então Companhia Energética de Brasília – CEB, pela Companhia de Saneamento Ambiental do Distrito Federal – CAESB e pela Secretaria de Estado De Proteção da Ordem Urbanística do Distrito Federal – DF LEGAL, respectivamente.

[13] Conforme malha censitária parcial do IBGE de 2019.

Tabela 2.2.1: Amostra da PDAD 2021 por localidade

Localidade	Amostra	Localidade	Amostra
Águas Claras	1.808	Plano Piloto - Noroeste	1.387
Arniqueira	630	Recanto das Emas	654
Brazlândia	582	Riacho Fundo	594
Candangolândia	561	Riacho Fundo II	604
Ceilândia	868	S. Sebastião - Consolidado	596
Cruzeiro	616	S. Sebastião - Morro da Cruz	550
Fercal	514	Samambaia	1.059
Gama	778	Santa Maria	696
Guará	1.220	SCIA/Estrutural - Chácara S. Luzia	512
Itapoã	585	SCIA/Estrutural - Consolidado	531
J. Botânico - Consolidado	889	SIA	530
J. Botânico - Jardim Mangueiral	679	Sobradinho	742
Lago Norte	998	Sobradinho II	753
Lago Sul	935	Sol Nasc./Pôr do Sol	600
Núcleo Bandeirante	621	Sudoeste/Octogonal	1.399
Paranoá	578	Taguatinga - Consolidado	1.198
Park Way	853	Taguatinga - S. Prim. ARINE	556
Planaltina - Arapoanga	575	Taguatinga - S. Prim. ARIS	527
Planaltina - Consolidado	710	V. Pires - 26 de Setembro	672
Plano Piloto - Asa Norte	1.936	V. Pires - Consolidado	1.356
Plano Piloto - Asa Sul	1.928	Varjão	510
Plano Piloto - Demais	666		

Fonte: CODEPLAN/DIEPS/GEGED/NUEST

O tamanho da amostra foi determinado a partir da relação:

$$n_i = n\frac{N_i Si}{\sum_{i=1}^{43} N_i S_i} \tag{1}$$

Em que n_i é o tamanho da amostra na localidade; N_i denota o número de domicílios da localidade i e S_i é a raiz quadrada da variância, para todos com i, $(i = 1, 2, 3, ..., 43)$

As estimativas dos totais e proporções foram obtidas a partir dos seguintes estimadores:

$$\hat{Y}_i = N_i \bar{y}_i \tag{2}$$

Em que $\hat{Y}_i$ é o estimador do total da localidade i e $\bar{y}_i$ é a média da amostra da localidade i.

$$\hat{p}_i = \frac{y_i}{n_i} \tag{3}$$

Em que $\hat{p}_i$ é o estimador de uma proporção da localidade i e y_i é o valor para uma característica na amostra da localidade i.

Para o Distrito Federal, os estimadores foram:

$$\bar{Y}_i = \sum_{i=1}^{43} \infty_i \hat{y}_i \tag{4}$$

e

$$\bar{p}_i = \sum_{i=1}^{43} \infty_i \hat{p}_i \tag{5}$$

Em que ∞_i é o peso da RA i obtido pela relação, sendo o inverso da fração amostral:

$$\infty_i = \frac{N_i}{n_i} \tag{6}$$

e

$$N = \sum_{i=1}^{43} N_i \tag{7}$$

Apoiados em resultados de pesquisas desse mesmo porte, com a mesma finalidade, pode-se prever um erro de 3,5%, com 95% de grau de confiança.

A fração amostral resulta da seguinte relação:

$$Fi = \frac{n_i}{N_i} \tag{8}$$

Em que n_i é o tamanho da amostra da localidade i e N_i é o número de domicílios da localidade i.

Para a expansão dos resultados, foram consideradas as projeções populacionais produzidas pela Codeplan, tendo como norte as projeções realizadas pelo Instituto Brasileiro de Geografia e Estatística – IBGE, distribuídas pelas RAs pela equipe da Diretoria de Estudos e Políticas Sociais – DIPOS, da Codeplan[14]. As informações populacionais foram pós-estratificadas por cada uma das 43 localidades territoriais, por sexo e faixas de idade[15], totalizando 1.376 pós-estratos. As informações de domicílios foram expandidas com os dados do Cadastro Nacional de Endereços para Fins Estatísticos – CNEFE, do IBGE[16].

Ao longo do texto, as barras verticais e horizontais nos gráficos denotam o intervalo de confiança das estimativas, calculadas por *bootstrap* segundo metodologia proposta por Rao e Wu (1988)[17], utilizando o pacote *survey*[18] do software R. Além disso, definiu-se um coeficiente de variação máximo de 25% para o reporte das estimativas. As estimativas que apresentaram coeficientes de variação superiores a esse limite foram omitidas do relatório, garantindo, dessa forma, que apenas informações com um parâmetro de qualidade definido fossem divulgadas. Por essa razão, nem sempre as tabelas totalizarão 100% ou os totais populacionais do domínio em análise. Além disso, foram considerados apenas as respostas válidas para as questões, excluíndo-se, portanto, os casos para os quais o morador não sabia fornecer a informação[19].

[14] Como a PDAD 2021 não abrangeu 100% do território, sua população-alvo é ligeiramente inferior à população residente, estimada em 3.091.667, ou seja, uma diferença de 80.786 pessoas. As informações completas sobre as projeções populacionais estão disponíveis em: <https://www.codeplan.df.gov.br/wp-content/uploads/2021/12/Estudo-Projecoes-populacionais-para-as-Regioes-Administrativas-do-Distrito-Federal-2020-2030-Resultados.pdf>

[15] Foram considerados quinquenios de zero até 74 anos e mais de 75 anos.

[16] Para duas localidades, 26 de setembro e Morro da Cruz, o CNEFE não refletia, no nomento da expansão, o volume de domicílios particulares da região. Assim sendo, utilizou-se como estimativa o peso do responsável pelo domicílio.

[17] Rao, J.N.K. and C.F.J. Wu. 1988. Re-Sampling Inference With Complex Survey Data. JASA, March Vol. 83 No.401 pp. 231-241.

[18] Informações sobre o pacote estão disponíveis em: T. Lumley (2020) "Survey: analysis of complex survey samples". R package version 4.0.

[19] Sendo a PDAD uma pesquisa domiciliar, preferencialmente, procura-se entrevistar todos os moradores do domicílio. Entretanto, no momento da entrevista, nem todos os moradores podem estar presentes presentes. Nestes casos, conforme a metodologia adotada pela pesquisa, é possível que um morador forneça informações sobre os demais, o que pode ocasionar situações de não respostas para determinadas questões.

2.3 Caracterização da Unidade de Planejamento Territorial (UPT) Central Adjacente 1

A política urbana brasileira é regida pelos artigos artigos 182 e 183 da Constituição Federal de 1988. A regulamentação desses artigos veio em 2001, com a Lei nº 10.257, de 10 de julho de 2001, conhecida como Estatuto da Cidade, que estabelece diretrizes gerais da política urbana. O estatuto estabelece o Plano Diretor como instrumento básico da política de desenvolvimento e expansão urbana[20].

Aqui no DF, o Plano Diretor de Ordenamento Territorial do Distrito Federal instituiu as Unidades de Planejamento Territorial – UPTs[21] (artigo 103 da Lei Complementar 803/2009) para fins de ordenamento e gestão do território do DF. O Distrito Federal foi dividido em 7 (sete) UPTs, as UPTs Norte, Sul, Leste, Oeste, Central, Central Adjacente I e Central Adjacente II (Figura 2.3.1).

Figura 2.3.1: Unidades de Planejamento Territorial com destaque para as RA que compõem a UPT Central Adjacente 1

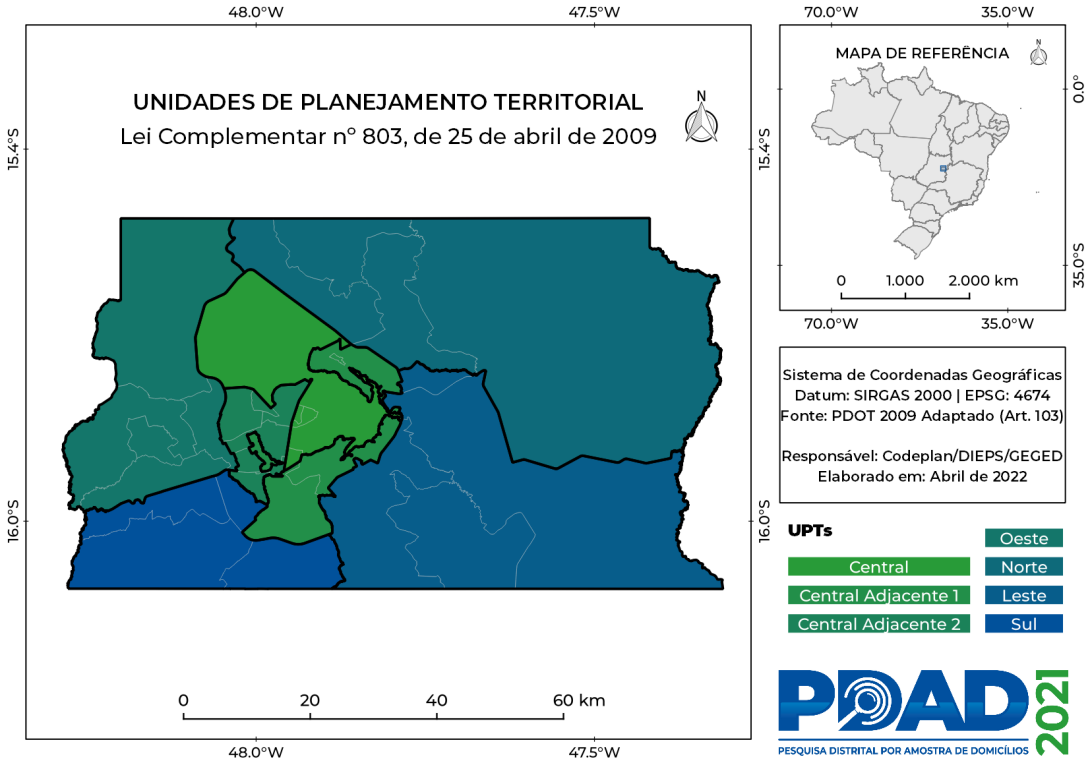

[20] BRASIL. Lei no 10.257 de 10 de julho de 2001. Disponível em: <http://www.planalto.gov.br/ccivil_03/leis/leis_2001/l10257.htm>. Acesso em: 26 abr. 2022.

[21] DISTRITO FEDERAL. Lei Complementar no 803 de 25 de abril de 2009. Disponível em: <http://www.sinj.df.gov.br/sinj/Norma/60298/Lei_Complementar_803_25_04_2009.html>. Acesso em: 26 abr. 2022.

O Estatuto da Cidade estabelece que a revisão do Plano Diretor deve ser realizada a cada 10 anos e, no DF, a Secretaria de Estado de Desenvolvimento Urbano e Habitação – SEDUH iniciou o processo de revisão em 2019, que pode ser acompanhado no Portal do PDOT[22]. Os principais aspectos da UPT Central Adjacente I e do Lago Sul são:

- A Região Administrativa – RA XVI – Lago Sul concentra 30,44% da população da UPT Central, que é formada também pelas RAs Lago Norte, Park Way e Varjão. No DF, a população da RA representa 1,01% do total;
- A população total da UPT Central Adjacente I é de 100.019 habitantes, o que representa 3,32% da população do Distrito Federal;
- A densidade demográfica do Lago Sul na área pesquisada é de 433,66 habitantes/km².

2.4 Breve histórico e características da RA Lago Sul

A Região Administrativa do Lago Sul – RA XVI – completa 62 anos no dia 30 de agosto de 2022. O território da RA ocupa uma área de 7.604,87 hectares e o abastecimento de água na RA é realizado pelo reservatório do Torto, Santa Maria, Bananal e Cabeça do Veado[23]. A Regional do Plano Piloto e Cruzeiro é responsável pelo estudantes de escolas públicas dessa RA[24].

A denominação Lago Sul originou-se da própria posição geográfica da área – margem Sul do Lago Paranoá. Foi desmembrada da RA I – Plano Piloto, continuando sujeita às diretrizes urbanísticas estabelecidas para Brasília, visto que o Lago Sul constitui um dos principais visuais do Plano Piloto, compondo o envoltório da paisagem do Conjunto Urbano Tombado, garantindo sua ambiência e compreensão[25]. O lago Sul foi sendo ocupado e preferido, para atender as residências de autoridades, devido ao tamanho dos lotes, à vista do Lago Paranoá[26].

[22] Disponível em: <http://www.pdot.seduh.df.gov.br/>

[23] CAESB. Estações de Tratamento de Água. Disponível em: <https://atlascaesb.maps.arcgis.com/apps/MapJournal/index.html?appid=4d06131962ca482a9d51502c630e195f>. Acesso em: 6 abr. 2022.

[24] SEEDF. Coordenação de Regionais de Ensino. Disponível em: <https://www.educacao.df.gov.br/coordenacoes-regionais-de-ensino/>. Acesso em: 7 abr. 2022

[25] SEDUH. Documento Técnico – Plano Diretor de Ordenamento Territorial do Distrito Federal. Disponível em: <http://www.seduh.df.gov.br/wp-conteudo/uploads/2017/09/documento_tecnico_pdot12042017.pdf>. Acesso em: 19 abr. 2022

[26] COSTA, Graciete Guerra da. As regiões administrativas do Distrito Federal de 1960 a 2011. 2011. Disponível em: <https://repositorio.unb.br/handle/10482/9987>

Durante a década de 1970 ocorreu a consolidação do Lago Sul, com o início da oferta de comércio e serviços, e a melhoria da acessibilidade ao Plano Piloto. A RA foi criada pela Lei nº 643, de 10 de janeiro de 1994, tendo sido seus limites físico-administrativos fixados pelo decreto 15.515, de 17 de março de 1994.

O Lago Sul está inserido em duas Áreas de Proteção Ambiental (APA): a APA Gama Cabeça de Veado e a APA do Lago Paranoá, abrangendo parques ecológicos e unidades de conservação, tais como: Parque Ecológico Dom Bosco, Parque Vivencial do Anfiteatro Natural do Lago Sul, Parque Ecológico Península Sul, Jardim Botânico de Brasília, Parque das Copaíbas, Parque Ecológico Bernardo Sayão, Parque Ecológico e Vivencial Canjerana e Parque Ecológico Garça Branca[27].

Localizado na beira do Lago Paranoá, perto da barragem, o Parque Ecológico Dom Bosco oferece aos seus visitantes paisagens exuberantes, além de trilhas dentro do cerrado nativo. Por possuir uma rua asfaltada bem inclinada, o local tornou-se ideal para a prática do Downhill sobre skate (descer uma ladeira andando de Skate, aproveitando toda sua extensão e largura executando manobras). Outro grande atrativo desta unidade é a Ermida Dom Bosco, tradicional monumento e ponto turístico de Brasília, que fica localizada exatamente sob o paralelo 15S, conforme o sonho do salesiano Dom Bosco, em 1883[28].

O Jardim Botânico de Brasília inclui a Estação Ecológica Jardim Botânico de Brasília (EEJBB), abriga mananciais que abastecem 25% de toda a região do Lago Sul e Jardim Botânico. São aproximadamente cinco mil hectares, dos quais 526 para visitação e 4.430 destinados à preservação e à pesquisa. A área de visitação do Jardim Botânico é composta pelo Centro de Visitantes, Centro de Excelência do Cerrado, Espaço Oribá/ Piquenique/ Parque Infantil, Orquidário, Cactário, Biblioteca, Permacultura, Anfiteatro, Trilhas Interpretativas, Alameda das Nações e dos Estados e Jardins Temáticos[29].

[27] IBRAM, Instituto Brasília Ambiental. Guia de Parques do Distrito Federal. Disponível em: <https://ibram.df.gov.br/wp-content/uploads/2018/03/GUIA-DE-PARQUES.compressed.pdf>. Acesso em: 6 abr. 2022.

[28] IBRAM, Instituto Brasília Ambiental. Guia de Parques do Distrito Federal. Disponível em: <https://ibram.df.gov.br/wp-content/uploads/2018/03/GUIA-DE-PARQUES.compressed.pdf>. Acesso em: 6 abr. 2022.

[29] JARDIM BOTÂNICO DE BRASÍLIA. Jardim Botânico de Brasília. Disponível em: <https://www.jardimbotanico.df.gov.br/>. Acesso em: 19 abr. 2022.

Em relação ao transporte público, a empresa que atende a RA é a Pioneira[30], e a principal via da RA é a Estrada Parque Dom Bosco (DF-025)[31], além dos acessos pela Estrada Parque Aeroporto – EPAR (DF-047), Estrada Parque Cabeça do Veado – EPCV (DF-035) e Estrada Parque Juscelino Kubitschek – EPJK (DF-027).

Atualmente, o Lago Sul é uma das chamadas áreas nobres do DF, conta com uma estrutura urbana consolidada, com opções de entretenimento e lazer, comércio diversificado, equipamentos de educação, saúde e segurança, além de equipamentos de abrangência regional, como o Pontão Sul, empreendimento de lazer, gastronomia e turismo[32].

O mapa de cobertura da PDAD 2021 para o Lago Sul é apresentado na Figura 2.4.1.

Figura 2.4.1: Área de cobertura do Lago Sul na PDAD 2021

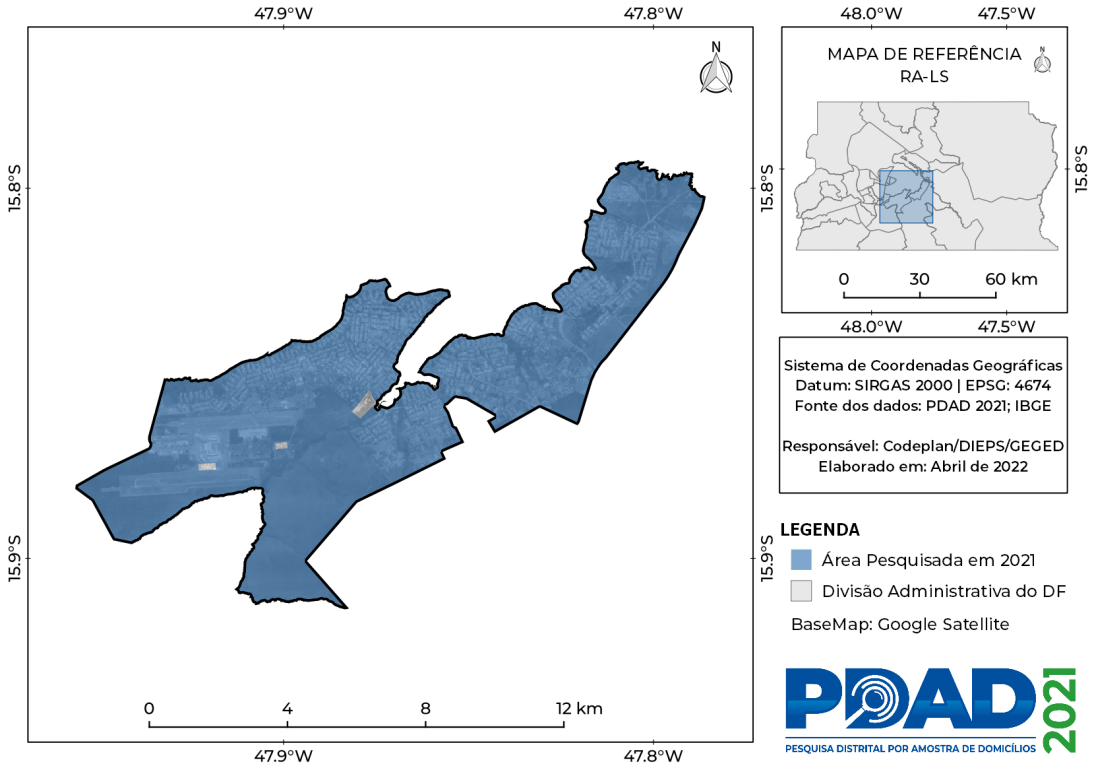

[30] SECRETARIA DE TRANSPORTE E MOBILIDADE. Dados do Sistema de Transporte Público Coletivo do Distrito Federal. Disponível em: <https://semob.df.gov.br/dados-do-sistema-de-transporte-publico-do-df/>. Acesso em: 6 abr. 2022.

[31] DER. SISTEMA RODOVIÁRIO DO DISTRITO FEDERAL, 2018. Disponível em: <https://arquivos.der.df.gov.br/downloads/SRDF_2018/Legislacao_SRDF_modificado_19_09_2018.pdf>.

[32] CODEPLAN. PDAD 2018 - Lago Sul, 2019. Disponível em: <https://www.codeplan.df.gov.br/wp-content/uploads/2020/06/Lago-Sul.pdf>.

3 RESULTADOS – MORADORES

3.1 Caracterização da população urbana

A PDAD 2021 aponta que a população urbana da RA Lago Sul era de **30.446** pessoas, sendo 51,7% do sexo de nascimento feminino (Figura 3.1.3 e Tabela A.3). A idade média era de 42,5 anos. A pirâmide etária, apresentada na Figura 3.1.1, traz a distribuição da população por faixas de idade e por sexo (Tabela A.1).

Figura 3.1.1: Distribuição da população por faixas de idade e sexo, Lago Sul, 2021

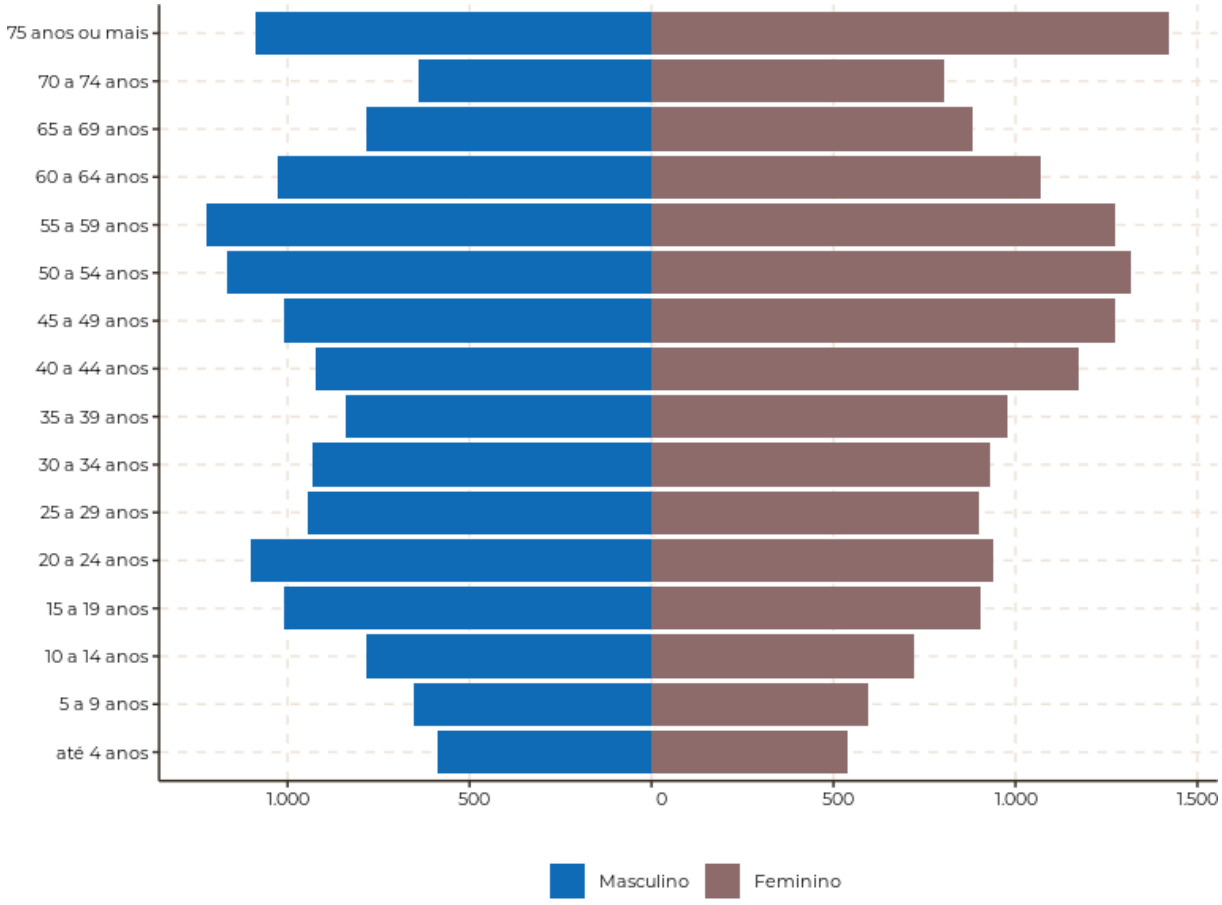

Fonte: CODEPLAN/DIEPS/GEREPS/PDAD 2021

Para entender como as pessoas estão organizadas dentro dos domicílios, foram criados os seguintes arranjos: unipessoal; monoparental feminino; casais sem filhos; casais com um filho; casais com dois filhos; casais com três ou mais filhos; e outros perfis. Para essas classificações, observou-se que o arranjo "casal com 1 filho" foi o mais observado, em 26,7% dos domicílios (Figura 3.1.2 e Tabela A.2).

Figura 3.1.2: Distribuição da população por arranjos domiciliares, Lago Sul, 2021

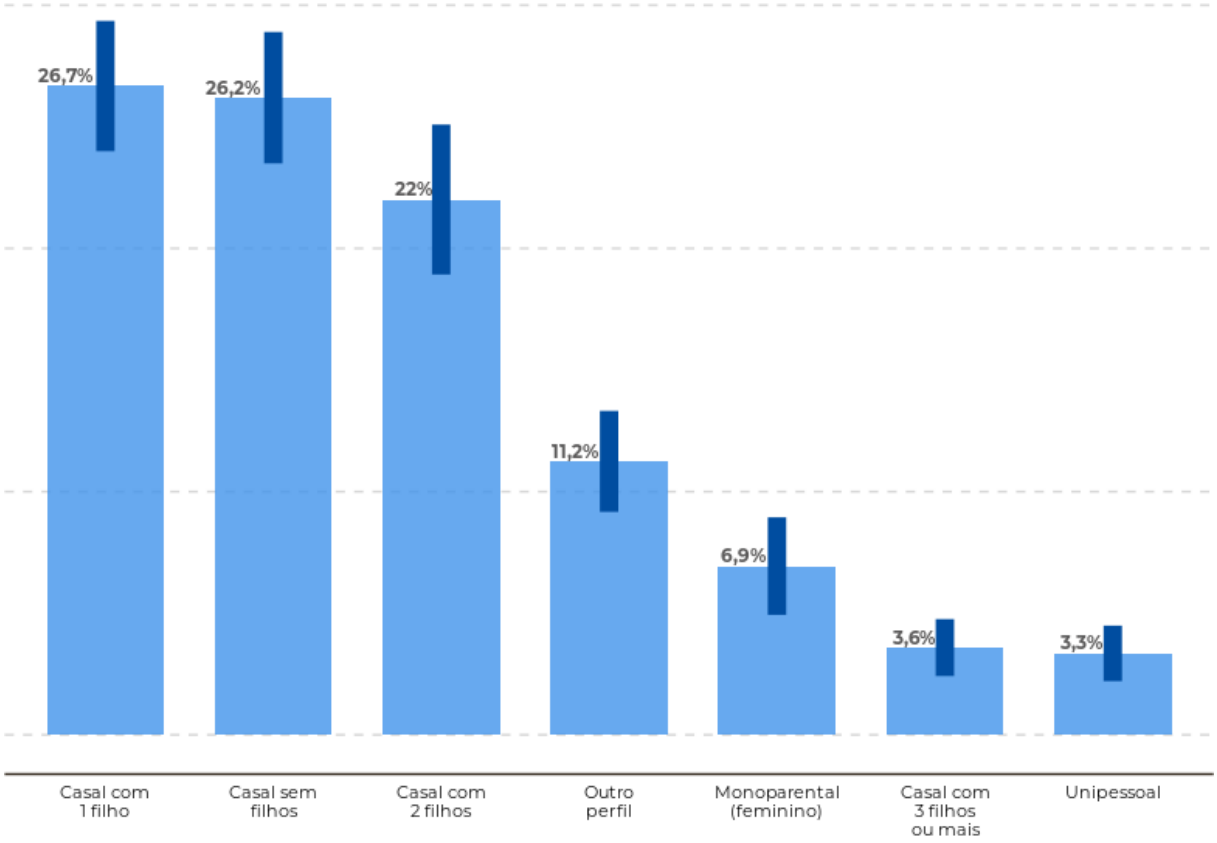

Fonte: CODEPLAN/DIEPS/GEREPS/PDAD 2021

Figura 3.1.3: Distribuição da população por sexo, Lago Sul, 2021

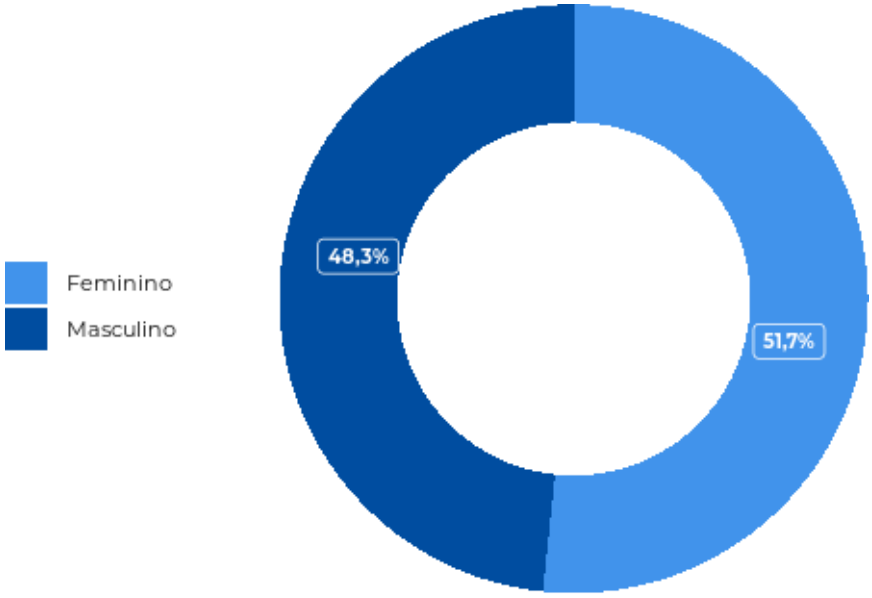

Fonte: CODEPLAN/DIEPS/GEREPS/PDAD 2021

Nesta edição, a PDAD trouxe uma inovação, com perguntas sobre identidade de gênero e sobre orientação sexual dos moradores com 18 anos ou mais de idade[33]. Quando considerado o cruzamento com a questão sobre sexo de nascimento dessas pessoas, sobre identidade de gênero, 1% dos respondentes era transgênero[34]; no que diz respeito à orientação sexual, 1,4% dos respondentes eram lésbicas, gays, bissexuais ou outros (Figura 3.1.4 e Tabelas A.4 e A.5).

Quando consideradas as pessoas LGBTQIA+[35], ou seja, pessoas transgêneros e/ou lésbicas, gays, bissexuais ou outros, verificou-se uma resposta afirmativa para 2,2% dos respondentes (Figura 3.1.4 e Tabela A.6).

No que diz respeito à raça/cor da pele, verificou-se que a resposta mais comum foi branca, para 66,8% dos moradores (Figura 3.1.5 e Tabela A.8). Sobre o estado civil, 58,1% da população com 14 anos ou mais de idade se declararam casados (Figura 3.1.6 e Tabela A.9).

Por fim, sobre a posse de carteira nacional de habilitação (CNH), 92,7% dos moradores de 18 anos ou mais de idade afirmaram ter o documento (Figura 3.1.7 e Tabela A.7).

[33] Para mais informações sobre o tema, consulte a Nota Técnica *Gênero e Orientação Sexual no DF – um olhar inclusivo*. Disponível em: <https://www.codeplan.df.gov.br/wp-content/uploads/2018/03/NT-Genero-e-Orientacao-Sexual-no-DF-um-olhar-inclusivo.pdf>

[34] Considera-se transgenero todas as pessoas que declaram ter uma identidade de gênero diferente do sexo registrado na certidão de nascimento. Esse termo engloba as pessoas: transfemininas, transmasculinas, não binárias, travestis, entre outras identificações adotadas pela população.

[35] Pessoas que se identificaram como transgêneros e também lésbicas, gays, bissexuais ou outros são consideradas apenas uma vez.

Figura 3.1.4: Identidade de gênero e orientação sexual das pessoas com 18 anos ou mais, Lago Sul, 2021

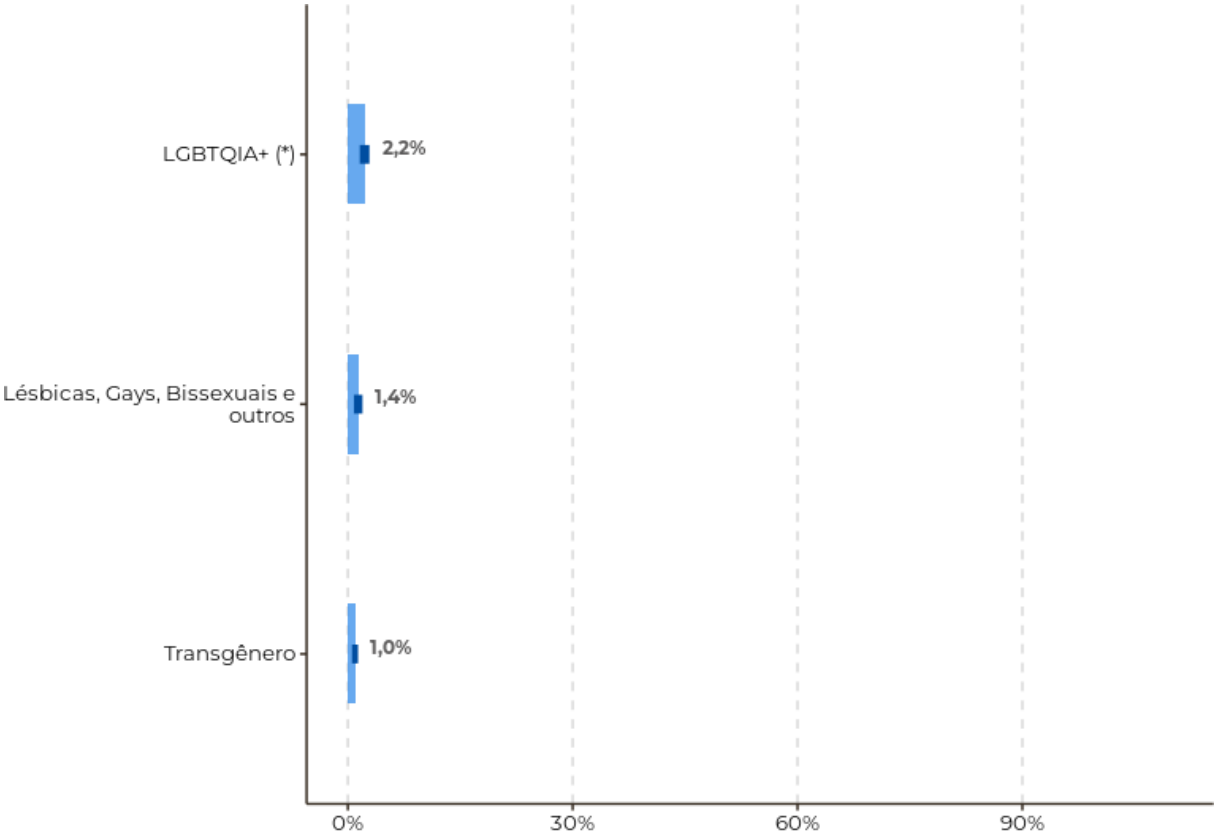

Fonte: CODEPLAN/DIEPS/GEREPS/PDAD 2021
(*) Pessoas que se identificaram como transgêneros e também lésbicas, gays, bissexuais ou outros são consideradas apenas uma vez.

Figura 3.1.5: Distribuição da população por raça/cor da pele, Lago Sul, 2021

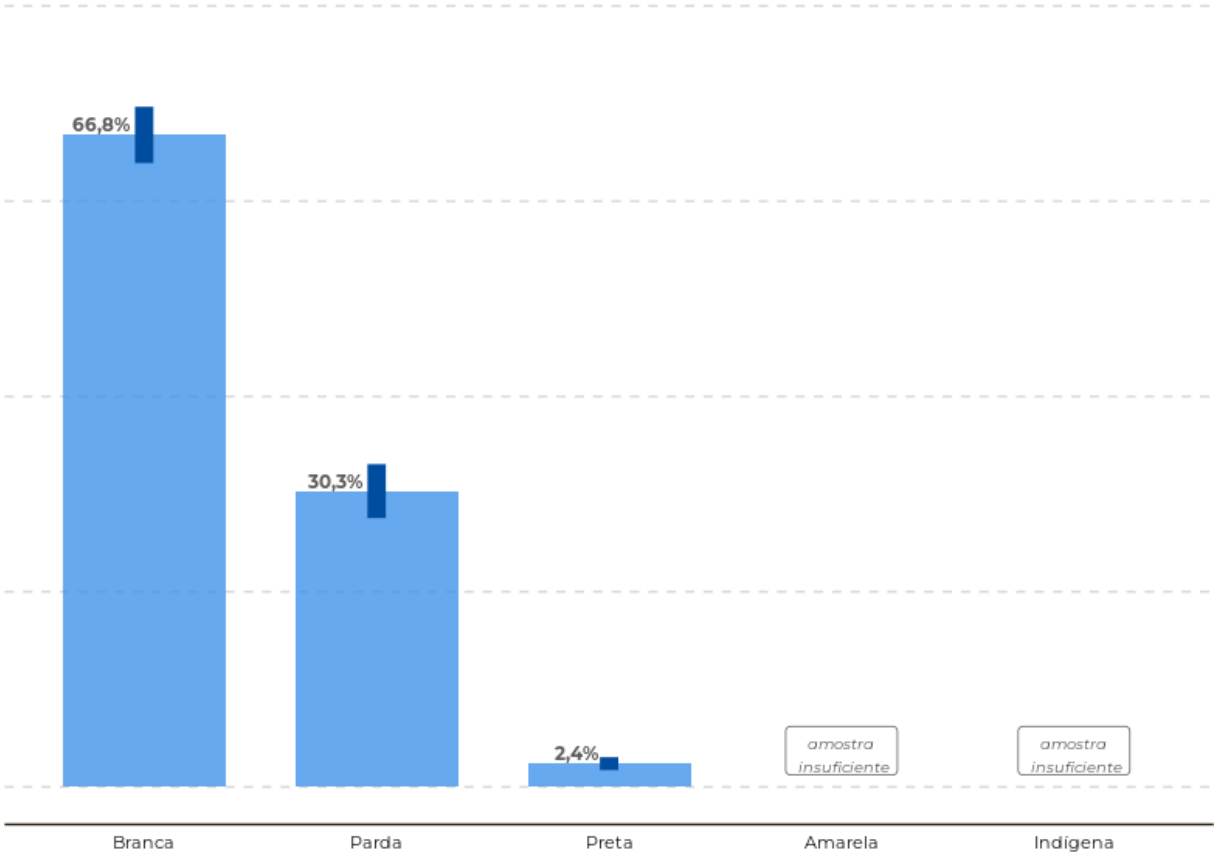

Fonte: CODEPLAN/DIEPS/GEREPS/PDAD 2021

Figura 3.1.6: Distribuição da população por estado civil (14 anos ou mais), Lago Sul, 2021

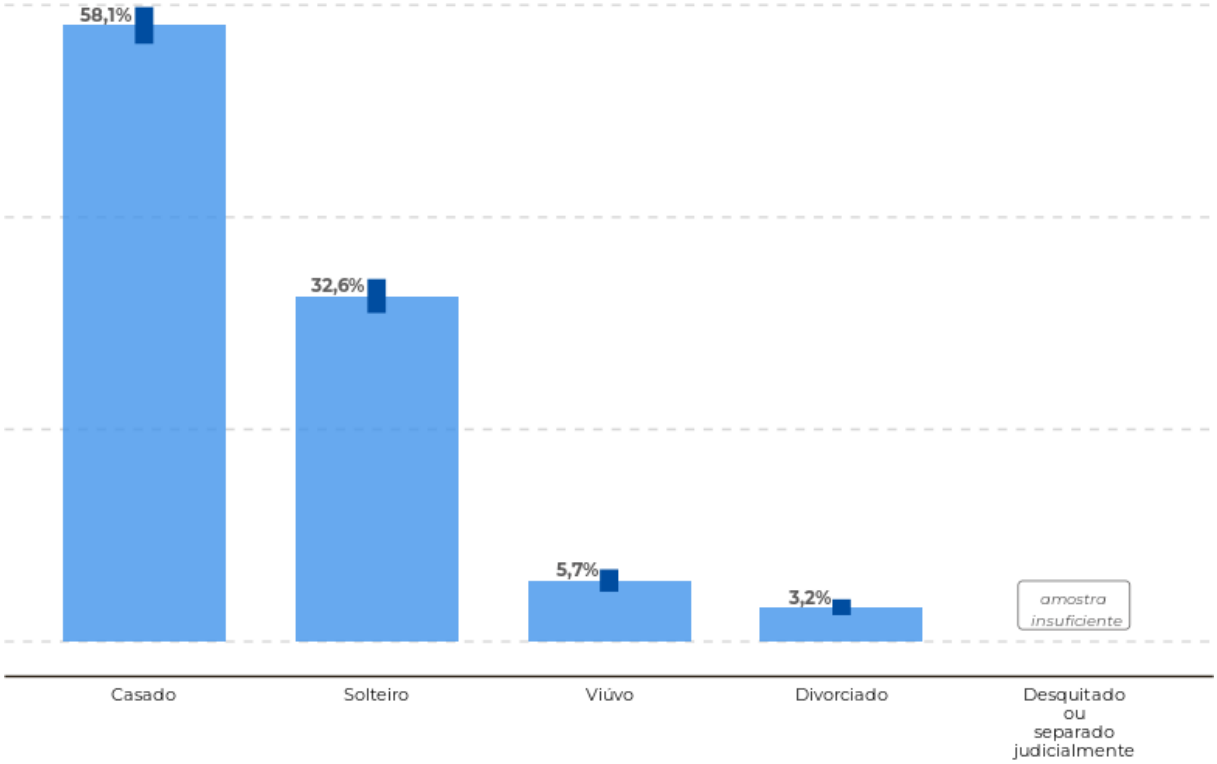

Fonte: CODEPLAN/DIEPS/GEREPS/PDAD 2021

Figura 3.1.7: Pessoas com 18 anos ou mais que possuíam CNH, Lago Sul, 2021

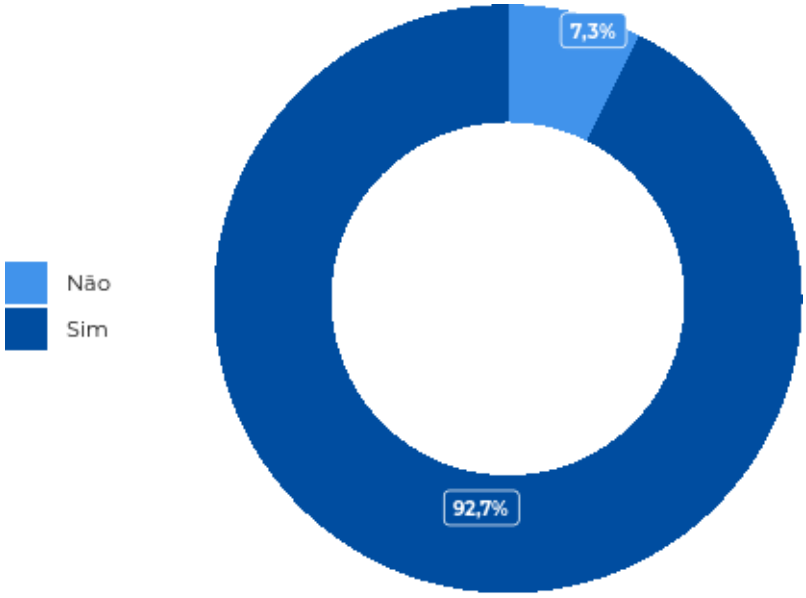

Fonte: CODEPLAN/DIEPS/GEREPS/PDAD 2021

3.2 Migração

Quanto à origem dos moradores, 53,2% informaram ter nascido fora do DF (Tabela A.10)[36]. Para os que não nasceram no DF, o estado mais reportado foi Minas Gerais, segundo 18,3% dos entrevistados (Figura 3.2.1 e Tabela A.11). Para todos os moradores do DF, o tempo médio de moradia na capital federal é de 30,3 anos, enquanto o tempo médio de moradia da RA é de 18,5 anos. Sobre aqueles que vieram para o DF ou que deixaram o território, mas retornaram posteriormente, foi questionada a motivação que os levou a fazer isso. Para 44,5% dos responsáveis dos domicílios, acompanhar parentes ou reunião familiar foi a principal razão da movimentação (Figura 3.2.2 e Tabela A.12).

Figura 3.2.1: Principais estados de nascimento das pessoas que vieram de fora do DF, Lago Sul, 2021

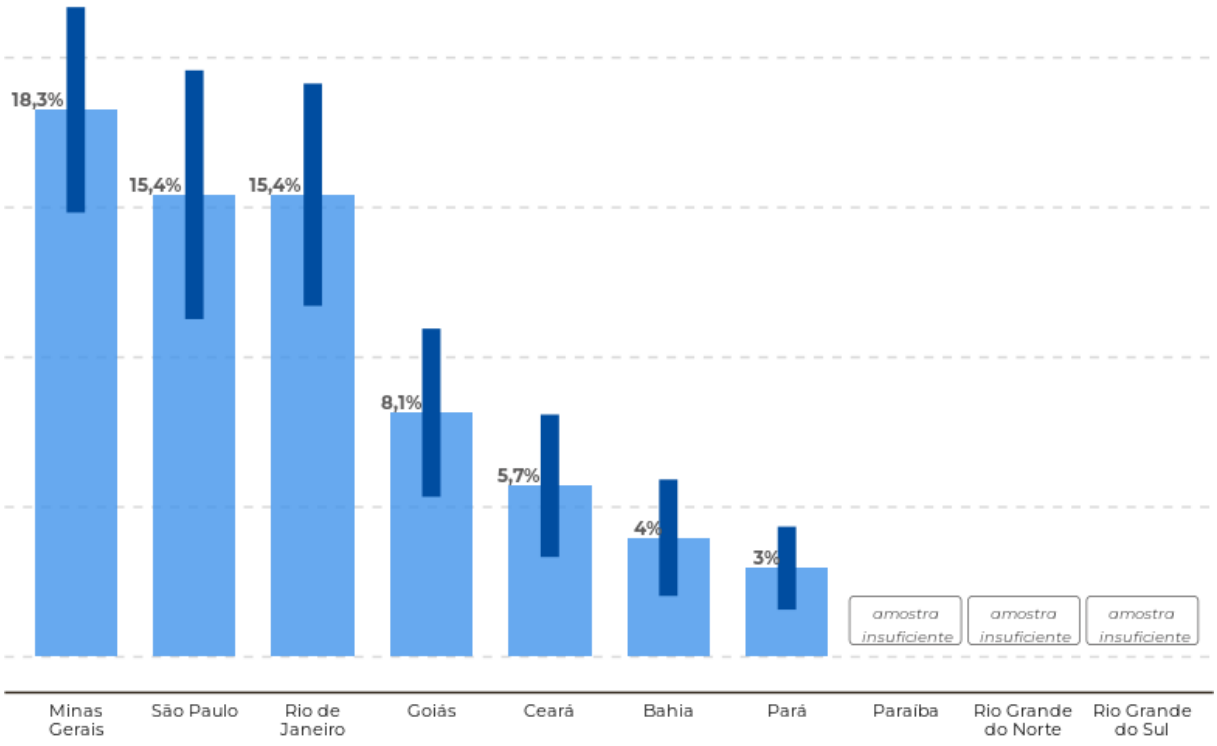

Fonte: CODEPLAN/DIEPS/GEREPS/PDAD 2021
Obs.: São reportadas até o limite das dez maiores categorias.

[36] Devido a problemas na coleta, esta questão apresentou problemas de consistência. Com o intuito de permanecer fornecendo estimativas para esta característica, cerca de 40% dos casos passou por um processo de imputação das respostas. As pessoas que foram imputadas como nascidas fora do DF não tiveram seu local de nascimento imputados.

Figura 3.2.2: Distribuição da motivação do responsável do domicílio a mudar e/ou retornar à capital federal, Lago Sul, 2021

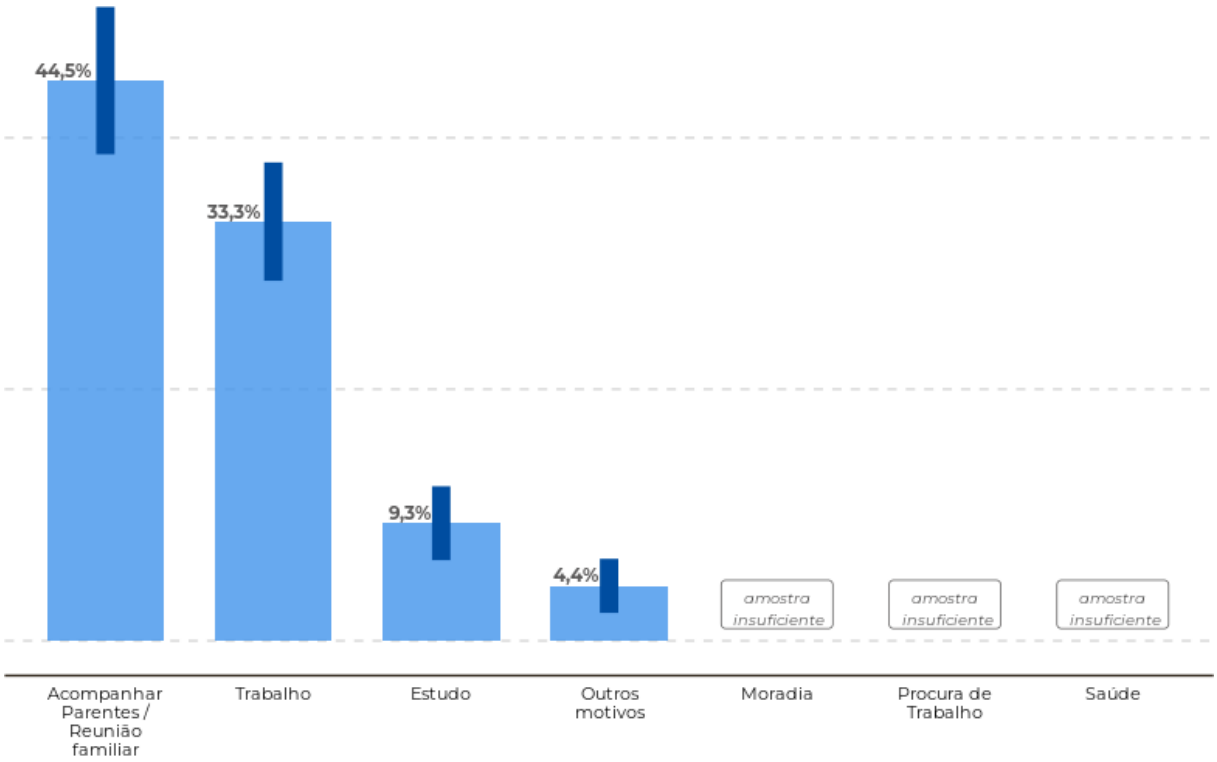

Fonte: CODEPLAN/DIEPS/GEREPS/PDAD 2021

Segundo os moradores com 14 anos ou mais de idade, 4,4% afirmaram ter intenção de constituir um novo domicílio no DF, sendo a RA Plano Piloto a mais reportada (46,2%) (Figura 3.2.3 e Tabela A.13).

Figura 3.2.3: Intenção e localidade para constituição de novo domicílio nos próximos 12 meses das pessoas de 14 anos ou mais, Lago Sul, 2021

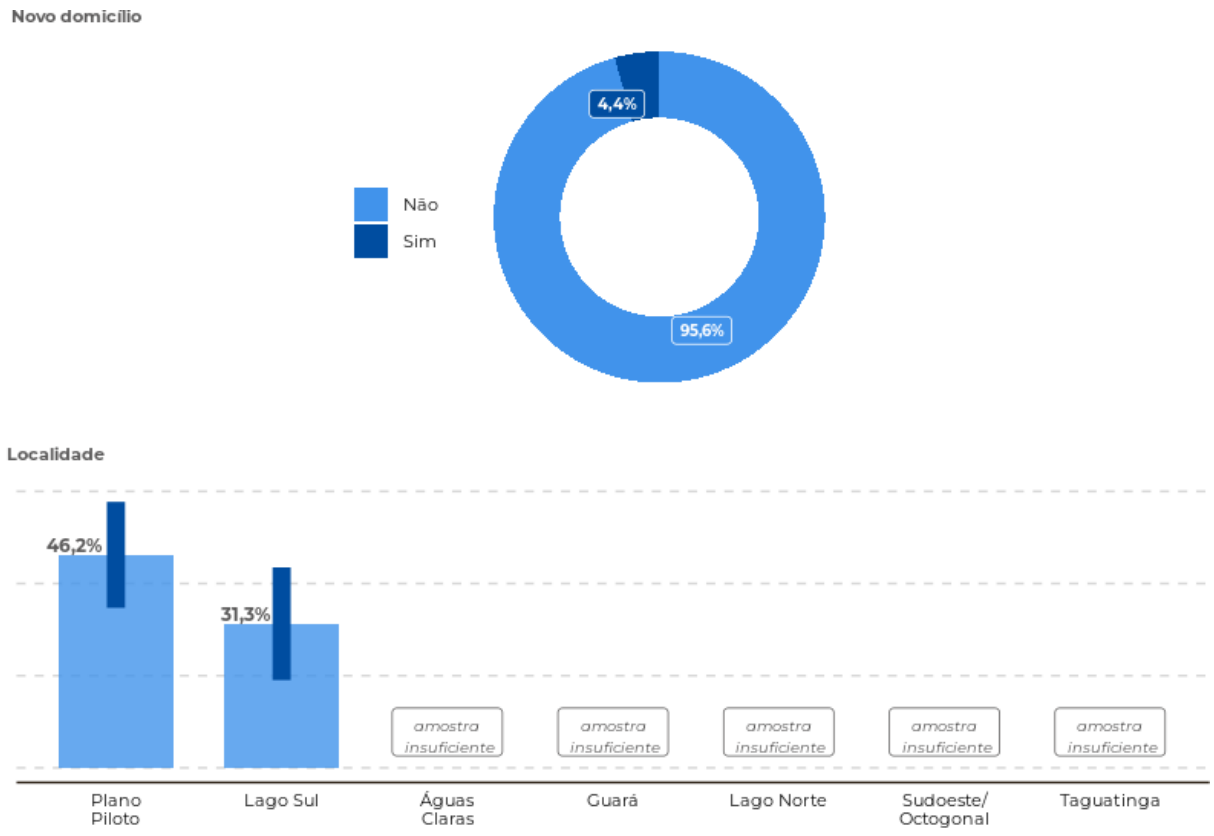

Fonte: CODEPLAN/DIEPS/GEREPS/PDAD 2021

3.3 Saúde

A PDAD 2021 levantou informações sobre pessoas com deficiência. No que diz respeito à visão, 84,8% declararam que "não têm dificuldade" para enxergar (Figura 3.3.1 e Tabela A.14). Quanto à audição, 97,5% declararam que "não têm dificuldade" para escutar (Figura 3.3.1 e Tabela A.15). Já para a locomoção, 97,8% informaram que "não têm dificuldade" para caminhar ou subir degraus (Figura 3.3.1 e Tabela A.16). Por fim, 98,1% reportaram que não têm dificuldade decorrente de limitações nas funções mentais, enquanto 97,7% não têm dificuldade para pegar pequenos objetos (Figura 3.3.1 e Tabelas A.17 e A.18).

Sobre a cobertura de plano de saúde privado, verificou-se que 91,2% declararam ter este serviço, dos quais 71,6% eram individual/familiar e 61,3% tinham coparticipação/franquia (Figura 3.3.2 e Tabela A.19).

No que diz respeito ao atendimento de saúde, 55,4% dos moradores informaram ter utilizado consultório particular/ clinica privada na última ocasião de necessidade (Figura 3.3.3 e Tabela A.22).

O principal motivo para o atendimento foi vacinação, segundo 41,6% (Figura 3.3.4 e Tabela A.23), e a localidade de atendimento predominante, entre estes, foi Plano Piloto (54,5%) (Figura 3.3.5 e Tabela A.24).

Figura 3.3.1: Distribuição da população segundo grau de dificuldade para enxergar, ouvir, caminhar ou subir degraus, limitação nas funções mentais ou dificuldade para pegar pequenos objetos, Lago Sul, 2021

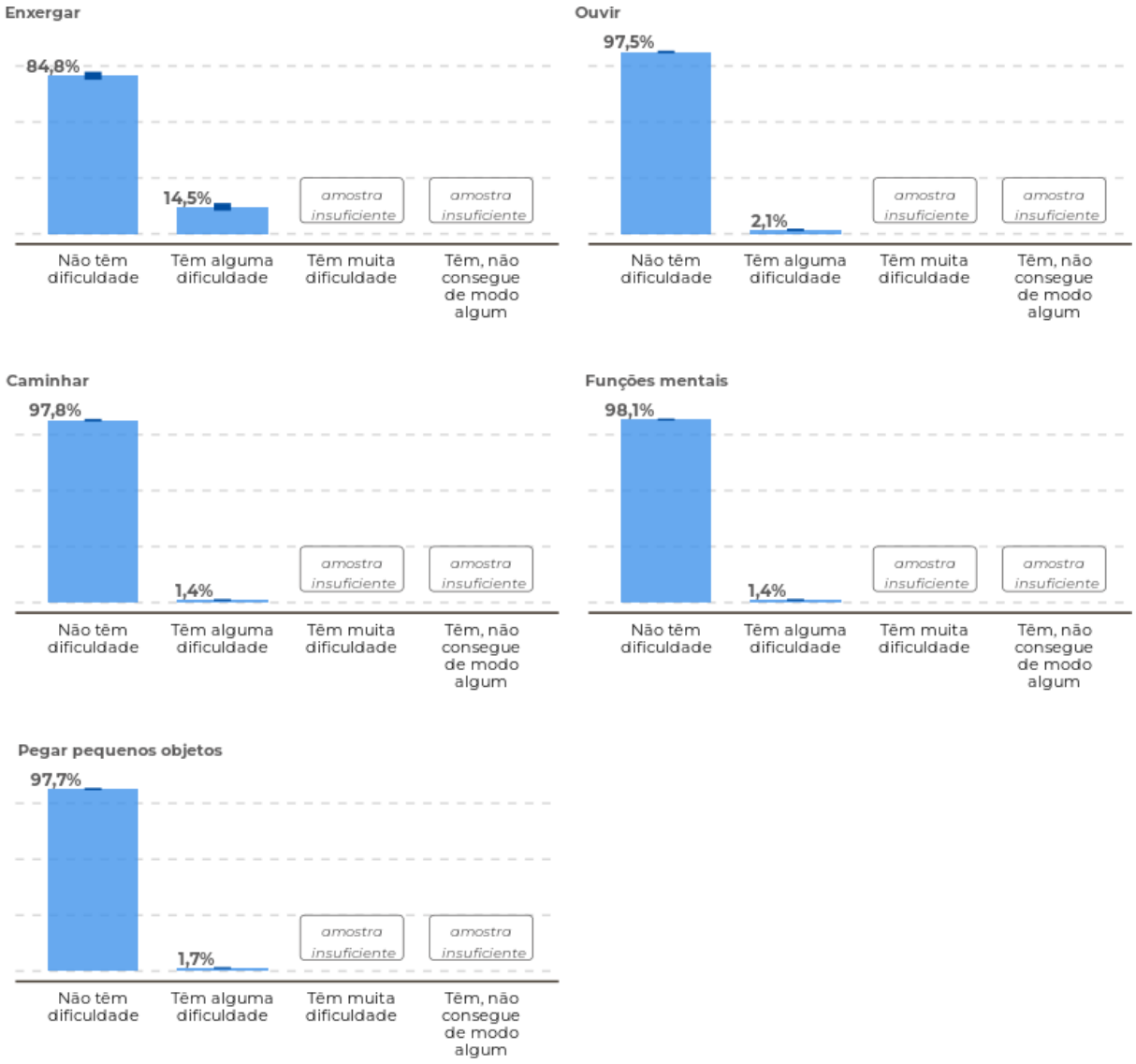

Fonte: CODEPLAN/DIEPS/GEREPS/PDAD 2021

Figura 3.3.2: Distribuição das pessoas com plano de saúde, por tipo de cobertura, Lago Sul, 2021

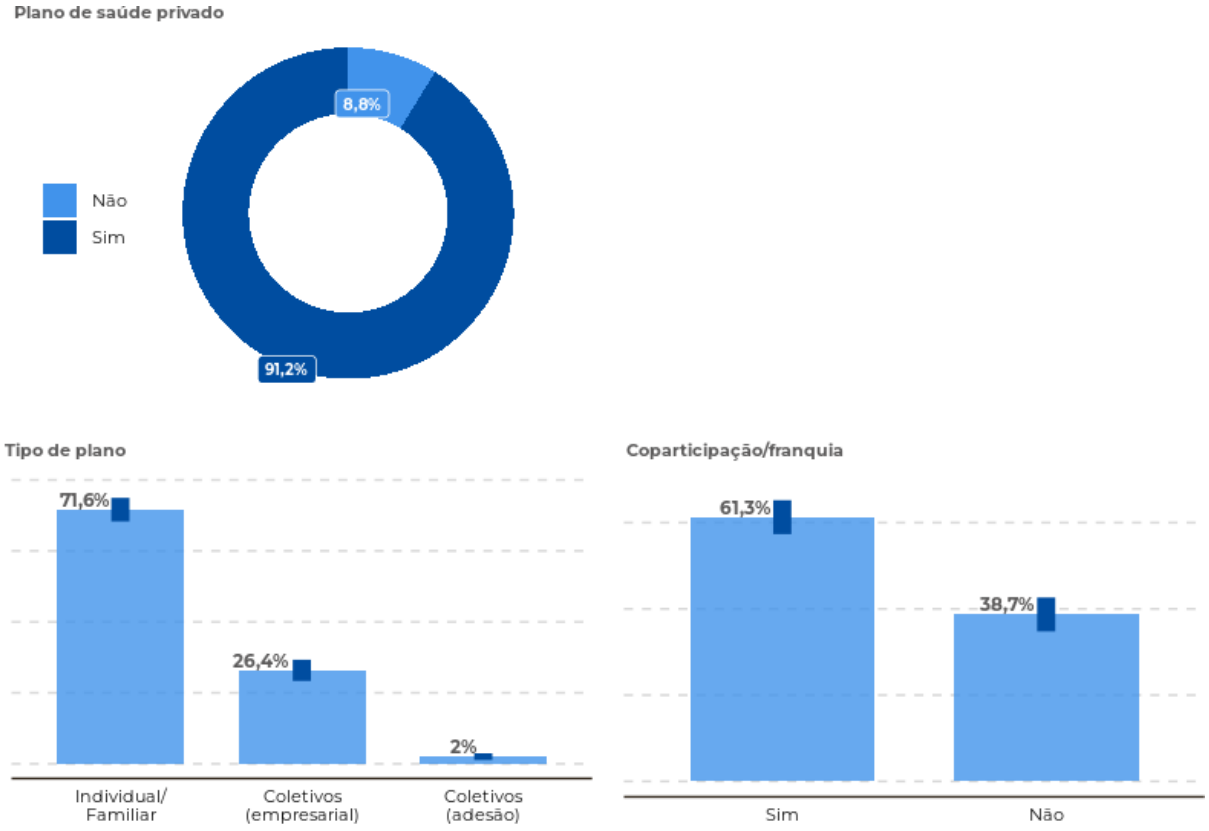

Fonte: CODEPLAN/DIEPS/GEREPS/PDAD 2021

Figura 3.3.3: Último serviço de saúde utilizado, Lago Sul, 2021

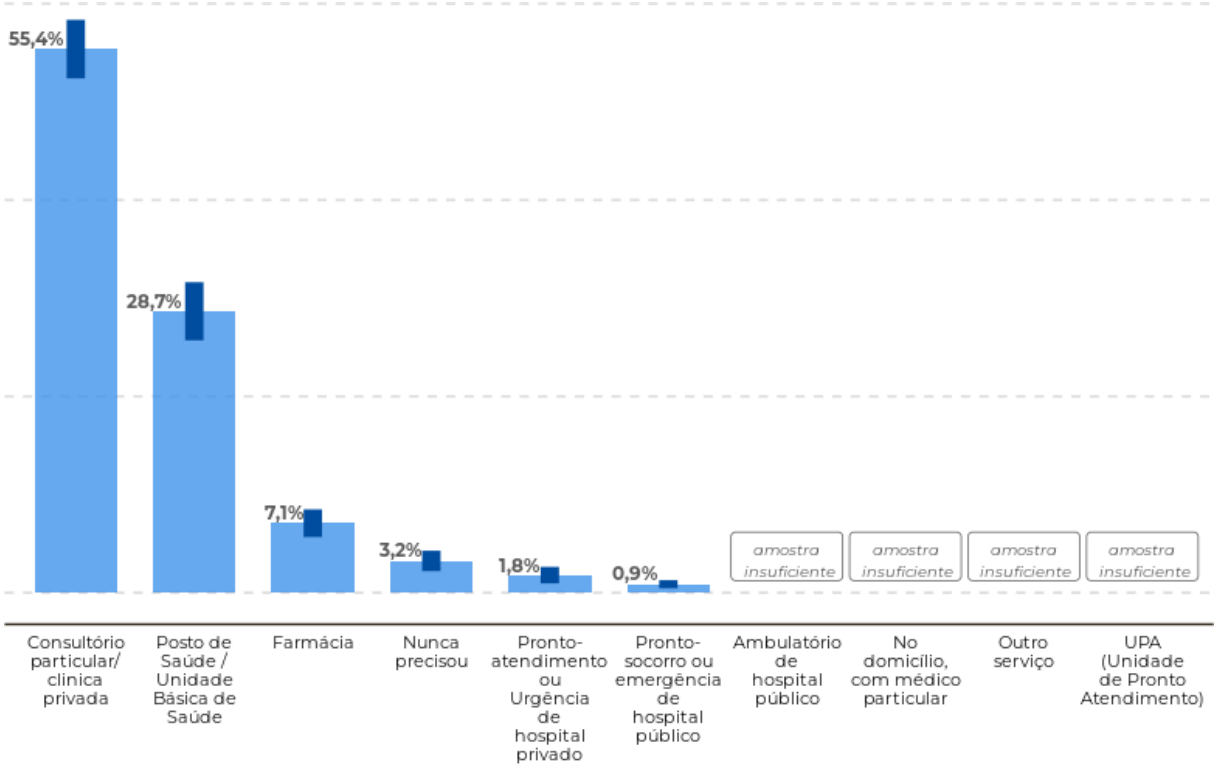

Fonte: CODEPLAN/DIEPS/GEREPS/PDAD 2021
Obs.: São reportadas até o limite das dez maiores categorias

Figura 3.3.4: Motivo do atendimento de saúde, Lago Sul, 2021

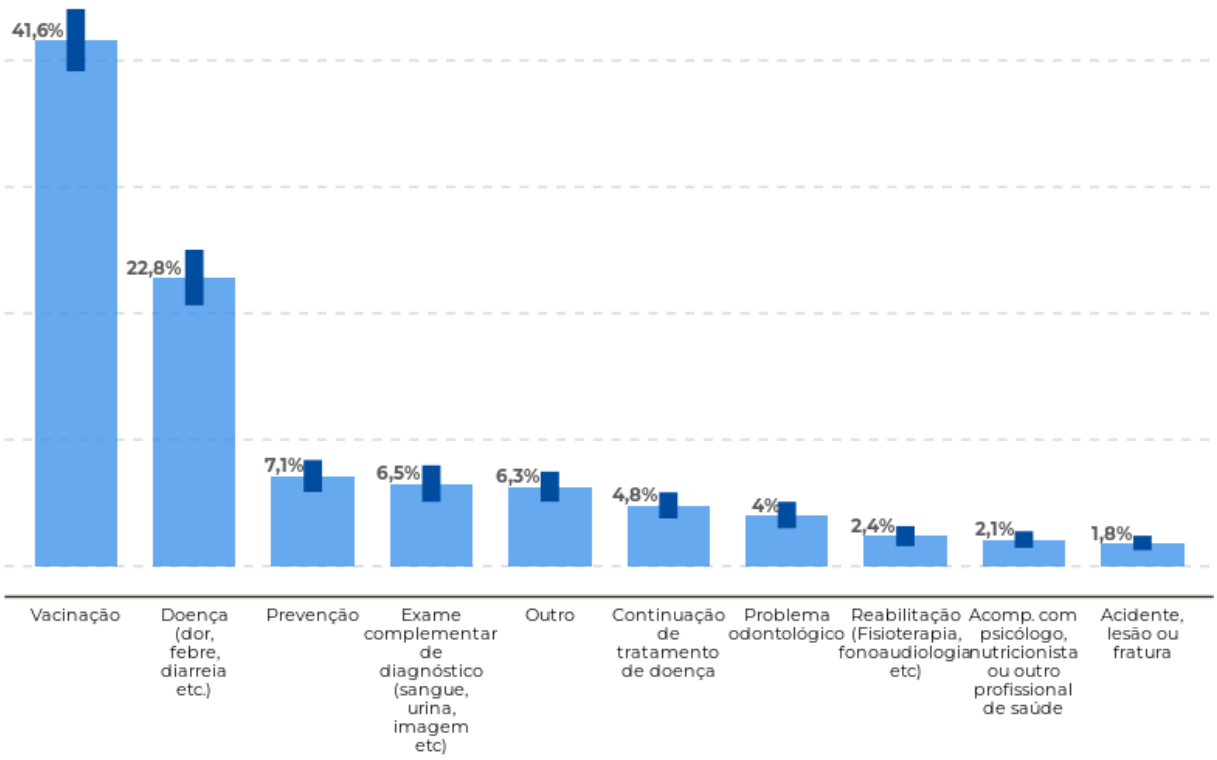

Fonte: CODEPLAN/DIEPS/GEREPS/PDAD 2021
Obs.: São reportadas até o limite das dez maiores categorias.

Figura 3.3.5: Localidade de atendimento do último serviço de saúde utilizado, Lago Sul, 2021

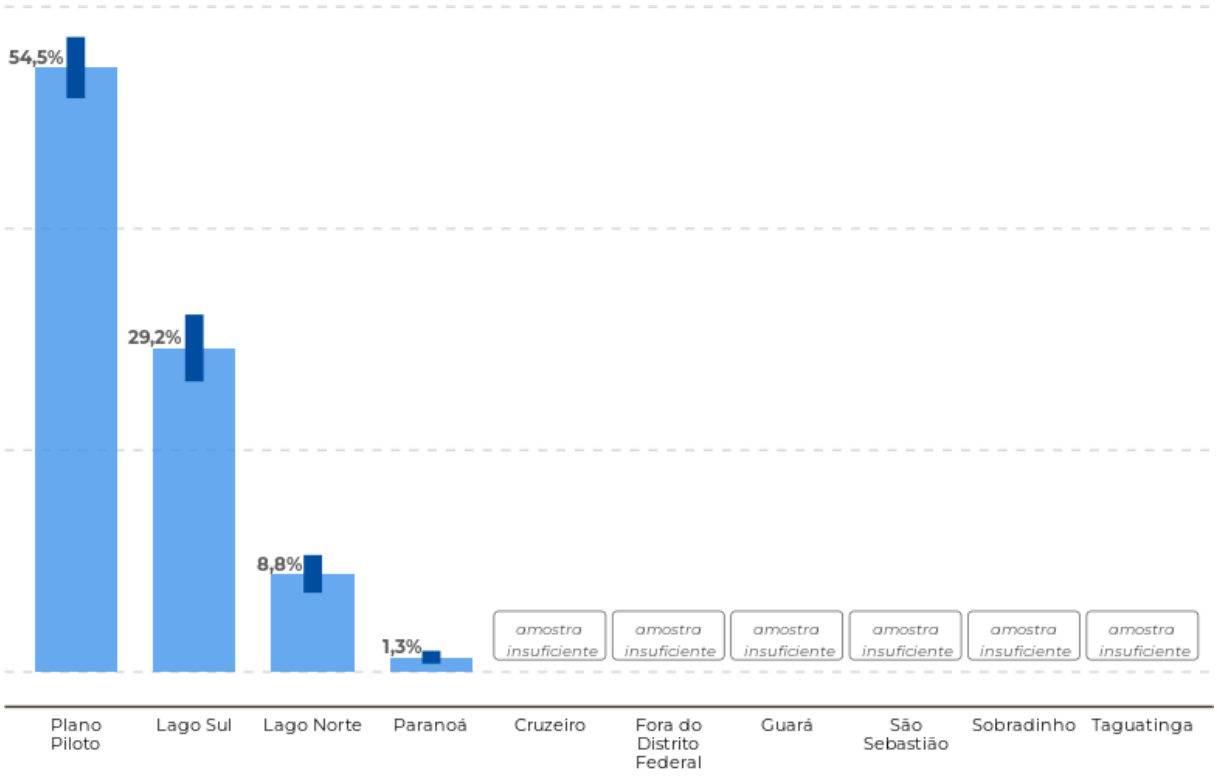

Fonte: CODEPLAN/DIEPS/GEREPS/PDAD 2021
Obs.: São reportadas até o limite das dez maiores categorias.

3.4 Comunicação

Sobre o acesso à comunicação, 91,7% dos entrevistados declararam possuir ao menos um celular para uso pessoal, enquanto 18,9% declararam possuir ao menos um tablet (Figura 3.4.1 e Tabelas A.25 e A.26). Quanto ao tipo de linha, 23% afirmaram utilizar pré-paga e 75% pós-paga[37] (Figura 3.4.2 e Tabelas A.27 e A.28).

Figura 3.4.1: Posse de celular e tablet para uso pessoal, Lago Sul, 2021

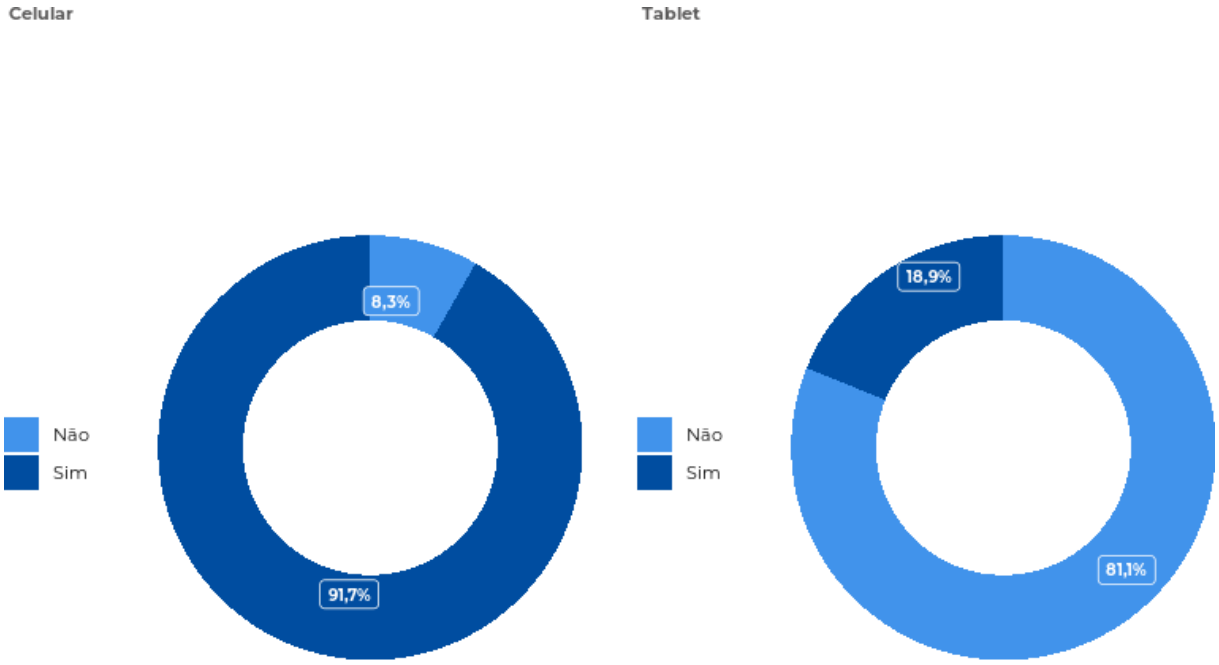

Fonte: CODEPLAN/DIEPS/GEREPS/PDAD 2021

Perguntados se acessaram à internet nos últimos três meses, 92,8% dos entrevistados responderam afirmativamente, dos quais 96,6% acessaram todos os dias. Sobre os meios de acesso, 81,4% se conectaram por meio de microcomputador, 98,7% por meio de celular ou tablet e 75,3% por outros meios (como televisão, videogame ou outro equipamento eletrônico)[38] (Figuras 3.4.3 e 3.4.4 e Tabelas A.29, A.31, A.32 e A.33).

[37] Um morador poderia ter, simultaneamente, tanto linha pré-paga quanta pós-paga.
[38] O mesmo morador pode ter acessado a internet por mais de um meio.

Figura 3.4.2: Posse de linha pré-paga e pós-paga para uso pessoal, Lago Sul, 2021

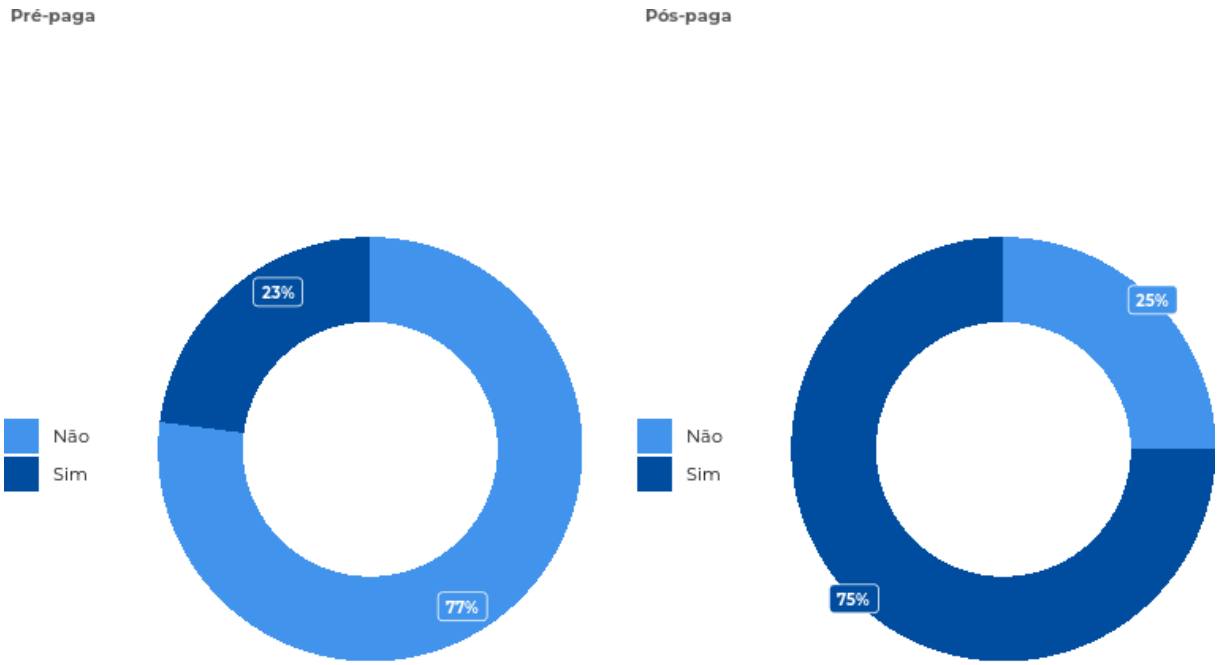

Fonte: CODEPLAN/DIEPS/GEREPS/PDAD 2021

Figura 3.4.3: Acesso à internet e meios de acesso nos últimos três meses, Lago Sul, 2021

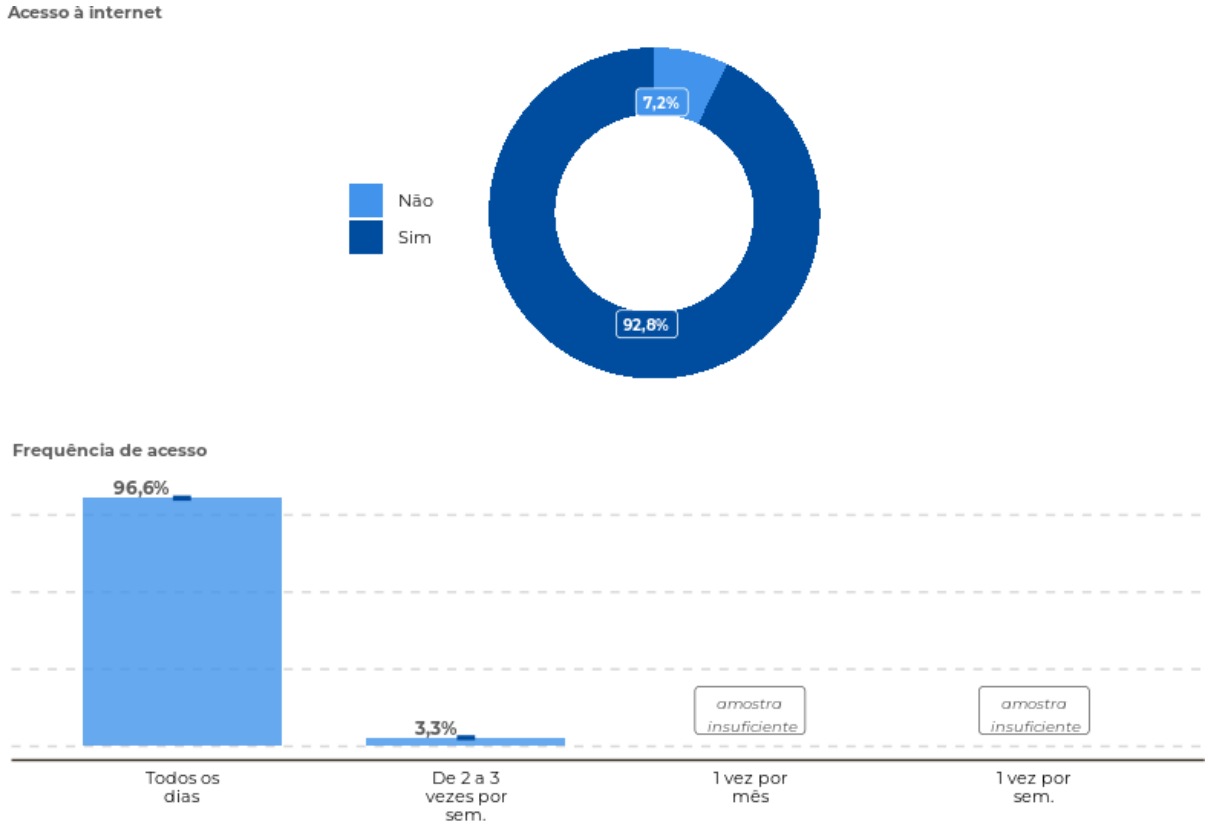

Fonte: CODEPLAN/DIEPS/GEREPS/PDAD 2021

Figura 3.4.4: Meios de acesso nos últimos três meses, Lago Sul, 2021

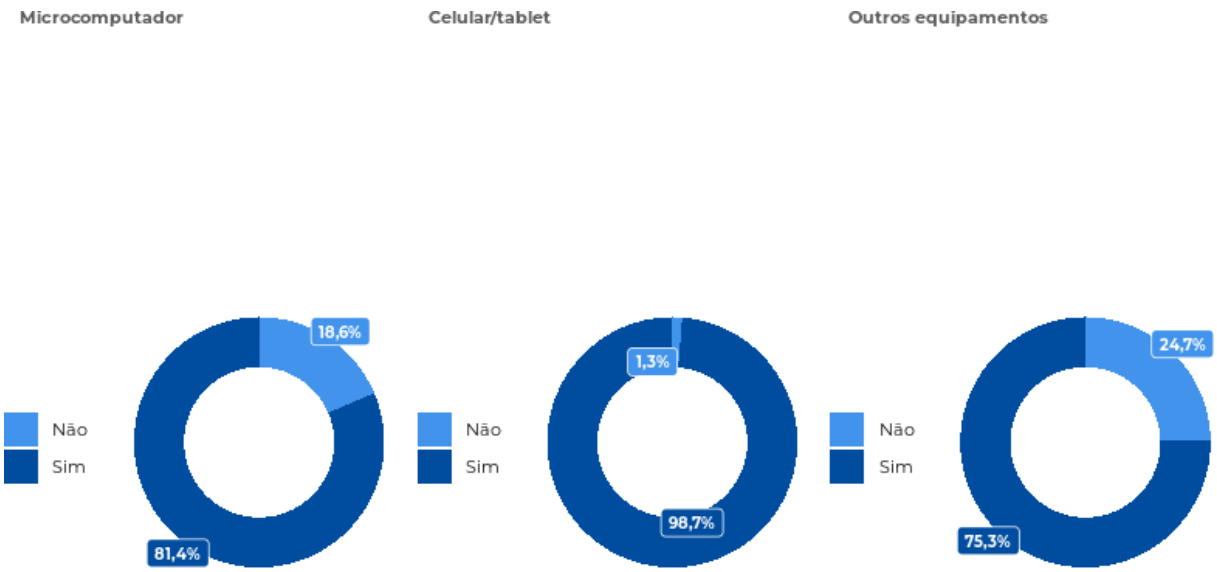

Fonte: CODEPLAN/DIEPS/GEREPS/PDAD 2021

Foram perguntados, ainda, os motivos de acesso à internet, tendo-se as seguintes respostas: 95,1% para comunicação; 94,8% para multimídia, lazer e cultura; 88,3% informações e notícias; 73,8% criação e compartilhamento de conteúdo; 73% para transações financeiras ou comerciais; 54,9% para educação ou cursos; e 57,1% para trabalho (Figura 3.4.5 e Tabelas A.34 até A.40).

Figura 3.4.5: Motivações do acesso à internet, Lago Sul, 2021

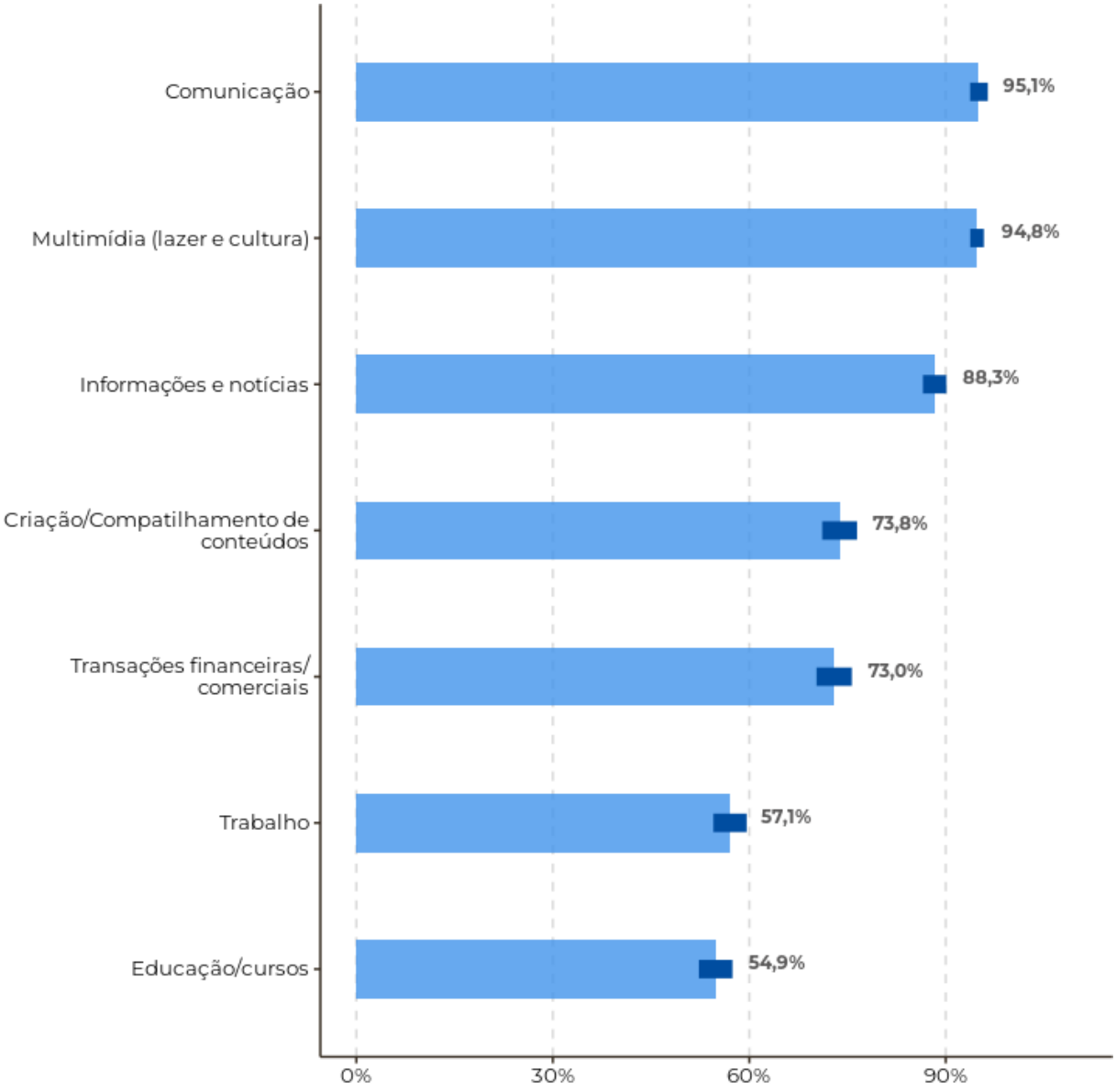

Fonte: CODEPLAN/DIEPS/GEREPS/PDAD 2021

3.5 Escolaridade

Sobre a escolaridade, 99% dos moradores com seis anos ou mais de idade declararam saber ler e escrever (Figura 3.5.1 e Tabela A.41)[39]. Para as pessoas entre 4 e 24 anos, 83,1% reportaram frequentar escola particular (Figura 3.5.2 e Tabela A.42). Considerando-se os estudantes de todas as idades, a modalidade predominante era presencial, para 93,4% dos respondentes (Figura 3.5.3 e Tabela A.43), e o turno predominante era matutino (50,7%) (Figura 3.5.4 e Tabela A.44). A frequência escolar, por faixa de idades[40], é apresentada na Figura 3.5.5.

Figura 3.5.1: População com seis anos ou mais de idade que declararam saber ler e escrever, Lago Sul, 2021

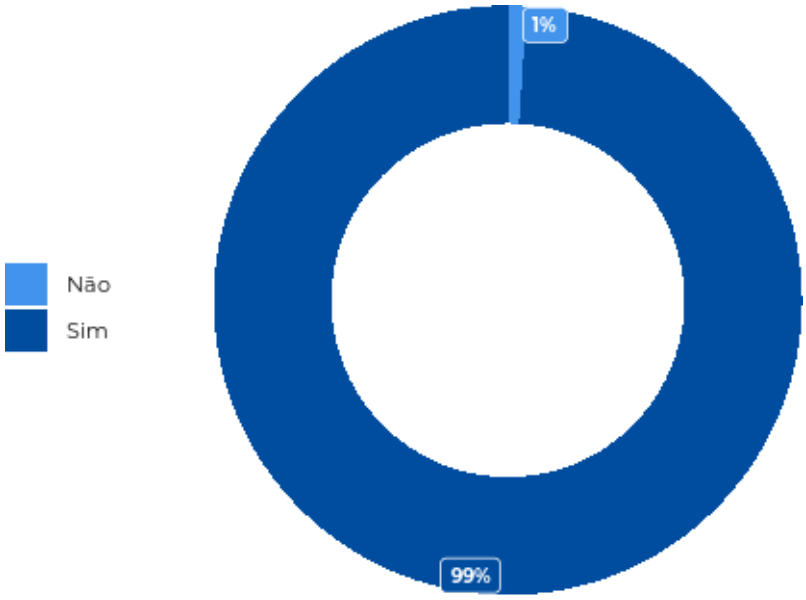

Fonte: CODEPLAN/DIEPS/GEREPS/PDAD 2021

Entre aqueles que frequentavam alguma unidade de ensino, 50,9% estudavam na RA Plano Piloto (Figura 3.5.6 e Tabela A.46). O principal meio de transporte declarado foi automóvel, para 76,9% dos respondentes (Figura 3.5.7 e Tabela A.47). O tempo gasto mais reportado foi até 15 minutos para 48,2% dos estudantes (Figura 3.5.8 e Tabela A.48).

[39] O reporte deste resultado desconsidera quem não sabia responder à questão.

[40] A frequência escolar é obrigatória para crianças a partir de 4 anos completos em 31/03 de cada ano. Como data de nascimento completa não foi captada para todas as crianças, não foi possível fazer o corte para as crianças de 4 anos. Dessa forma, as informações para essas faixas-etárias precisam ser analisadas com cautela.

Figura 3.5.2: Distribuição da frequência escolar da população entre 4 e 24 anos, Lago Sul, 2021

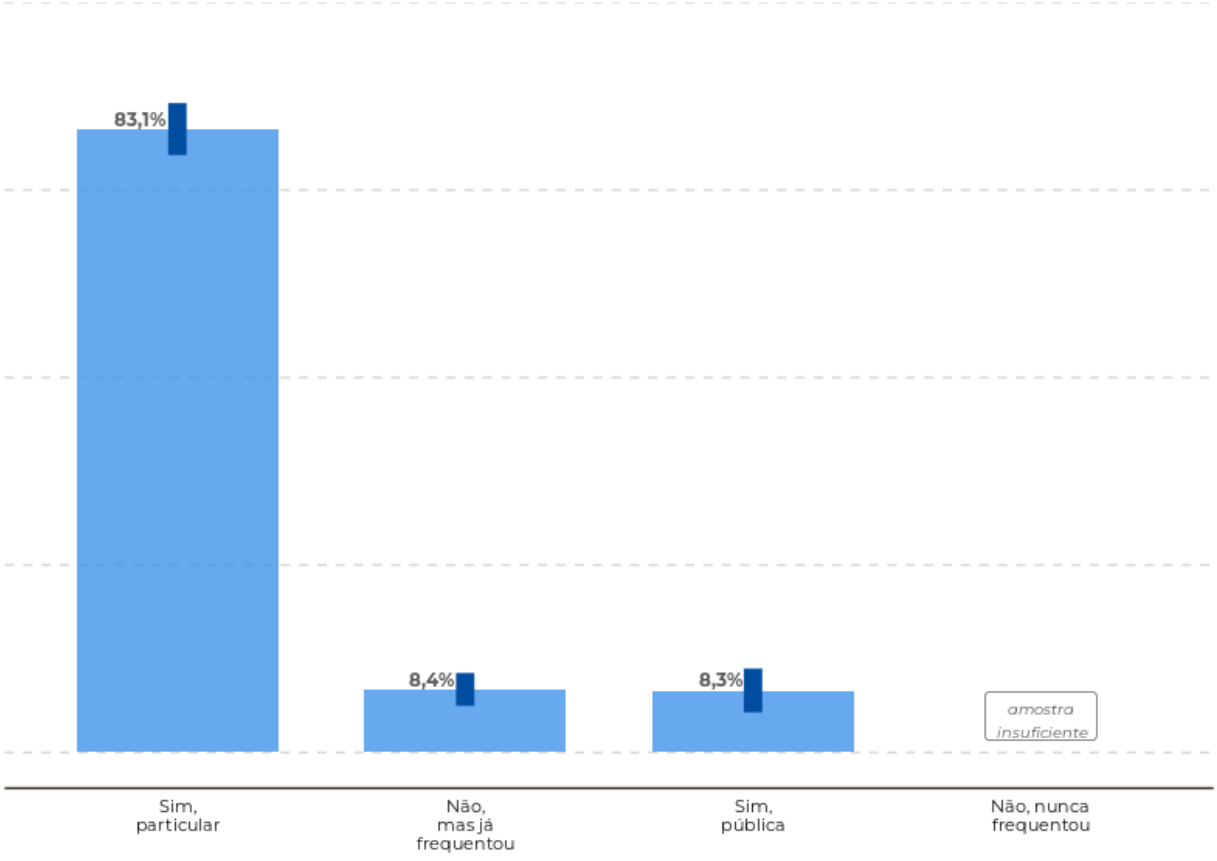

Fonte: CODEPLAN/DIEPS/GEREPS/PDAD 2021

Figura 3.5.3: Distribuição da modalidade de ensino de todos os estudantes, Lago Sul, 2021

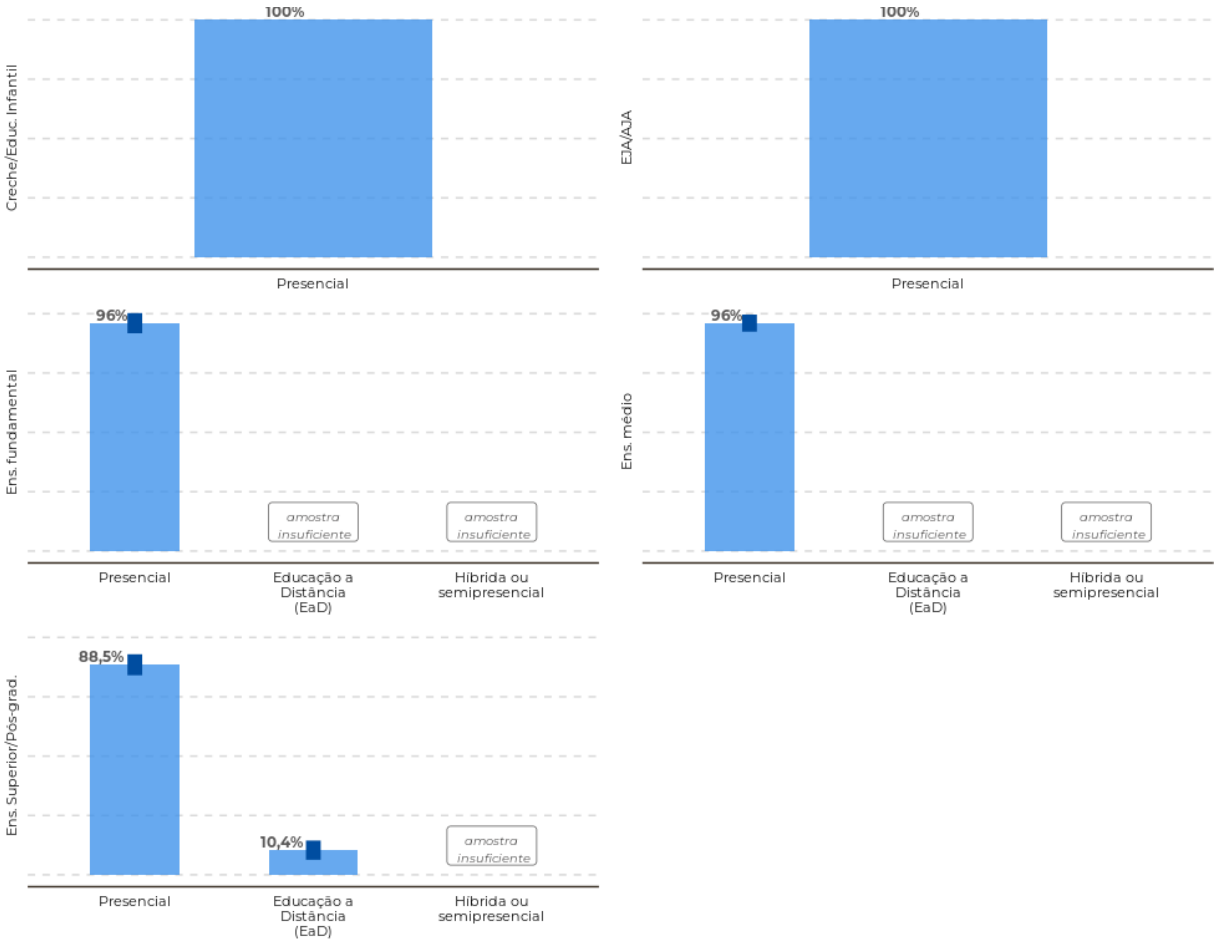

Fonte: CODEPLAN/DIEPS/GEREPS/PDAD 2021

Figura 3.5.4: Distribuição do turno de estudo de todos os estudantes, Lago Sul, 2021

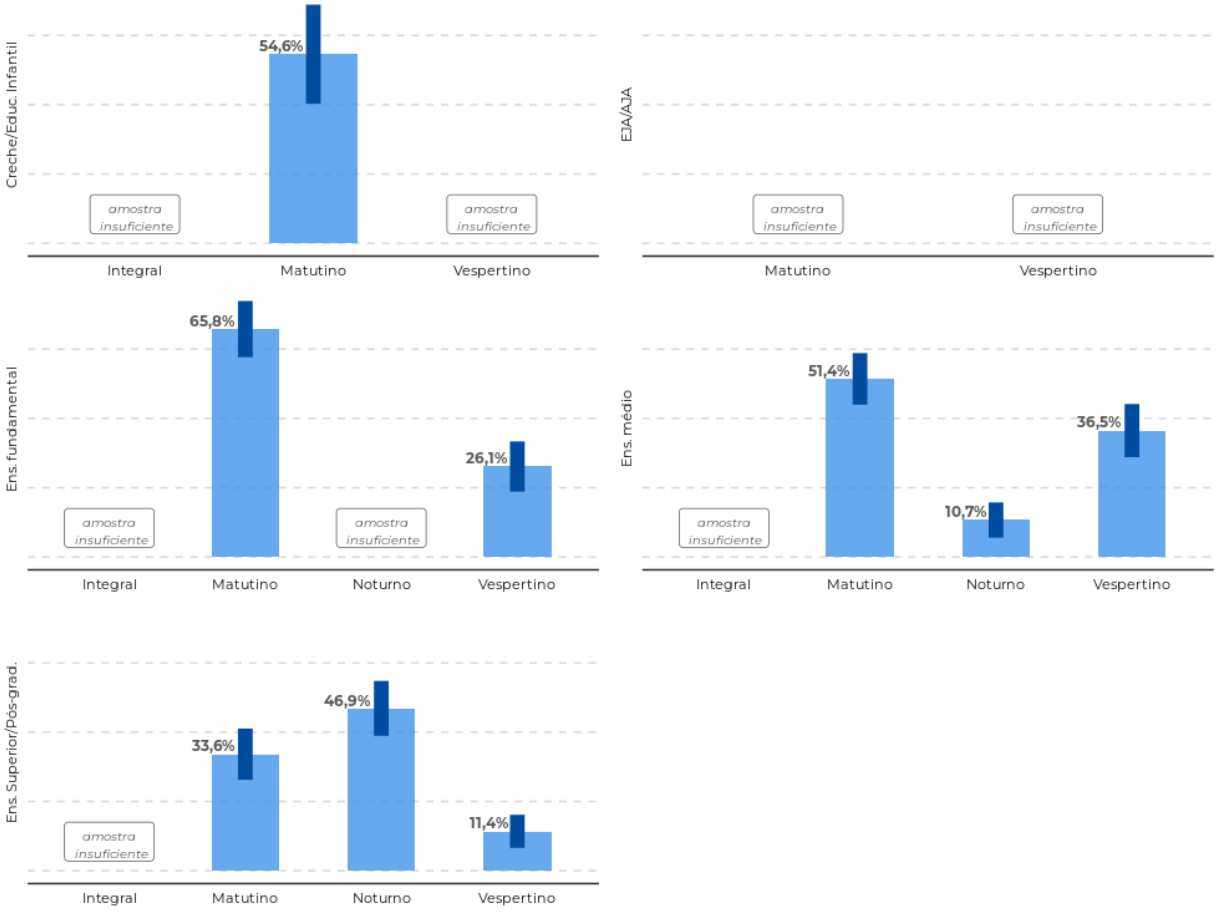

Fonte: CODEPLAN/DIEPS/GEREPS/PDAD 2021

Figura 3.5.5: Distribuição da frequência escolar por faixas de idade, Lago Sul, 2021

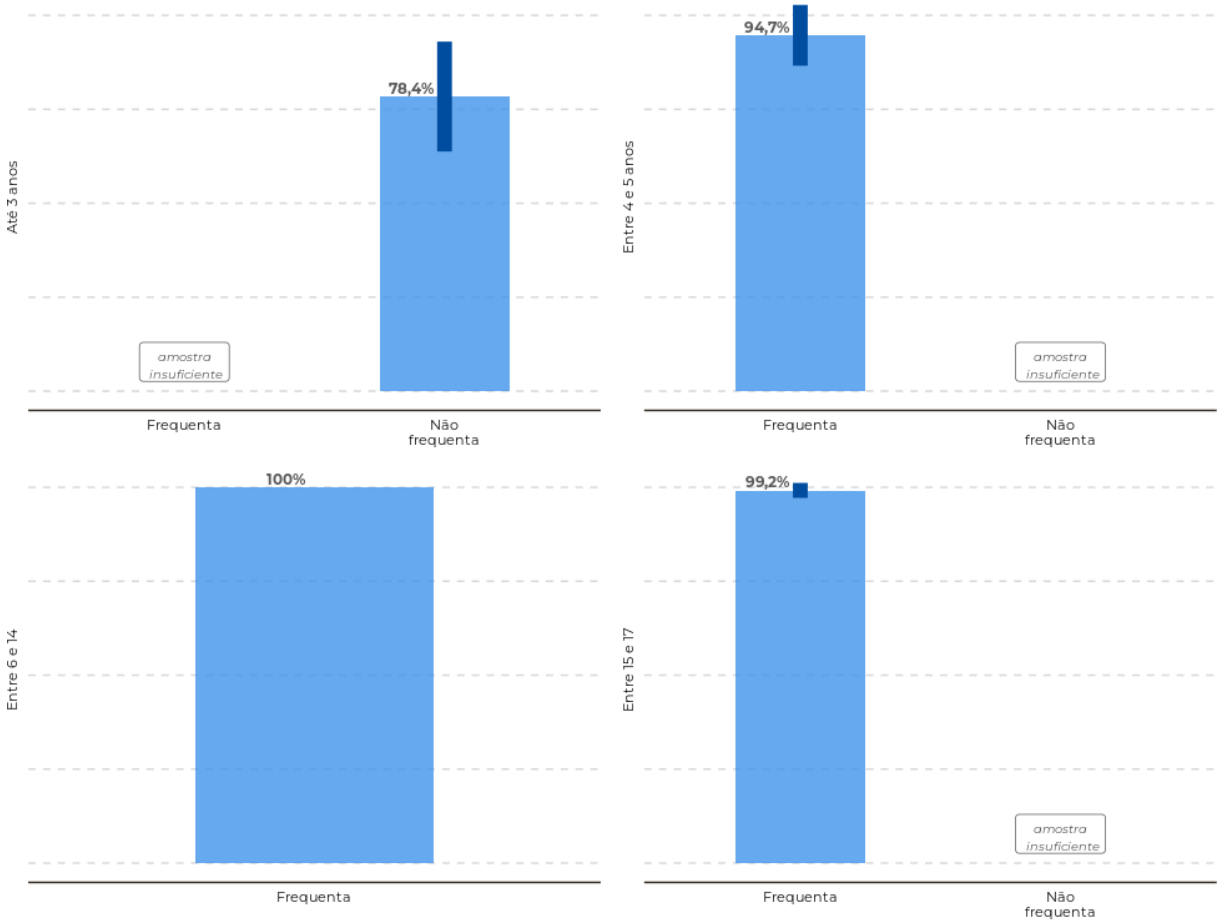

Fonte: CODEPLAN/DIEPS/GEREPS/PDAD 2021

Figura 3.5.6: Região Administrativa/Município da unidade de estudo, Lago Sul, 2021

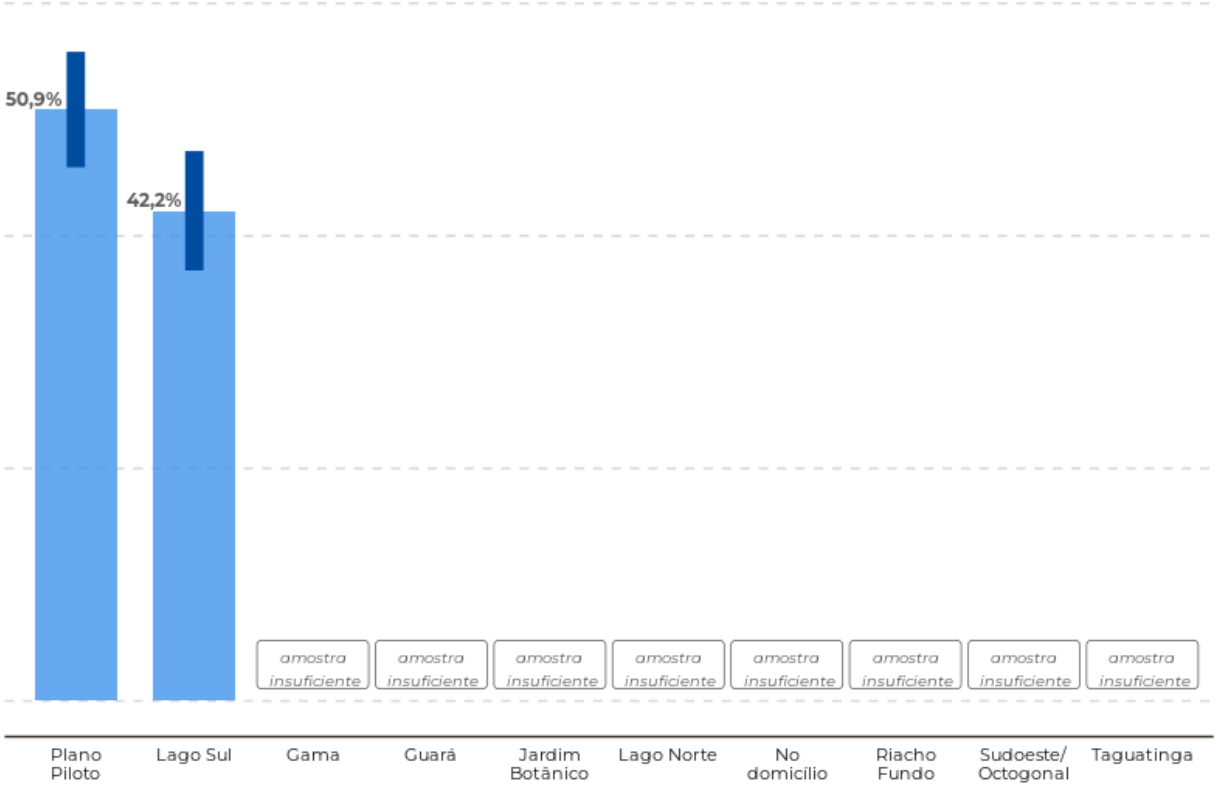

Fonte: CODEPLAN/DIEPS/GEREPS/PDAD 2021
Obs.: São reportadas até o limite das dez maiores categorias.

Figura 3.5.7: Principal meio de transporte da casa até a escola de todos os estudantes, Lago Sul, 2021

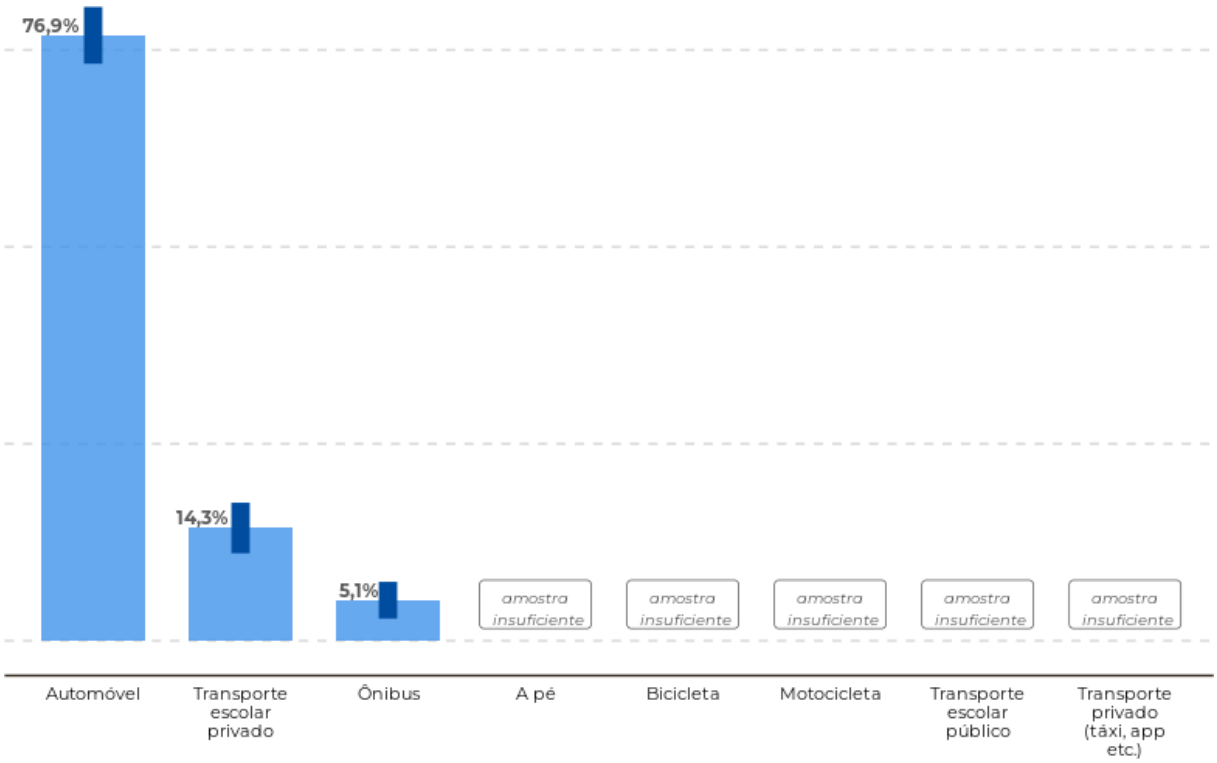

Fonte: CODEPLAN/DIEPS/GEREPS/PDAD 2021

Figura 3.5.8: Tempo de deslocamento da casa até a escola de todos os estudantes, Lago Sul, 2021

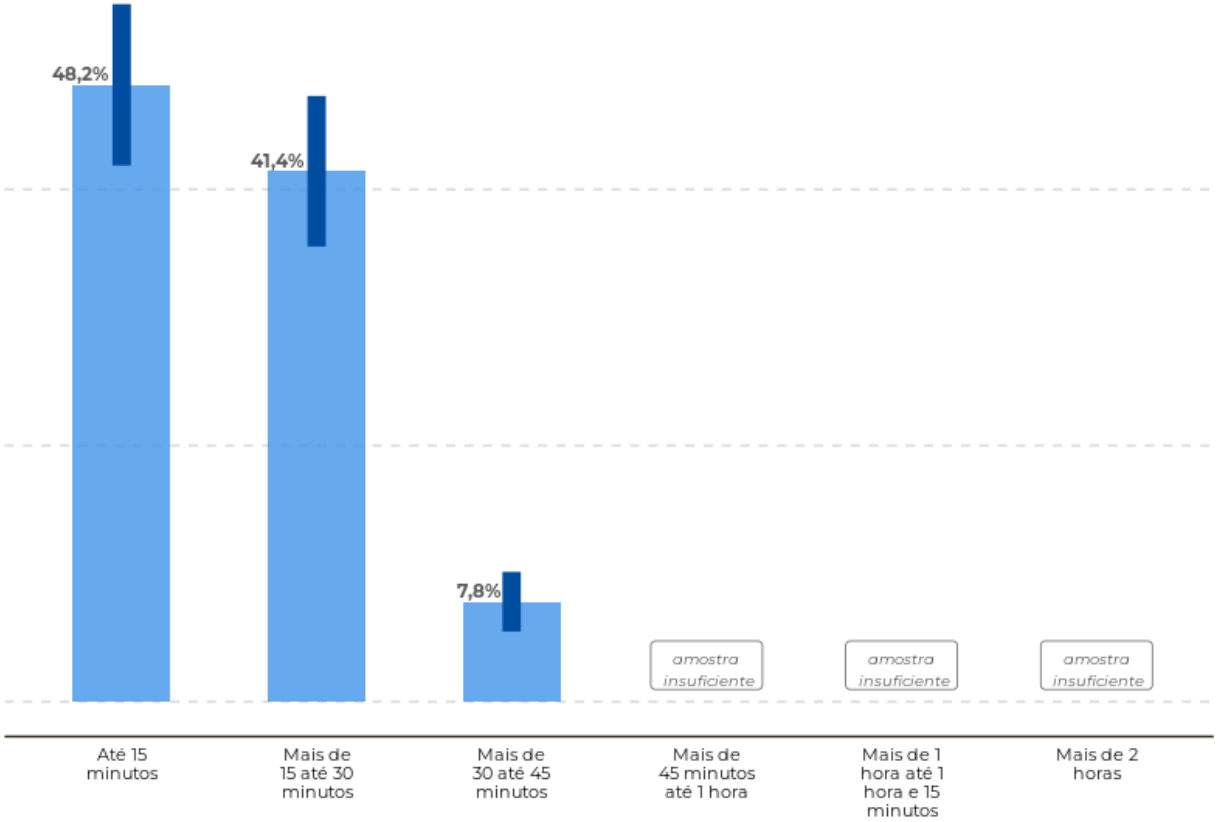

Fonte: CODEPLAN/DIEPS/GEREPS/PDAD 2021

Por fim, no que diz respeito à escolaridade das pessoas com 25 anos ou mais, 87,2% declararam ter o ensino superior completo (Figura 3.5.9 e Tabela A.49).

Figura 3.5.9: Escolaridade da população com 25 anos ou mais, Lago Sul, 2021

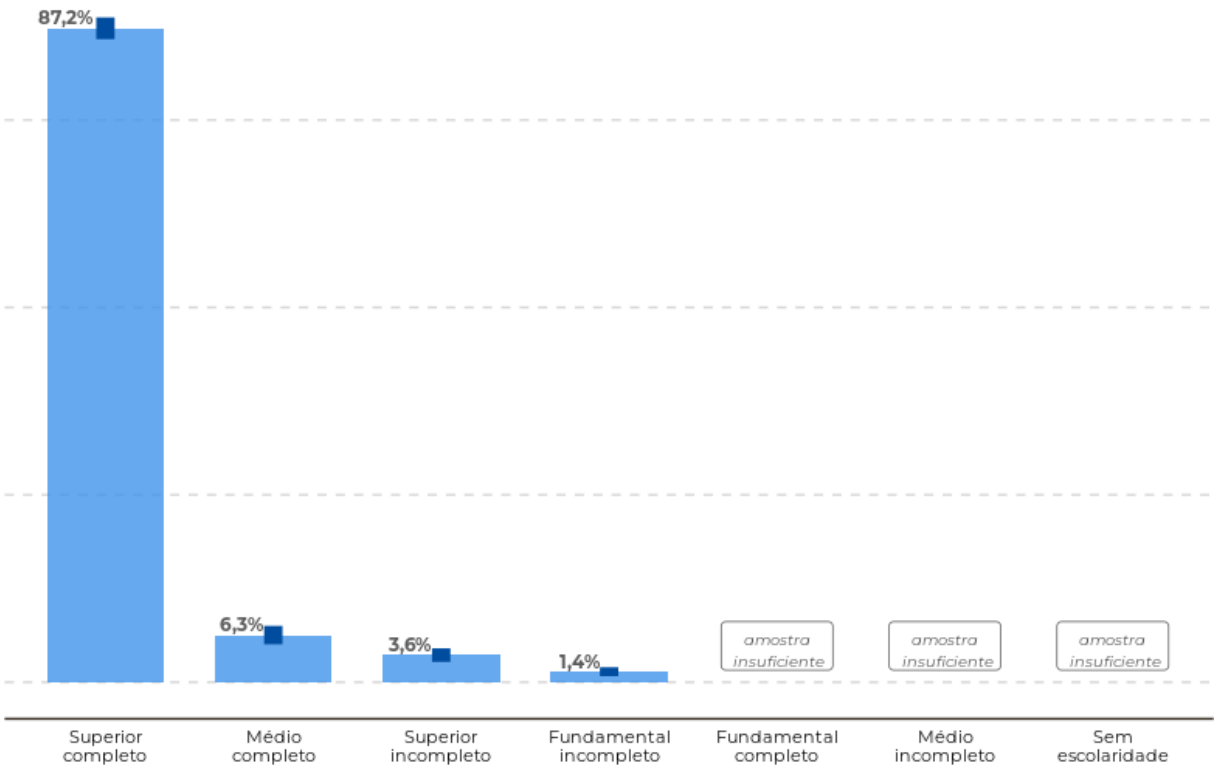

Fonte: CODEPLAN/DIEPS/GEREPS/PDAD 2021

3.6 Trabalho

Considerando as pessoas com 14 anos ou mais, também conhecida como população em idade ativa (PIA), 48,1% estavam economicamente ativas, isto é, ocupadas ou desocupadas[41] (12.897 pessoas, Figura 3.6.1).

Figura 3.6.1: Taxa de participação das pessoas em idade ativa (14 anos ou mais de idade), Lago Sul, 2021

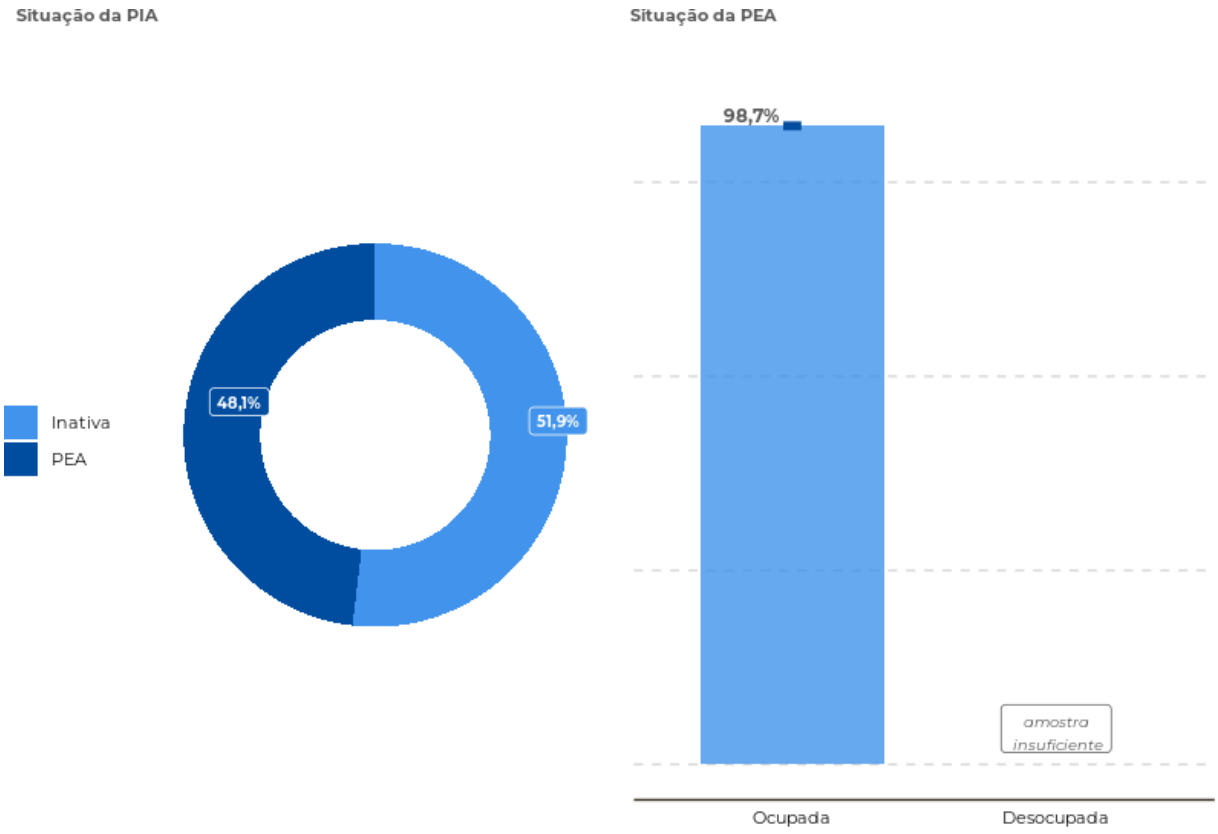

Fonte: CODEPLAN/DIEPS/GEREPS/PDAD 2021

Uma questão relevante para o mercado de trabalho diz respeito à parcela da população que não estuda, nem trabalha, os chamados "nem-nem". Para a população entre 18 e 29 anos, 15,1% se encontravam nesta situação (692 jovens).

Para os ocupados, foi questionada a atividade da empresa em que estes exerciam o seu trabalho principal, sendo o setor de Outros Serviços o mais informado, segundo 44% dos respondentes (Figura 3.6.4 e Tabela A.56). A Região Administrativa onde a maioria dos respondentes declarou exercer seu

[41] São classificadas como desocupadas as pessoas que não tinham trabalho, mas procuraram por uma ocupação no período considerado.

Figura 3.6.2: População de 18 a 29 anos por situação de trabalho e estudo, Lago Sul, 2021

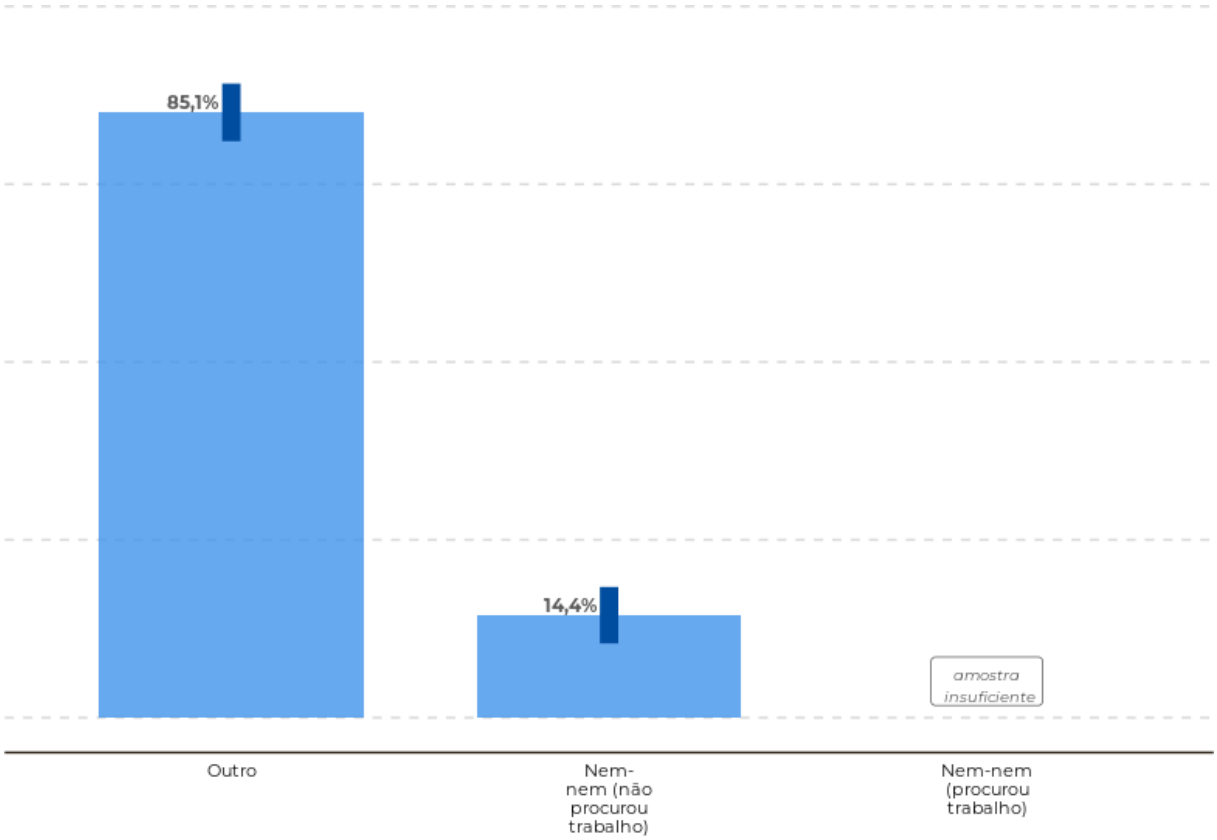

Fonte: CODEPLAN/DIEPS/GEREPS/PDAD 2021

trabalho principal foi Plano Piloto (59,3%, Tabela A.55 e Figura 3.6.3). Finalmente, a posição na ocupação mais comum foi empregado no setor público, para 40,7% dos entrevistados (Figura 3.6.5 e Tabela A.57). Em média, os trabalhadores estavam há 11,7 anos na ocupação principal, e trabalhavam 34,8 horas por semana.

Figura 3.6.3: Local onde as pessoas exerciam seu trabalho principal, Lago Sul, 2021

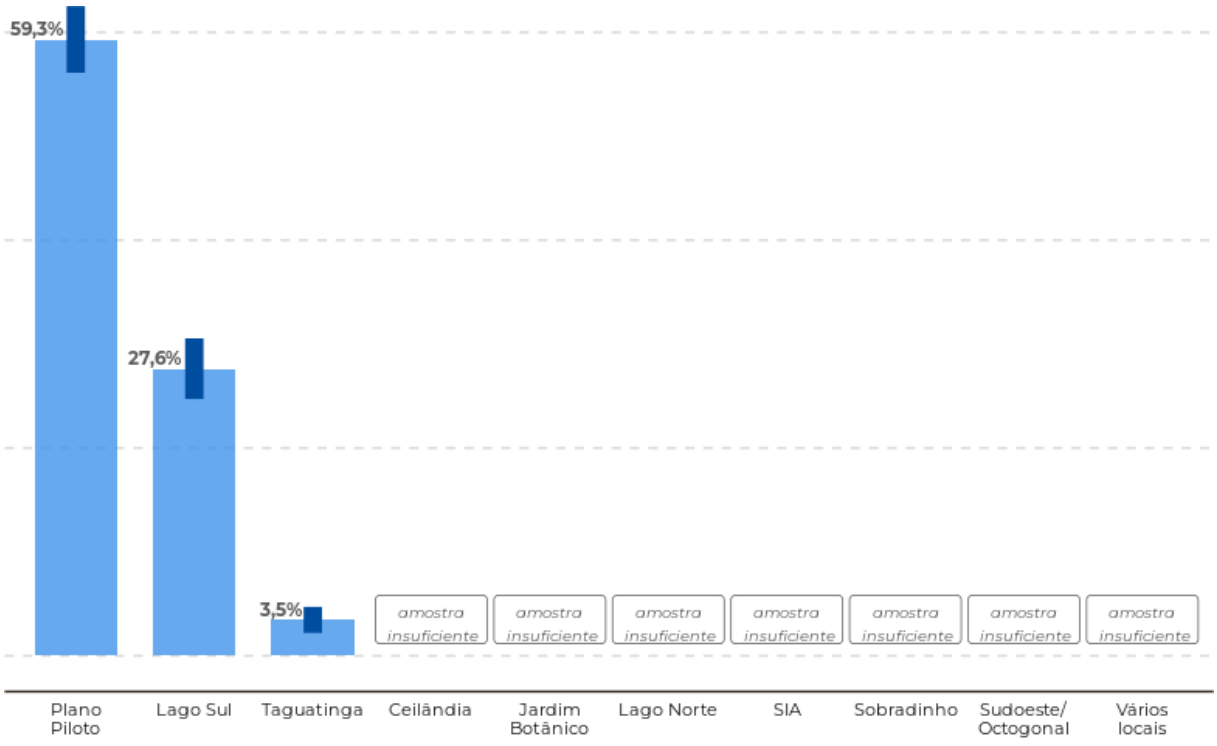

Fonte: CODEPLAN/DIEPS/GEREPS/PDAD 2021
Obs.: São reportadas até o limite das dez maiores categorias.

Sobre os trabalhadores do setor público, a principal área de atuação era federal (55,1%) e era estatutário (80,1%) (Figura 3.6.6 e Tabelas A.58 e A.59).

Sobre os empreendedores (sócios de cooperativas, autônomos, empregadores, donos de negócios familiares e profissionais liberais), 50,1% eram microempreendedores individuais (MEI) e 72,8% possuíam Cadastro Nacional de Pessoa Jurídica (CNPJ) (Figura 3.6.7 e Tabelas A.60 e A.61).

No que tange ao deslocamento para o trabalho, 97,6% informaram utilizar automóvel (Figura 3.6.8 e Tabela A.62). Dentre estes, o principal meio de transporte reportado foi automóvel, segundo 97,5% dos entrevistados. Sobre a duração deste trajeto, de 15 até 30 minutos foi o tempo de deslocamento mais reportado (44,3% dos respondentes, Figura 3.6.9 e Tabela A.64).

Figura 3.6.4: Distribuição do setor de atividade da empresa em que as pessoas exerciam seu trabalho principal, Lago Sul, 2021

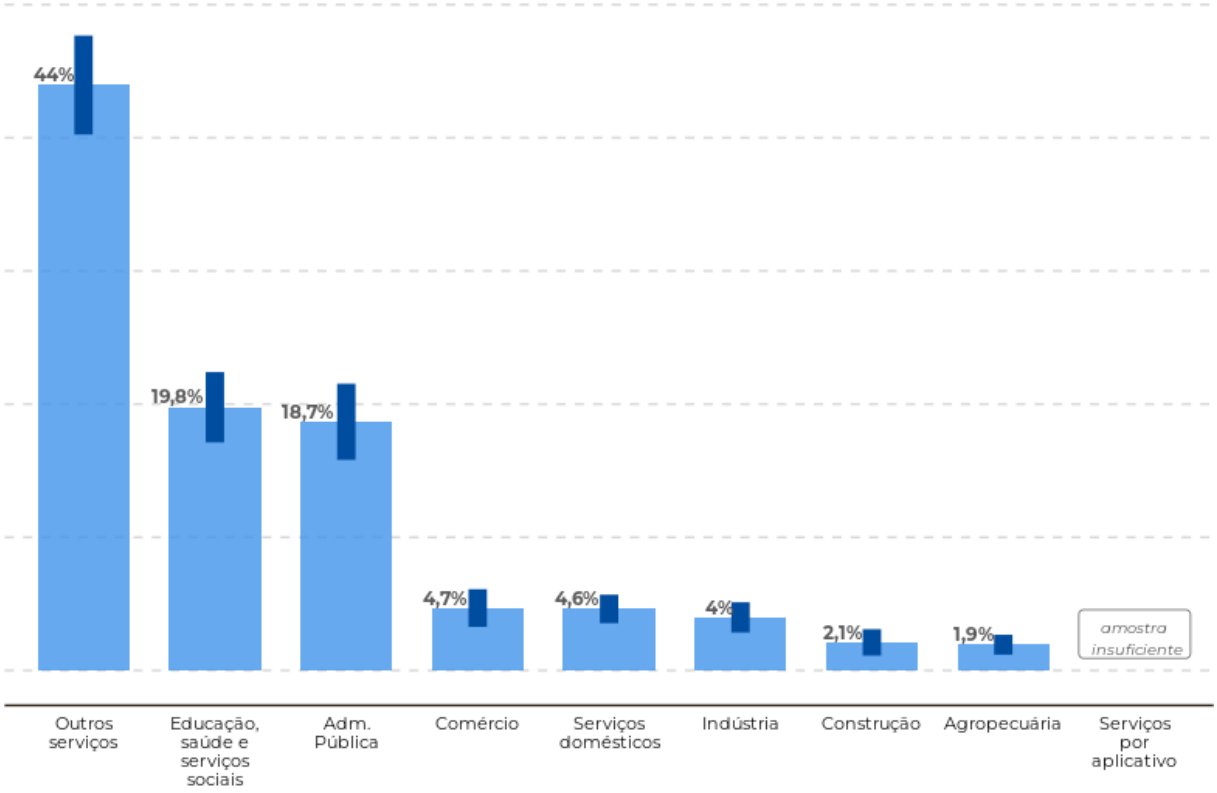

Fonte: CODEPLAN/DIEPS/GEREPS/PDAD 2021

Figura 3.6.5: Distribuição da posição na ocupação principal, Lago Sul, 2021

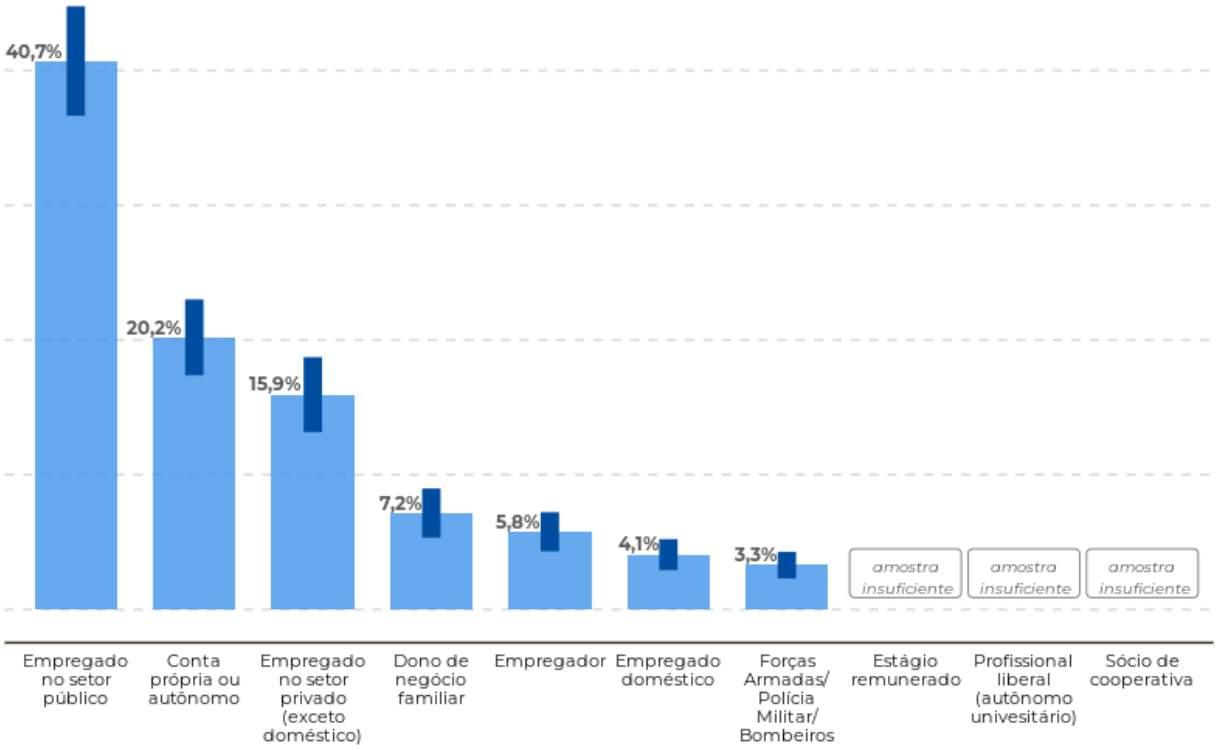

Fonte: CODEPLAN/DIEPS/GEREPS/PDAD 2021
Obs.: São reportadas até o limite das dez maiores categorias.

Figura 3.6.6: Área de atuação e modalidade de contratação dos servidores/empregados públicos, Lago Sul, 2021

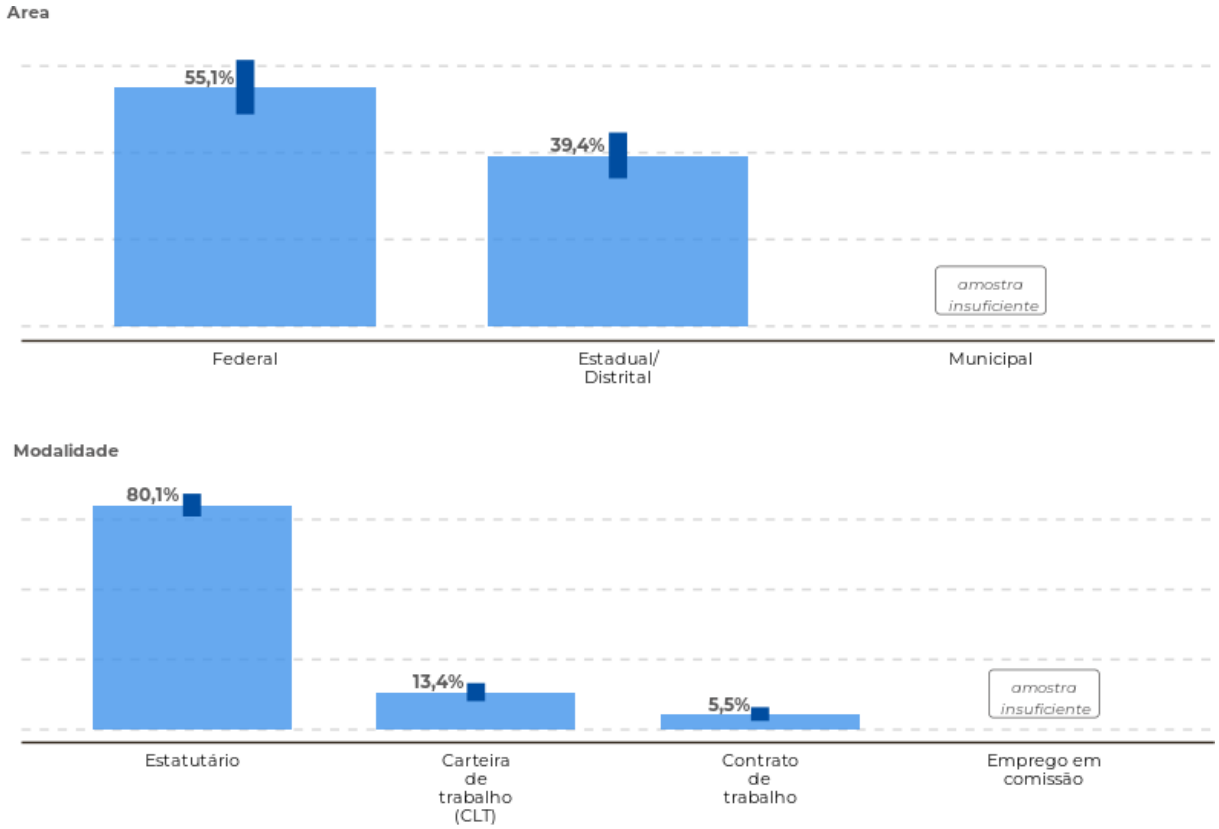

Fonte: CODEPLAN/DIEPS/GEREPS/PDAD 2021

Figura 3.6.7: Empreendedores segundo cadastro de Microempreendedores Individuais (MEI) e Cadastro Nacional de Pessoa Jurídica (CNPJ), Lago Sul, 2021

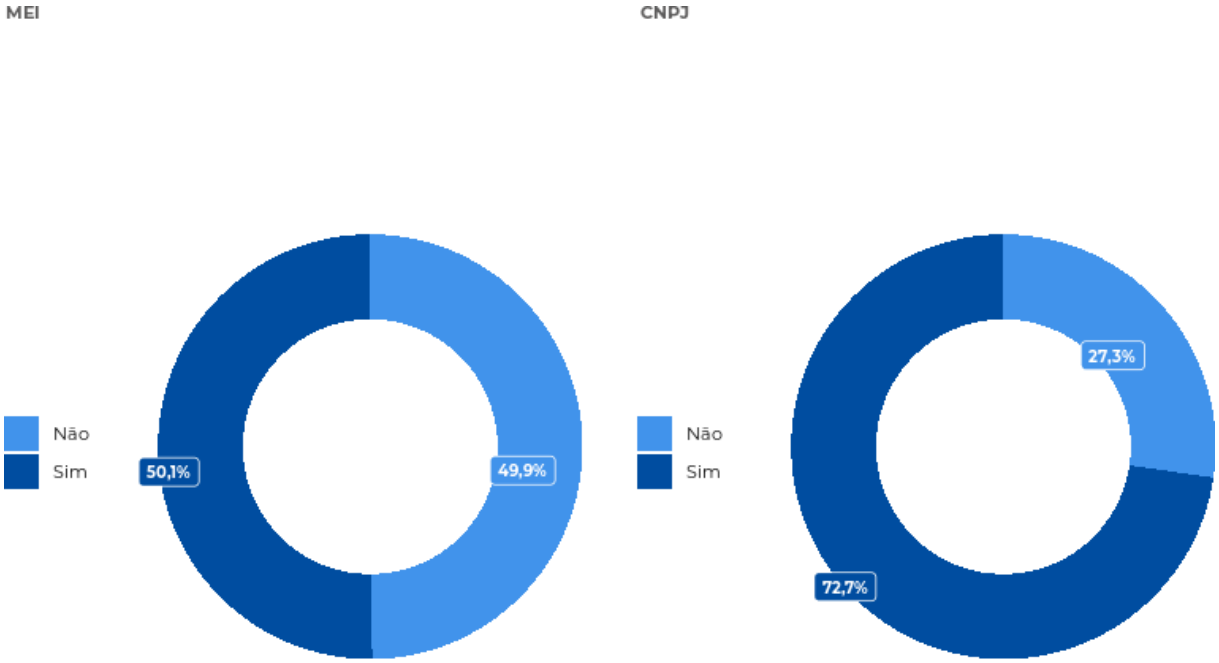

Fonte: CODEPLAN/DIEPS/GEREPS/PDAD 2021

Figura 3.6.8: Meios de transporte utilizados para deslocamento até o trabalho principal, Lago Sul, 2021

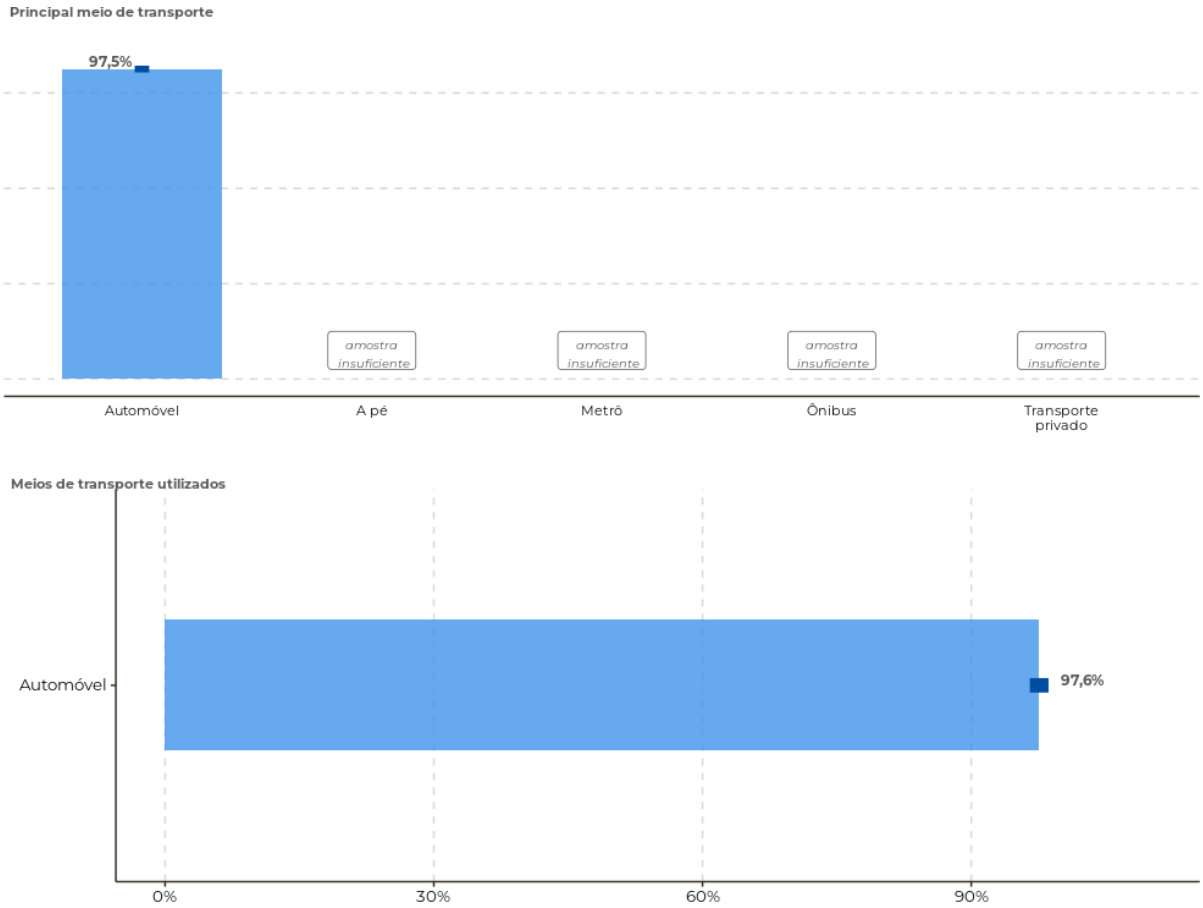

Fonte: CODEPLAN/DIEPS/GEREPS/PDAD 2021

Figura 3.6.9: Tempo para deslocamento até o trabalho principal, Lago Sul, 2021

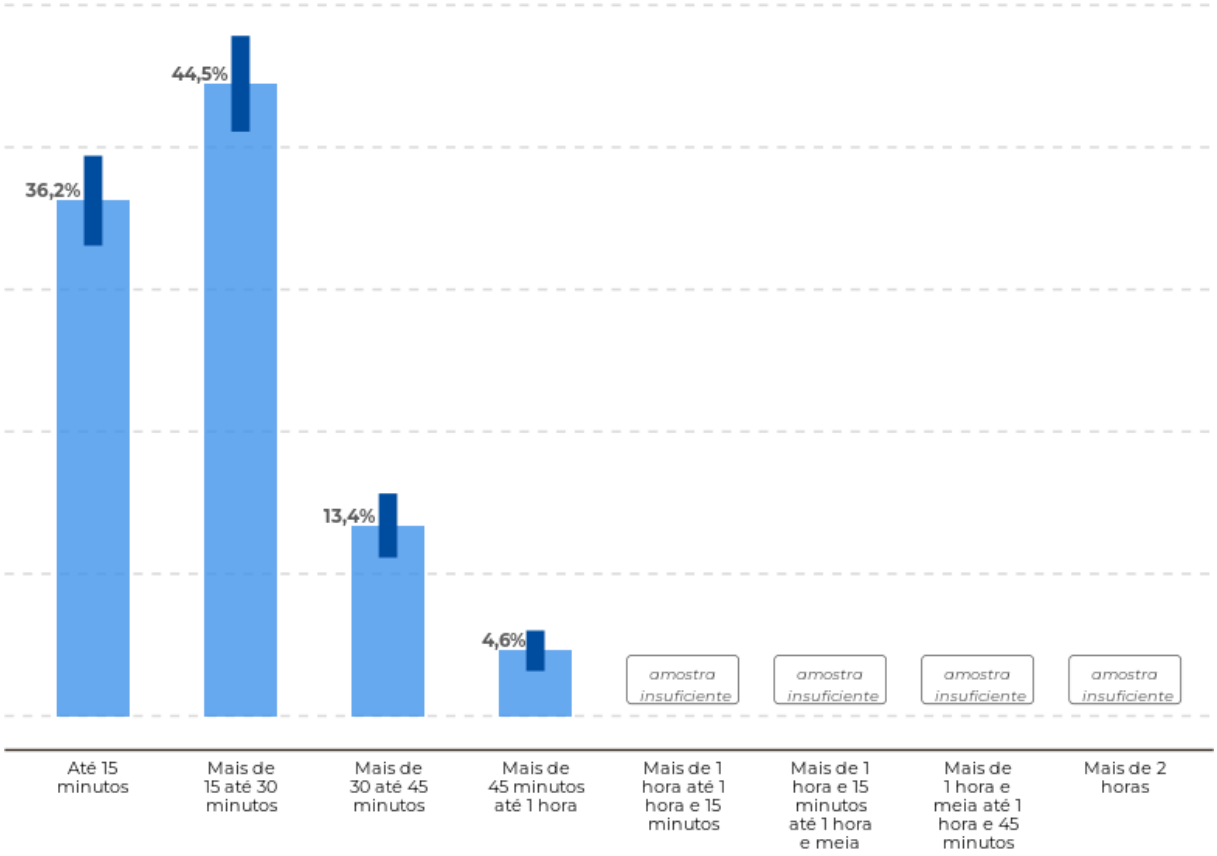

Fonte: CODEPLAN/DIEPS/GEREPS/PDAD 2021

Sobre a formalização dos assalariados privados, 84,8% informaram ter carteira de trabalho assinada pelo atual empregador[42]. Sobre a cobertura da previdência social pública (INSS), 89,9% dos assalariados privados declararam fazer contribuição[43] (Figura 3.6.10 e Tabelas A.65 e A.66).

Figura 3.6.10: Distribuição dos assalariados privados segundo posse de carteira de trabalho assinada (CTPS) e contribuição ao INSS, Lago Sul, 2021

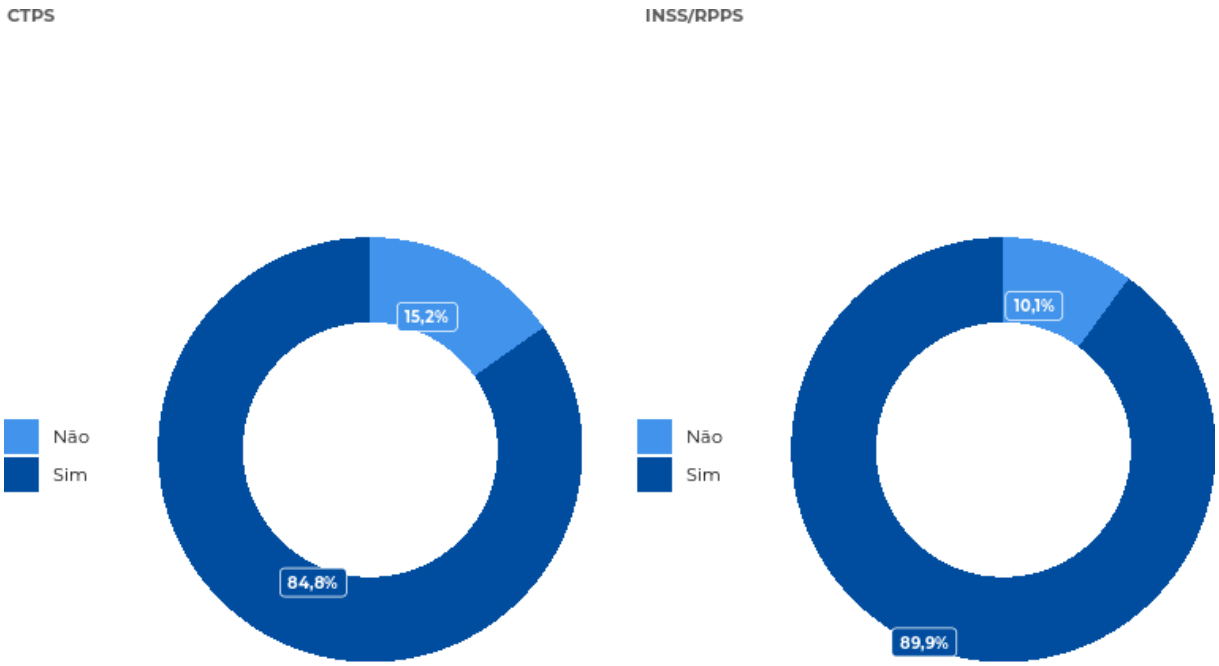

Fonte: CODEPLAN/DIEPS/GEREPS/PDAD 2021

[42] Para este resultado foram desconsideradas as pessoas que não souberam responder e aquelas que disseram não ter carteira assinada por serem funcionários públicos.

[43] Para este resultado foram considerados os empregados no setor privado, trabalhadores domésticos, religiosos remunerados e aprendizes.

3.7 Rendimento

No que diz respeito à remuneração de trabalho principal, o valor[44] médio observado foi de R$ 12.537,62. No que tange à desigualdade, o coeficiente de Gini[45] para esta remuneração foi de 0,39. De modo a ampliar a análise da distribuição desta renda, a Figura 3.7.2 apresenta a curva de Lorenz, que descreve a relação entre a proporção da renda e de pessoas de maneira cumulativa[46].

Já a renda domiciliar[47] estimada foi de R$ 31.322,90, que resulta em um valor médio por pessoa de R$ 10.979,10. Quanto à desigualdade, o índice de Gini da renda domiciliar foi de 0,33, enquanto para a renda por pessoa foi de 0,34 (a Figura 3.7.4 apresenta a curva de Lorenz desta renda).

A Figura 3.7.1 apresenta a distribuição do rendimento bruto do trabalho principal por faixas de salário mínimo (considerando o valor de 2021, de R$ 1.100,00), enquanto a Figura 3.7.3 apresenta a renda domiciliar para estas mesmas faixas. Essas informações estão também nas Tabelas A.61 e A.68, respectivamente.

[44] Todos valores monetários foram corrigidos pelo Índice Nacional de Preços ao Consumidor Amplo – IPCA, de Brasília, calculado pelo IBGE, tendo como referência o mês de julho de 2021.

[45] O coeficiente de Gini é uma medida de desigualdade que varia entre 0 e 1, em que o valor nulo indica igualdade total e o valor unitário indica desigualdade total.

[46] Em caso de uma distribuição perfeitamente igualitária, a "curva" de Lorenz seria coincidente com a linha de 45°. Assim, quanto maior a convexidade da curva, maior a desigualdade.

[47] A renda domiciliar foi calculada da seguinte maneira: caso algum membro do domicílio se recusasse a informar o valor de algum rendimento questionado (trabalho, aposentadoria, pensões, benefícios sociais ou outros rendimentos), todo o domicílio foi desconsiderado para o cálculo da renda domiciliar. Isso foi feito pois, havendo a recusa da informação por parte de um morador, sabe-se que existe um rendimento no domicílio mas sem ser possível determinar o seu valor, o que afetaria o cômputo do rendimento domiciliar total. Adicionalmente, caso o entrevistado não soubesse informar o rendimento do trabalho, o domicílio também foi excluído do cálculo. Como a renda do trabalho é a fonte de rendimento mais comum dos domicílios, a falta desta informação poderia subestimar muito os valores médios estimados. Adicionalmente, foram desconsiderados os rendimentos iguais a zero.

Figura 3.7.1: Distribuição do rendimento bruto do trabalho principal por faixas de salário mínimo, Lago Sul, 2021

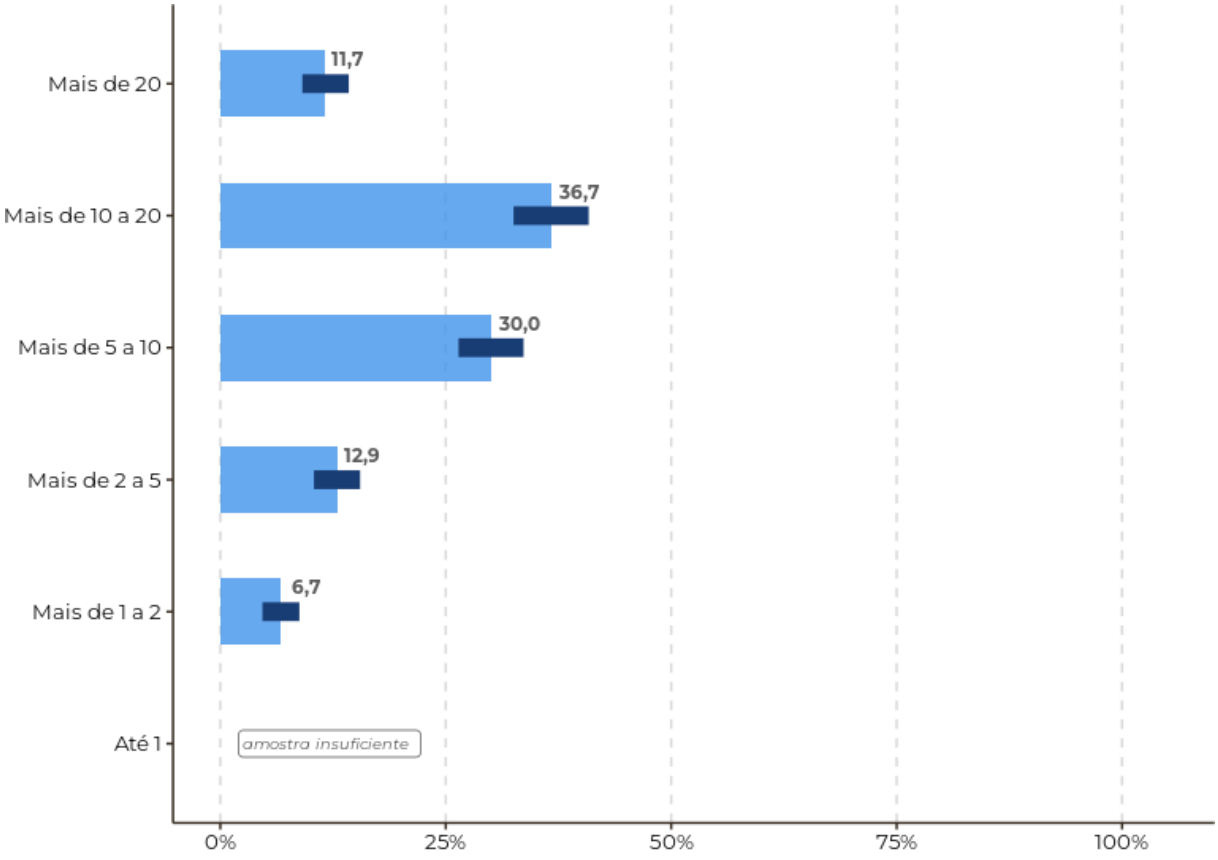

Fonte: CODEPLAN/DIEPS/GEREPS/PDAD 2021
Obs.: Valor do salário mínimo em 2021 era R$ 1.100,00. Valores atualizados pelo IPCA/Brasília.

Figura 3.7.2: Curva de Lorenz do rendimento bruto do trabalho principal, Lago Sul, 2021

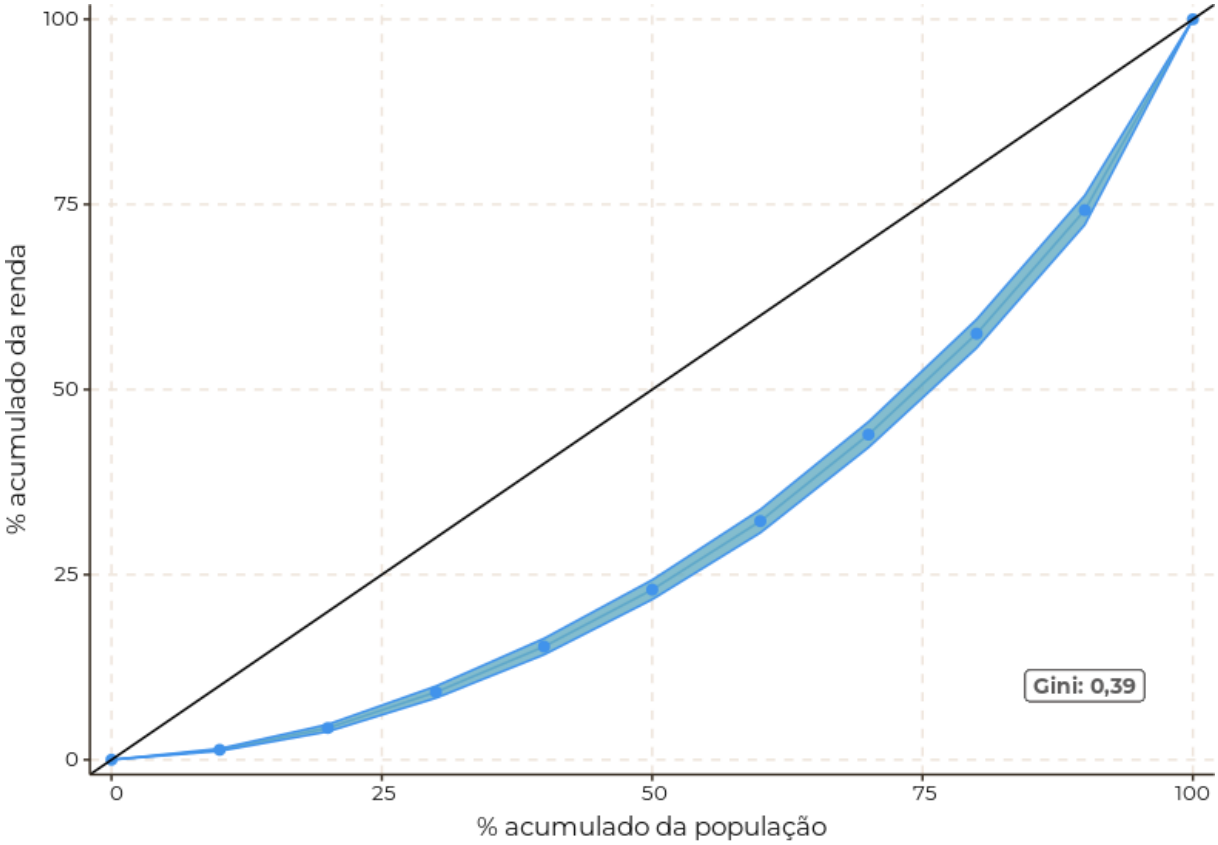

Fonte: CODEPLAN/DIEPS/GEREPS/PDAD 2021
Obs.1: Valores atualizados pelo IPCA/Brasília, R$ de julho de 2021.
Obs.2: Intervalo de confiança na área sombreada.

Figura 3.7.3: Distribuição do rendimento domiciliar por faixas de salário mínimo, Lago Sul, 2021

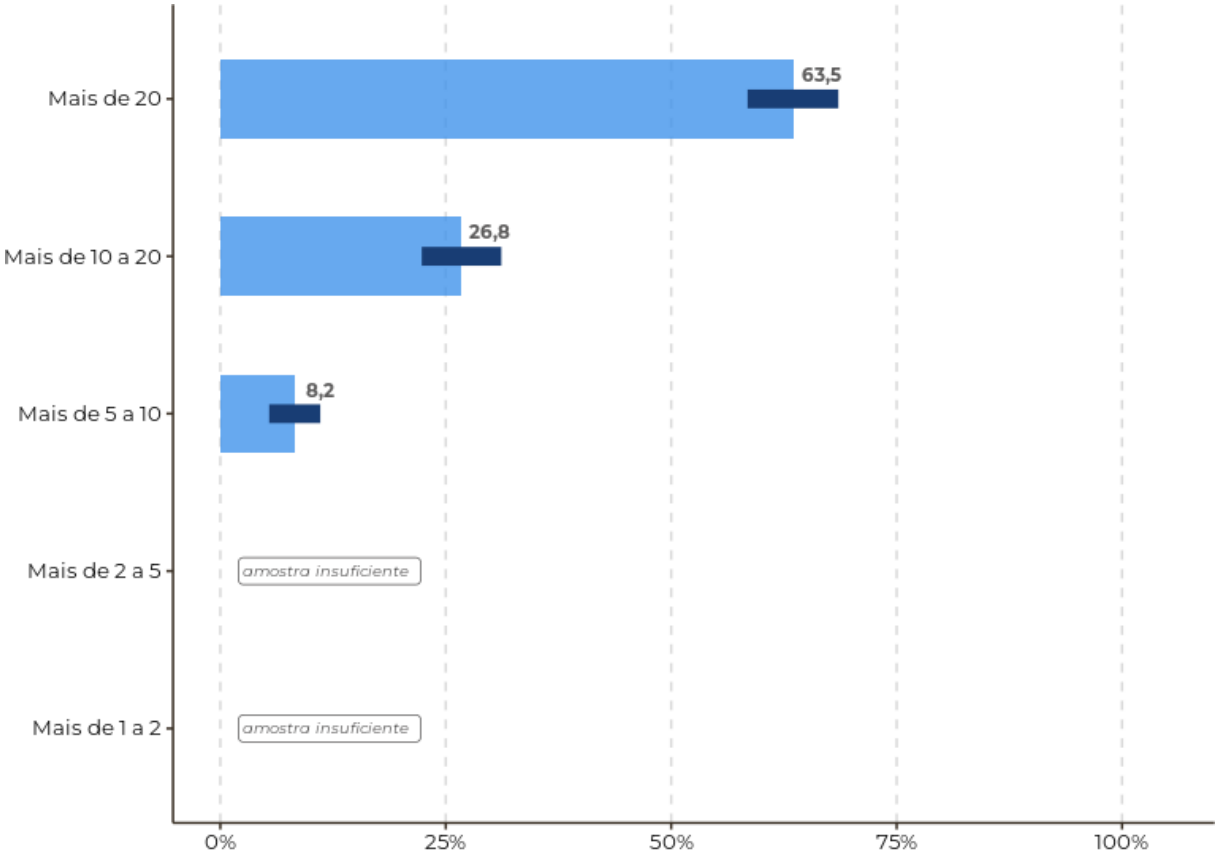

Fonte: CODEPLAN/DIEPS/GEREPS/PDAD 2021
Obs.: Valor do salário mínimo em 2021 era R$ 1.100,00. Valores atualizados pelo IPCA/Brasília.

Figura 3.7.4: Curva de Lorenz do rendimento domiciliar, Lago Sul, 2021

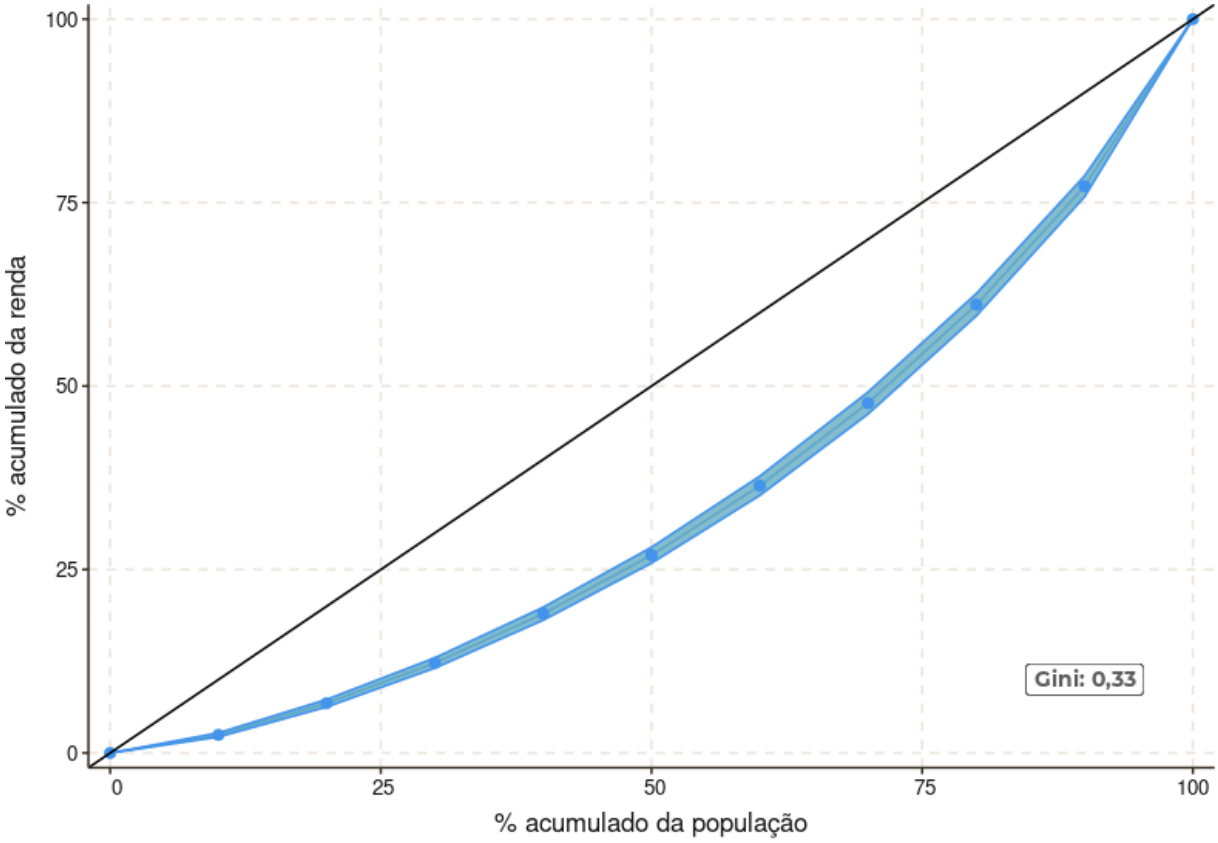

Fonte: CODEPLAN/DIEPS/GEREPS/PDAD 2021
Obs.1: Valores atualizados pelo IPCA/Brasília, R$ de julho de 2021.
Obs.2: Intervalo de confiança na área sombreada.

4 RESULTADOS – DOMICÍLIOS

4.1 Características dos domicílios

A unidade de observação utilizada nesta pesquisa foi o domicílio particular, tendo-se um número estimado de **9.018** unidades ocupadas, com uma média de 3,38 moradores por domicílio. A condição permanente foi observada em 98,3% dos domicílios (Figura 4.1.1 e Tabela A.69).

Figura 4.1.1: Distribuição dos domicílios ocupados segundo a espécie, Lago Sul, 2021

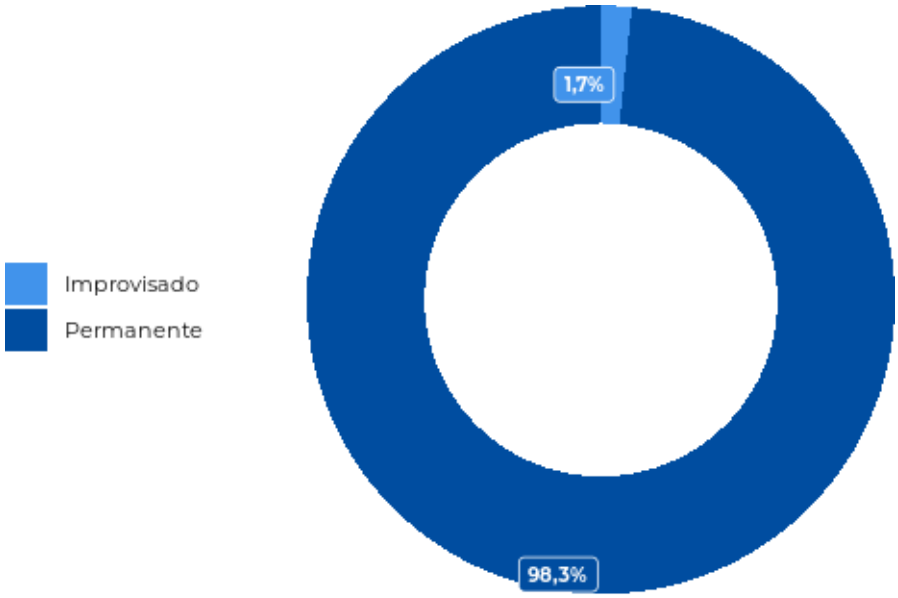

Fonte: CODEPLAN/DIEPS/GEREPS/PDAD 2021

No que diz respeito ao tipo, 83,3% dos domicílios eram casas fora de condomínio (Figura 4.1.2 e Tabela A.70), enquanto a condição de ocupação mais comum era próprio, já pago, para 92,2% (Figura 4.1.3 e Tabela A.71). Por fim, 94,6% dos domicílios próprios possuíam escritura definitiva registrada em cartório, segundo informação dos moradores (Figura 4.1.4 e Tabela A.72).

Figura 4.1.2: Distribuição dos domicílios ocupados segundo o tipo, Lago Sul, 2021

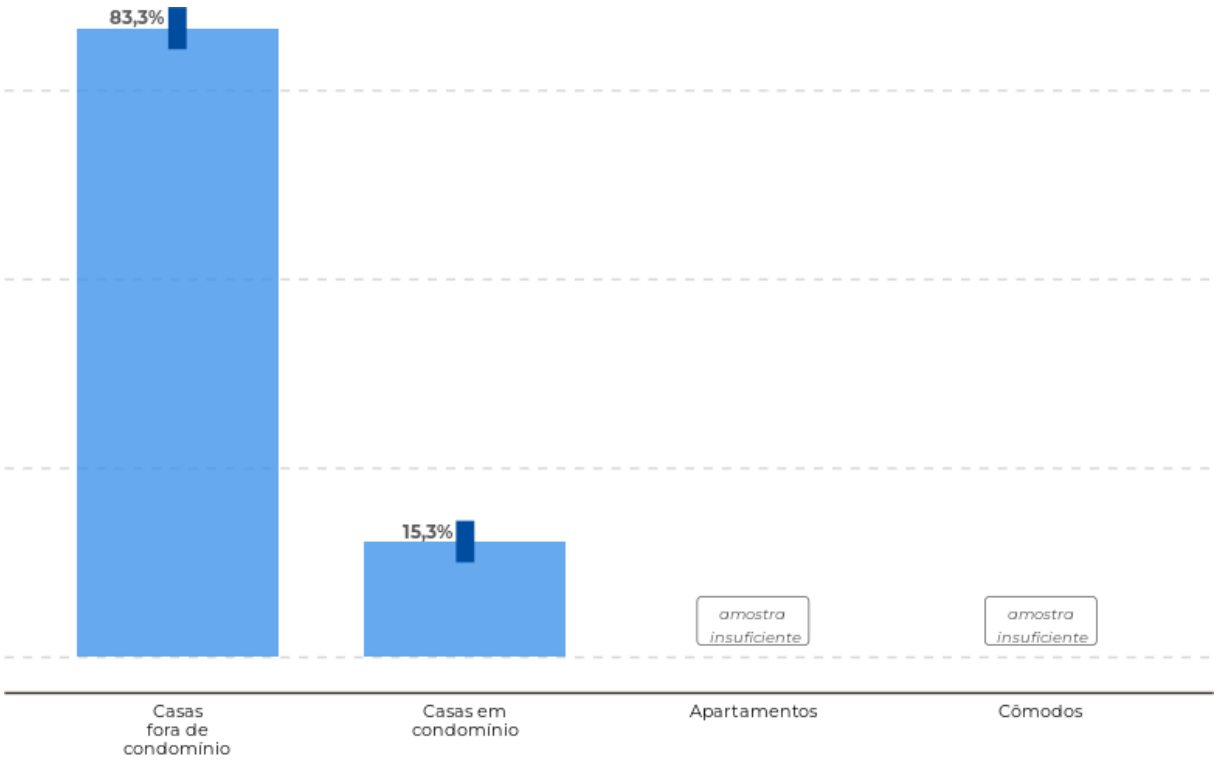

Fonte: CODEPLAN/DIEPS/GEREPS/PDAD 2021

Figura 4.1.3: Distribuição dos domicílios ocupados e próprios segundo a condição de ocupação, Lago Sul, 2021

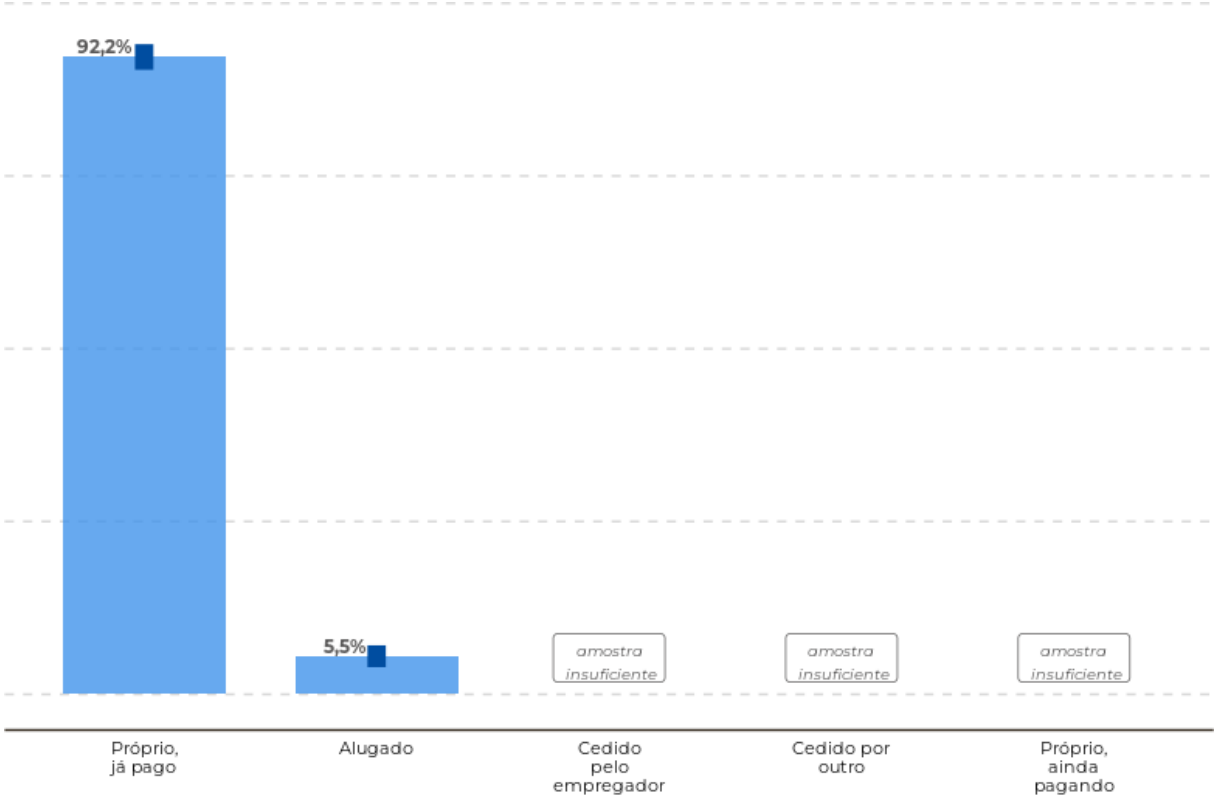

Fonte: CODEPLAN/DIEPS/GEREPS/PDAD 2021

Figura 4.1.4: Distribuição dos domicílios ocupados segundo a regularização do lote, Lago Sul, 2021

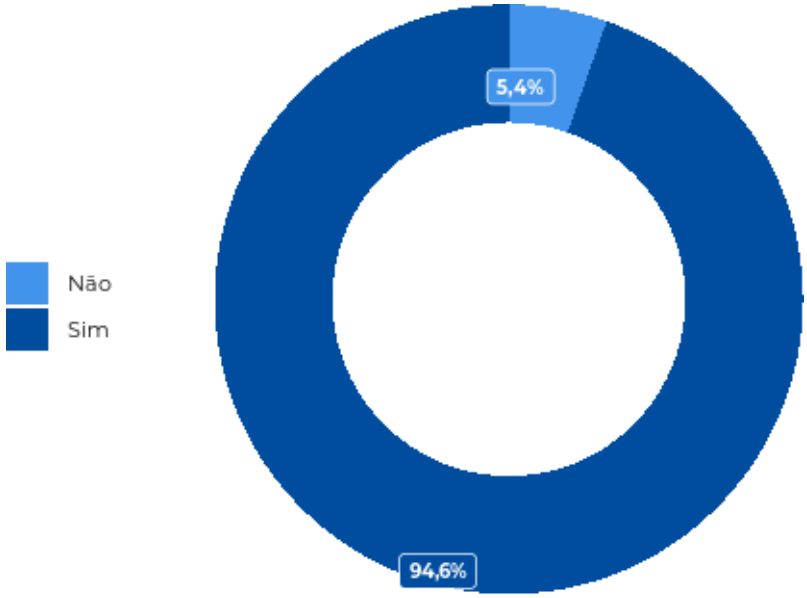

Fonte: CODEPLAN/DIEPS/GEREPS/PDAD 2021

4.2 Infraestrutura domiciliar

Passando para a infraestrutura domiciliar, verificou-se que 99,5% das residências apresentavam parede externa de alvenaria com revestimento (Figura 4.2.1 e Tabela A.73), 98,9% tinham o material do piso de "cerâmica / procelanato / madeira" (Figura 4.2.2 e Tabela A.74), enquanto o telhado era de telha, exceto fibrocimento, com laje em 79,2% dos domicílios (Figura 4.2.3 e Tabela A.75).

Figura 4.2.1: Distribuição dos domicílios ocupados segundo material predominante nas paredes externas, Lago Sul, 2021

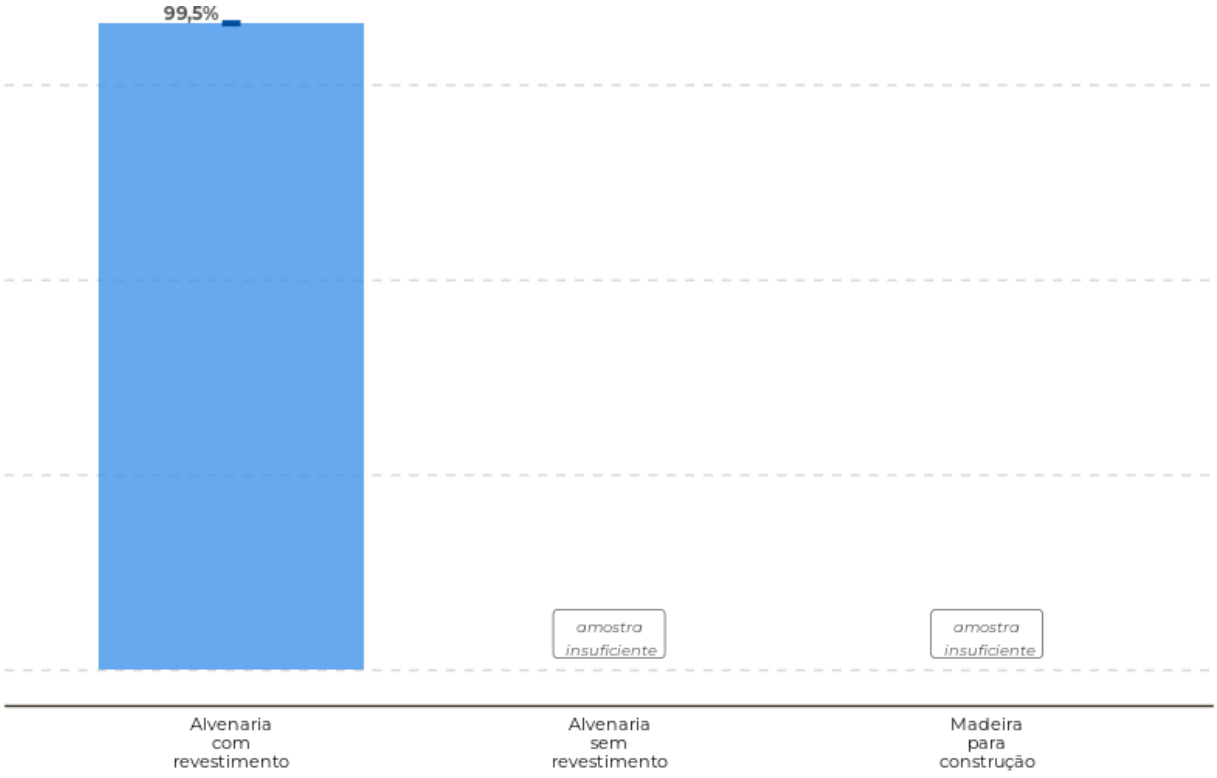

Fonte: CODEPLAN/DIEPS/GEREPS/PDAD 2021

Nos aspectos ligados ao tamanho e à composição dos domicílios, observou-se um número médio de 13,2 cômodos, dos quais 4,3 estavam servindo como dormitório e 4,6 eram banheiros.

Quanto ao abastecimento de água, 99% dos domicílios tinham acesso à rede geral da Companhia de Saneamento Ambiental do Distrito Federal (CAESB) (Figura 4.2.4 e Tabela A.76). Sobre a posse de caixa d'água, 98,6% afirmaram ter este item.

No que diz respeito ao esgotamento sanitário, verificou-se que 93,3% dos domicílios com ligação à rede geral da CAESB , 5,6% declararam ter fossa

Figura 4.2.2: Distribuição dos domicílios ocupados segundo material predominante no piso, Lago Sul, 2021

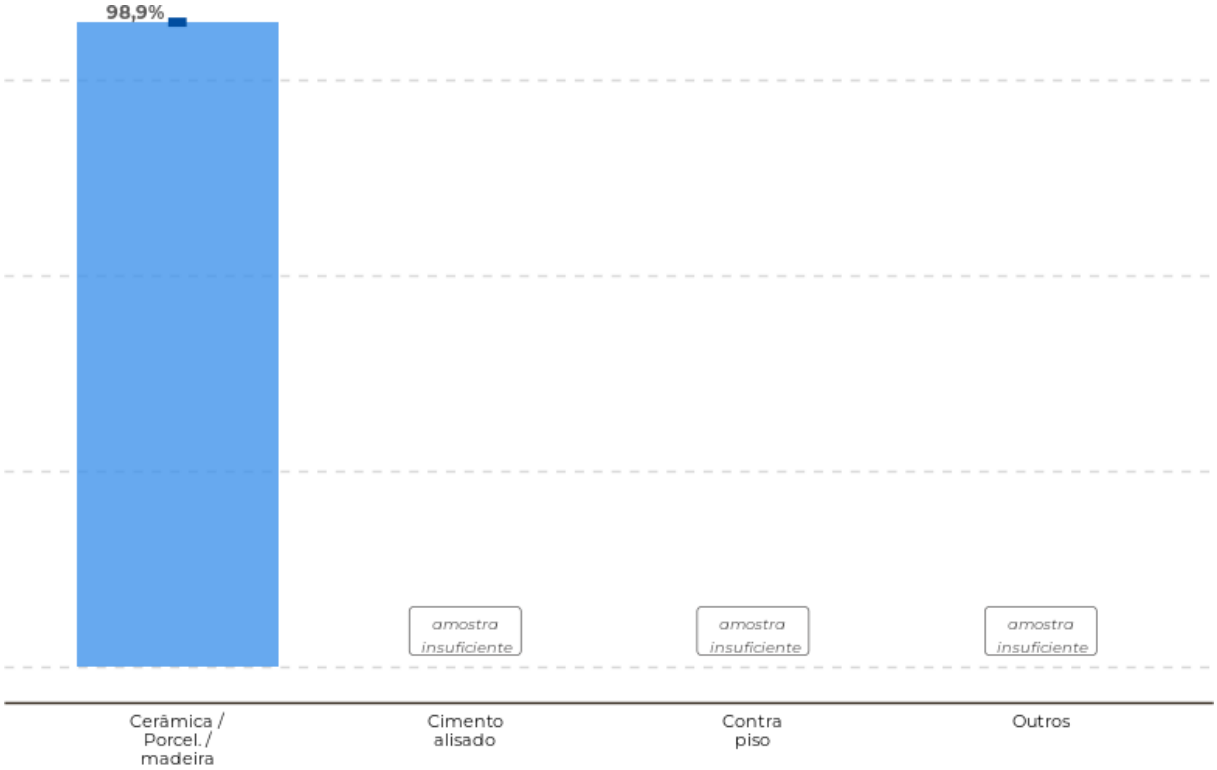

Fonte: CODEPLAN/DIEPS/GEREPS/PDAD 2021

Figura 4.2.3: Distribuição dos domicílios ocupados segundo material predominante na cobertura (telhado), Lago Sul, 2021

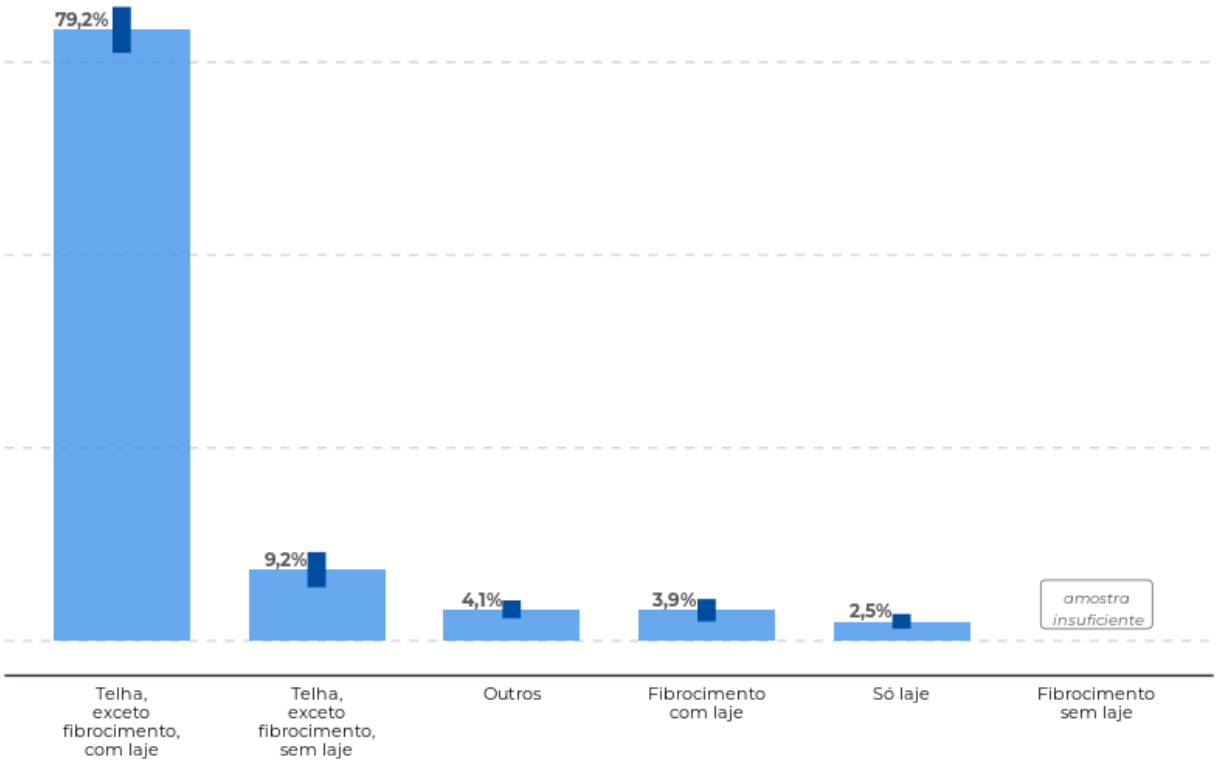

Fonte: CODEPLAN/DIEPS/GEREPS/PDAD 2021

Figura 4.2.4: Abastecimento de água no domicílio, Lago Sul, 2021

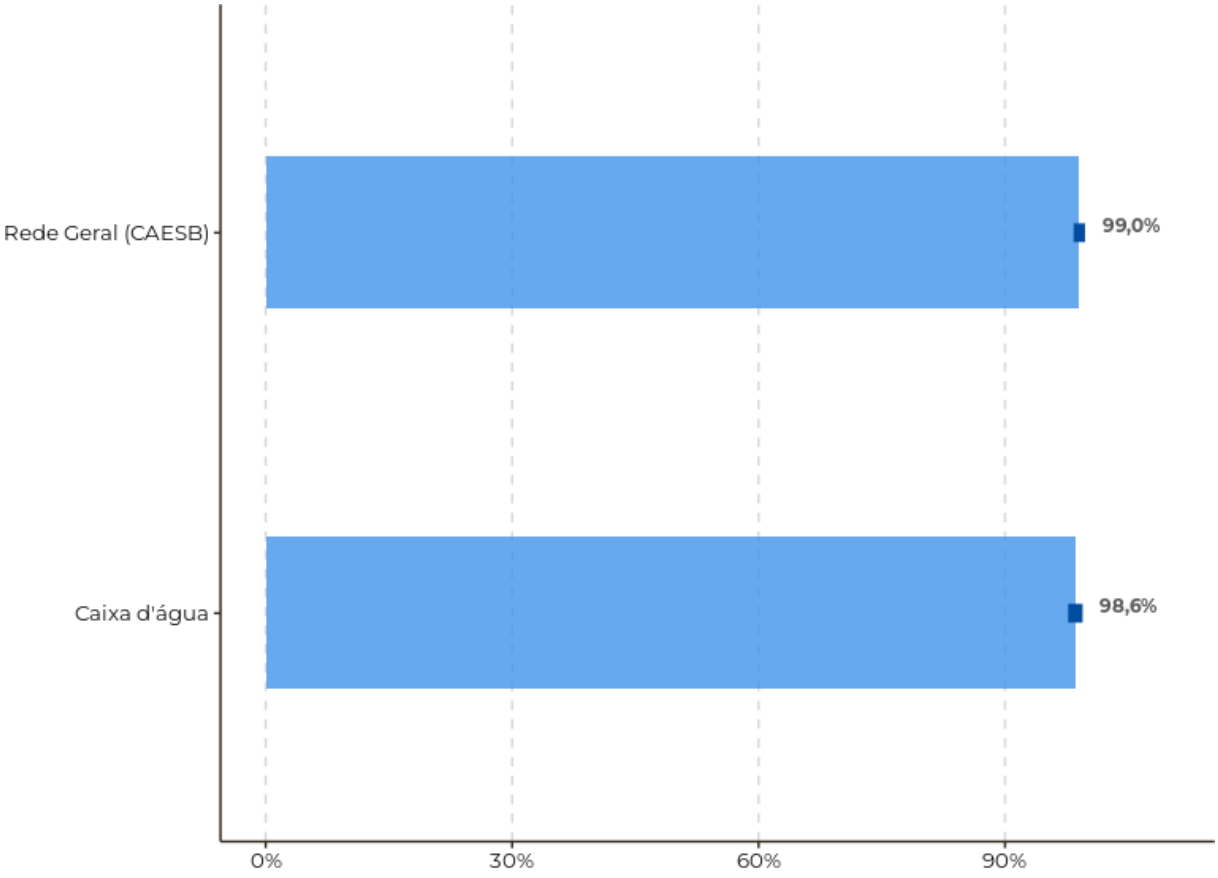

Fonte: CODEPLAN/DIEPS/GEREPS/PDAD 2021

séptica, 1,7% tinham fossa rudimentar (Figura 4.2.5 e Tabela A.77).

Figura 4.2.5: Esgotamento sanitário do domicílio, Lago Sul, 2021

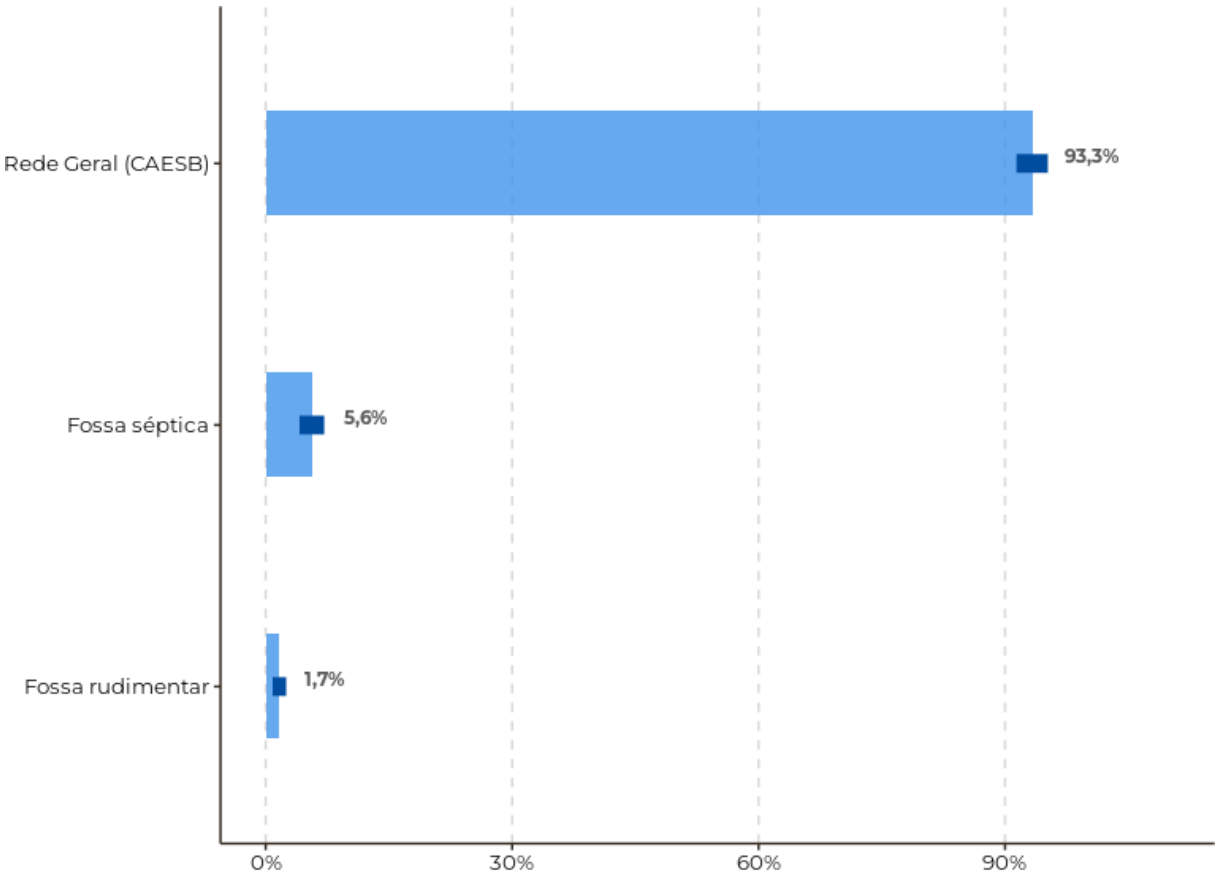

Fonte: CODEPLAN/DIEPS/GEREPS/PDAD 2021

Sobre o abastecimento de energia elétrica, 100% declararam possuir abastecimento da rede geral da Companhia Energética de Brasília (CEB/Neoenergia)[48], 3,1% utilizavam geradores solares (Figura 4.2.6 e Tabela A.78).

No que diz respeito ao recolhimento de lixo, 98,6% afirmaram ter coleta direta[49], sendo 82,8% seletiva e 98,6% não seletiva, 84,9% tinham coleta indireta. Além disso, 93,9% faziam a separação do lixo no domicílio, entre orgânico e reciclável (Figura 4.2.7 e Tabela A.79).

[48] Em março de 2021 o grupo Neoenergia assumiu as operações da CEB, mudando o seu nome para Neoenergia Distribuição Brasília em 21 de abril do mesmo ano.
[49] Um domicílio pode ter tanto coleta direta seletiva quanto coleta direta não-seletiva.

Figura 4.2.6: Abastecimento de energia elétrica no domicílio, Lago Sul, 2021

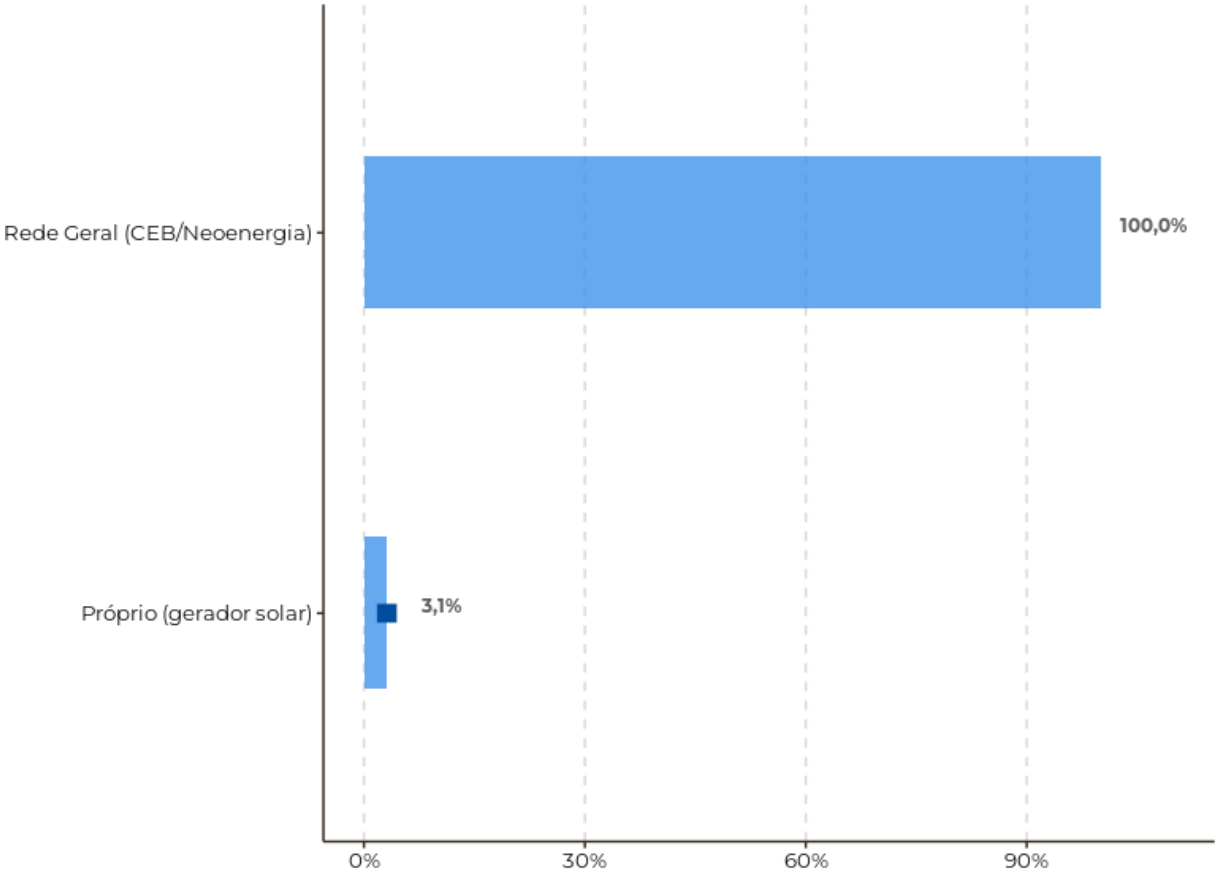

Fonte: CODEPLAN/DIEPS/GEREPS/PDAD 2021

Figura 4.2.7: Recolhimento do lixo no domicílio, Lago Sul, 2021

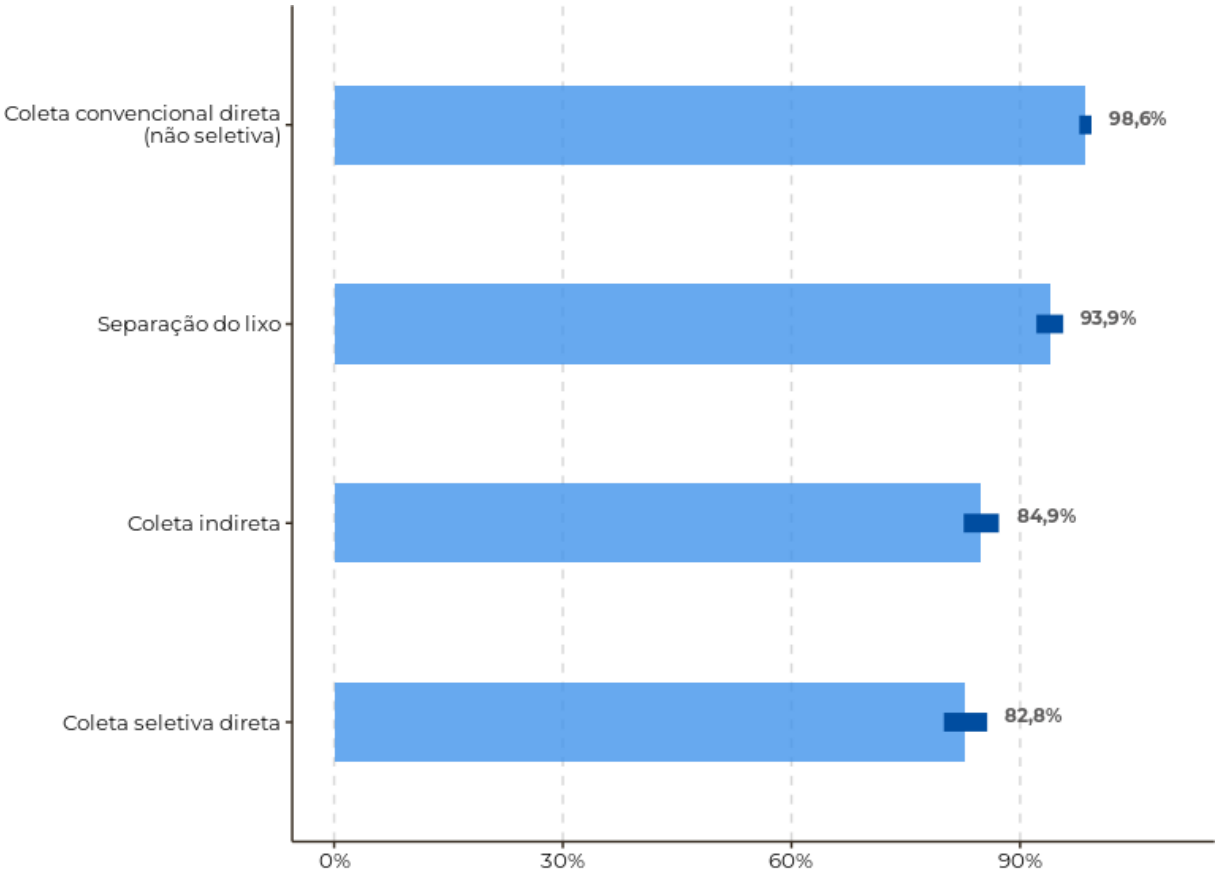

Fonte: CODEPLAN/DIEPS/GEREPS/PDAD 2021

4.3 Infraestrutura urbana nas proximidades dos domicílios

Passando para as questões referentes à infraestrutura urbana existente nas proximidades dos domicílios, verificou-se que a rua de acesso principal ao domicílio era asfaltada em 99,8% das unidades, 99% afirmaram ter calçada, das quais 99,6% tinham meio fio, sendo avaliadas como "boa", segundo 61,2% dos respondentes. Para 99,5% dos entrevistados havia iluminação na rua principal de acesso ao domicílio, enquanto 94,2% responderam que havia drenagem da água da chuva (boca de lobo) (Figura 4.3.1 e Tabela A.80).

Figura 4.3.1: Infraestrutura urbana na rua de acesso dos domicílios, Lago Sul, 2021

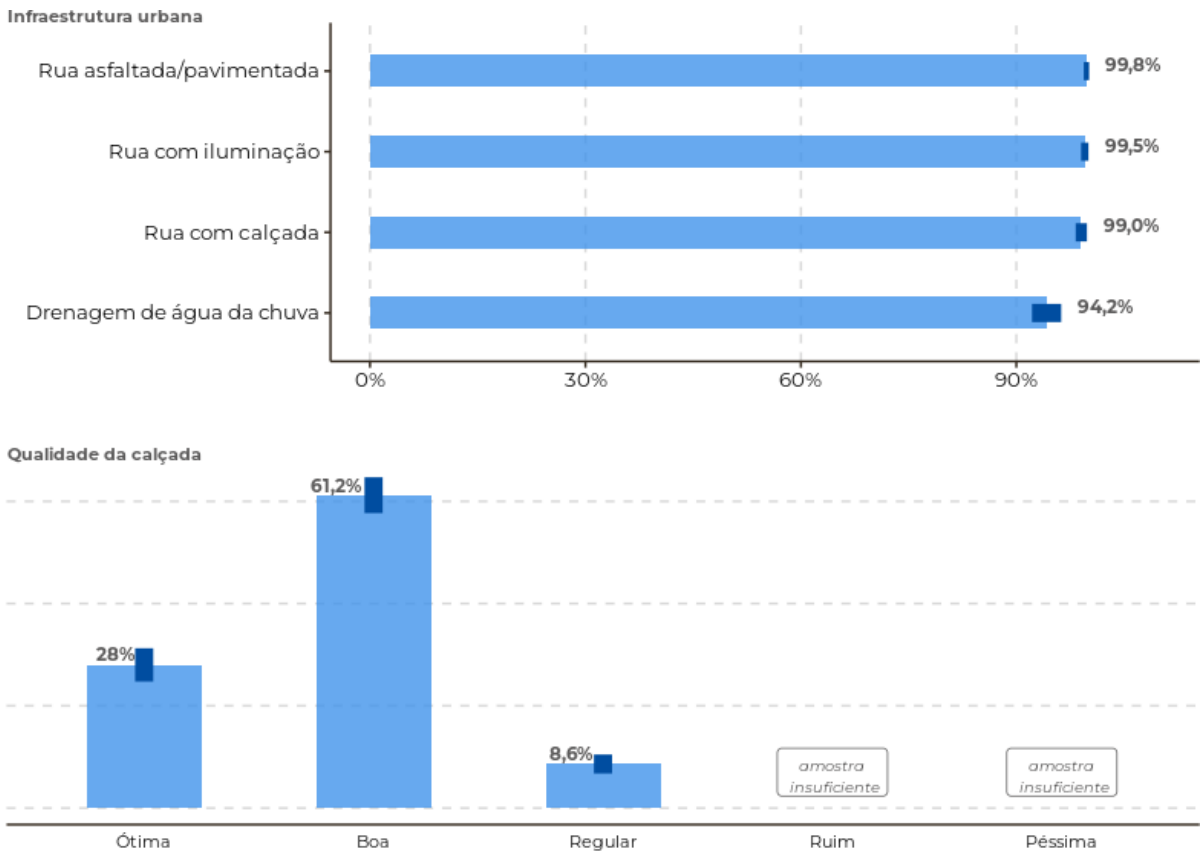

Fonte: CODEPLAN/DIEPS/GEREPS/PDAD 2021

Sobre problemas nas proximidades dos domicílios, 5% informaram que as ruas ficavam alagadas em ocasiões de chuva e 4,4% disseram que ruas próximas eram esburacadas (Figura 4.3.2 e Tabela A.82).

Sobre infraestrutura pública nas proximidades dos domicílios, 88,4% responderam que havia ruas arborizadas, 79,9% responderam que havia jardins e parques, 69,2% responderam que existia praça, 59,8% informaram a existência

Figura 4.3.2: Problemas nas cercanias do domicílio, Lago Sul, 2021

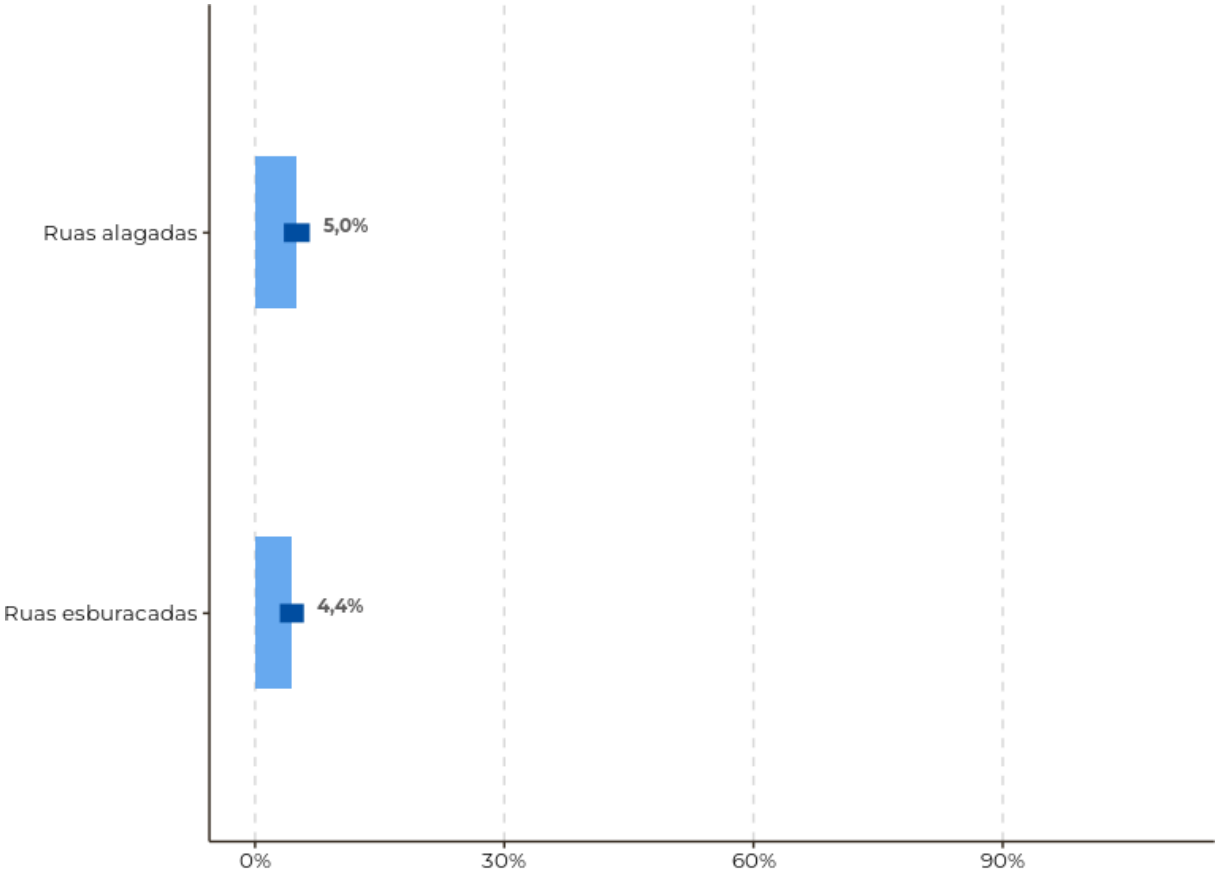

Fonte: CODEPLAN/DIEPS/GEREPS/PDAD 2021

de espaços culturais públicos, 72,4% informaram existiam academias comunitárias (também conhecidos como PEC – Ponto de Encontro Comunitário), 65,8% relataram a existência de quadras esportivas, 74,9% afirmaram haver ciclovia/ciclofaixa, 74,7% relataram existir travessia sinalizada para pedestres (como faixas de pedestre, passarela, passagem subterrânea ou semáforo) e 87,2% disseram existir ponto de ônibus (Figura 4.3.3 e Tabela A.83).

Figura 4.3.3: Infraestrutura urbana nas cercanias do domicílio, Lago Sul, 2021

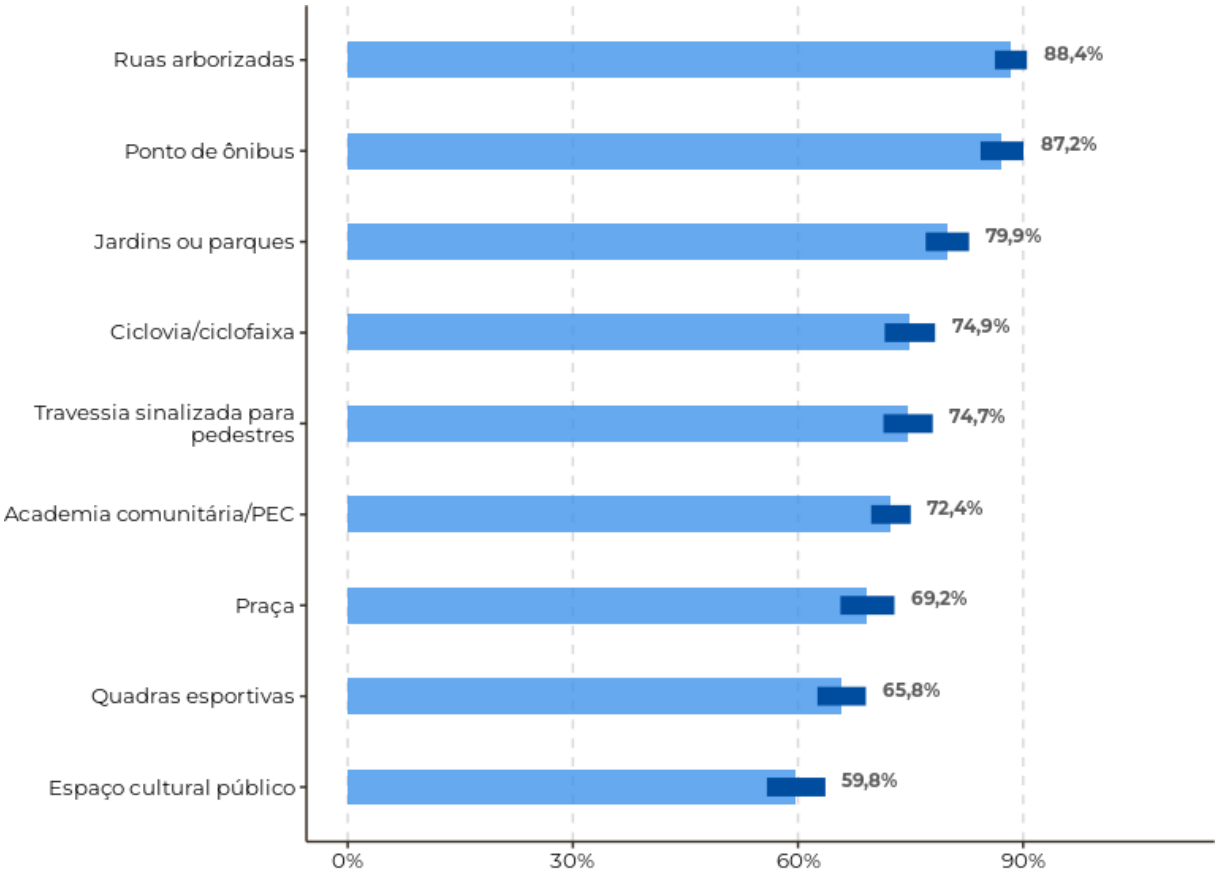

Fonte: CODEPLAN/DIEPS/GEREPS/PDAD 2021

No que tange às questões de segurança, 82,9% afirmaram haver policiamento militar regular, em 88,6% dos domicílios havia equipamento ou dispositivo de segurança particular e em 76,3% havia tais serviços compartilhados com mais domicílios (como portarias, sistemas de segurança de condomínio, servidos de ronda etc.) (Figura 4.3.4 e Tabela A.84).

Figura 4.3.4: Segurança nas proximidades do domicílio, Lago Sul, 2021

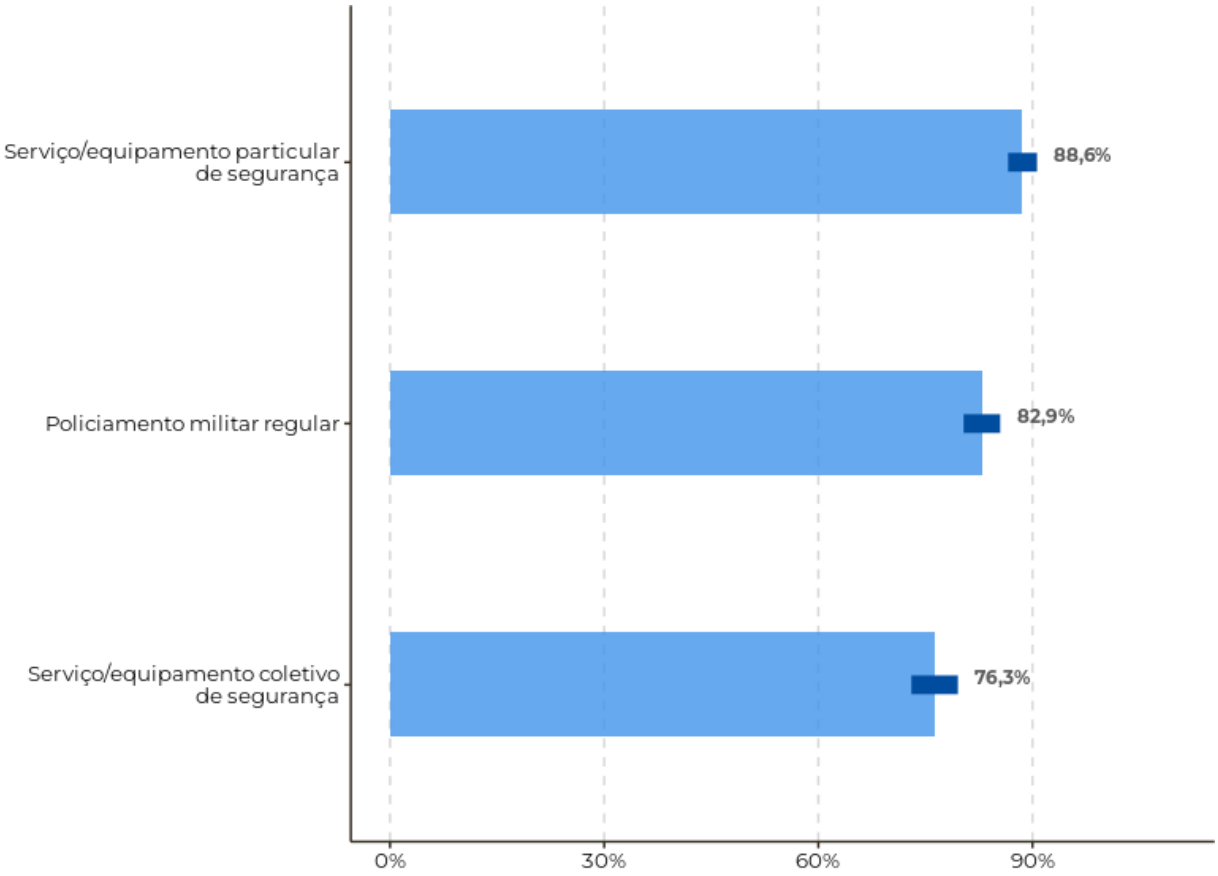

Fonte: CODEPLAN/DIEPS/GEREPS/PDAD 2021

4.4 Serviços domiciliares e inventário de bens duráveis

Uma importante característica que permite avaliar a capacidade de consumo das unidades domiciliares é a contratação de serviços domiciliares e a posse de bens duráveis. Assim sendo, este bloco é dedicado a investigar essas questões. Em 89,7% havia assinatura serviços on-line, como filmes, músicas, notícias, cursos, esportes etc., enquanto em 76% dos domicílios havia serviço de TV por assinatura, e 22,4% assinavam revistas ou jornais impressos (Figura 4.4.1 e Tabela A.85).

Figura 4.4.1: Contratação de serviços pelos domicílios, Lago Sul, 2021

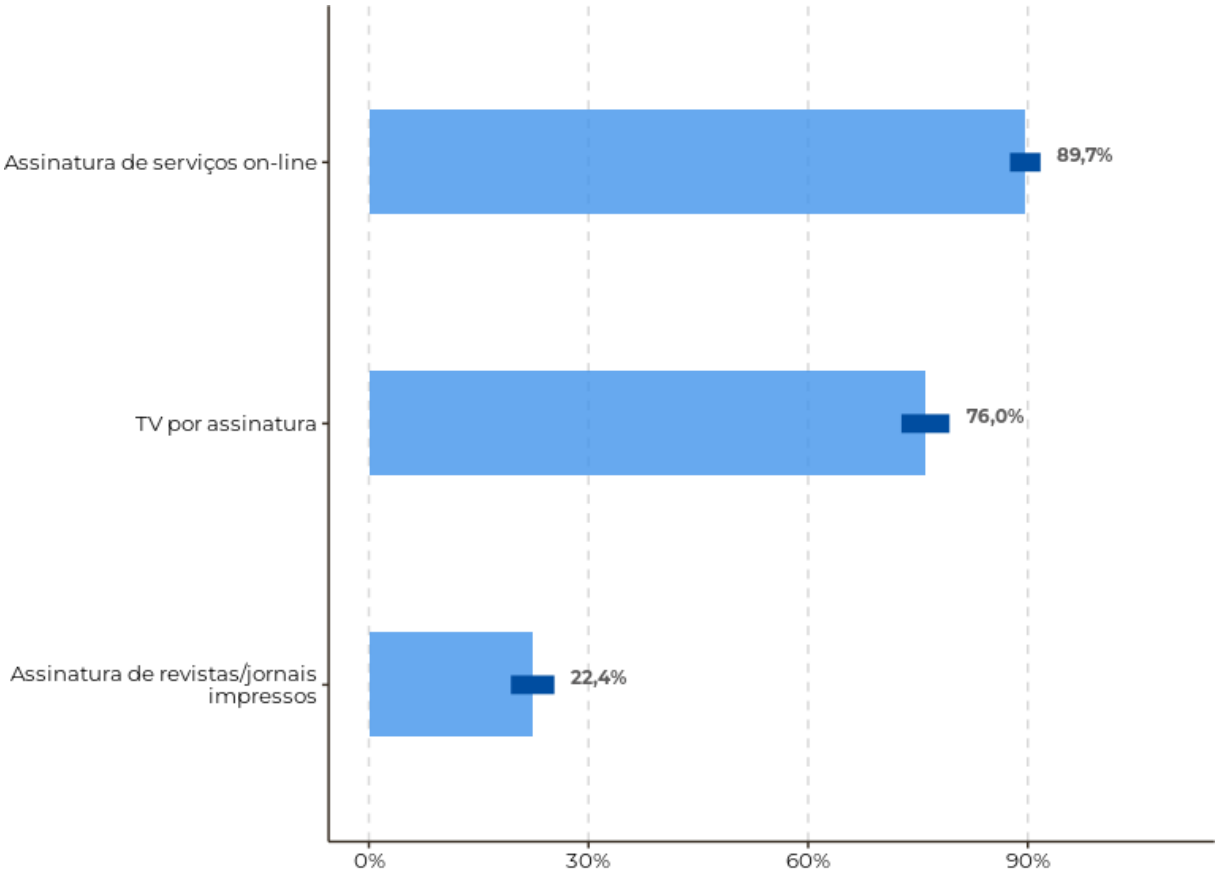

Fonte: CODEPLAN/DIEPS/GEREPS/PDAD 2021

Sobre internet, 100% possuíam acesso[50], sendo que 99,9% do acesso era realizado por meio próprio (Figura 4.4.2 e Tabela A.86).

No que diz respeito à posse de veículos, 99,4% dos entrevistados declararam possuir automóvel, 13,5% informaram ter motocicleta e 53,2% disseram possuir bicicleta (Figura 4.4.3 e Tabela A.88).

[50] Pelo menos um morador do domicílio tinha acesso à internet, seja esta fixa ou móvel.

Figura 4.4.2: Modalidades de acesso à internet no domicílio, Lago Sul, 2021

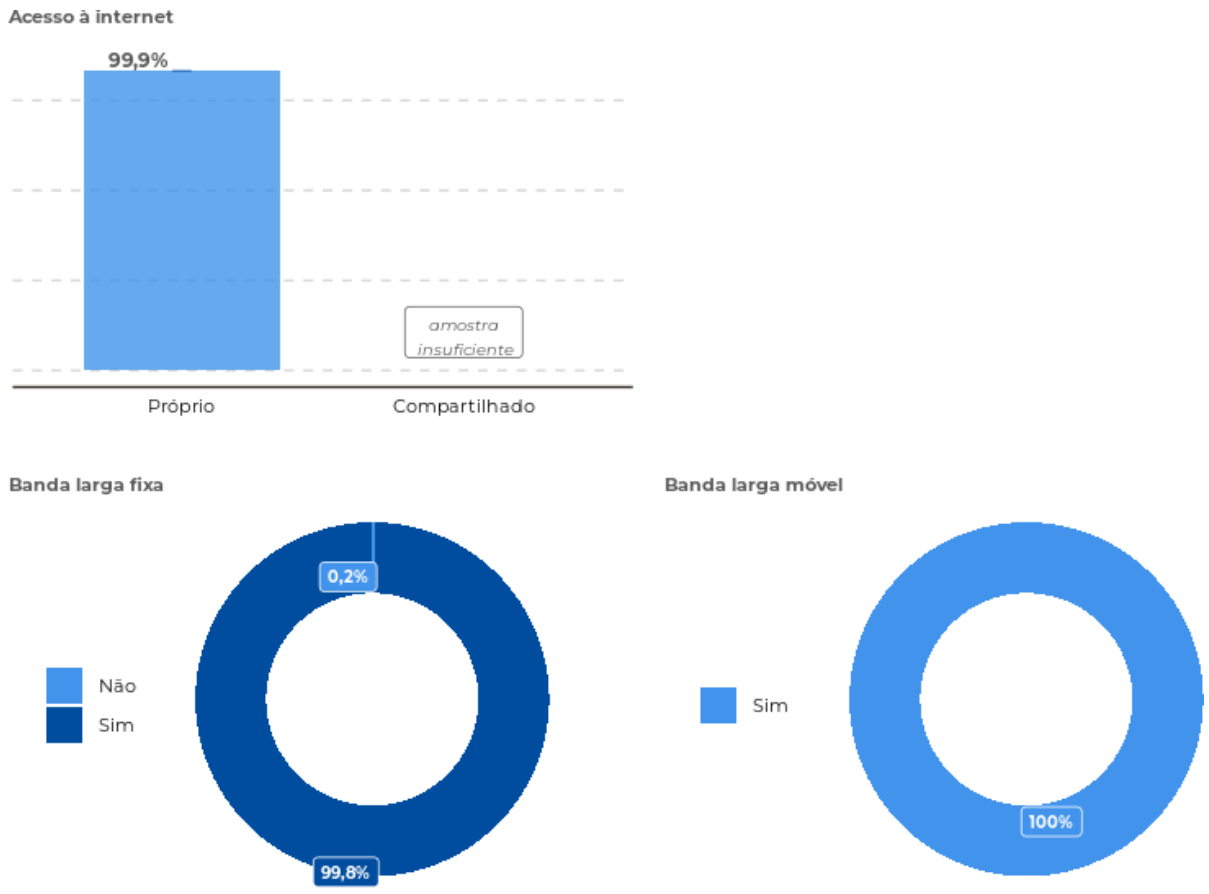

Fonte: CODEPLAN/DIEPS/GEREPS/PDAD 2021

Figura 4.4.3: Posse de veículos no domicílio, Lago Sul, 2021

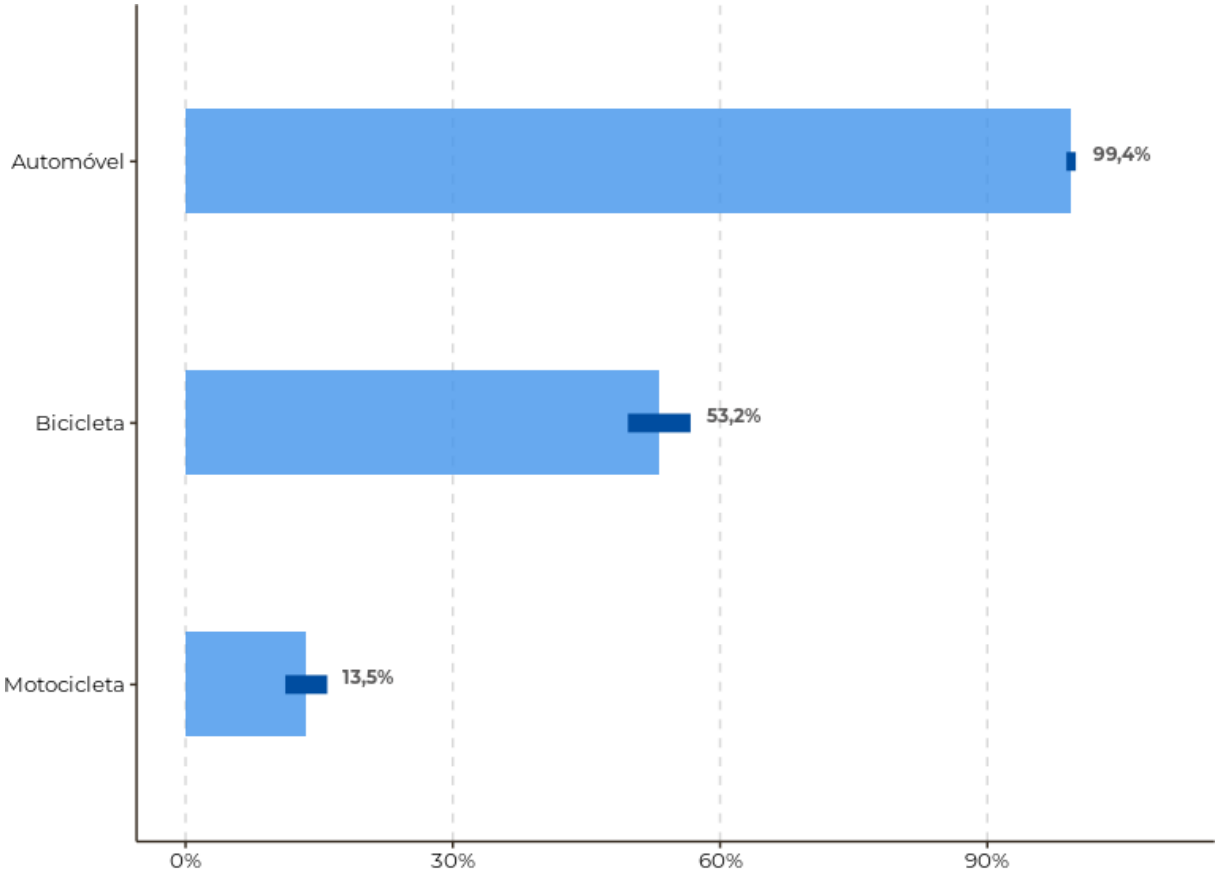

Fonte: CODEPLAN/DIEPS/GEREPS/PDAD 2021

Sobre a posse de eletrodomésticos, observou-se que 100% dos domicílios tinham pelo menos um fogão, 97,8% tinham micro-ondas, 39,4% tinham geladeira de uma porta, 84,4% tinham geladeira de duas ou mais portas, 65,4% tinham freezer, 65,1% tinham máquina de lavar roupas, 59,8% tinham máquina de lavar e secar roupas, 31,8% tinham secadora de roupa, 59,3% máquina de lavar louça, 2,8% tinham televisores tubo, 98,9% televisores tela fina/plana, 9,6% tinham reprodutores de DVD e/ou Blu-ray, 56,2% tinham microcomputadores de mesa, 88,9% tinham notebook/laptop, 88,6% tinham ar condicionado, 73,8% tinham circuladores de ar e/ou ventiladores, 47% tinham placas de aquecedor solar e 75,1% tinham telefone fixo (Figura 4.4.4, Figura 4.4.5 e Tabela A.89).

Figura 4.4.4: Inventário de bens duráveis dos domicílios, Lago Sul, 2021

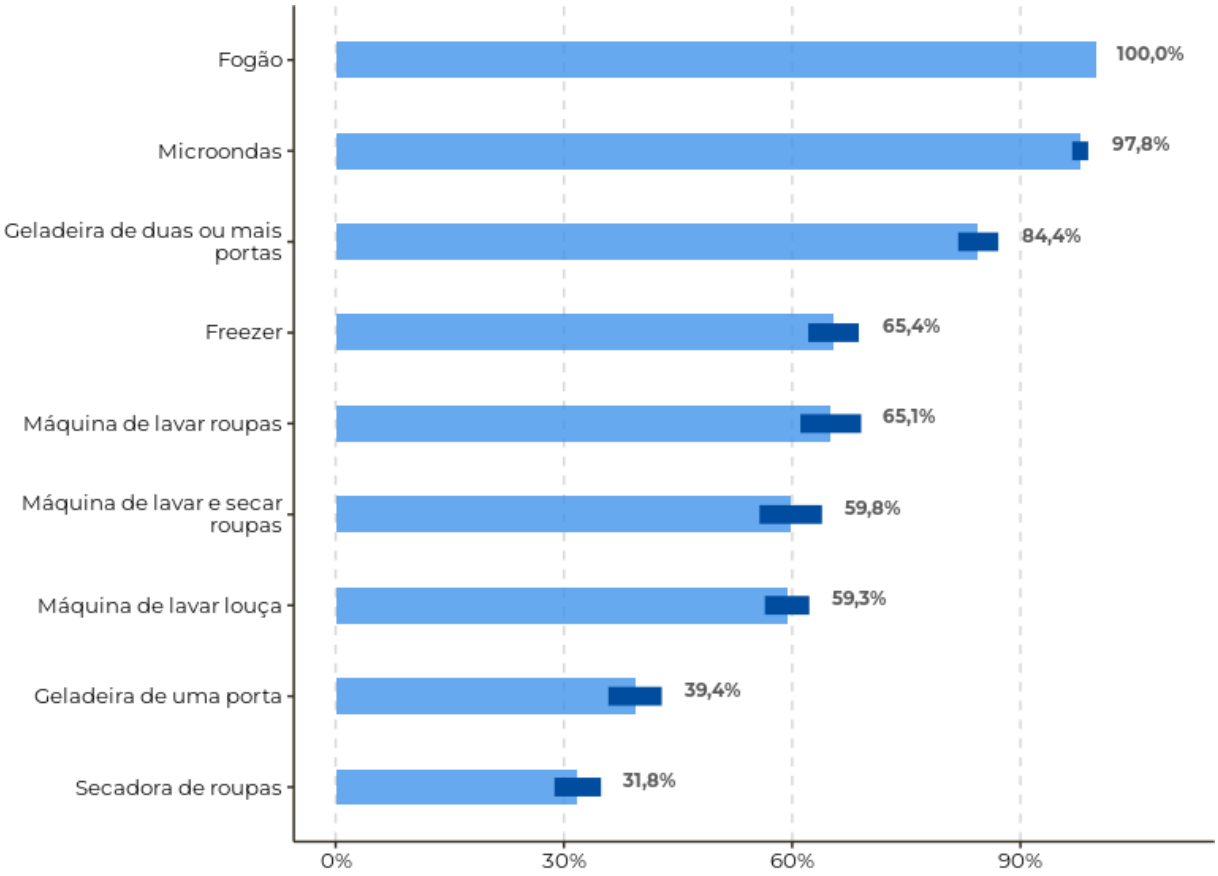

Fonte: CODEPLAN/DIEPS/GEREPS/PDAD 2021

Questionou-se, ainda, a utilização de serviços domésticos. Em 66,1% os respondentes declararam haver a contratação de empregados domésticos, sejam mensalistas ou diaristas (Figura 4.4.6 e Tabela A.90).

Figura 4.4.5: Inventário de bens duráveis dos domicílios (Continuação), Lago Sul, 2021

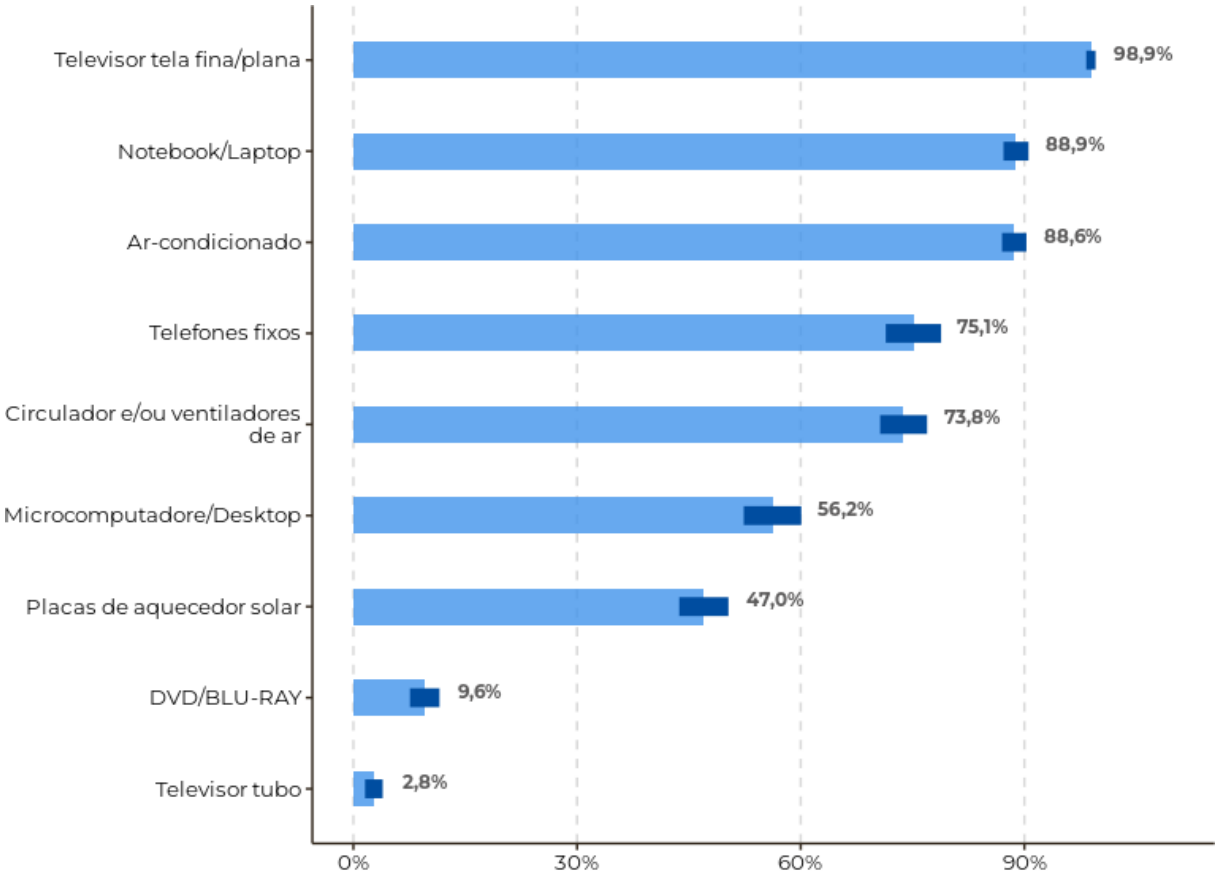

Fonte: CODEPLAN/DIEPS/GEREPS/PDAD 2021

Figura 4.4.6: Utilização de serviços domésticos nos domicílios, Lago Sul, 2021

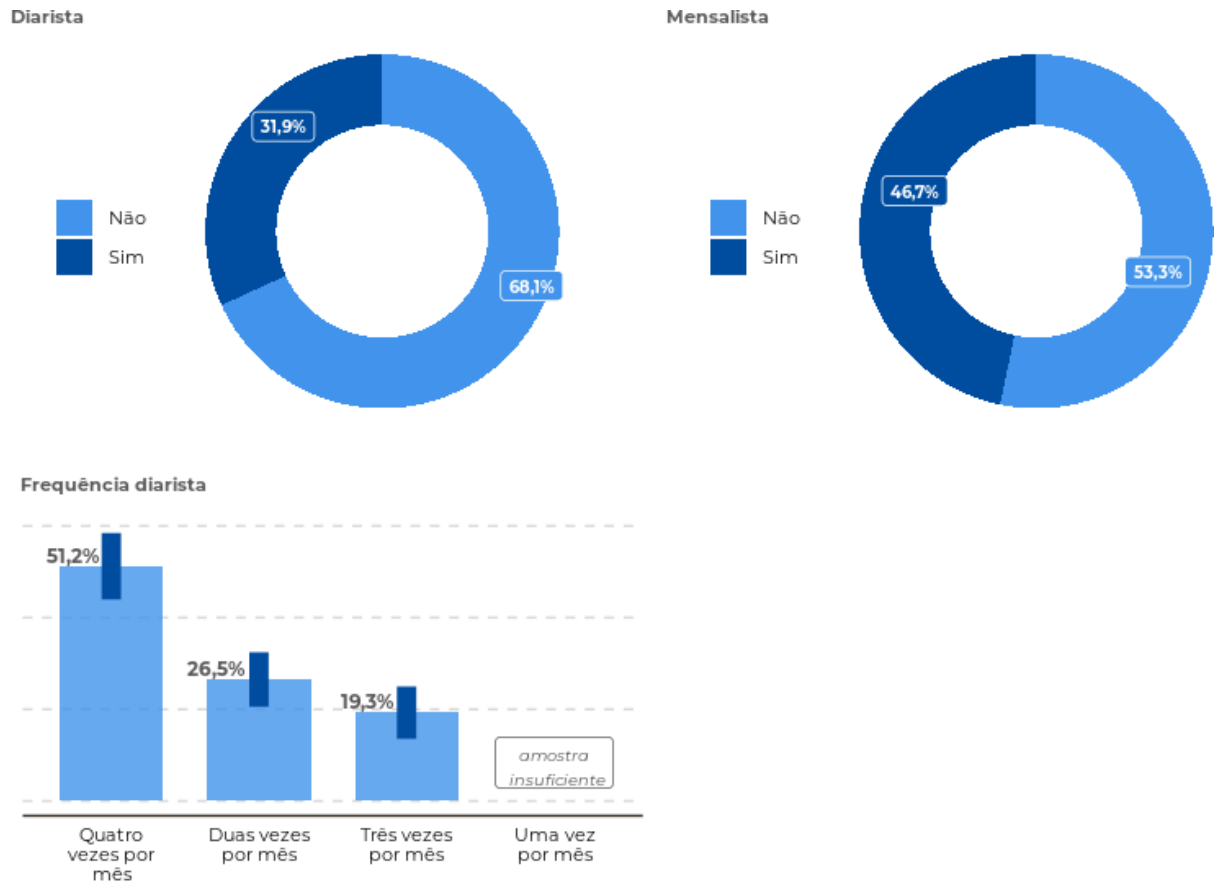

Fonte: CODEPLAN/DIEPS/GEREPS/PDAD 2021

4.5 Localidades predominantes de compras

Nesta edição, a PDAD perguntou quais eram as localidades predominantes de compra de alguns itens de consumo domiciliar[51]. Para alimentação, higiene e limpeza, tendo como referência o último mês a partir da data da entrevista, 78,8% dos respondentes indicaram a RA Lago Sul como a principal localidade. Agora, sempre considerando como referência os últimos doze meses, o principal local de compra de eletrodomésticos foi Lago Sul (42,3%), de materiais de construção ou manutenção foi Lago Sul (57,8%) e de serviços em geral (exceto limpeza doméstica) foi Lago Sul (79,9%).

[51] Foram desconsiderados os domicílios que não efetuaram compras dos itens questionados no período de referência.

Figura 4.5.1: Locais predominantes de compra de artigos de alimentação, higiene e limpeza, eletrodomésticos, material de construção/manutenção e serviços em geral, Lago Sul, 2021

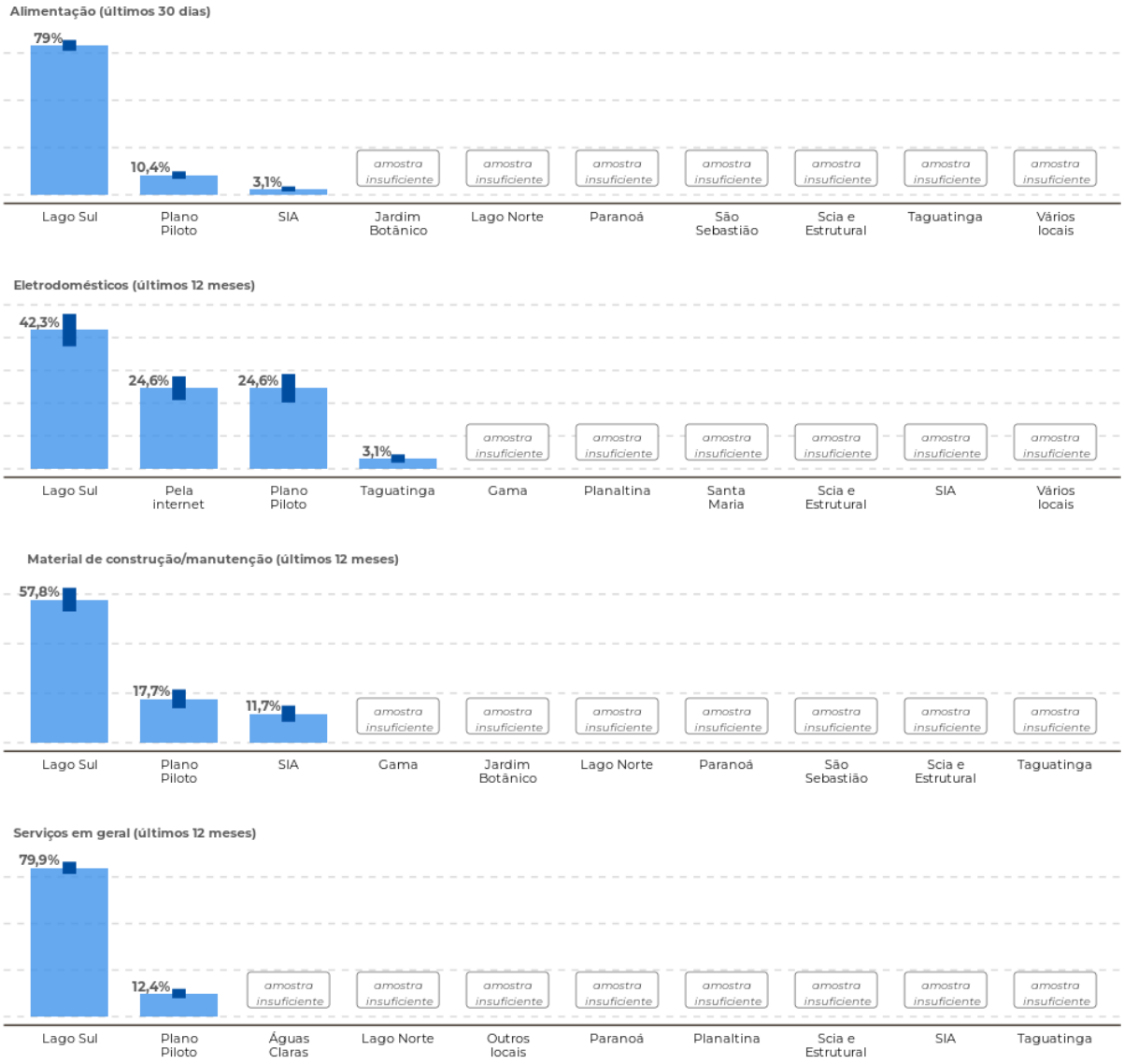

Fonte: CODEPLAN/DIEPS/GEREPS/PDAD 2021
Obs.: São reportadas até o limite das dez maiores categorias.

4.6 Animais de estimação

Outra novidade da PDAD 2021 diz respeito à existência de animais de estimação nos domicílios. Segundo os entrevistados, em 71,5% havia pelo menos um animal de estimação; em 10% havia gato; em 65,9% havia cachorro; em 7,8% havia ave; em 7,7% havia peixe; em 3,8% havia algum outro animal (Figura 4.6.1 e Tabela A.96).

Figura 4.6.1: Existência de gatos, cachorros, aves, peixes ou outros animais domésticos no domicílio, Lago Sul, 2021

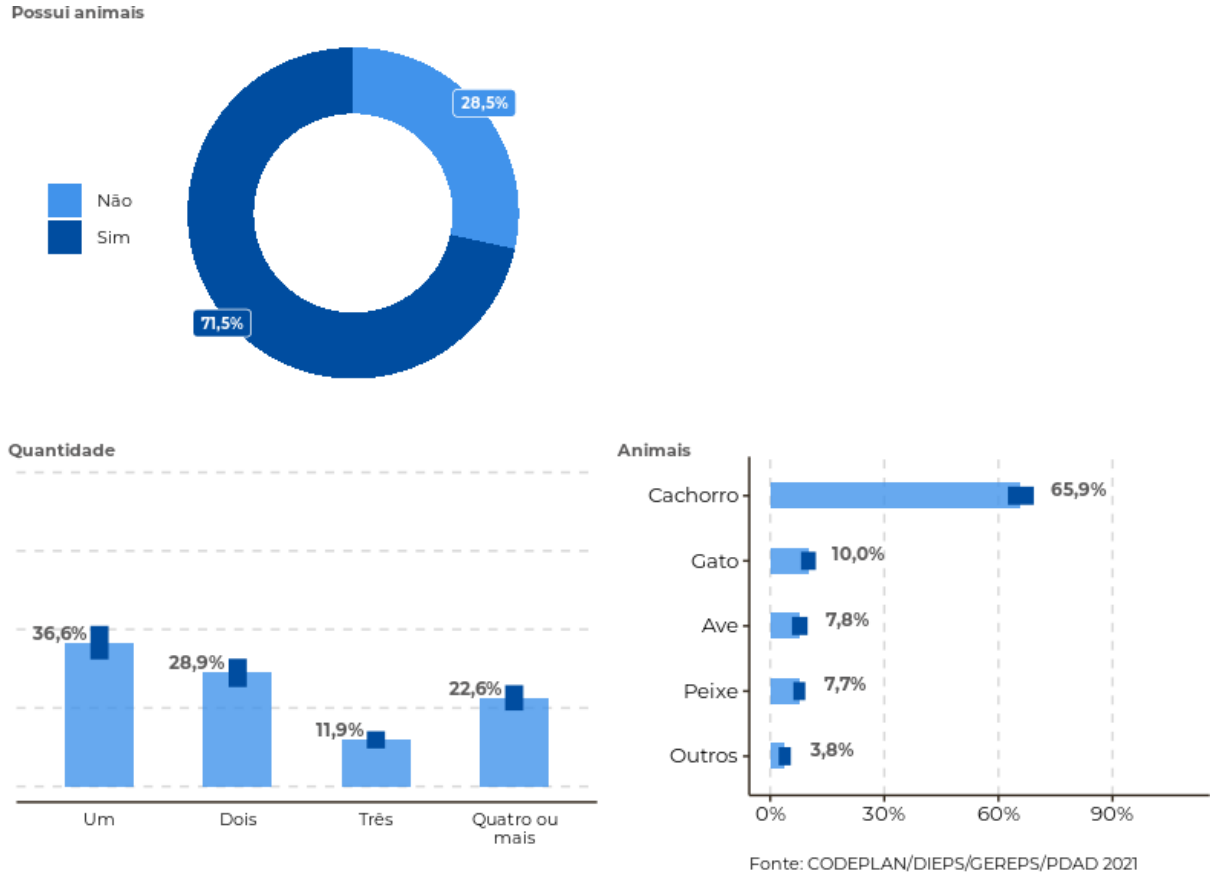

Fonte: CODEPLAN/DIEPS/GEREPS/PDAD 2021

4.7 Segurança alimentar

Para finalizar este capítulo de domicílios, a PDAD 2021 investigou domicílios em situação de insegurança alimentar[52].

A insegurança alimentar foi obtida a partir da aplicação da Escala Brasileira de Insegurança Alimentar (EBIA), uma escala psicométrica que avalia de maneira direta a dimensão de acesso aos alimentos na população, por meio da percepção e experiência com a fome[53]. Trata-se de um indicador originário do indicador Cornell, desenvolvido pela Universidade de Cornell[54].

A EBIA mede diretamente a percepção e vivência de insegurança alimentar e fome no nível domiciliar, captando a dificuldade de acesso familiar aos alimentos e a experiência de vida com a insegurança alimentar e a fome vivenciada nos domicílios[55]. Fornece estimativas da prevalência de insegurança alimentar em diferentes níveis de severidade e sua obtenção está baseada em perguntas sobre comportamentos adotados frente à insuficiência alimentar e a incerteza em relação ao acesso ao alimento.

A insegurança alimentar se divide em três escalas[56]:

- **Insegurança Alimentar leve:** Preocupação ou incerteza quanto acesso aos alimentos no futuro; qualidade inadequada dos alimentos resultante de estratégias que visam não comprometer a quantidade de alimentos;
- **Insegurança Alimentar Moderada:** Redução quantitativa de alimentos entre os adultos e/ou ruptura nos padrões de alimentação resultante da falta de alimentos entre os adultos;

[52] Instituto Brasileiro de Geografia e Estatística (IBGE). Pesquisa Nacional por Amostra de Domicílios – Segurança Alimentar. Rio de Janeiro: IBGE, Diretoria de Pesquisa, Coordenação de Trabalho e Renda; 2006. Disponível em: <http://www.planalto.gov.br/consea/static/documentos/Eventos/IIIConferencia/PNADSegurancaAlimentar2004%20VERS%C3O%20FINAL.pdf>

[53] KEPPLE AW, SEGALL-CORRÊA AM. Conceituando e medindo segurança alimentar e nutricional. Ciência & Saúde Coletiva, 16(1):187-199, 2011.

[54] RADIMER KL, OLSON CM, GREENE JC, CAMPBELL CC, HABICHT J-P. Understanding hunger and developing indicators to assess it in women and children. J Nutr Educ 1992; 24(Suppl.):36-45.

[55] KEPPLE AW, SEGALL-CORRÊA AM. Conceituando e medindo segurança alimentar e nutricional. Ciência & Saúde Coletiva, 16(1):187-199, 2011.

[56] IBGE. Pesquisa de Orçamentos Familiares: 2017-2018. Análise da segurança alimentar no Brasil, 2020

- **Insegurança alimentar grave:** Redução quantitativa de alimentos também entre as crianças, ou seja, ruptura nos padrões de alimentação resultante da falta de alimentos entre todos os moradores, incluindo as crianças. Nessa situação, a fome passa a ser uma experiência vivida no domicílio.

Os resultados apontam que 1,9% estavam nesta situação nos três meses anteriores à data da entrevista, seja esta leve, moderada ou grave (Figura 4.7.1 e Tabela A.97).

Figura 4.7.1: Distribuição dos domicílios por situação de segurança alimentar nos últimos 3 meses, Lago Sul, 2021

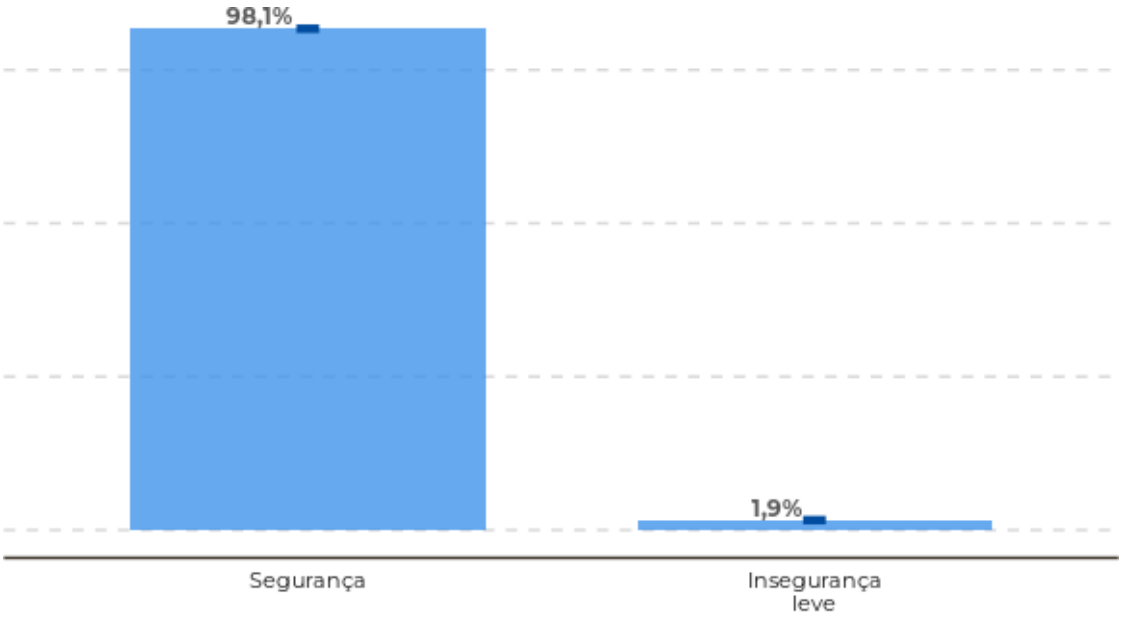

Fonte: CODEPLAN/DIEPS/GEREPS/PDAD 2021

5 CONSIDERAÇÕES FINAIS

Este relatório teve por objetivo apresentar os principais resultados da PDAD 2021. Apesar de ser um relatório amplo, abrangendo a grande maioria das questões investigadas pelo levantamento, ele não foi exaustivo. A riqueza das informações coletadas pela PDAD permite que diversas análises sejam realizadas, sobre os mais variados assuntos, os quais, por limitação de espaço e por objetividade, não puderam ser completamente explorados neste relatório.

Análises mais aprofundadas sobre os diversos temas da PDAD são comumente conduzidas pela própria Codeplan, em estudos específicos, divulgados no site da Companhia. A divulgação da PDAD 2021 permite que tais estudos sejam atualizados, além de possibilitar a realização de novas investigações, uma vez que novos temas foram adicionados nesta edição, como as investigações de identidade de gênero, orientação sexual e insegurança alimentar.

Além disso, a Codeplan disponibiliza os microdados de suas pesquisas em seu site para que a sociedade possa utilizar as informações coletadas da maneira mais ampla possível. Diversas perguntas podem ter suas respostas extraídas deste levantamento, o que faz da PDAD a principal fonte de dados para retratar os aspectos socioeconômicos do Distrito Federal e de suas Regiões Administrativas. Espera-se que essa nova edição da PDAD contribua com o entendimento do nosso território, com a produção de novos conhecimentos que, por seu turno, resultem em ações que melhorem a qualidade de vida da população.

ANEXOS

Tabelas relacionadas aos moradores

Características gerais e de migração

Tabela A.1: População por faixa etária e sexo, Lago Sul, 2021

	Feminino		Masculino	
Resposta	Total	%	Total	%
Total	15.732	51,7	14.714	48,3
até 4 anos	540	47,8	589	52,2
5 a 9 anos	597	47,8	653	52,2
10 a 14 anos	723	48,0	782	52,0
15 a 19 anos	905	47,2	1.012	52,8
20 a 24 anos	940	46,0	1.103	54,0
25 a 29 anos	901	48,9	943	51,1
30 a 34 anos	930	49,9	933	50,1
35 a 39 anos	978	53,8	840	46,2
40 a 44 anos	1.172	55,9	925	44,1
45 a 49 anos	1.274	55,8	1.010	44,2
50 a 54 anos	1.316	53,0	1.165	47,0
55 a 59 anos	1.273	51,0	1.221	49,0
60 a 64 anos	1.071	51,0	1.027	49,0
65 a 69 anos	883	52,9	785	47,1
70 a 74 anos	806	55,8	639	44,2
75 anos ou mais	1.423	56,7	1.087	43,3

Fonte: CODEPLAN/DIEPS/GEREPS/PDAD 2021

Tabela A.2: Arranjos domiciliares, Lago Sul, 2021

Resposta	Total	%
Total	9.018	100,0
Casal com 1 filho	2.406	26,7
Casal sem filhos	2.362	26,2
Casal com 2 filhos	1.985	22,0
Outro perfil	1.014	11,2
Monoparental (feminino)	626	6,9
Casal com 3 filhos ou mais	324	3,6
Unipessoal	302	3,3

Fonte: CODEPLAN/DIEPS/GEREPS/PDAD 2021

Tabela A.3: População por sexo, Lago Sul, 2021

Resposta	Total	%
Total	30.446	100,0
Feminino	15.732	51,7
Masculino	14.714	48,3

Fonte: CODEPLAN/DIEPS/GEREPS/PDAD 2021

Tabela A.4: Identidade de gênero das pessoas com 18 anos ou mais, Lago Sul, 2021

Resposta	Total	%
Total	25.309	100
Cisgênero	25.066	99
Transgênero	242	1

Fonte: CODEPLAN/DIEPS/GEREPS/PDAD 2021

Tabela A.5: Orientação sexual das pessoas com 18 anos ou mais, Lago Sul, 2021

Resposta	Total	%
Total	25.258	100,0
Heterossexual	24.908	98,6
Lésbicas, Gays, Bissexuais e outros	350	1,4

Fonte: CODEPLAN/DIEPS/GEREPS/PDAD 2021

Tabela A.6: População com 18 anos ou mais segundo identificação LGBTQIA+, Lago Sul, 2021

Resposta	Total	%
Total	25.332	100,0
Não LGBTQIA+	24.764	97,8
LGBTQIA+	567	2,2

Fonte: CODEPLAN/DIEPS/GEREPS/PDAD 2021

Tabela A.7: Pessoas com 18 anos ou mais que possuíam CNH, Lago Sul, 2021

Resposta	Total	%
Total	25.266	100,0
Sim	23.409	92,7
Não	1.856	7,3

Fonte: CODEPLAN/DIEPS/GEREPS/PDAD 2021

Tabela A.8: População por raça/cor da pele, Lago Sul, 2021

Resposta	Total	%
Total	30.446	100,0
Branca	20.335	66,8
Parda	9.228	30,3
Preta	729	2,4
Amarela	(***)	(***)
Indígena	(***)	(***)

Fonte: CODEPLAN/DIEPS/GEREPS/PDAD 2021
(***): Estimativa não divulgada por insuficiência de amostra

Tabela A.9: Estado civil das pessoas com 14 anos ou mais de idade, Lago Sul, 2021

Resposta	Total	%
Total	26.759	100,0
Casado	15.541	58,1
Solteiro	8.716	32,6
Viúvo	1.538	5,7
Divorciado	865	3,2
Desquitado ou separado judicialmente	(***)	(***)

Fonte: CODEPLAN/DIEPS/GEREPS/PDAD 2021
(***): Estimativa não divulgada por insuficiência de amostra

Tabela A.10: Pessoas nascidas no DF, Lago Sul, 2021

Resposta	Total	%
Total	30.446	100,0
Outro estado	16.190	53,2
DF	14.256	46,8

Fonte: CODEPLAN/DIEPS/GEREPS/PDAD 2021

Tabela A.11: Estado de nascimento das pessoas que vieram de fora do DF, Lago Sul, 2021

Resposta	Total	%
Total	7.492	100,0
Minas Gerais	1.368	18,3
São Paulo	1.156	15,4
Rio de Janeiro	1.156	15,4
Goiás	611	8,1
Ceará	428	5,7
Bahia	298	4,0
Pará	222	3,0
Acre	(***)	(***)
Alagoas	(***)	(***)
Amapá	(***)	(***)
Amazonas	(***)	(***)
Espírito Santo	(***)	(***)
Maranhão	(***)	(***)
Mato Grosso do Sul	(***)	(***)
Paraíba	(***)	(***)
Paraná	(***)	(***)
Pernambuco	(***)	(***)
Piauí	(***)	(***)
Rio Grande do Norte	(***)	(***)
Rio Grande do Sul	(***)	(***)
Rondônia	(***)	(***)
Roraima	(***)	(***)
Santa Catarina	(***)	(***)
Sergipe	(***)	(***)
Tocantins	(***)	(***)

Fonte: CODEPLAN/DIEPS/GEREPS/PDAD 2021
(***): Estimativa não divulgada por insuficiência de amostra

Tabela A.12: Motivação do chefe do domicílio a mudar e/ou retornar para o DF, Lago Sul, 2021

Resposta	Total	%
Total	3.463	100,0
Acompanhar Parentes / Reunião familiar	1.543	44,5
Trabalho	1.154	33,3
Estudo	324	9,3
Moradia	(***)	(***)
Outros motivos	(***)	(***)
Procura de Trabalho	(***)	(***)
Saúde	(***)	(***)

Fonte: CODEPLAN/DIEPS/GEREPS/PDAD 2021
(***): Estimativa não divulgada por insuficiência de amostra

Tabela A.13: Intenção e localidade para constituição de novo domicílio das pessoas de 14 anos ou mais, Lago Sul, 2021

Resposta	Total	%
Total	1.134	100,0
Plano Piloto	524	46,2
Águas Claras	(***)	(***)
Guará	(***)	(***)
Lago Norte	(***)	(***)
Lago Sul	(***)	(***)
Sudoeste/Octogonal	(***)	(***)
Taguatinga	(***)	(***)

Fonte: CODEPLAN/DIEPS/GEREPS/PDAD 2021
(***): Estimativa não divulgada por insuficiência de amostra

Saúde

Tabela A.14: Pessoas com dificuldade permanente de enxergar, Lago Sul, 2021

Resposta	Total	%
Total	30.008	100,0
Não têm dificuldade	25.436	84,8
Têm alguma dificuldade	4.336	14,5
Têm muita dificuldade	(***)	(***)
Têm, não consegue de modo algum	(***)	(***)

Fonte: CODEPLAN/DIEPS/GEREPS/PDAD 2021
(***): Estimativa não divulgada por insuficiência de amostra

Tabela A.15: Pessoas com dificuldade permanente de ouvir, Lago Sul, 2021

Resposta	Total	%
Total	30.008	100,0
Não têm dificuldade	29.271	97,5
Têm alguma dificuldade	637	2,1
Têm muita dificuldade	(***)	(***)
Têm, não consegue de modo algum	(***)	(***)

Fonte: CODEPLAN/DIEPS/GEREPS/PDAD 2021
(***): Estimativa não divulgada por insuficiência de amostra

Tabela A.16: Pessoas com dificuldade permanente de caminhar ou subir degraus, Lago Sul, 2021

Resposta	Total	%
Total	30.008	100,0
Não têm dificuldade	29.334	97,8
Têm alguma dificuldade	406	1,4
Têm muita dificuldade	(***)	(***)
Têm, não consegue de modo algum	(***)	(***)

Fonte: CODEPLAN/DIEPS/GEREPS/PDAD 2021
(***): Estimativa não divulgada por insuficiência de amostra

Tabela A.17: Pessoas com deficiência mental/intelectual permanente, Lago Sul, 2021

Resposta	Total	%
Total	30.008	100,0
Não têm dificuldade	29.427	98,1
Têm alguma dificuldade	417	1,4
Têm muita dificuldade	(***)	(***)
Têm, não consegue de modo algum	(***)	(***)

Fonte: CODEPLAN/DIEPS/GEREPS/PDAD 2021
(***): Estimativa não divulgada por insuficiência de amostra

Tabela A.18: Pessoas com dificuldade permanente para pegar pequenos objetos, Lago Sul, 2021

Resposta	Total	%
Total	30.008	100,0
Não têm dificuldade	29.310	97,7
Têm alguma dificuldade	502	1,7
Têm muita dificuldade	(***)	(***)
Têm, não consegue de modo algum	(***)	(***)

Fonte: CODEPLAN/DIEPS/GEREPS/PDAD 2021
(***): Estimativa não divulgada por insuficiência de amostra

Tabela A.19: Pessoas com plano de saúde privado, Lago Sul, 2021

Resposta	Total	%
Total	30.382	100,0
Sim	27.714	91,2
Não	2.668	8,8

Fonte: CODEPLAN/DIEPS/GEREPS/PDAD 2021

Tabela A.20: Tipo de plano de saúde privado, Lago Sul, 2021

Resposta	Total	%
Total	27.524	100,0
Individual/Familiar	19.713	71,6
Coletivos (empresarial)	7.254	26,4
Coletivos (adesão)	556	2,0

Fonte: CODEPLAN/DIEPS/GEREPS/PDAD 2021

Tabela A.21: Planos de saúde privado com coparticipação e/ou franquia, Lago Sul, 2021

Resposta	Total	%
Total	27.134	100,0
Sim	16.627	61,3
Não	10.506	38,7

Fonte: CODEPLAN/DIEPS/GEREPS/PDAD 2021

Tabela A.22: Último serviço de saúde utilizado, Lago Sul, 2021

Resposta	Total	%
Total	30.048	100,0
Consultório particular/ clinica privada	16.638	55,4
Posto de Saúde / Unidade Básica de Saúde	8.615	28,7
Farmácia	2.128	7,1
Nunca precisou	972	3,2
Pronto-atendimento ou Urgência de hospital privado	540	1,8
Pronto-socorro ou emergência de hospital público	261	0,9
Ambulatório de hospital público	(***)	(***)
Ambulatório ou consultório de empresa ou sindicato	(***)	(***)
Centro de Especialidades / Policlínica do SUS	(***)	(***)
No domicílio, com médico particular	(***)	(***)
No domicílio, com profissional da equipe de saúde da família	(***)	(***)
Outro serviço	(***)	(***)
UPA (Unidade de Pronto Atendimento)	(***)	(***)

Fonte: CODEPLAN/DIEPS/GEREPS/PDAD 2021

(***): Estimativa não divulgada por insuficiência de amostra

Tabela A.23: Motivo de atendimento de saúde utilizado da última vez, Lago Sul, 2021

Resposta	Total	%
Total	29.024	100,0
Vacinação	12.078	41,6
Doença (dor, febre, diarreia etc.)	6.626	22,8
Prevenção	2.068	7,1
Exame complementar de diagnóstico (sangue, urina, imagem etc)	1.896	6,5
Outro	1.825	6,3
Continuação de tratamento de doença	1.394	4,8
Problema odontológico	1.174	4,0
Reabilitação (Fisioterapia, fonoaudiologia etc)	689	2,4
Acomp. com psicólogo, nutricionista ou outro profissional de saúde	609	2,1
Acidente, lesão ou fratura	531	1,8
Parto	(***)	(***)
Pré-natal	(***)	(***)
Solicitação de atestado de saúde	(***)	(***)

Fonte: CODEPLAN/DIEPS/GEREPS/PDAD 2021

(***): Estimativa não divulgada por insuficiência de amostra

Tabela A.24: Localidade do atendimento do último serviço de saúde utilizado, Lago Sul, 2021

Resposta	Total	%
Total	29.058	100,0
Plano Piloto	15.841	54,5
Lago Sul	8.489	29,2
Lago Norte	2.569	8,8
Paranoá	383	1,3
Águas Claras	(***)	(***)
Brazlândia	(***)	(***)
Candangolândia	(***)	(***)
Ceilândia	(***)	(***)
Cruzeiro	(***)	(***)
Fora do Distrito Federal	(***)	(***)
Gama	(***)	(***)
Guará	(***)	(***)
Itapoã	(***)	(***)
Jardim Botânico	(***)	(***)
Núcleo Bandeirante	(***)	(***)
Planaltina	(***)	(***)
Recanto das Emas	(***)	(***)
Riacho Fundo II	(***)	(***)
Samambaia	(***)	(***)
Santa Maria	(***)	(***)
São Sebastião	(***)	(***)
Sobradinho	(***)	(***)
Sobradinho II	(***)	(***)
Sudoeste/Octogonal	(***)	(***)
Taguatinga	(***)	(***)
Varjão	(***)	(***)

Fonte: CODEPLAN/DIEPS/GEREPS/PDAD 2021

(***): Estimativa não divulgada por insuficiência de amostra

Comunicação e informação

Tabela A.25: Posse de celular para uso pessoal, Lago Sul, 2021

Resposta	Total	%
Total	30.437	100,0
Sim	27.920	91,7
Não	2.517	8,3

Fonte: CODEPLAN/DIEPS/GEREPS/PDAD 2021

Tabela A.26: Posse de tablet para uso pessoal, Lago Sul, 2021

Resposta	Total	%
Total	30.437	100,0
Não	24.690	81,1
Sim	5.747	18,9

Fonte: CODEPLAN/DIEPS/GEREPS/PDAD 2021

Tabela A.27: Posse de linha pré-paga uso pessoal, Lago Sul, 2021

Resposta	Total	%
Total	30.354	100
Não	23.387	77
Sim	6.966	23

Fonte: CODEPLAN/DIEPS/GEREPS/PDAD 2021

Tabela A.28: Posse de linha pós-paga uso pessoal, Lago Sul, 2021

Resposta	Total	%
Total	30.354	100
Sim	22.769	75
Não	7.585	25

Fonte: CODEPLAN/DIEPS/GEREPS/PDAD 2021

Tabela A.29: Acesso à internet nos últimos três meses, Lago Sul, 2021

Resposta	Total	%
Total	30.273	100,0
Sim	28.081	92,8
Não	2.192	7,2

Fonte: CODEPLAN/DIEPS/GEREPS/PDAD 2021

Tabela A.30: Frequência de acesso à internet nos últimos três meses, Lago Sul, 2021

Resposta	Total	%
Total	28.074	100,0
Todos os dias	27.109	96,6
De 2 a 3 vezes por sem.	930	3,3
1 vez por mês	(***)	(***)
1 vez por sem.	(***)	(***)

Fonte: CODEPLAN/DIEPS/GEREPS/PDAD 2021
(***): Estimativa não divulgada por insuficiência de amostra

Tabela A.31: Acesso à internet por meio de microcomputador/laptop, Lago Sul, 2021

Resposta	Total	%
Total	28.029	100,0
Sim	22.825	81,4
Não	5.203	18,6

Fonte: CODEPLAN/DIEPS/GEREPS/PDAD 2021

Tabela A.32: Acesso à internet por meio de celular/tablet, Lago Sul, 2021

Resposta	Total	%
Total	28.040	100,0
Sim	27.686	98,7
Não	(***)	(***)

Fonte: CODEPLAN/DIEPS/GEREPS/PDAD 2021
(***): Estimativa não divulgada por insuficiência de amostra

Tabela A.33: Acesso à internet por outro meio, Lago Sul, 2021

Resposta	Total	%
Total	28.016	100,0
Sim	21.091	75,3
Não	6.925	24,7

Fonte: CODEPLAN/DIEPS/GEREPS/PDAD 2021

Tabela A.34: Acesso à internet por motivo de trabalhar (pessoas com 14 anos ou mais), Lago Sul, 2021

Resposta	Total	%
Total	26.454	100,0
Sim	15.093	57,1
Não	11.360	42,9

Fonte: CODEPLAN/DIEPS/GEREPS/PDAD 2021

Tabela A.35: Acesso à internet por motivo de educação/cursos, Lago Sul, 2021

Resposta	Total	%
Total	27.973	100,0
Sim	15.347	54,9
Não	12.626	45,1

Fonte: CODEPLAN/DIEPS/GEREPS/PDAD 2021

Tabela A.36: Acesso à internet por motivo de informações/notícias, Lago Sul, 2021

Resposta	Total	%
Total	27.985	100,0
Sim	24.712	88,3
Não	3.272	11,7

Fonte: CODEPLAN/DIEPS/GEREPS/PDAD 2021

Tabela A.37: Acesso à internet por motivo de criação/compartilhamento de conteúdo, Lago Sul, 2021

Resposta	Total	%
Total	27.985	100,0
Sim	20.652	73,8
Não	7.333	26,2

Fonte: CODEPLAN/DIEPS/GEREPS/PDAD 2021

Tabela A.38: Acesso à internet por motivo de multimídia (lazer e cultura), Lago Sul, 2021

Resposta	Total	%
Total	27.994	100,0
Sim	26.531	94,8
Não	1.463	5,2

Fonte: CODEPLAN/DIEPS/GEREPS/PDAD 2021

Tabela A.39: Acesso à internet por motivo de comunicação, Lago Sul, 2021

Resposta	Total	%
Total	27.985	100,0
Sim	26.605	95,1
Não	1.380	4,9

Fonte: CODEPLAN/DIEPS/GEREPS/PDAD 2021

Tabela A.40: Acesso à internet por motivo de transações financeiras/comerciais, Lago Sul, 2021

Resposta	Total	%
Total	27.949	100
Sim	20.393	73
Não	7.556	27

Fonte: CODEPLAN/DIEPS/GEREPS/PDAD 2021

Educação

Tabela A.41: Pessoas com cinco anos ou mais que sabem ler e escrever, Lago Sul, 2021

Resposta	Total	%
Total	29.286	100,0
Sim	28.920	98,8
Não	365	1,2

Fonte: CODEPLAN/DIEPS/GEREPS/PDAD 2021

Tabela A.42: Frequência escolar da população entre 4 e 24 anos, Lago Sul, 2021

Resposta	Total	%
Total	6.954	100,0
Sim, particular	5.782	83,1
Não, mas já frequentou	585	8,4
Sim, pública	575	8,3
Não, nunca frequentou	(***)	(***)

Fonte: CODEPLAN/DIEPS/GEREPS/PDAD 2021
(***): Estimativa não divulgada por insuficiência de amostra

Tabela A.43: Modalidade de ensino dos estudantes, Lago Sul, 2021

	Educação a Distância (EaD)		Híbrida ou semipresencial		Presencial	
Resposta	Total	%	Total	%	Total	%
Creche/Educ. Infantil	(***)	(***)	(***)	(***)	785	100,0
EJA/AJA	(***)	(***)	(***)	(***)	(***)	(***)
Ens. fundamental	(***)	(***)	(***)	(***)	2.531	96,0
Ens. médio	(***)	(***)	(***)	(***)	1.136	96,0
Ens. Superior/Pós-grad.	297	10,4	(***)	(***)	2.535	88,5

Fonte: CODEPLAN/DIEPS/GEREPS/PDAD 2021
(***): Estimativa não divulgada por insuficiência de amostra

Tabela A.44: Turno de estudo dos alunos, Lago Sul, 2021

	Integral		Matutino		Noturno		Vespertino	
Resposta	Total	%	Total	%	Total	%	Total	%
Creche/Educ. Infantil	(***)	(***)	(***)	(***)	(***)	(***)	(***)	(***)
EJA/AJA	(***)	(***)	(***)	(***)	(***)	(***)	(***)	(***)
Ens. fundamental	(***)	(***)	1.712	65,8	(***)	(***)	680	26,1
Ens. médio	(***)	(***)	604	51,4	(***)	(***)	429	36,5
Ens. Superior/Pós-grad.	(***)	(***)	861	33,6	1.200	46,9	291	11,4

Fonte: CODEPLAN/DIEPS/GEREPS/PDAD 2021
(***): Estimativa não divulgada por insuficiência de amostra

Tabela A.45: Frequência escolar, por faixa de idade, Lago Sul, , 2021

	Frequenta		Não frequenta	
Resposta	Total	%	Total	%
Até 3 anos	(***)	(***)	697	78,4
Entre 4 e 5 anos	462	94,7	(***)	(***)
Entre 6 e 14	2.506	100,0	(***)	(***)
Entre 15 e 17	1.220	99,2	(***)	(***)

Fonte: CODEPLAN/DIEPS/GEREPS/PDAD 2021
(***): Estimativa não divulgada por insuficiência de amostra

Tabela A.46: Região Administrativa/Município da unidade de estudo, Lago Sul, 2021

Resposta	Total	%
Total	7.486	100,0
Plano Piloto	3.807	50,9
Lago Sul	3.156	42,2
Gama	(***)	(***)
Guará	(***)	(***)
Jardim Botânico	(***)	(***)
Lago Norte	(***)	(***)
No domicílio	(***)	(***)
Park Way	(***)	(***)
Riacho Fundo	(***)	(***)
Riacho Fundo II	(***)	(***)
Sudoeste/ Octogonal	(***)	(***)
Taguatinga	(***)	(***)

Fonte: CODEPLAN/DIEPS/GEREPS/PDAD 2021
(***): Estimativa não divulgada por insuficiência de amostra

Tabela A.47: Principal meio de transporte da casa até a unidade de ensino, Lago Sul, 2021

Resposta	Total	%
Total	7.369	100,0
Automóvel	5.664	76,9
Transporte escolar privado	1.055	14,3
Ônibus	379	5,1
A pé	(***)	(***)
Bicicleta	(***)	(***)
Motocicleta	(***)	(***)
Transporte escolar público	(***)	(***)
Transporte privado (táxi, app etc.)	(***)	(***)

Fonte: CODEPLAN/DIEPS/GEREPS/PDAD 2021
(***): Estimativa não divulgada por insuficiência de amostra

Tabela A.48: Tempo de deslocamento utilizado até a unidade de ensino, Lago Sul, 2021

Resposta	Total	%
Total	7.469	100,0
Até 15 minutos	3.566	47,7
Mais de 15 até 30 minutos	3.066	41,0
Mais de 30 até 45 minutos	578	7,7
Mais de 1 hora até 1 hora e 15 minutos	(***)	(***)
Mais de 2 horas	(***)	(***)
Mais de 45 minutos até 1 hora	(***)	(***)
Não sabe	(***)	(***)

Fonte: CODEPLAN/DIEPS/GEREPS/PDAD 2021
(***): Estimativa não divulgada por insuficiência de amostra

Tabela A.49: Escolaridade das pessoas com 25 anos ou mais de idade, Lago Sul, 2021

Resposta	Total	%
Total	22.412	100,0
Superior completo	19.553	87,2
Médio completo	1.410	6,3
Superior incompleto	810	3,6
Fundamental incompleto	314	1,4
Sem escolaridade	(***)	(***)
Fundamental completo	(***)	(***)
Médio incompleto	(***)	(***)

Fonte: CODEPLAN/DIEPS/GEREPS/PDAD 2021
(***): Estimativa não divulgada por insuficiência de amostra

Trabalho e rendimento

Tabela A.50: Distribuição da população em idade ativa (PIA - 14 anos ou mais), segundo situação de atividade, Lago Sul, 2021

Resposta	Total	%
Total	26.810	100,0
Inativa	13.913	51,9
PEA	12.897	48,1

Fonte: CODEPLAN/DIEPS/GEREPS/PDAD 2021

Tabela A.51: Distribuição da população economicamente ativa (PEA - 14 anos ou mais), segundo situação de ocupação, Lago Sul, 2021

Resposta	Total	%
Total	12.897	100,0
Ocupada	12.730	98,7
Desocupada	(***)	(***)

Fonte: CODEPLAN/DIEPS/GEREPS/PDAD 2021
(***): Estimativa não divulgada por insuficiência de amostra

Tabela A.52: Distribuição da população economicamente ativa (PEA - 14 anos ou mais), segundo situação de ocupação, Lago Sul, 2021

Resposta	Total	%
Total	12.897	100,0
Ocupada	12.730	98,7
Desocupada	(***)	(***)

Fonte: CODEPLAN/DIEPS/GEREPS/PDAD 2021
(***): Estimativa não divulgada por insuficiência de amostra
Obs.: Exclusive pessoas sem classificação de situação ocupacional.

Tabela A.53: Pessoas entre 18 e 29 anos por situação de trabalho e estudo, Lago Sul, 2021

Resposta	Total	%
Total	4.574	100,0
Outro	3.882	84,9
Nem-nem	692	15,1

Fonte: CODEPLAN/DIEPS/GEREPS/PDAD 2021

Tabela A.54: Pessoas entre 18 e 29 anos por situação de trabalho, estudo e procura por trabalho nos últimos 30 dias, Lago Sul, 2021

Resposta	Total	%
Total	4.562	100,0
Outro	3.882	85,1
Nem-nem (não procurou trabalho)	657	14,4
Nem-nem (procurou trabalho)	(***)	(***)

Fonte: CODEPLAN/DIEPS/GEREPS/PDAD 2021
(***): Estimativa não divulgada por insuficiência de amostra

Tabela A.67: Rendimento bruto do trabalho principal em faixas de salário mínimo, Lago Sul, 2021

Faixas	Total	%
Até 1	249	3,3
Mais de 1 até 2	503	6,6
Mais de 2 até 5	968	12,8
Mais de 5 até 10	2.246	29,6
Mais de 10 até 20	2.745	36,2
Mais de 20	874	11,5

Fonte: CODEPLAN/DIEPS/GEREPS/PDAD 2021
Obs.1: Salários mínimos em R$ de Jul/2021, pelo IPCA/Brasília
Obs.2: Salário mínimo de R$ 1.100,00.

Tabela A.55: Região Administrativa de exercício do trabalho principal, Lago Sul, 2021

Resposta	Total	%
Total	12.708	100,0
Plano Piloto	7.538	59,3
Lago Sul	3.512	27,6
Taguatinga	439	3,5
Águas Claras	(***)	(***)
Águas Lindas de Goiás (Goiás)	(***)	(***)
Arniqueira	(***)	(***)
Candangolândia	(***)	(***)
Ceilândia	(***)	(***)
Cruzeiro	(***)	(***)
Fercal	(***)	(***)
Gama	(***)	(***)
Goiânia (Goiás)	(***)	(***)
Guará	(***)	(***)
Itapoã	(***)	(***)
Jardim Botânico	(***)	(***)
Lago Norte	(***)	(***)
Novo Gama (Goiás)	(***)	(***)
Núcleo Bandeirante	(***)	(***)
Outros municípios de Goiás	(***)	(***)
Outros locais	(***)	(***)
Paranoá	(***)	(***)
Park Way	(***)	(***)
Planaltina	(***)	(***)
Samambaia	(***)	(***)
Santa Maria	(***)	(***)
São Sebastião	(***)	(***)
SCIA	(***)	(***)
SIA	(***)	(***)
Sobradinho	(***)	(***)
Sudoeste/ Octogonal	(***)	(***)
Vários locais	(***)	(***)
Varjão	(***)	(***)
Vicente Pires	(***)	(***)

Fonte: CODEPLAN/DIEPS/GEREPS/PDAD 2021
(***): Estimativa não divulgada por insuficiência de amostra

Tabela A.56: Setor de atividade das pessoas ocupadas, Lago Sul, 2021

Resposta	Total	%
Total	12.630	100,0
Outros serviços	5.552	44,0
Educação, saúde e serviços sociais	2.496	19,8
Adm. Pública	2.359	18,7
Comércio	592	4,7
Serviços domésticos	583	4,6
Indústria	503	4,0
Construção	265	2,1
Agropecuária	244	1,9
Serviços por aplicativo	(***)	(***)

Fonte: CODEPLAN/DIEPS/GEREPS/PDAD 2021
(***): Estimativa não divulgada por insuficiência de amostra

Tabela A.57: Posição na ocupação do trabalho principal, Lago Sul, 2021

Resposta	Total	%
Total	12.444	100,0
Empregado no setor público	5.065	40,7
Conta própria ou autônomo	2.513	20,2
Empregado no setor privado (exceto doméstico)	1.985	15,9
Dono de negócio familiar	890	7,2
Empregador	718	5,8
Empregado doméstico	508	4,1
Forças Armadas/ Polícia Militar/ Bombeiros	410	3,3
Profissional liberal (autônomo univesitário)	163	1,3
Estágio remunerado	(***)	(***)
Sócio de cooperativa	(***)	(***)
Trabalhador sem remuneração salarial	(***)	(***)

Fonte: CODEPLAN/DIEPS/GEREPS/PDAD 2021
(***): Estimativa não divulgada por insuficiência de amostra

Tabela A.58: Área de atuação dos servidores/empregados públicos, Lago Sul, 2021

Resposta	Total	%
Total	5.420	100,0
Federal	2.987	55,1
Estadual/Distrital	2.134	39,4
Municipal	300	5,5

Fonte: CODEPLAN/DIEPS/GEREPS/PDAD 2021

Tabela A.59: Modalidade de contratação dos servidores/empregados públicos, Lago Sul, 2021

Resposta	Total	%
Total	5.415	100,0
Estatutário	4.338	80,1
Carteira de trabalho (CLT)	723	13,4
Contrato de trabalho	300	5,5
Emprego em comissão	(***)	(***)

Fonte: CODEPLAN/DIEPS/GEREPS/PDAD 2021
(***): Estimativa não divulgada por insuficiência de amostra

Tabela A.60: Sócios de cooperativas, autônomos, empregadores, donos de negócios familiares e profissionais liberais que eram Microempreendedores Individuais (MEI), Lago Sul, 2021

Resposta	Total	%
Total	4.269	100,0
Sim	2.141	50,1
Não	2.128	49,9

Fonte: CODEPLAN/DIEPS/GEREPS/PDAD 2021

Tabela A.61: Sócios de cooperativas, autônomos, empregadores, donos de negócios familiares e profissionais liberais que possuíam CNPJ, Lago Sul, 2021

Resposta	Total	%
Total	4.292	100,0
Sim	3.119	72,7
Não	1.173	27,3

Fonte: CODEPLAN/DIEPS/GEREPS/PDAD 2021

Tabela A.62: Meios de transporte para o trabalho principal, Lago Sul, 2021

Variável	Total		%	
	Sim	Não	Sim	Não
Ônibus	(***)	11.179	(***)	99,4
Automóvel	10.975	271	97,6	2,4
Transporte privado	(***)	11.158	(***)	99,2
Metrô	(***)	11.218	(***)	99,8
Motocicleta	(***)	11.191	(***)	99,5
Bicicleta	(***)	11.227	(***)	99,8
A pé	(***)	11.020	(***)	98,0

Fonte: CODEPLAN/DIEPS/GEREPS/PDAD 2021
(***): Estimativa não divulgada por insuficiência de amostra

Tabela A.63: Principal meio de transporte utilizado para o trabalho principal, Lago Sul, 2021

Resposta	Total	%
Total	11.246	100,0
Automóvel	10.966	97,5
A pé	(***)	(***)
Metrô	(***)	(***)
Ônibus	(***)	(***)
Transporte privado	(***)	(***)

Fonte: CODEPLAN/DIEPS/GEREPS/PDAD 2021
(***): Estimativa não divulgada por insuficiência de amostra

Tabela A.64: Tempo de deslocamento até o trabalho principal, Lago Sul, 2021

Resposta	Total	%
Total	11.246	100,0
Mais de 15 até 30 minutos	4.979	44,3
Até 15 minutos	4.058	36,1
Mais de 30 até 45 minutos	1.500	13,3
Mais de 45 minutos até 1 hora	514	4,6
Mais de 1 hora até 1 hora e 15 minutos	(***)	(***)
Mais de 1 hora e 15 minutos até 1 hora e meia	(***)	(***)
Mais de 1 hora e meia até 1 hora e 45 minutos	(***)	(***)
Mais de 2 horas	(***)	(***)
Não sabe	(***)	(***)

Fonte: CODEPLAN/DIEPS/GEREPS/PDAD 2021
(***): Estimativa não divulgada por insuficiência de amostra

Tabela A.65: Pessoas com carteira de trabalho assinada pelo atual empregador no trabalho principal, Lago Sul, 2021

Resposta	Total	%
Total	2.727	100,0
Sim	2.250	82,5
Não	477	17,5

Fonte: CODEPLAN/DIEPS/GEREPS/PDAD 2021

Tabela A.66: Pessoas que contribuem com a previdência pública, Lago Sul, 2021

Resposta	Total	%
Total	26.521	100,0
Não	13.615	51,3
Sim	12.905	48,7

Fonte: CODEPLAN/DIEPS/GEREPS/PDAD 2021

Tabela A.68: Rendimento bruto domiciliar por faixas de salário mínimo, Lago Sul, 2021

Faixas	N	%
Mais de 1 até 2	(***)	(***)
Mais de 2 até 5	(***)	(***)
Mais de 5 até 10	356	8,2
Mais de 10 até 20	1.154	26,8
Mais de 20	2.740	63,5

Fonte: CODEPLAN/DIEPS/GEREPS/PDAD 2021
(***): Estimativa não divulgada por insuficiência de amostra
Obs.1: Salários mínimos em R$ de Jul/2021, pelo IPCA/Brasília
Obs.2: Salário mínimo de R$ 1.000,00.

Tabelas relacionadas aos domicílios

Características do domicílio particular

Tabela A.69: Domicílios ocupados segundo a espécie, Lago Sul, 2021

Resposta	Total	%
Total	9.018	100,0
Permanente	8.867	98,3
Improvisado	151	1,7

Fonte: CODEPLAN/DIEPS/GEREPS/PDAD 2021

Tabela A.70: Domicílios ocupados segundo o tipo, Lago Sul, 2021

Resposta	Total	%
Total	9.018	100,0
Casas fora de condomínio	7.508	83,3
Casas em condomínio	1.381	15,3
Apartamentos	(***)	(***)
Cômodos	(***)	(***)

Fonte: CODEPLAN/DIEPS/GEREPS/PDAD 2021
(***): Estimativa não divulgada por insuficiência de amostra

Tabela A.71: Domicílios ocupados segundo a situação de ocupação, Lago Sul, 2021

Resposta	Total	%
Total	9.018	100,0
Próprio, já pago	8.317	92,2
Alugado	496	5,5
Cedido pelo empregador	(***)	(***)
Cedido por outro	(***)	(***)
Próprio, ainda pagando	(***)	(***)

Fonte: CODEPLAN/DIEPS/GEREPS/PDAD 2021
(***): Estimativa não divulgada por insuficiência de amostra

Tabela A.72: Domicílios ocupados segundo regularização do lote, Lago Sul,

Resposta	Total	%
Total	8.392	100,0
Sim	7.939	94,6
Não	453	5,4

Fonte: CODEPLAN/DIEPS/GEREPS/PDAD 2021

Tabela A.73: Material predominante nas paredes externas do domicílio, Lago Sul, 2021

Resposta	Total	%
Total	9.018	100,0
Alvenaria com revestimento	8.975	99,5
Alvenaria sem revestimento	(***)	(***)
Madeira para construção	(***)	(***)

Fonte: CODEPLAN/DIEPS/GEREPS/PDAD 2021
(***): Estimativa não divulgada por insuficiência de amostra

Tabela A.74: Material predominante no piso do domicílio, Lago Sul, 2021

Resposta	Total	%
Total	9.018	100,0
Cerâmica / Porcel. / madeira	8.921	98,9
Cimento alisado	(***)	(***)
Contra piso	(***)	(***)
Outros	(***)	(***)

Fonte: CODEPLAN/DIEPS/GEREPS/PDAD 2021
(***): Estimativa não divulgada por insuficiência de amostra

Tabela A.75: Material predominante na cobertura (telhado) do domicílio, Lago Sul, 2021

Resposta	Total	%
Total	9.018	100,0
Telha, exceto fibrocimento, com laje	7.141	79,2
Telha, exceto fibrocimento, sem laje	831	9,2
Outros	367	4,1
Fibrocimento com laje	356	3,9
Só laje	227	2,5
Fibrocimento sem laje	(***)	(***)

Fonte: CODEPLAN/DIEPS/GEREPS/PDAD 2021
(***): Estimativa não divulgada por insuficiência de amostra

Tabela A.76: Abastecimento de água no domicílio, Lago Sul, 2021

	Total		%	
Variável	Sim	Não	Sim	Não
Rede Geral (CAESB)	8.932	(***)	99,0	(***)
Poço/Cisterna	(***)	8.932	(***)	99,0
Poço artesiano	(***)	8.953	(***)	99,3
Captação de água da chuva	(***)	8.986	(***)	99,6
Gambiarra/gato	(***)	8.996	(***)	99,8
Caixa d'água	8.889	(***)	98,6	(***)

Fonte: CODEPLAN/DIEPS/GEREPS/PDAD 2021
(***): Estimativa não divulgada por insuficiência de amostra

Tabela A.77: Esgotamento sanitário do domicílio, Lago Sul, 2021

	Total		%	
Variável	Sim	Não	Sim	Não
Rede Geral (CAESB)	8.414	604	93,3	6,7
Fossa séptica	507	8.511	5,6	94,4
Fossa rudimentar	151	8.867	1,7	98,3
Esgotamento a céu aberto	(***)	9.007	(***)	99,9

Fonte: CODEPLAN/DIEPS/GEREPS/PDAD 2021
(***): Estimativa não divulgada por insuficiência de amostra

Tabela A.78: Abastecimento de energia elétrica no domicílio, Lago Sul, 2021

	Total		%	
Variável	Sim	Não	Sim	Não
Rede Geral (CAESB)	9.018	(***)	100,0	(***)
Próprio (gerador a combustível)	(***)	9.018	(***)	100,0
Próprio (gerador solar)	280	8.738	3,1	96,9
Outras fontes renováveis	(***)	8.986	(***)	99,6
Gambiarra/gato	(***)	9.018	(***)	100,0

Fonte: CODEPLAN/DIEPS/GEREPS/PDAD 2021
(***): Estimativa não divulgada por insuficiência de amostra

Tabela A.79: Recolhimento do lixo no domicílio, Lago Sul, 2021

	Total		%	
Variável	Sim	Não	Sim	Não
Coleta seletiva direta	7.443	1.543	82,8	17,2
Coleta convencional direta (não seletiva)	8.878	(***)	98,6	(***)
Coleta indireta	7.583	1.348	84,9	15,1
Jogado em local impróprio	(***)	8.630	(***)	99,6
Outro (enterrado ou queimado)	(***)	8.587	(***)	99,0
Separação do lixo	8.457	550	93,9	6,1

Fonte: CODEPLAN/DIEPS/GEREPS/PDAD 2021
(***): Estimativa não divulgada por insuficiência de amostra

Tabela A.80: Infraestrutura urbana na rua de acesso dos domicílios, Lago Sul, 2021

	Total		%	
Variável	Sim	Não	Sim	Não
Rua asfaltada/pavimentada	8.986	(***)	99,8	(***)
Rua com calçada	8.921	(***)	99,0	(***)
Rua com iluminação	8.975	(***)	99,5	(***)
Drenagem de água da chuva	8.425	518	94,2	5,8

Fonte: CODEPLAN/DIEPS/GEREPS/PDAD 2021
(***): Estimativa não divulgada por insuficiência de amostra

Tabela A.81: Qualidade da calçada, Lago Sul, 2021

Resposta	Total	%
Total	8.899	100,0
Boa	5.447	61,2
Ótima	2.492	28,0
Regular	766	8,6
Péssima	(***)	(***)
Ruim	(***)	(***)

Fonte: CODEPLAN/DIEPS/GEREPS/PDAD 2021
(***): Estimativa não divulgada por insuficiência de amostra

Tabela A.82: Problemas nas cercanias do domicílio, Lago Sul, 2021

	Total		%	
Variável	Sim	Não	Sim	Não
Erosão	(***)	8.953	(***)	99,3
Área em declive	(***)	8.986	(***)	99,6
Entulho	(***)	8.953	(***)	99,3
Esgoto a céu aberto	(***)	8.942	(***)	99,2
Ruas Alagadas	453	8.565	5,0	95,0
Ruas esburacadas	399	8.619	4,4	95,6

Fonte: CODEPLAN/DIEPS/GEREPS/PDAD 2021
(***): Estimativa não divulgada por insuficiência de amostra

Tabela A.83: Infraestrutura urbana e equipamentos públicos nas cercanias do domicílio, Lago Sul, 2021

	Total		%	
Variável	Sim	Não	Sim	Não
Ruas arborizadas	7.950	1.046	88,4	11,6
Jardins ou parques	7.119	1.791	79,9	20,1
Praça	6.170	2.740	69,2	30,8
Espaço cultural	5.253	3.538	59,8	40,2
Academia comunitária/PEC	6.418	2.449	72,4	27,6
Quadras esportivas	5.836	3.031	65,8	34,2
Ciclovia/ciclofaixa	6.699	2.244	74,9	25,1
Travessia sinalizada para pedestres	6.710	2.276	74,7	25,3
Ponto de ônibus	7.853	1.154	87,2	12,8

Fonte: CODEPLAN/DIEPS/GEREPS/PDAD 2021

Tabela A.84: Segurança nas proximidades do domicílio, Lago Sul, 2021

	Total		%	
Variável	Sim	Não	Sim	Não
Policiamento militar regular	7.432	1.532	82,9	17,1
Serviço/equipamento particular de segurança	7.972	1.025	88,6	11,4
Serviço/equipamento coletivo de segurança	6.839	2.125	76,3	23,7

Fonte: CODEPLAN/DIEPS/GEREPS/PDAD 2021

Serviços domiciliares inventário de bens duráveis

Tabela A.85: Contratação de serviços pelos domicílios, Lago Sul, 2021

	Total		%	
Variável	Sim	Não	Sim	Não
TV por assinatura	6.839	2.157	76,0	24,0
Assinatura de revistas/jornais impressos	2.017	7.001	22,4	77,6
Assinatura de serviços on-line	8.036	928	89,7	10,3

Fonte: CODEPLAN/DIEPS/GEREPS/PDAD 2021

Tabela A.86: Acesso à internet no domicílio, Lago Sul, 2021

Resposta	Total	%
Total	9.018	100,0
Próprio	9.007	99,9
Compartilhado	(***)	(***)

Fonte: CODEPLAN/DIEPS/GEREPS/PDAD 2021
(***): Estimativa não divulgada por insuficiência de amostra

Tabela A.87: Tipo de acesso à internet no domicílio, Lago Sul, 2021

	Total		%	
Variável	Sim	Não	Sim	Não
Banda larga fixa	8.996	(***)	99,8	(***)
Banda larga móvel	9.018	(***)	100,0	(***)

Fonte: CODEPLAN/DIEPS/GEREPS/PDAD 2021
(***): Estimativa não divulgada por insuficiência de amostra

Tabela A.88: Posse de veículos no domicílio, Lago Sul, 2021

	Total		%	
Variável	Sim	Não	Sim	Não
Automóvel	8.964	(***)	99,4	(***)
Motocicleta	1.219	7.777	13,5	86,5
Bicicleta	4.789	4.218	53,2	46,8

Fonte: CODEPLAN/DIEPS/GEREPS/PDAD 2021

Tabela A.89: Inventário de bens duráveis dos domicílios, Lago Sul, 2021

	Total		%	
Variável	Sim	Não	Sim	Não
Fogão	9.018	(***)	100,0	(***)
Microondas	8.824	194	97,8	2,2
Geladeira de uma porta	3.549	5.469	39,4	60,6
Geladeira de duas ou mais portas	7.616	1.402	84,4	15,6
Freezer	5.901	3.117	65,4	34,6
Máquina de lavar roupas	5.868	3.150	65,1	34,9
Máquina de lavar e secar roupas	5.394	3.624	59,8	40,2
Secadora de roupas	2.869	6.149	31,8	68,2
Máquina de lavar louça	5.350	3.668	59,3	40,7
Televisor tubo	248	8.770	2,8	97,2
Televisor tela fina/plana	8.921	(***)	98,9	(***)
DVD/BLU-RAY	863	8.155	9,6	90,4
Microcomputadore/Desktop	5.070	3.948	56,2	43,8
Notebook/Laptop	8.015	1.003	88,9	11,1
Ar-condicionado	7.993	1.025	88,6	11,4
Circulador e/ou ventiladores de ar	6.656	2.362	73,8	26,2
Telefones fixos	6.774	2.244	75,1	24,9
Placas de aquecedor solar	4.239	4.779	47,0	53,0

Fonte: CODEPLAN/DIEPS/GEREPS/PDAD 2021

(***): Estimativa não divulgada por insuficiência de amostra

Tabela A.90: Utilização de serviços domésticos nos domicílios, Lago Sul, 2021

	Total		%	
Variável	Sim	Não	Sim	Não
Mensalista	4.207	4.800	46,7	53,3
Diarista	2.859	6.116	31,9	68,1

Fonte: CODEPLAN/DIEPS/GEREPS/PDAD 2021

Tabela A.91: Frequência mensal da utilização de serviço doméstico do tipo diarista, Lago Sul, 2021

Resposta	Total	%
Total	1.791	100,0
Quatro vezes por mês	917	51,2
Duas vezes por mês	475	26,5
Três vezes por mês	345	19,3
Uma vez por mês	(***)	(***)

Fonte: CODEPLAN/DIEPS/GEREPS/PDAD 2021
(***): Estimativa não divulgada por insuficiência de amostra

Localidades predominantes de compras

Tabela A.92: Locais predominantes de compra de artigos de alimentação, higiene e limpeza, Lago Sul, 2021

Resposta	Total	%
Total	9.018	100,0
Lago Sul	7.109	78,8
Plano Piloto	938	10,4
SIA	280	3,1
Águas Claras	(***)	(***)
Gama	(***)	(***)
Guará	(***)	(***)
Jardim Botânico	(***)	(***)
Lago Norte	(***)	(***)
Não comprou	(***)	(***)
Núcleo Bandeirante	(***)	(***)
Paranoá	(***)	(***)
Pela internet	(***)	(***)
Planaltina	(***)	(***)
Riacho Fundo II	(***)	(***)
Samambaia	(***)	(***)
Santa Maria	(***)	(***)
São Sebastião	(***)	(***)
Scia e Estrutural	(***)	(***)
Taguatinga	(***)	(***)
Vários locais	(***)	(***)

Fonte: CODEPLAN/DIEPS/GEREPS/PDAD 2021
(***): Estimativa não divulgada por insuficiência de amostra

Tabela A.93: Locais predominantes de compra de artigos de eletrodomésticos, Lago Sul, 2021

Resposta	Total	%
Total	8.921	100,0
Não comprou	3.387	38,0
Lago Sul	2.341	26,2
Pela internet	1.359	15,2
Plano Piloto	1.359	15,2
Taguatinga	173	1,9
Gama	(***)	(***)
Lago Norte	(***)	(***)
Núcleo Bandeirante	(***)	(***)
Paranoá	(***)	(***)
Planaltina	(***)	(***)
Riacho Fundo	(***)	(***)
Samambaia	(***)	(***)
Santa Maria	(***)	(***)
Scia e Estrutural	(***)	(***)
SIA	(***)	(***)
Sudoeste e Octogonal	(***)	(***)
Vários locais	(***)	(***)

Fonte: CODEPLAN/DIEPS/GEREPS/PDAD 2021
(***): Estimativa não divulgada por insuficiência de amostra

Tabela A.94: Locais predominantes de compra de material de construção/manutenção, Lago Sul, 2021

Resposta	Total	%
Total	8.932	100,0
Não comprou	4.789	53,6
Lago Sul	2.395	26,8
Plano Piloto	734	8,2
SIA	485	5,4
Gama	(***)	(***)
Guará	(***)	(***)
Itapoã	(***)	(***)
Jardim Botânico	(***)	(***)
Lago Norte	(***)	(***)
Núcleo Bandeirante	(***)	(***)
Paranoá	(***)	(***)
Planaltina	(***)	(***)
Riacho Fundo	(***)	(***)
Santa Maria	(***)	(***)
São Sebastião	(***)	(***)
Scia e Estrutural	(***)	(***)
Taguatinga	(***)	(***)

Fonte: CODEPLAN/DIEPS/GEREPS/PDAD 2021
(***): Estimativa não divulgada por insuficiência de amostra

Tabela A.95: Locais predominantes de compra de material de serviços em geral (exceto limpeza doméstica), Lago Sul, 2021

Resposta	Total	%
Total	8.867	100,0
Lago Sul	4.034	45,5
Não comprou	3.819	43,1
Plano Piloto	626	7,1
Águas Claras	(***)	(***)
Gama	(***)	(***)
Jardim Botânico	(***)	(***)
Lago Norte	(***)	(***)
Núcleo Bandeirante	(***)	(***)
Outros locais	(***)	(***)
Paranoá	(***)	(***)
Pela internet	(***)	(***)
Planaltina	(***)	(***)
Riacho Fundo	(***)	(***)
Santa Maria	(***)	(***)
Scia e Estrutural	(***)	(***)
SIA	(***)	(***)
Taguatinga	(***)	(***)

Fonte: CODEPLAN/DIEPS/GEREPS/PDAD 2021
(***): Estimativa não divulgada por insuficiência de amostra

Animais de estimação

Tabela A.96: Existência de gatos, cachorros, aves, peixes ou outros animais domésticos no domicílio, Lago Sul, 2021

	Total		%	
Variável	Sim	Não	Sim	Não
Gato	906	8.112	10,0	90,0
Cachorro	5.944	3.074	65,9	34,1
Ave	701	8.317	7,8	92,2
Peixe	690	8.328	7,7	92,3
Outro	345	8.673	3,8	96,2

Fonte: CODEPLAN/DIEPS/GEREPS/PDAD 2021

Segurança alimentar

Tabela A.97: Distribuição dos domicílios por situação de segurança alimentar nos últimos 3 meses, Lago Sul, 2021

Resposta	Total	%
Total	8.910	100,0
Segurança	8.738	98,1
Insegurança leve	173	1,9

Fonte: CODEPLAN/DIEPS/GEREPS/PDAD 2021

Companhia de Planejamento do Distrito Federal – Codeplan
Setor de Administração Municipal
SAM, Bloco H, Setores Complementares
Ed. Sede Codeplan

CEP: 70620-080 - Brasília-DF
Fone: (0xx61) 3342-2222
<www.codeplan.df.gov.br>
codeplan@codeplan.df.gov.br

codeplan
COMPANHIA DE PLANEJAMENTO DO DISTRITO FEDERAL